# Samstag 14.03.2026

Veröffentlicht am 13.03.2026 um 17:00

## Vormittag

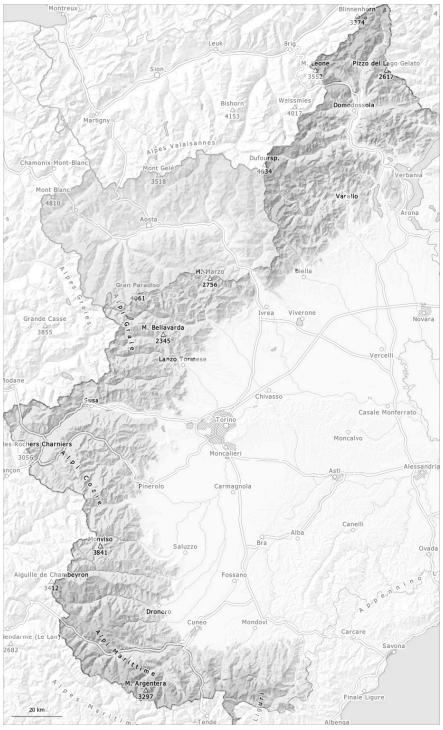


## Nachmittag

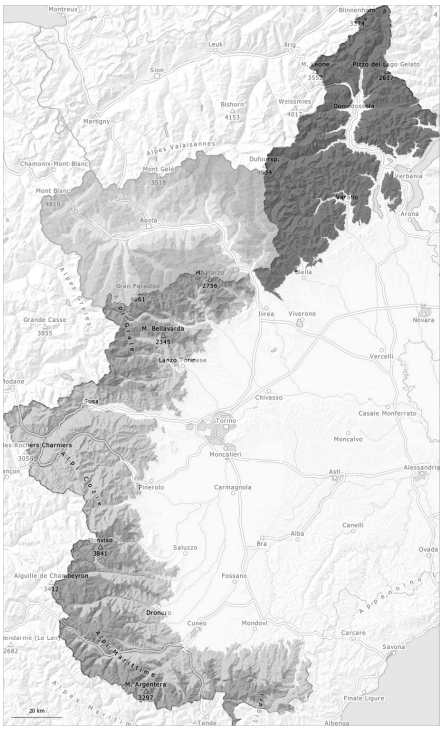


| 1 | 2 | 3 | 4 | 5 |
|---|---|---|---|---|
| gering | mäßig | erheblich | groß | sehr groß |

## Gefahrenstufe 4 - Groß

**AM:**

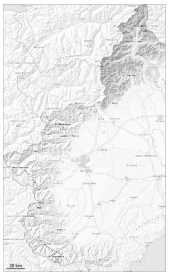

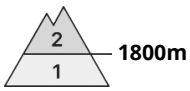


**Tendenz: Lawinengefahr steigt**
am Sonntag, den 15.03.2026

**PM:**

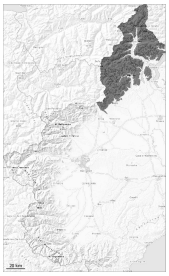

**Tendenz: Lawinengefahr steigt**
am Sonntag, den 15.03.2026

### Mit der Intensivierung der Niederschläge steigt die Lawinengefahr am Nachmittag rasch an auf die Stufe 4, "groß".

Es fällt viel Schnee. Mit der Intensivierung der Schneefälle nehmen Anzahl und Größe der Gefahrenstellen ab dem Mittag zu. Am Nachmittag wird verbreitet die Gefahrenstufe 4, "groß" erreicht.
An allen Expositionen sind mit Neuschnee und starkem Wind vermehrt große Lawinen zu erwarten. Lawinen können bis in Tallagen vorstoßen und exponierte Verkehrswege stellenweise gefährden.

Von Skitouren, Freeriden und Schneeschuhwanderungen wird dringend abgeraten.

## Schneedecke

**Gefahrenmuster** gm.6: lockerer schnee und wind

Die Altschneedecke ist gut verfestigt, mit einer oft tragfähigen Schmelzharschkruste an der Oberfläche. Bis Sonntag fällt verbreitet viel Schnee. Der Neuschnee verbindet sich nur langsam mit dem Altschnee. Der Südwind verfrachtet den Neuschnee intensiv.

Mittlere und hohe Lagen: In der Altschneedecke sind besonders an Schattenhängen einzelne Schwachschichten vorhanden.

## Tendenz

Bis Sonntag fällt viel Schnee.
Der Neuschnee verbindet sich an allen Expositionen nur langsam mit dem Altschnee.

## Gefahrenstufe 3 - Erheblich

**AM:**

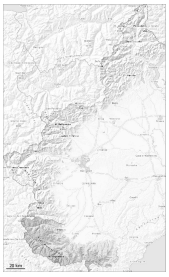

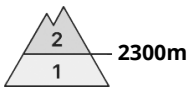


**Tendenz: Lawinengefahr steigt**
am Sonntag, den 15.03.2026

Triebschnee

**2300m**

**PM:**

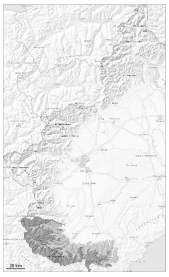

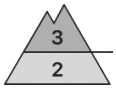


**Tendenz: Lawinengefahr steigt**
am Sonntag, den 15.03.2026

Neuschnee

**1500m**

Neuschnee

**1500m**

### Allmählicher Anstieg der Lawinengefahr mit Neuschnee und starkem Wind.

In den letzten Tagen fielen oberhalb von rund 1800 m bis zu 20 cm Schnee, lokal auch mehr. Ab dem Mittag fällt Schnee oberhalb von rund 1300 m. Der Wind bläst verbreitet stark.
Mit Neuschnee und starkem Wind aus südlichen Richtungen entstehen am Nachmittag vor allem in mittleren und hohen Lagen störanfällige Triebschneeansammlungen. An allen Expositionen und oberhalb von rund 1500 m sind mit der Intensivierung der Schneefälle mittlere und vereinzelt große Lawinen zu erwarten.

Skitouren, Variantenabfahrten und Schneeschuhwanderungen erfordern große Vorsicht und Zurückhaltung.

## Schneedecke

**Gefahrenmuster** gm.6: lockerer schnee und wind

Am Dienstag fielen oberhalb von rund 1600 m verbreitet 15 bis 20 cm Schnee, lokal bis zu 30 cm. Er ist stellenweise schlecht mit dem Altschnee verbunden.
Bis Sonntag fällt verbreitet Schnee oberhalb von rund 1000 m. Der Neuschnee verbindet sich nur langsam mit dem Altschnee.
Der Südwind verfrachtet den Neuschnee intensiv.

Verbreitet liegt noch viel Schnee.

## Tendenz

Anstieg der Lawinengefahr mit dem Schneefall.

## Gefahrenstufe 3 - Erheblich

**AM:**

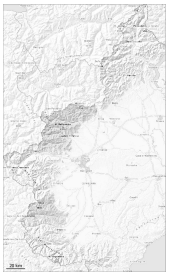

**Tendenz: Lawinengefahr steigt**
am Sonntag, den 15.03.2026

**PM:**

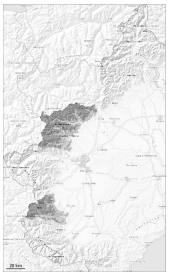

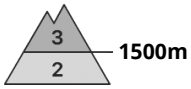


**Tendenz: Lawinengefahr steigt**
am Sonntag, den 15.03.2026

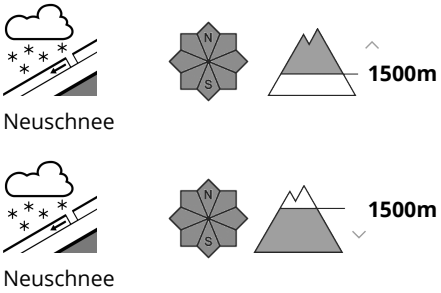


### Allmählicher Anstieg der Lawinengefahr mit Neuschnee und starkem Wind.

Ab dem Mittag fällt Schnee oberhalb von rund 1300 m. Der Wind bläst verbreitet stark.
Mit Neuschnee und starkem Wind aus südlichen Richtungen entstehen am Nachmittag vor allem in mittleren und hohen Lagen störanfällige Triebschneeansammlungen. An allen Expositionen und oberhalb von rund 1500 m sind mit der Intensivierung der Schneefälle mittlere und vereinzelt große Lawinen zu erwarten.

Skitouren, Variantenabfahrten und Schneeschuhwanderungen erfordern große Vorsicht und Zurückhaltung.

## Schneedecke

**Gefahrenmuster** gm.6: lockerer schnee und wind

Die Altschneedecke ist gut verfestigt, mit einer aus lockerem Schnee bestehenden Oberfläche, die auf einer oft tragfähigen Schmelzharschkruste liegt.
Bis Sonntag fällt verbreitet Schnee oberhalb von rund 1200 m. Der Neuschnee verbindet sich nur langsam mit dem Altschnee.
Der Südwind verfrachtet den Neuschnee intensiv.

Mittlere und hohe Lagen: In der Altschneedecke sind besonders an Schattenhängen einzelne Schwachschichten vorhanden.
Vor allem in Gipfellagen liegt wenig Schnee.

## Tendenz

Anstieg der Lawinengefahr mit dem Schneefall.

## Gefahrenstufe 2 - Mäßig

**AM:**

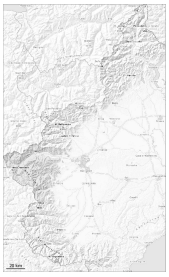

1

**Tendenz: Lawinengefahr steigt**
am Sonntag, den 15.03.2026

**PM:**

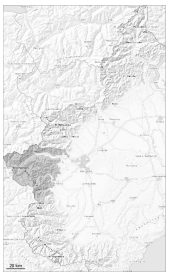

2

**Tendenz: Lawinengefahr steigt**
am Sonntag, den 15.03.2026

Neuschnee

N S

### Allmählicher Anstieg der Lawinengefahr mit Neuschnee und starkem Wind.

Ab dem Mittag fällt Schnee oberhalb von rund 1300 m. Der Wind bläst verbreitet stark.
Mit Neuschnee und starkem Wind aus südlichen Richtungen entstehen am Nachmittag vor allem in mittleren und hohen Lagen störanfällige Triebschneeansammlungen. An allen Expositionen sind mit der Intensivierung der Schneefälle kleine und mittlere Lawinen zu erwarten.
Der Neuschnee überlagert eine recht günstige Altschneedecke.

Schwachschichten im Altschnee können besonders in der Höhe vereinzelt und meist mit großer Zusatzbelastung ausgelöst werden. Dies vor allem an extrem steilen Schattenhängen oberhalb von rund 2700 m.

### Schneedecke

**Gefahrenmuster** gm.6: lockerer schnee und wind

Die Altschneedecke ist gut verfestigt, mit einer aus lockerem Schnee bestehenden Oberfläche, die auf einer oft tragfähigen Schmelzharschkruste liegt.
Bis Sonntag fällt verbreitet Schnee oberhalb von rund 1200 m. Der Neuschnee verbindet sich nur langsam mit dem Altschnee.
Der Südwind verfrachtet den Neuschnee intensiv.

Mittlere und hohe Lagen: In der Altschneedecke sind besonders an Schattenhängen einzelne Schwachschichten vorhanden.
Vor allem in Gipfellagen liegt wenig Schnee.

### Tendenz

> Anstieg der Lawinengefahr mit dem Schneefall.