ICGC Institut Cartogràfic i Geològic de Catalunya

Servei Meteorològic de Catalunya meteo.cat

Boletín de peligro de aludes para el Pirineo de Catalunya
Del 13/03/2026 al 14/03/2026

(Válido fuera pistas de esquí y zonas no controladas)

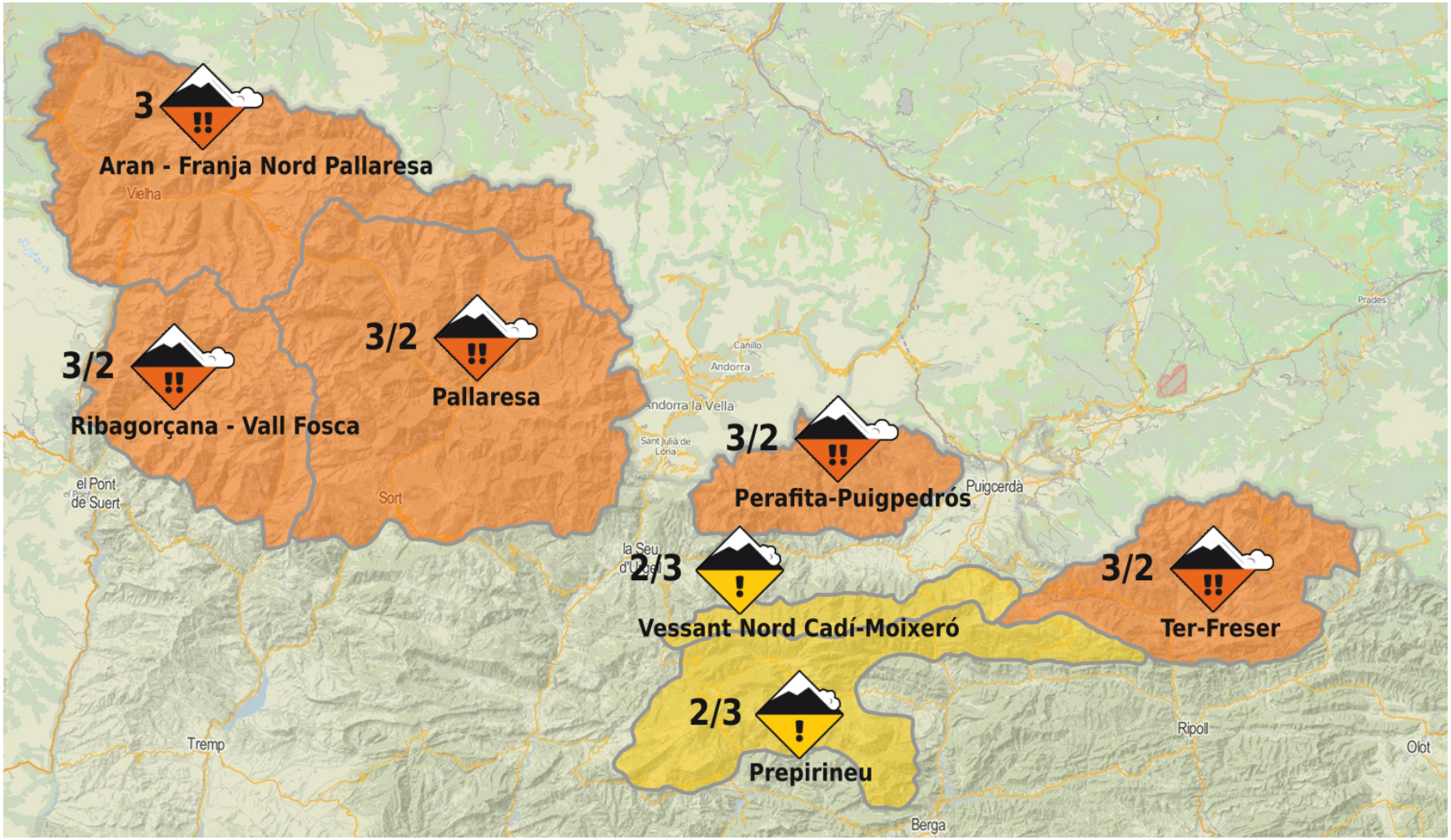

5 MUY FUERTE	4 FUERTE	3 NOTABLE	2 LIMITADO	1 DÉBIL

ICGC Institut Cartogràfic i Geològic de Catalunya

meteo.cat Servei Meteorològic de Catalunya

Boletín de peligro de aludes Aran - Franja Nord Pallaresa Del 13/03/2026 al 14/03/2026

(Válido fuera pistas de esquí y zonas no controladas)

Notable (3)

Situación primaria

Nieve venteada

Distribución

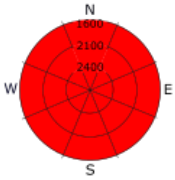

Tamaño

Origen

Tendencia

Situación secundaria

Capas débiles persistentes

Distribución

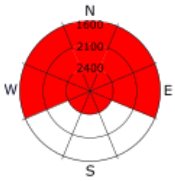

Tamaño

Origen

Tendencia

Estado del manto nivoso

El manto nivoso existente es susceptible de ser removido en cotas altas por el viento. El viernes soplará viento de SW que moverá nieve de cimas y crestes y formará nuevas placas en orientaciones NW, N y NE. Las nevadas previstas el sábado (30-40 cm de nieve fría), con progresivo incremento de viento de NW y N, formará nuevas placas en orientaciones E, S y W. Con esta previsión, las placas se encontrarán en todas las orientaciones por encima de los 2100 m. Estas pueden caer incluso de forma natural. Serán de tamaño suficiente para enterrar a una persona. Por debajo de los 2100 m pueden caer purgas de nieve reciente en pendientes empinadas sin capacidad para enterrarnos. Hay varias capas débiles persistentes enterradas: escarcha o facetas sobre la costra marrón. Estas capas pueden fracturar fácilmente a nuestro paso dando lugar a aludes de tamaño suficiente para enterrar a una persona o incluso a un grupo de personas a medida que se incremente el grosor de placa con las nevadas.

Distribución del manto nivoso

Hay nieve por encima de unos 1.400-1-500 ma umbrías y 1.700 ma solanas. Los espesores a unos 2.200 m son superiores a los normales en la Franja Norte de la Pallaresa y en la mitad sur del Aran donde rondan los 180-220 cm. En la mitad norte de Arán hay unos 120-140 cm de grosor total.

Tendencia para las próximas 48-72h

Las placas de viento se mantendrán frágiles y pueden seguir aumentando su grosor. El frío mantendrá activas las capas débiles. Evolución del peligro: ESTACIONARIO o en PROGRESIVO AUMENTO

El próximo boletín será emitido el día 2026-03-14

5 MUY FUERTE	4 FUERTE	3 NOTABLE	2 LIMITADO	1 DÉBIL

EAWS EUROPEAN AVALANCHE WARNING SERVICES

ICGC Institut Cartogràfic i Geològic de Catalunya

meteo.cat Servei Meteorològic de Catalunya

Boletín de peligro de aludes Ribagorçana - Vall Fosca Del 13/03/2026 al 14/03/2026

(Válido fuera pistas de esquí y zonas no controladas)

NOTABLE (3) el sábado
LIMITADO (2) el viernes

Situación primaria

Nieve venteada

Distribución

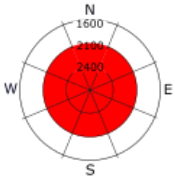

Tamaño

Origen

Tendencia

Situación secundaria

Capas débiles persistentes

Distribución

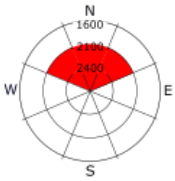

Tamaño

Origen

Tendencia

Estado del manto nivoso

El manto nivoso existente es susceptible de ser removido por el viento. El viernes se prevé la formación de placas de viento a causa del viento de componente SW. El sábado con las nevadas previstas con el giro de viento hacia NW y N se formarán nuevas placas de viento. El extremo norte de este sector, más influenciado por las nevadas, es donde las placas serán más gruesas. Con esta meteorologia prevista, los aludes de placa de viento se encontrarán pues en todas las orientaciones por encima de los 2100 m. De cara al sábado serían más gruesas bajo collados y crestas orientadas a S y E. Tanto el viernes como el sábado las placas se presentarán frágiles, pueden caer de forma espontánea y tener tamaño suficiente para enterrar a una persona. La nieve granulada existente, que se concentra en umbrías, quedará enterrada por las placas y puede dar paso a caídas naturales de placas, con capacidad de enterrar a una persona, debido a esta capa débil.

Distribución del manto nivoso

Hay nieve en el suelo a 1.600 m en terreno umbrío, y por encima de unos 1.800 m en laderas soleadas. El manto es esquiable por encima de unos 1.800-1.900 ma umbrías. Los grosores alcanzan los 100-130 cm a unos 2.200 m. Estos valores son superiores a los normales para la época.

Tendencia para las próximas 48-72h

El fuerte viento de norte previsto el domingo barrerá la nieve y concentrará el peligro solo en terreno acotado y específico. Peligro EN PROGRESIVO DESCENSO

El próximo boletín será emitido el día 2026-03-14

5 MUY FUERTE	4 FUERTE	3 NOTABLE	2 LIMITADO	1 DÉBIL

EAWS EUROPEAN AVALANCHE WARNING SERVICES

ICGC Institut Cartogràfic i Geològic de Catalunya

Servei Meteorològic de Catalunya

Boletín de peligro de aludes Pallaresa
Del 13/03/2026 al 14/03/2026

(Válido fuera pistas de esquí y zonas no controladas)

NOTABLE (3) el sábado
LIMITADO (2) el viernes

Situación primaria

Nieve venteada

Distribución

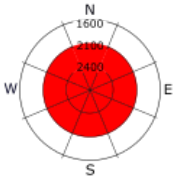

Tamaño

Origen

Tendencia

Estado del manto nivoso

El manto nivoso existente es susceptible de ser removido por el viento. El viernes se prevé la formación de placas de viento a causa del viento de componente SW. El sábado con las nevadas previstas con el giro de viento hacia NW y N se formarán nuevas placas de viento. El extremo norte de este sector, más influenciado por las nevadas, es donde las placas serán más gruesas. Con esta meteorologia prevista, los aludes de placa de viento se encontrarán pues en todas las orientaciones por encima de los 2100 m. De cara al sábado serían más gruesas bajo collados y crestas orientadas a S y E. Tanto el viernes como el sábado las placas se presentarán frágiles, pueden caer de forma espontánea y tener tamaño suficiente para enterrar a una persona.

Distribución del manto nivoso

Hay nieve en el suelo a 1.600 m en N, ya 1.800-1.900 m en S. El manto es esquiable por encima de unos 1.800-1.900 m en umbrías. Los espesores alcanzan los 110-150 cm en cotas medias, variable según los efectos del viento.

Tendencia para las próximas 48-72h

El fuerte viento de norte previsto el domingo barrerá la nieve y concentrará el peligro solo en terreno acotado y específico. Peligro EN PROGRESIVO DESCENSO

El próximo boletín será emitido el día 2026-03-14

5 MUY FUERTE	4 FUERTE	3 NOTABLE	2 LIMITADO	1 DÉBIL

EAWS EUROPEAN AVALANCHE WARNING SERVICES

ICGC Institut Cartogràfic i Geològic de Catalunya

Servei Meteorològic de Catalunya

Boletín de peligro de aludes Perafita-Puigpedrós Del 13/03/2026 al 14/03/2026

(Válido fuera pistas de esquí y zonas no controladas)

NOTABLE (3) el sábado
LIMITADO (2) el viernes

Situación primaria

Nieve venteada

Distribución

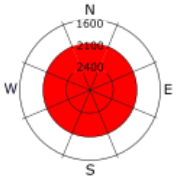

Tamaño

Origen

Tendencia

Estado del manto nivoso

El manto nivoso existente es susceptible de ser removido por el viento. El viernes se prevé la formación de placas de viento a causa del viento de componente SW. Por el sábado, con las nevadas previstas con el giro de viento hacia NW y N se formarán nuevas placas de viento. El extremo norte de este sector, más influenciado por las nevadas, es donde las placas serán más gruesas. Con esta meteorología prevista, los aludes de placa de viento se encontrarán pues en todas las orientaciones por encima de los 2100 m. De cara al sábado serían más gruesas bajo collados y crestas orientadas a S y E. Tanto el viernes como el sábado las placas se presentarán frágiles, pueden caer de forma espontánea y tener tamaño suficiente para enterrar a una persona.

Distribución del manto nivoso

Hay nieve en el suelo por encima de unos 1.700 m en N y 1.900 en S. Los espesores, aunque irregulares, rondan los 80-100 cm en cotas medias. Son grosores por encima de los habituales para la época.

Tendencia para las próximas 48-72h

El fuerte viento de norte previsto el domingo barrerá la nieve y concentrará el peligro solo en terreno acotado y específico. Peligro EN PROGRESIVO DESCENSO

El próximo boletín será emitido el día 2026-03-14

5 MUY FUERTE	4 FUERTE	3 NOTABLE	2 LIMITADO	1 DÉBIL

EAWS EUROPEAN AVALANCHE WARNING SERVICES

ICGC Institut Cartogràfic i Geològic de Catalunya

Servei Meteorològic de Catalunya

Boletín de peligro de aludes Vessant Nord Cadí-Moixeró Del 13/03/2026 al 14/03/2026

(Válido fuera pistas de esquí y zonas no controladas)

LIMITADO (2) pasando a NOTABLE (3) en cotas altas el sábado

Situación primaria

Nieve venteada

Distribución

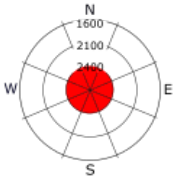

Tamaño

Origen

Tendencia

Situación secundaria

Capas débiles persistentes

Distribución

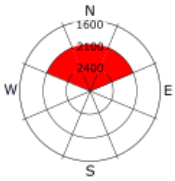

Tamaño

Origen

Tendencia

Estado del manto nivoso

El manto nivoso es susceptible de ser removido por el viento, especialmente de las cotas más altas donde no se ha encostrado en superficie. En las umbrías, se conserva la nieve granulada caída en la semana. El viernes se prevé la formación de placas a causa del viento del SW. El sábado, con las débiles nevadas y giro de viento a NW y N se pueden formar pequeñas placas. Con esta previsión, las placas se encontrarán pues en todas las orientaciones, especialmente por encima de los 2400 m. De cara al sábado serían más gruesas bajo collados y cordales en S y E. Tanto el viernes como el sábado las placas se presentarán frágiles, pueden caer de forma espontánea, e incluso alcanzar tamaño suficiente para enterrar a una persona. La nieve granulada existente, que se concentra en umbrías por encima de los 2100 m, quedará enterrada por las placas y puede dar paso a caídas naturales de placas, con capacidad de enterrar a una persona, a causa de esta capa débil, en estas cotas y orientaciones.

Distribución del manto nivoso

En umbrías hay nieve por encima de 1.600 m, esquiable por encima de unos 1.700 m. En solanas la nieve está presente por encima de 1.800 m. Los grosores están alrededor de 160-180 cm a 2.200 m. Estos valores son muy excedentarios para la época del año.

Tendencia para las próximas 48-72h

El fuerte viento de norte previsto el domingo barrerá la nieve y concentrará el peligro solo en terreno acotado y específico. Peligro EN PROGRESIVO DESCENSO

El próximo boletín será emitido el día 2026-03-14

5 MUY FUERTE	4 FUERTE	3 NOTABLE	2 LIMITADO	1 DÉBIL

EAWS EUROPEAN AVALANCHE WARNING SERVICES

ICGC Institut Cartogràfic i Geològic de Catalunya

Servei Meteorològic de Catalunya

Boletín de peligro de aludes Prepirineu
Del 13/03/2026 al 14/03/2026

(Válido fuera pistas de esquí y zonas no controladas)

LIMITADO (2) pasando a NOTABLE (3) en cotas altas el sábado

Situación primaria

Nieve venteada

Distribución

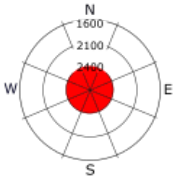

Tamaño

Origen

Tendencia

Situación secundaria

Capas débiles persistentes

Distribución

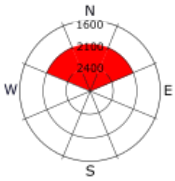

Tamaño

Origen

Tendencia

Estado del manto nivoso

El manto nivoso existente es susceptible de ser removido por el viento. El viernes se prevé la formación de placas de viento a causa del viento de componente SW. El sábado con las nevadas previstas con el giro de viento hacia NW y N se formarán nuevas placas de viento. El extremo norte de este sector, más influenciado por las nevadas, es donde las placas serán más gruesas. Con esta meteorologia prevista, los aludes de placa de viento se encontrarán pues en todas las orientaciones por encima de los 2100 m. De cara al sábado serían más gruesas bajo collados y crestas orientadas a S y E. Tanto el viernes como el sábado las placas se presentarán frágiles, pueden caer de forma espontánea y tener tamaño suficiente para enterrar a una persona. La nieve granulada existente, que se concentra en umbrías, quedará enterrada por las placas y puede dar paso a caídas naturales de placas, con capacidad de enterrar a una persona, debido a esta capa débil.

Distribución del manto nivoso

En umbrías hay nieve por encima de 1.600-1700 m. En solanas la nieve está presente por encima de 1.800-1.900 m. Los espesores, aunque irregulares, rondan los 60-80 cm en cotas medias.

Tendencia para las próximas 48-72h

El fuerte viento de norte previsto el domingo barrerá la nieve y concentrará el peligro solo en terreno acotado y específico. Peligro EN PROGRESIVO DESCENSO

El próximo boletín será emitido el día 2026-03-14

5 MUY FUERTE	4 FUERTE	3 NOTABLE	2 LIMITADO	1 DÉBIL

EAWS EUROPEAN AVALANCHE WARNING SERVICES

ICGC Institut Cartogràfic i Geològic de Catalunya

Servei Meteorològic de Catalunya

Boletín de peligro de aludes Ter-Freser
Del 13/03/2026 al 14/03/2026

(Válido fuera pistas de esquí y zonas no controladas)

NOTABLE (3) el sábado
LIMITADO (2) el viernes

Situación primaria

Nieve venteada

Distribución

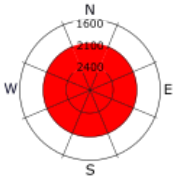

Tamaño

Origen

Tendencia

Situación secundaria

Capas débiles persistentes

Distribución

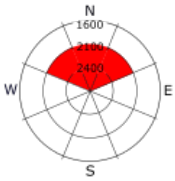

Tamaño

Origen

Tendencia

Estado del manto nivoso

El manto nivoso existente es susceptible de ser removido por el viento. El viernes se prevé la formación de placas de viento a causa del viento de componente SW. El sábado con las nevadas previstas con el giro de viento hacia NW y N se formarán nuevas placas de viento. El extremo norte de este sector, más influenciado por las nevadas, es donde las placas serán más gruesas. Con esta meteorologia prevista, los aludes de placa de viento se encontrarán pues en todas las orientaciones por encima de los 2100 m. De cara al sábado serían más gruesas bajo collados y crestas orientadas a S y E. Tanto el viernes como el sábado las placas se presentarán frágiles, pueden caer de forma espontánea y tener tamaño suficiente para enterrar a una persona. La nieve granulada existente, que se concentra en umbrías, quedará enterrada por las placas y puede dar paso a caídas naturales de placas, con capacidad de enterrar a una persona, debido a esta capa débil.

Distribución del manto nivoso

Hay nieve en el suelo por encima de 1.600-1.700 m. Es esquiable a partir de unos 1700 m. El manto nivoso presenta grosores muy excedentarios para la época del año. En lugares no afectados por el viento los grosores oscilan entre 80-100 cm a unos 2.000 my más de 150 cm por encima de 2.400 m.

Tendencia para las próximas 48-72h

El fuerte viento de norte previsto el domingo barrerá la nieve y concentrará el peligro solo en terreno acotado y específico. Peligro EN PROGRESIVO DESCENSO

El próximo boletín será emitido el día 2026-03-14

5 MUY FUERTE	4 FUERTE	3 NOTABLE	2 LIMITADO	1 DÉBIL

EAWS EUROPEAN AVALANCHE WARNING SERVICES