BUTLLETÍ DEL PERILL D'ALLAUS DEL PRINCIPAT D'ANDORRA

Servei meteorològic nacional
Principat d'Andorra

Elaborat el 13/03/2026 16:00
Propera actualització 14/03/2026 a les 16h

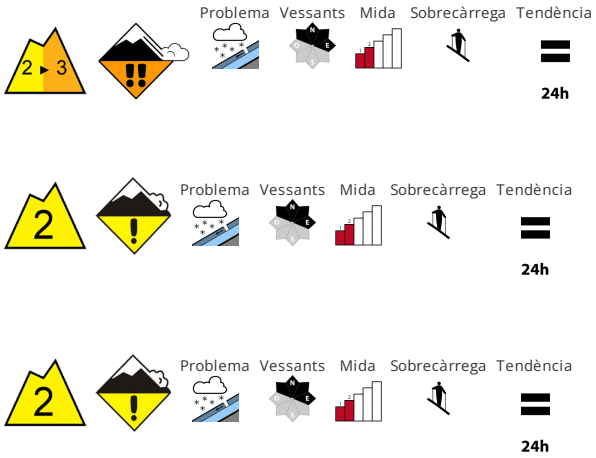

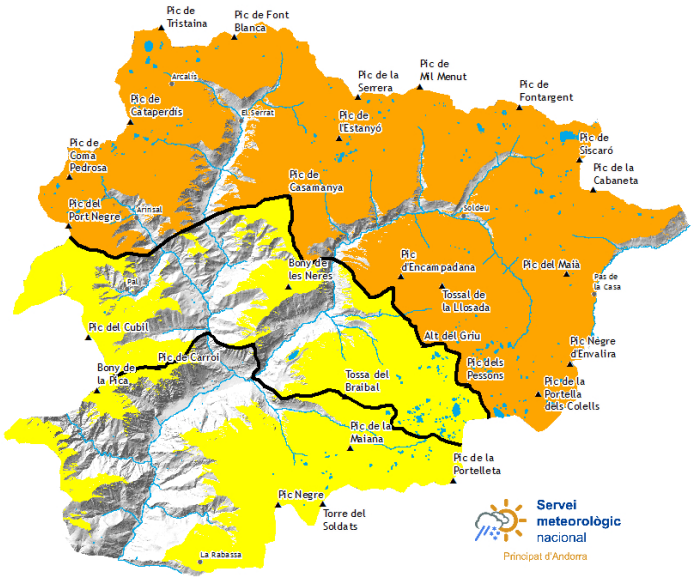

ESTABILITAT DEL MANTELL NIVAL

Al nord, el grau de perill 3 (marcat) s'assolirà en el transcurs de la jornada. La neu recent de dissabte es dipositarà a sobre d'una superfície desfavorable del mantell de neu vella sobretot en vessants inclinats orientats a nord-oest, nord i nord-est en cotes altes. Sobretot aquí a la part superior del mantell de neu hi ha capes febles de cristalls facetats. Les allaus seques poden ser desencadenades fàcilment i assolir mida mitjana. Poden desencadenar-se algunes allaus de lliscament basal també al matí. Els indrets perillosos són coberts amb neu recent i difícils de reconèixer amb mala visibilitat.

QUALITAT DE LA NEU

El dissabte caurà neu fins als 1200 m sobretot als al nord. Sobretot fins al diumenge cauran de 20 a 30 cm de neu per sobre dels 2000 m aproximadament, localment fins a 50 cm. El diumenge el vent serà fort.

GRUIXOS DEL MANTELL NIVAL FORA DE PISTA

Zona nord		Gruix neu		
Mantell Nival		1500m	2000m	2500m
N	1600 m	0 cm	150 cm	200 cm
S	1900 m	0 cm	100 cm	150 cm

Zona centre		Gruix neu		
Mantell Nival		1500m	2000m	2500m
N	1600 m	0 cm	150 cm	200 cm
S	1900 m	0 cm	100 cm	150 cm

Zona sud		Gruix neu		
Mantell Nival		1500m	2000m	2500m
N	1600 m	0 cm	120 cm	150 cm
S	1900 m	0 cm	60 cm	100 cm

Govern d'Andorra

EAWS EUROPEAN AVALANCHE WARNING SERVICES

Aquest butlletí ha estat elaborat seguint les normes i recomanacions de l'**European Avalanche Warning Services**, del qual el **Servei meteorològic Nacional** n'és membre

BUTLLETÍ DEL PERILL D'ALLAUS DEL PRINCIPAT D'ANDORRA

Servei meteorològic nacional
Principat d'Andorra

Informació detallada per espais naturals protegits

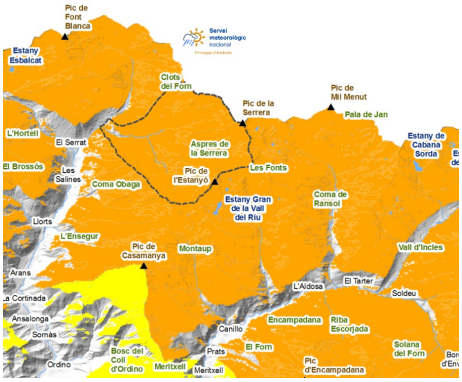

SORTENY

Es preveu neu a totes les cotes del Parc de Sorteny, l´ambient serà hivernal durant tot el cap de setmana. Dissabte no es preveu que faci vent, però la neu nova als vessants nord tindrà tendència a desprendre´s més fàcilment, ja que reposarà a sobre de cares planes formades aquests darrers dies. La mala visibilitat ens ha de mantenir a dins del bosc.

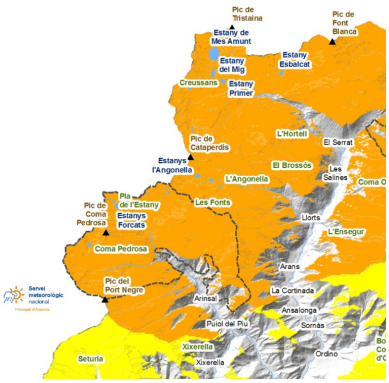

COMAPEDROSA

Aquest final de setmana amb nits serenes i baixes humitats s´han format grans angulosos a la superfície dels vessants nord. La neu nova reposarà a sobre d´aquesta capa de neu, fet que pot facilitar les allaus als vessants nord. Tot i així, la nevada, amb mala visibilitat a cotes altes, ens ha de fer quedar a cotes mitges.

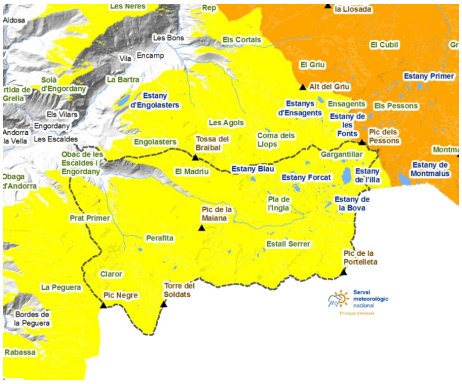

MADRIU-PERAFITA-CLAROR

La neu nova pot tapar acumulacions ventades als vessants nord i est, que haurem d´evitar. L´ambient tornarà a ser hivernal, amb neu nova i freda a totes les cotes.

Govern d'Andorra

EAWS
EUROPEAN AVALANCHE WARNING SERVICES

Aquest butlletí ha estat elaborat seguint les normes i recomanacions de l'**European Avalanche Warning Services**, del qual el **Servei meteorològic Nacional** n'és membre

BUTLLETÍ DEL PERILL D'ALLAUS DEL PRINCIPAT D'ANDORRA

Servei meteorològic nacional
Principat d'Andorra

Gruixos de neu nova dels darrers dies (de les últimes 24h mesurat a les 06:00h UTC)

	09/03/2026	10/03/2026	11/03/2026	12/03/2026
FEDA (Central)	0 cm	0 cm	0 cm	0 cm
Engolasters - FEDA	0 cm	0 cm	0 cm	0 cm
Bony de les Neres	0 cm	0 cm	0 cm	0 cm
Sorteny	4 cm	0 cm	7 cm	0 cm
Les Fonts d'Arinsal	0 cm	0 cm	5 cm	0 cm
Perafita	0 cm	0 cm	0 cm	0 cm
Tossa Espiolets	0 cm	0 cm	4 cm	0 cm
Grau Roig - FEDA	1 cm	0 cm	1 cm	0 cm
Fontverd	0 cm	0 cm	0 cm	0 cm
Ransol - FEDA	0 cm	0 cm	0 cm	0 cm
Caborreu	0 cm	1 cm	2 cm	0 cm
La Solana	0 cm	0 cm	3 cm	0 cm
Coll Pa	0 cm	0 cm	0 cm	0 cm
Envalira Antenes	3 cm	2 cm	0 cm	0 cm
Vall del Riu FEDA	0 cm	0 cm	0 cm	0 cm