BUTLLETÍ DEL PERILL D'ALLAUS DEL PRINCIPAT D'ANDORRA

Elaborado el 13/03/2026 16:00
Proxima actualización 14/03/2026 a las 16h

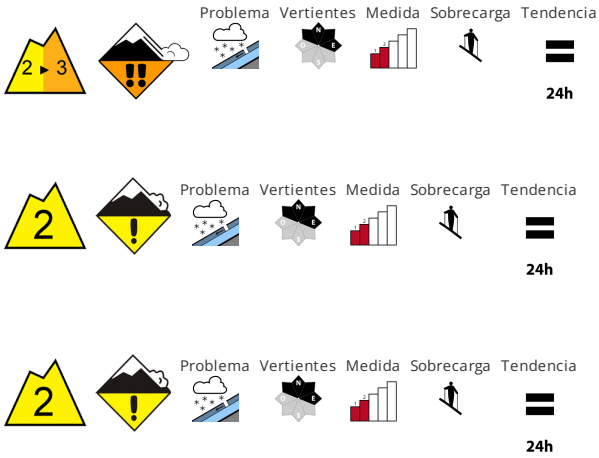

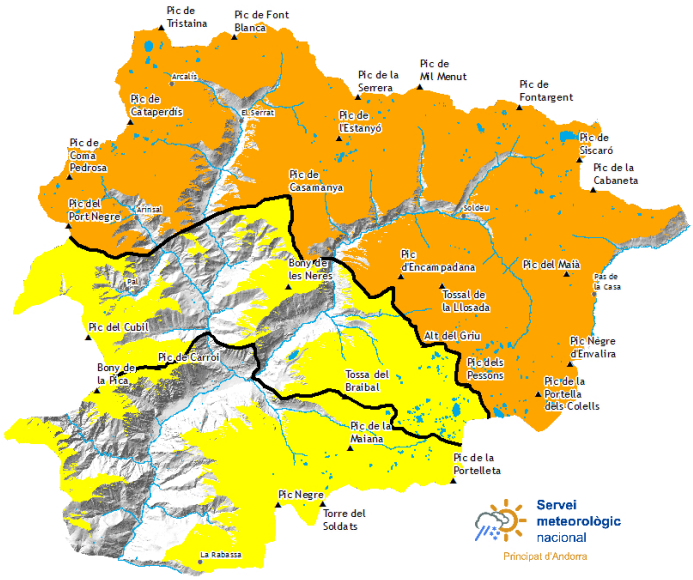

CALIDAD DE LA NIEVE

Al norte, el grado de peligro 3 (notable) se alcanzará en el transcurso de la jornada. La nieve reciente del sábado se depositará encima de una superficie desfavorable del manto de nieve antigua sobre todo en laderas inclinadas orientadas a noroeste , norte y nordeste en cotas altas. Sobre todo aquí en la parte superior del manto de nieve hay capas débiles de cristales facetados. Los aludes de nieve seca pueden ser desencadenadas fácilmente y alcanzar un tamaño mediano. Pueden desencadenarse algunos aludes de deslizamiento basal por la mañana. Los lugares peligrosos están cubiertos con nieve reciente y resultan difíciles de reconocer con poca visibilidad.

ESTABILIDAD DEL MANTO NIVOSO

El sábado caerá nieve hasta los 1200 m sobre todo en los norte. Sobre todo hasta el domingo caerán de 50 a 30 cm de nieve por encima de los 2000 m aproximadamente, localmente hasta 50 cm. El domingo el viento soplará fuerte.

ESPESORES DEL MANTO NIVOSO FUERA DE PISTA

Zona norte		Espesor nieve		
Manto Nival		1500m	2000m	2500m
N	1600 m	0 cm	150 cm	200 cm
S	1900 m	0 cm	100 cm	150 cm

zona centro		Espesor nieve		
Manto Nival		1500m	2000m	2500m
N	1600 m	0 cm	150 cm	200 cm
S	1900 m	0 cm	100 cm	150 cm

Zona sur		Espesor nieve		
Manto Nival		1500m	2000m	2500m
N	1600 m	0 cm	120 cm	150 cm
S	1900 m	0 cm	60 cm	100 cm

Govern d'Andorra

EAWS EUROPEAN AVALANCHE WARNING SERVICES

Aquest butlletí ha estat elaborat seguint les normes i recomanacions de l'**European Avalanche Warning Services**, del qual el **Servei meteorològic Nacional** n'és membre

BUTLLETÍ DEL PERILL D'ALLAUS DEL PRINCIPAT D'ANDORRA

Servei meteorològic nacional
Principat d'Andorra

Información detallada por espacios naturales protegidos

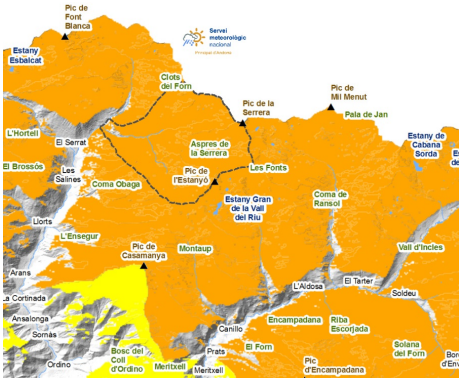

SORTENY

Se prevé nieve en todas las cotas del Parque de Sorteny, el ambiente será invernal durante todo el fin de semana. El sábado no se prevé que haga viento, pero la nieve nueva en las vertientes norte tendrá tendencia a desprenderse más fácilmente, ya que repondrá sobre caras planas formadas estos últimos días. La mala visibilidad debe mantenernos dentro del bosque.

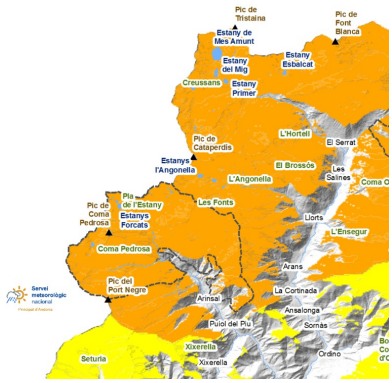

COMAPEDROSA

Este final de semana con noches serenas y bajas humedades se han formado grandes angulosos en la superficie de las vertientes norte. La nieve nueva repondrá encima de esta capa de nieve, lo que puede facilitar los aludes en las vertientes norte. Sin embargo, la nevada, con mala visibilidad en cotas altas, debe hacernos quedar en cotas medias.

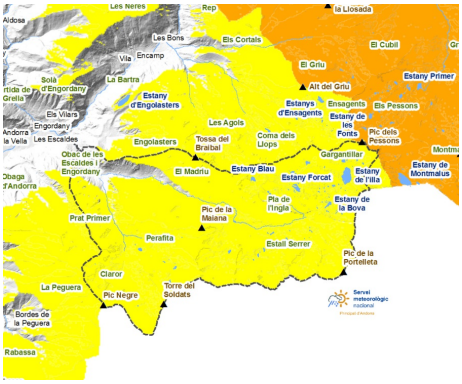

MADRIU-PERAFITA-CLAROR

La nieve nueva puede tapar acumulaciones venteadas en las vertientes norte y este, que deberemos evitar. El ambiente volverá a ser invernal, con nieve nueva y fría en todas las cotas.

Govern d'Andorra

EAWS EUROPEAN AVALANCHE WARNING SERVICES

Aquest butlletí ha estat elaborat seguint les normes i recomanacions de l'**European Avalanche Warning Services**, del qual el **Servei meteorològic Nacional** n'és membre

BUTLLETÍ DEL PERILL D'ALLAUS DEL PRINCIPAT D'ANDORRA

Servei meteorològic nacional
Principat d'Andorra

Espesores de nieve nueva de los últimos días (de las ultimas 24h mesurado a las 06:00h UTC)

	09/03/2026	10/03/2026	11/03/2026	12/03/2026
FEDA (Central)	0 cm	0 cm	0 cm	0 cm
Engolasters - FEDA	0 cm	0 cm	0 cm	0 cm
Bony de les Neres	0 cm	0 cm	0 cm	0 cm
Sorteny	4 cm	0 cm	7 cm	0 cm
Les Fonts d'Arinsal	0 cm	0 cm	5 cm	0 cm
Perafita	0 cm	0 cm	0 cm	0 cm
Tossa Espiolets	0 cm	0 cm	4 cm	0 cm
Grau Roig - FEDA	1 cm	0 cm	1 cm	0 cm
Fontverd	0 cm	0 cm	0 cm	0 cm
Ransol - FEDA	0 cm	0 cm	0 cm	0 cm
Caborreu	0 cm	1 cm	2 cm	0 cm
La Solana	0 cm	0 cm	3 cm	0 cm
Coll Pa	0 cm	0 cm	0 cm	0 cm
Envalira Antenes	3 cm	2 cm	0 cm	0 cm
Vall del Riu FEDA	0 cm	0 cm	0 cm	0 cm