MINISTERO DELLA DIFESA

meteomont Servizio Nazionale di previsione neve e valanghe

EAWS EUROPEAN AVALANCHE WARNING SERVICES

CARABINIERI

AERONAUTICA MILITARE SERVIZIO METEOROLOGICO

ALPI RETICHE

Bollettino Valanghe N. 374/2026 del 13/03/2026 ore 14.00
Validità 48 ore prossima emissione 14/03/2026

A cura del Servizio METEOMONT dell'ARMA dei CARABINIERI
In collaborazione con Servizio Meteorologico dell'Aeronautica militare

SITUAZIONE alle 14:00 del 13/03/2026

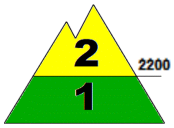

SITUAZIONE TIPO: passaggio da poca a molta neve.



SITUAZIONE TIPO: situazione primaverile.

Quota neve (mslm)	Nord	Sud
	1300 - 1600	2100 - 2400

Altezza Neve (cm)	Neve al suolo	Neve Fresca	Quota (mslm)
	115	0	2265
	34	0	1640

VALANGHE OSSERVATE: Nessuna valanga.

PREVISIONI 14/03/2026

GRADO DI PERICOLO: MARCATO 3

SITUAZIONE TIPO: neve a debole coesione e vento.

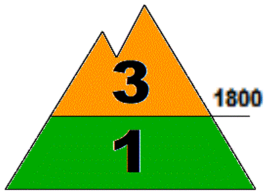

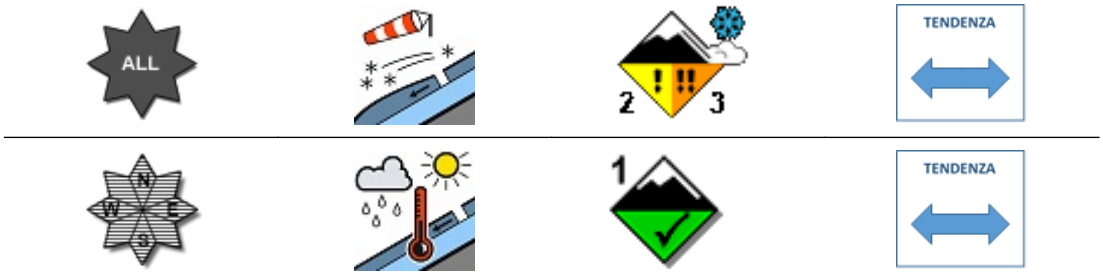

SITUAZIONE TIPO: pioggia su neve.

MANTO NEVOSO: La stabilità del manto nevoso è molto scarsa su alcuni punti (aree) per tutte le esposizioni al di sopra di 1800 mslm, possibili valanghe di dimensioni grandi.
La stabilità del manto nevoso è scarsa su pochi punti (aree) per isolati pendii al di sotto di 1800 mslm, possibili valanghe di dimensioni piccole.

AVVERTENZE

In considerazione delle avverse condizioni meteorologiche previste, e della scarsa visibilità, risulterà difficoltosa l'individuazione dell'itinerario e della valutazione del singolo pendio.

SCALA EUROPEA DEL GRADO DI PERICOLO VALANGHE

LEGENDA PROBLEMA

Bollettino realizzato su scala sinottica-regionale (standard EAWS). La sua valutazione non può escludere in alcun modo la necessità di una seria e capace valutazione locale del pericolo (singolo pendio) che può essere anche sensibilmente diverso. Le previsioni meteorologiche sono relative all'orario UTC (per l'Italia +1 in inverno e +2 in estate).

MINISTERO DELLA DIFESA

meteomont
Servizio Nazionale di previsione neve e valanghe

EAWS EUROPEAN AVALANCHE WARNING SERVICES

CARABINIERI

ALPI RETICHE

PREVISIONE METEO

Quota		14/03/2026 h6:00	14/03/2026 h12:00	14/03/2026 h18:00
1000	Venti	01 Nodi da Sud	02 Nodi da Sud	01 Nodi da Sud
	Temperature	-04 °C	-02 °C	-02 °C
	Temp.percepita	-4 °C	-2 °C	-2 °C
2000	Venti	01 Nodi da Sud	02 Nodi da Sud	01 Nodi da Sud
	Temperature	-04 °C	-02 °C	-02 °C
	Temp.percepita	-4 °C	-2 °C	-2 °C
3000	Venti	12 Nodi da Sud	12 Nodi da Sud	13 Nodi da Sud
	Temperature	-09 °C	-09 °C	-08 °C
	Temp.percepita	-17 °C	-17 °C	-16 °C
Zero termico		1300-1500 m.	1600-1800 m.	1600-1800 m.
Fenomeno				
Stato del cielo				

LEGENDA FENOMENI

Assenza Fenomeni · Nebbia · Foschia · Pioggia debole · Pioggia moderata · Pioggia forte · Temporali

Nevicata debole · Nevicata moderata · Nevicata forte

STATO DEL CIELO

Sereno · Poco nuvoloso · Nuvoloso · Molto nuvoloso · Coperto

Parametri meteonivometrici registrati presso i campi di rilevamento il 13/03/2026.

Località	Comune	Quota (m.s.l.m.)	Altezza neve (cm)	Neve caduta nelle 24 ore (cm)	Temp. Min (°C)	Temp. Max (°C)	Condizioni del tempo
BORMIO2000-LECCIONA	Valdisotto (SO)	2050	55	0	-3	+7	Assenza di precipitazioni
VALAR	Valdidentro (SO)	1930	66	0	-7	+5	Assenza di precipitazioni
DOSSO DEL VALLONE	Valfurva (SO)	2582	60	0	-8	+0	Assenza di precipitazioni
TORRE DI SM. CORTI *	Torre di Santa Maria (SO)	1774	35	0	N.P.	N.P.	Assenza di precipitazioni
COLONIA VIGILI	Ponte di Legno (BS)	1640	34	0	0	+7	Assenza di precipitazioni
MONTE SCALE *	Valdidentro (SO)	2252	46	0	N.P.	N.P.	Assenza di precipitazioni
COLMA DI ARCOGLIO *	Torre di Santa Maria (SO)	2265	115	0	N.P.	N.P.	Assenza di precipitazioni

(*) Rilievi fuori campo

L'INFORMAZIONE E' PREVENZIONE - LEGGI L'ATTUALE GRADO DI PERICOLO VALANGHE!

IL CAPO DEL CENTRO NAZIONALE METEOMONT
(Ten. Col. RFI Emanuela Gini)
FIRMA AUTOGRAFA OMESSA AI SENSI
DELL'ART.3 DEL D.LGS N.39/1993

Bollettino realizzato su scala sinottica-regionale (standard EAWS). La sua valutazione non può escludere in alcun modo la necessità di una seria e capace valutazione locale del pericolo (singolo pendio) che può essere anche sensibilmente diverso. Le previsioni meteorologiche sono relative all'orario UTC (per l'Italia +1 in inverno e +2 in estate).