# Bulletin d'estimation du risque d'avalanche

(valable en dehors des pistes balisées et ouvertes)

# MASSIF : Pelvoux

Rédigé le vendredi 13 mars 2026 à 15h

## Estimation des risques pour le : SAMEDI 14 MARS

**NOUVELLES PLAQUES EN FORMATION AVEC LES CHUTES DE NEIGE, PARFOIS GRANDES EN VERSANTS NORD D'ALTITUDE.**

3

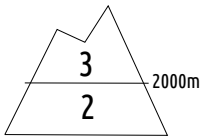


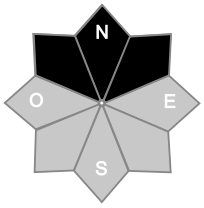


Plaques + épaisses

Au-dessus de 2000m indice de risque marqué, plus bas indice limité.

**Départs spontanés :** de plus en plus fréquents au fil des chutes de neige, rarement grands en versants nord d'altitude.

**Déclenchements provoqués :** plaques dans la neige fraiche, plus sensibles et épaisses en versants nord d'altitude.

Indices de risque : 5 très fort - 4 fort - 3 marqué - 2 limité - 1 faible -- En noir : les pentes les plus dangereuses

## Stabilité du manteau neigeux

**Situation avalancheuse typique :** neige fraîche couche fragile persistante

**Déclenchements provoqués :** plaques en formation dans la neige fraiche, plus nombreuses et épaisses en journée au fil des chutes de neige. Plaques faciles à déclencher, possibles en toutes orientations et générant des avalanches de taille petite à moyenne (taille 1 à 2). Elles sont plus sensibles et volumineuses en ubacs au-dessus de 1800/2000 m où la neige fraiche se dépose sur des couches fragiles persistantes peu enfouies, générant des avalanches de taille moyenne, rarement grande (taille 2 à 3) avec des cassures parfois larges.
Un départ très volumineux emportant la totalité du manteau neigeux reste non exclu suite à un premier départ de surface, par sollicitation de couches fragiles présentes à la base du manteau neigeux en versant est, nord et ouest au-dessus de 2000/2200 m, voir en versant sud à haute altitude.

**Départs spontanés :** peu probables dans la nuit de vendredi à samedi, puis devenant de plus en plus fréquent dès la matinée au fil des chutes de neige. Départs ponctuels de taille petite à moyenne en général (taille 1 à 2), rarement grand (taille 3) avec cassure linéaire en ubacs au-dessus de 2000/2200 m, en cas de sollicitation d'une couche fragile persistante enfouie.

## Qualité de la neige

**L'enneigement** reste globalement excédentaire ou se rapproche des normales selon les secteurs. Les limites d'enneigement remontent dans les pentes bien exposées au soleil.
Hauteurs de neige observées : 298 cm à la Nivôse des Écrins vers 3000 m, 197 cm au Pré de Mme Carle à 1900 m.

**Limite d'enneigement skiable** : vers 1300/1400 m en ubacs, 1600/1700 m en adrets pas trop raides.

**État de la neige de surface** : on retrouve en surface une couche de neige fraiche à toute altitude, de plus en plus épaisse en fil de la journée. Elle se dépose sur un manteau neigeux croûté dans les adrets, ainsi qu'en ubacs sous 1800/2000 m, mais sur de la neige plus froide et meuble au-dessus. Neige travaillée par le vent proche des crêtes.

## Aperçu météo pour le samedi 14 mars

| | nuit | matin | après-midi | soir |
|---|---|---|---|---|
| | | | | |

Chutes de neige, forte le matin, plus faible l'après-midi. Cumuls de l'ordre de 15 à 30 cm sur la journée.

| | | | | |
|---|---|---|---|---|
| **Pluie-Neige** | 1 400 m | 800 m | 1 000 m | |
| **Iso 0 °C** | 1 800 m | 1 200 m | 1 400 m | 1 200 m |
| **Vent 2000 m** | ↗ 15 km/h | → 20 km/h | ↓ 20 km/h | ↘ 30 km/h |
| **Vent 3000 m** | ↗ 45 km/h | ↗ 30 km/h | ↘ 30 km/h | ↘ 50 km/h |

## Épaisseur de neige hors-piste

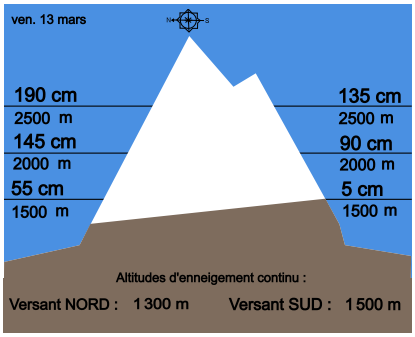


## Précipitations à 1800 m

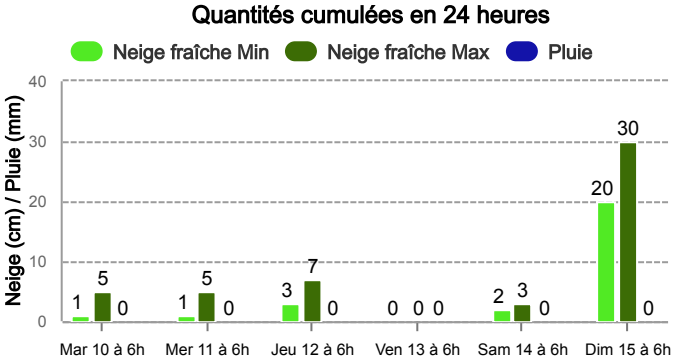


## Tendance du dimanche 15 mars

3

**Indice de risque marqué**

Nouvelles plaques en formation dans la neige fraiche avec le renforcement du vent de nord-est. Départs parfois volumineux en versant nord.

Pour consulter la vigilance en cours, veuillez vous rendre sur le site https://vigilance.meteofrance.fr/fr

Météo-France - 73 avenue de Paris, 94165 Saint-Mandé cedex - Contact : contact@meteo.fr

Rédigé par Météo-France avec la contribution des observateurs du réseau nivo-météorologiques. Partenariat : ANMSM (Maires de Stations de Montagne), DSF (Domaines Skiables de France), ADSP (Directeurs de Pistes et de la Sécurité des Stations de Sports d'Hiver) et autres acteurs de la montagne.

Bulletin neige & avalanches par téléphone au

**0 892 68 10 20** Service 0,35 € / min + prix appel

RÉPUBLIQUE FRANÇAISE
*Liberté Égalité Fraternité*

METEO FRANCE
À VOS CÔTÉS, DANS UN CLIMAT QUI CHANGE

# Bulletin d'estimation du risque d'avalanche

## (valable en dehors des pistes balisées et ouvertes)

# MASSIF : Pelvoux

Rédigé le vendredi 13 mars 2026 à 15h

## Conditions nivo-météo des 7 derniers jours

| | sam. 07/03 | | | | dim. 08/03 | | | | lun. 09/03 | | | | mar. 10/03 | | | | mer. 11/03 | | | | jeu. 12/03 | | | | ven. 13/03 | | | |
|---|---|---|---|---|---|---|---|---|---|---|---|---|---|---|---|---|---|---|---|---|---|---|---|---|---|---|---|---|
| | 03h | 09h | 15h | 21h | 03h | 09h | 15h | 21h | 03h | 09h | 15h | 21h | 03h | 09h | 15h | 21h | 03h | 09h | 15h | 21h | 03h | 09h | 15h | 21h | 03h | 09h | 15h | 21h |
| Météo | | | | | | | | | | | | | | | | | | | | | | | | | | | | |
| Vent (km/h) | 25 | 20 | 20 | 25 | 20 | 20 | 20 | 20 | 20 | 20 | 25 | 30 | 20 | 25 | 20 | 15 | 15 | 20 | 30 | 35 | 35 | 25 | 20 | 10 | 10 | 15 | 20 | 20 |
| à 3000m | | | | | | | | | | | | | | | | | | | | | | | | | | | | |
| Vent (km/h) | 10 | 10 | 10 | 10 | 10 | 10 | 10 | 10 | 5 | 15 | 15 | 15 | 10 | 10 | 15 | 5 | 5 | 10 | 20 | 10 | 15 | 20 | 15 | 5 | 5 | 5 | 15 | 15 |
| à 2000m | | | | | | | | | | | | | | | | | | | | | | | | | | | | |

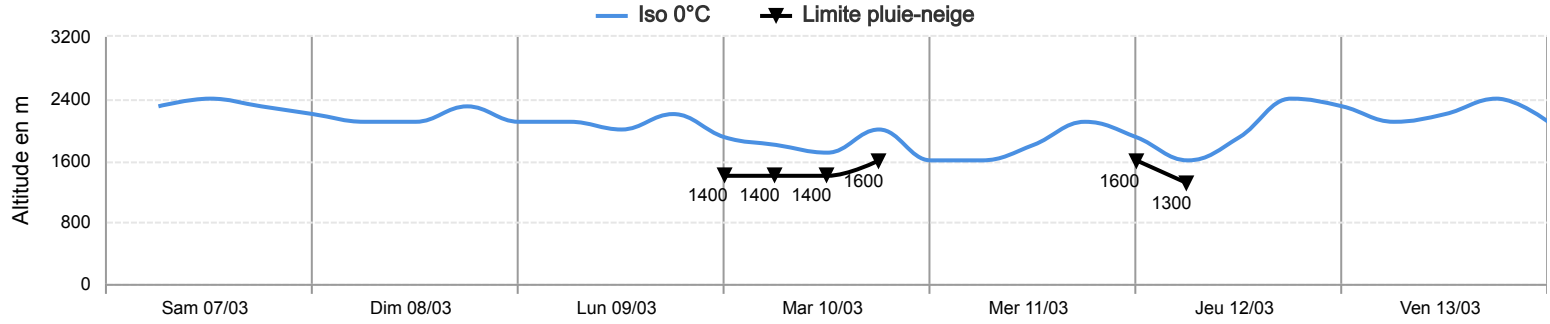


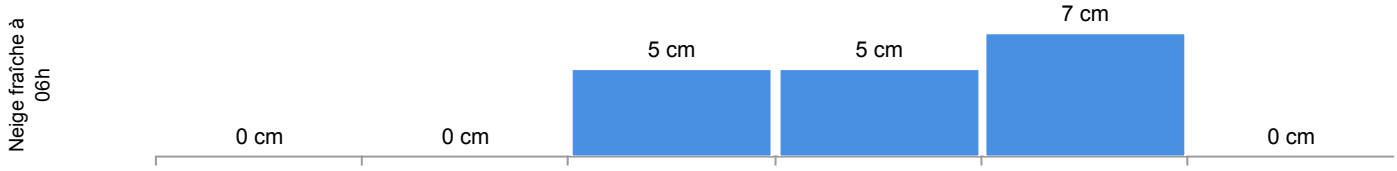


| Risque d'avalanche | sam. 07/03 | dim. 08/03 | lun. 09/03 | mar. 10/03 | mer. 11/03 | jeu. 12/03 | ven. 13/03 |
|---|---|---|---|---|---|---|---|
| | 2 | 2 | 2 | 2 | 2 | 2 | 2 |

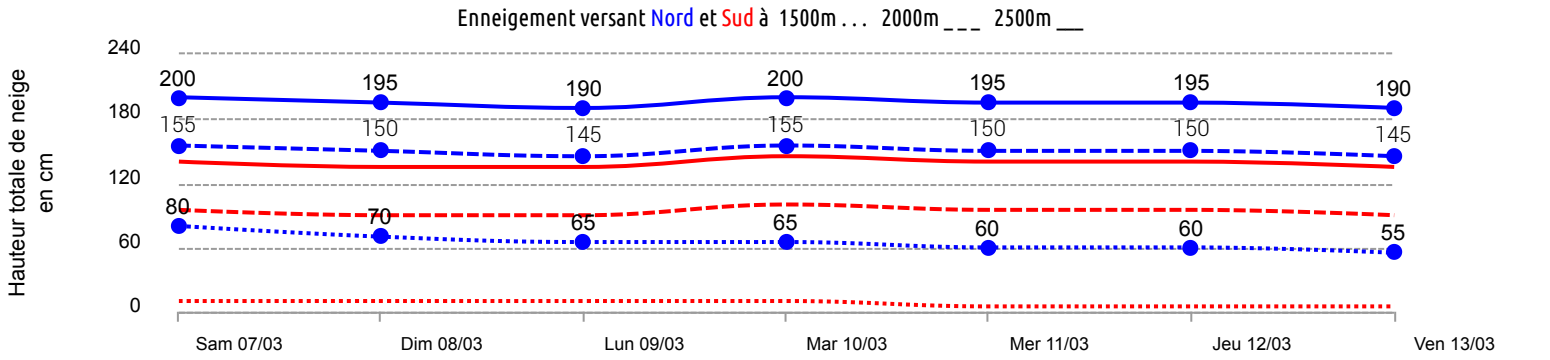


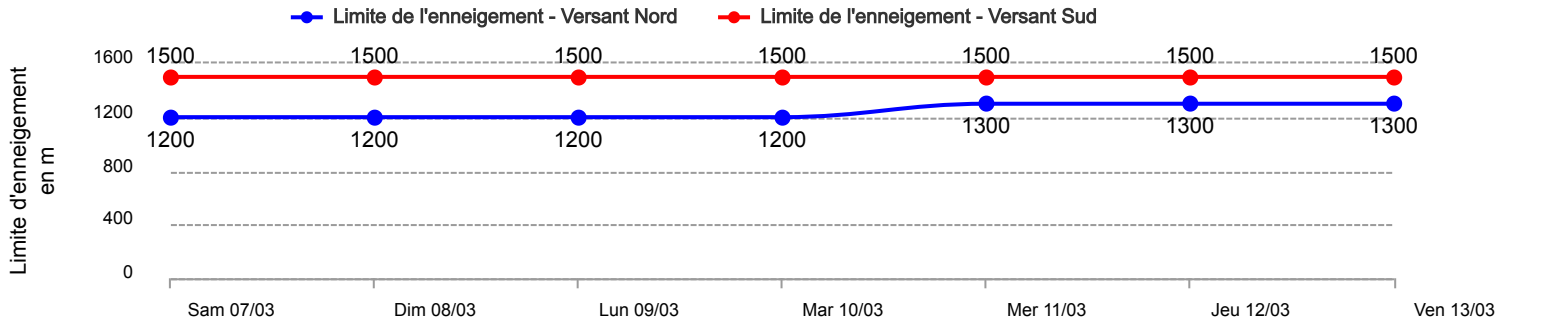


Pour consulter la vigilance en cours, veuillez vous rendre sur le site https://vigilance.meteofrance.fr/fr


**Météo-France - 73 avenue de Paris, 94165 Saint-Mandé cedex - Contact : contact@meteo.fr**



Rédigé par Météo-France avec la contribution des observateurs du réseau nivo-météorologiques. Partenariat : ANMSM (Maires de Stations de Montagne), DSF (Domaines Skiables de France), ADSP (Directeurs de Pistes et de la Sécurité des Stations de Sports d'Hiver) et autres acteurs de la montagne.



Bulletin neige & avalanches par téléphone au
0 892 68 10 20 Service 0,35 € / min + prix appel