Bulletin d'estimation du risque d'avalanche
(valable en dehors des pistes balisées et ouvertes)

MASSIF : Aravis

Rédigé le vendredi 13 mars 2026 à 16h

Estimation des risques pour le : SAMEDI 14 MARS

DE NOUVELLES INSTABILITÉS DANS LA NEIGE FRAICHE

3

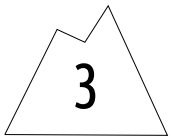

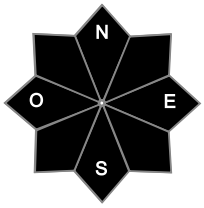

Indice de risque marqué.

Départs spontanés : Départs en neige fraiche pendant les chutes

Déclenchements provoqués : Plaques friables dans la neige récente, de plus en plus épaisses

Indices de risque : 5 très fort - 4 fort - 3 marqué - 2 limité - 1 faible -- En noir : les pentes les plus dangereuses

Stabilité du manteau neigeux

Situation avalancheuse typique : neige fraîche couche fragile persistante

Déclenchements provoqués :

* **Plaques friables dans la neige récente**, un peu plus nombreuses au fil des chutes, **facilement déclenchables** par un skieur. Taille 1 puis 2. Dans les **versants NO/N/NE, au-dessus de 1800 m**, la présence d'une couche fragile persistante facilite le déclenchement et **augmente la taille** des plaques. Taille 2 à 3, avec des cassures pouvant atteindre 1 m.
* Plaques à vent formées dans la nuit de vendredi à samedi par le vent de sud-ouest, facilement déclenchables par un skieur, mais recouvertes par la neige fraîche en journée. Taille 2.

Départs spontanés :

Départs majoritairement ponctuels, quelques fois en plaques dans les versants froids, en tous versants, pendant les chutes. Taille 1 puis 2. Dans de rares cas, ces départs peuvent provoquer une avalanche en cascade sollicitant la couche fragile persistante, taille 2 rarement 3.

Qualité de la neige

Enneigement :

Correct pour la saison.

Neige fraîche à partir de 900 m, mais avec une vraie sous couche uniquement au-dessus de 1200/1300 m en nord et 1400/1700 m en sud.

Qualité de la neige de samedi :

Quelques centimètres de neige fraîche en début de la journée, qui s'épaississent en cours de journée. Neige légère d'aspect poudreux. En face nord au-dessus de 1800 m et dans les versants ensoleillés au-dessus de 2500 m, cette neige repose sur de la vieille neige encore froide. Ailleurs, elle repose sur une croûte.

Aperçu météo pour le samedi 14 mars

Fort vent dans la nuit, puis neige modérée en matinée, faiblissant l'après-midi.

	nuit	matin	après-midi	soir
Pluie-Neige	1 300 m	700 m	700 m	500 m
Iso 0 °C	1 700 m	1 100 m	1 000 m	900 m
Vent 2000 m	↗ 80 km/h	→ 20 km/h	↘ 20 km/h	↙ 50 km/h
Vent 2500 m	↗ 100 km/h	↗ 30 km/h	↘ 30 km/h	↙ 60 km/h

Épaisseur de neige hors-piste

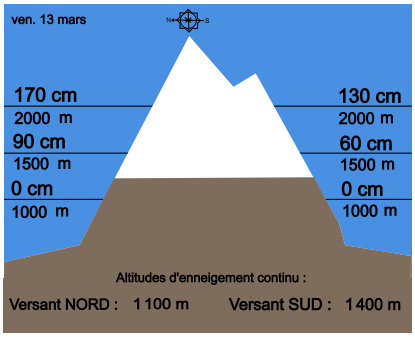

Précipitations à 1800 m

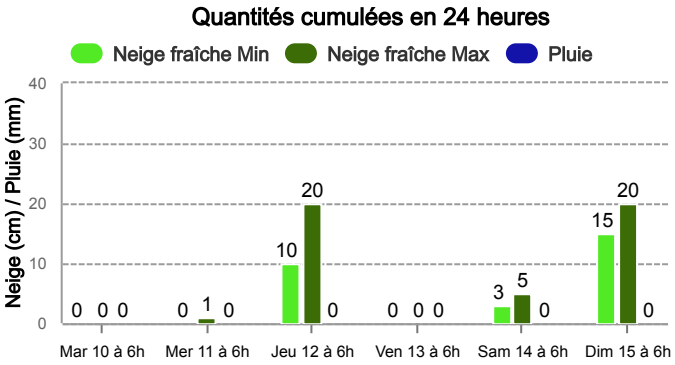

Tendance du dimanche 15 mars

3

Indice de risque marqué

De nouveau du fort vent dans la nuit de samedi à dimanche ⇒ nouvelles plaques à vent dans la neige récente.

Pour consulter la vigilance en cours, veuillez vous rendre sur le site https://vigilance.meteofrance.fr/fr

Météo-France - 73 avenue de Paris, 94165 Saint-Mandé cedex - Contact : contact@meteo.fr

Rédigé par Météo-France avec la contribution des observateurs du réseau nivo-météorologiques. Partenariat : ANMSM (Maires de Stations de Montagne), DSF (Domaines Skiables de France), ADSP (Directeurs de Pistes et de la Sécurité des Stations de Sports d'Hiver) et autres acteurs de la montagne.

Bulletin neige & avalanches par téléphone au

0 892 68 10 20 Service 0,35 € / min + prix appel

RÉPUBLIQUE FRANÇAISE
Liberté Égalité Fraternité

METEO FRANCE
À VOS CÔTÉS, DANS UN CLIMAT QUI CHANGE

Bulletin d'estimation du risque d'avalanche
(valable en dehors des pistes balisées et ouvertes)

MASSIF : Aravis

Rédigé le vendredi 13 mars 2026 à 16h

Conditions nivo-météo des 7 derniers jours

	sam. 07/03				dim. 08/03				lun. 09/03				mar. 10/03				mer. 11/03				jeu. 12/03				ven. 13/03			
	03h	09h	15h	21h	03h	09h	15h	21h	03h	09h	15h	21h	03h	09h	15h	21h	03h	09h	15h	21h	03h	09h	15h	21h	03h	09h	15h	21h
Météo																												
Vent (km/h)	20	10	15	10	20	10	15	15	15	15	20	25	25	40	40	40	40	50	60	45	30	20	5	10	30	45	50	70
à 2500m																												
Vent (km/h)	5	5	5	5	10	5	10	5	5	5	10	10	10	20	30	30	30	40	50	30	20	10	5	5	20	40	40	55
à 2000m																												

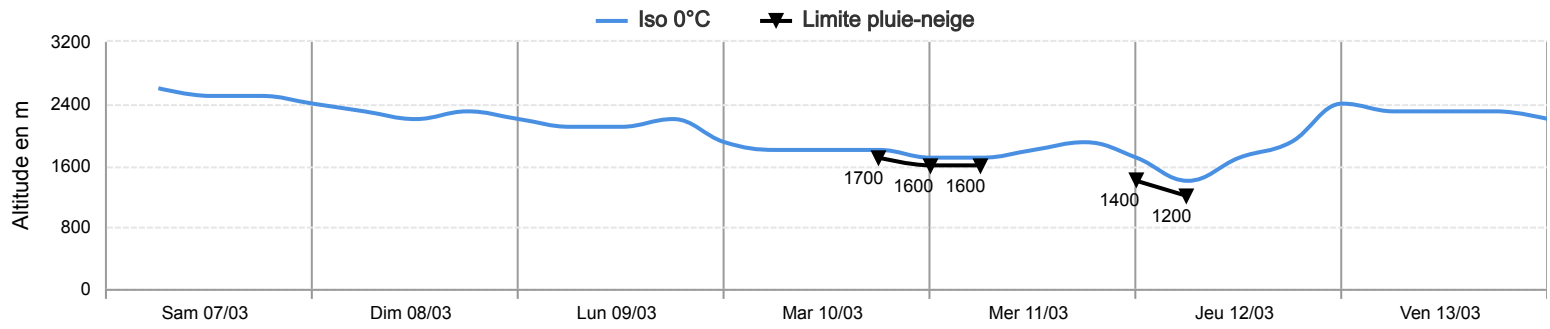

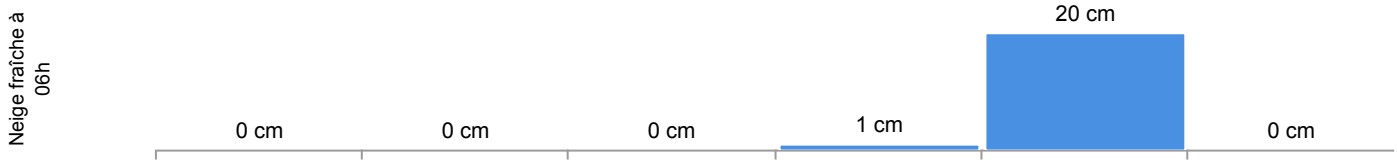

Risque d'avalanche	sam. 07/03	dim. 08/03	lun. 09/03	mar. 10/03	mer. 11/03	jeu. 12/03	ven. 13/03
	2	2	2	2	1	2	2

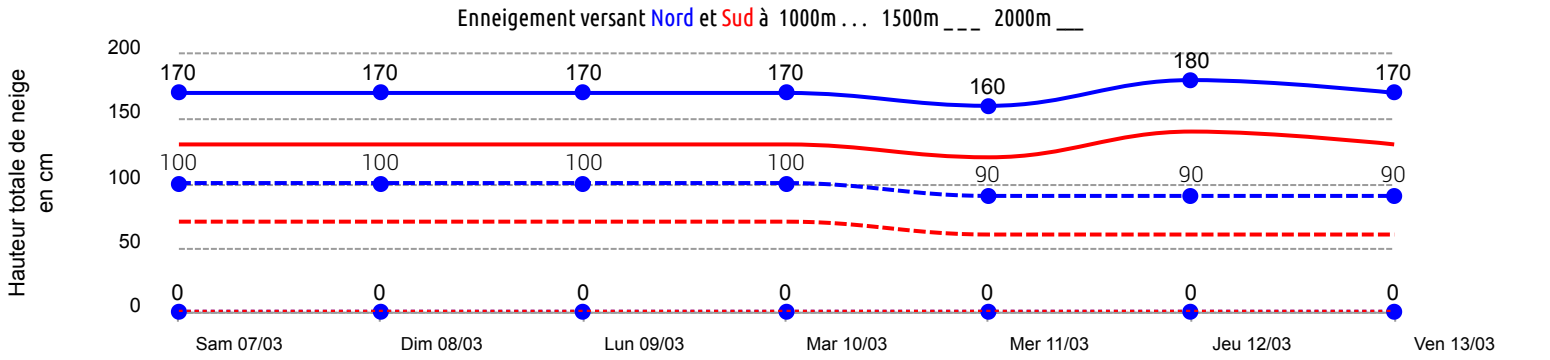

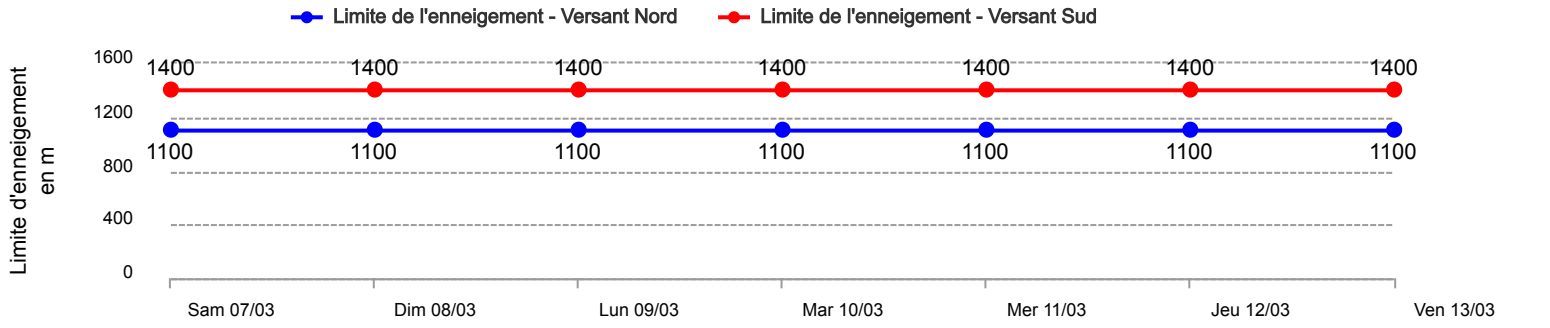

Pour consulter la vigilance en cours, veuillez vous rendre sur le site https://vigilance.meteofrance.fr/fr

Météo-France - 73 avenue de Paris, 94165 Saint-Mandé cedex - Contact : contact@meteo.fr

Rédigé par Météo-France avec la contribution des observateurs du réseau nivo-météorologiques. Partenariat : ANMSM (Maires de Stations de Montagne), DSF (Domaines Skiables de France), ADSP (Directeurs de Pistes et de la Sécurité des Stations de Sports d'Hiver) et autres acteurs de la montagne.

Bulletin neige & avalanches par téléphone au
0 892 68 10 20 Service 0,35 € / min + prix appel