RÉPUBLIQUE FRANÇAISE
Liberté Égalité Fraternité

METEO FRANCE
À VOS CÔTÉS, DANS UN CLIMAT QUI CHANGE

Bulletin d'estimation du risque d'avalanche
(valable en dehors des pistes balisées et ouvertes)

MASSIF : Aure Louron

Rédigé le vendredi 13 mars 2026 à 16h

Estimation des risques pour le : SAMEDI 14 MARS

CONDITIONS TRES HIVERNALES : CHUTES DE NEIGE VENTEES, FROID.

3

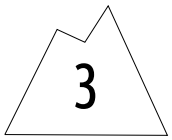

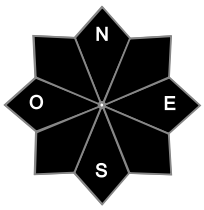

Indice de risque marqué.

Départs spontanés : en neige récente durant les chutes.

Déclenchements provoqués : plaques instables dans la neige récente.

Indices de risque : 5 très fort - 4 fort - 3 marqué - 2 limité - 1 faible -- En noir : les pentes les plus dangereuses

Stabilité du manteau neigeux

Situation avalancheuse typique : neige fraîche

Déclenchements provoqués : risque **marqué** (3).
Déclenchements **faciles par un seul skieur ou randonneur** d'**avalanches de plaques instables en toutes orientations**, les chutes de neige se faisant avec du vent de nord-ouest à nord soutenu. La couche de neige fraîche augmentant au fil des heures, les **cassures linéaires** deviendront **plus importantes au cours de la journée**, donnant lieu à des avalanches de **taille 1 à 2 en matinée**, **taille 2 à 3 ensuite**.
Ces plaques **déjà présentes au-dessus de 2000 à 2200m en matinée** se formeront aussi **plus bas l'après-midi sous le vent turbulent à tous niveaux** de nord-ouest à nord.
Départs de blocs dans les versants exposés au vent de nord-ouest à nord, blocs rapidement pulvérulents en glissant dans les pentes déventées.
De plus, pour **toute la journée au-dessus de 2400/2500m** dans **quelques secteurs nord raides restés à l'ombre**, les chutes de neige ventées se font sur une couche de **neige restée sèche et meuble**, mais **ayant perdue toute cohésion** (grains anguleux) ces dernières nuits, et qui sert donc de **couche fragile** : les **nouvelles plaques** y seront d'autant **plus facilement déclenchables par faible sollicitation**.

Observables : plaques **peu identifiables en début de matinée**, mais devenant de plus en plus **visibles** (transport) et **évidentes au fil des heures** avec le renforcement du vent. **Fissures devant les skis ou les raquettes**.

Départs spontanés : risque **faible devenant limité** (1 à 2) en **pentes raides**.
Départs ponctuels en général, provoquant des **avalanches de poudreuse petites à quelquefois moyennes** au cours de la matinée, des avalanches **moyennes plus fréquentes ensuite au fur et à mesure de l'augmentation de la couche de neige fraîche**.
Quelques **cassures linéaires**, **plutôt l'après-midi** et dans les secteurs **à l'abri du vent**, les **chutes de neige** se poursuivant et le **transport** par le vent **surchargeant** les plaques déjà formées ou décrites ci-dessus, provoquant des **avalanches de taille moyenne, plus rare et plus localisée** une de **grande taille** (plutôt fin de journée, soirée et nuit suivante) en partant d'une **accumulation constituée en altitude**.

Autres : retour rapide de conditions **très hivernales et surprenantes** par rapport à la veille, avec de **très mauvaises visibilités** et des **températures froides**, **accentuées par le vent** de nord-ouest à nord.

Qualité de la neige

Enneigement : avec le retour de ce temps hivernal, l'enneigement devient bon pour la saison, surtout au-dessus de 1400/1500m, mais reste assez maigre en versants exposés au vent d'Ouest et en versants Sud. Saupoudrage au petit matin dès 800m, jusqu'à 700m en cours de journée, épaisseur voisine de 10 cm dans la journée vers 1000m.
Limites skiables : à basse altitude, dès 1200m ce samedi matin, mais sans sous-couche en dessous de 1600m en versants froids, 1900m en versants Sud.
État de la neige : neige froide, sèche et meuble gagnant en épaisseur au fil des heures, posée sur un manteau ressaisi à regelé. Neige plus ou moins travaillée par le vent au cours de la journée, frittée à cartonnée près des crêtes, cols et sommets, restant meuble à l'abri du vent (clairières et combes déventées notamment).

Aperçu météo pour le samedi 14 mars

Chutes de neige, vent de nord-ouest à nord, froid.

	nuit	matin	après-midi	soir
Pluie-Neige	1 000 m	800 m	700 m	700 m
Iso 0 °C	1 300 m	1 200 m	1 100 m	1 100 m
Vent 1500 m	↘ 25 km/h	↘ 25 km/h	↘ 30 km/h	↓ 35 km/h
Vent 3000 m	↘ 55 km/h	↘ 60 km/h	↘ 70 km/h	↓ 80 km/h

Pour consulter la vigilance en cours, veuillez vous rendre sur le site https://vigilance.meteofrance.fr/fr

Météo-France - 73 avenue de Paris, 94165 Saint-Mandé cedex - Contact : contact@meteo.fr

Rédigé par Météo-France avec la contribution des observateurs du réseau nivo-météorologiques. Partenariat : ANMSM (Maires de Stations de Montagne), DSF (Domaines Skiables de France), ADSP (Directeurs de Pistes et de la Sécurité des Stations de Sports d'Hiver) et autres acteurs de la montagne.

Bulletin neige & avalanches par téléphone au
0 892 68 10 20 Service 0,35 € / min + prix appel

Bulletin d'estimation du risque d'avalanche

(valable en dehors des pistes balisées et ouvertes)

MASSIF : Aure Louron

Rédigé le vendredi 13 mars 2026 à 16h

Épaisseur de neige hors-piste

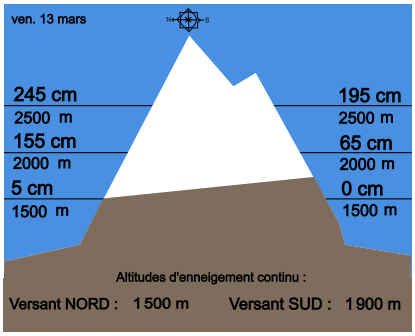

Précipitations à 1800 m

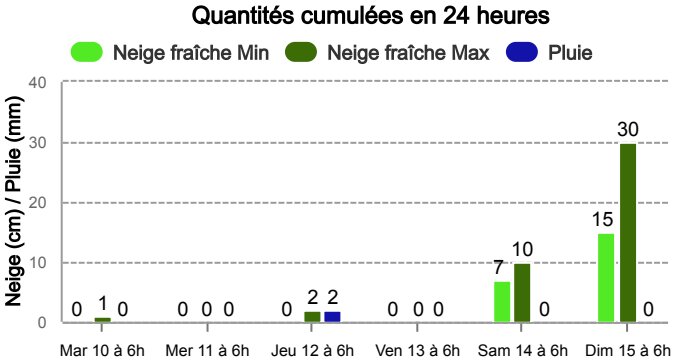

Tendance du dimanche 15 mars

Indice de risque marqué

Maintien du risque marqué pour les déclenchements provoqués, le risque de départs spontanés deviendra lui aussi marqué, fonction des cumuls de neige attendus sur l'ensemble de cet épisode hivernal.

Pour consulter la vigilance en cours, veuillez vous rendre sur le site https://vigilance.meteofrance.fr/fr

Météo-France - 73 avenue de Paris, 94165 Saint-Mandé cedex - Contact : contact@meteo.fr

Rédigé par Météo-France avec la contribution des observateurs du réseau nivo-météorologiques. Partenariat : ANMSM (Maires de Stations de Montagne), DSF (Domaines Skiables de France), ADSP (Directeurs de Pistes et de la Sécurité des Stations de Sports d'Hiver) et autres acteurs de la montagne.

Bulletin neige & avalanches par téléphone au

0 892 68 10 20 Service 0,35 € / min + prix appel

RÉPUBLIQUE FRANÇAISE
Liberté Égalité Fraternité

METEO FRANCE
À VOS CÔTÉS, DANS UN CLIMAT QUI CHANGE

Bulletin d'estimation du risque d'avalanche

(valable en dehors des pistes balisées et ouvertes)

MASSIF : Aure Louron

Rédigé le vendredi 13 mars 2026 à 16h

Conditions nivo-météo des 7 derniers jours

	sam. 07/03				dim. 08/03				lun. 09/03				mar. 10/03				mer. 11/03				jeu. 12/03				ven. 13/03			
	03h	09h	15h	21h	03h	09h	15h	21h	03h	09h	15h	21h	03h	09h	15h	21h	03h	09h	15h	21h	03h	09h	15h	21h	03h	09h	15h	21h
Météo																												
Vent (km/h)	25	20	40	50	30	20	20	15	10	15	20	15	15	10	45	35	40	65	60	55	40	30	55	60	35	60	60	50
à 3000m																												
Vent (km/h)	10	15	10	10	10	5	5	5	2	5	5	5	5	5	15	10	20	15	15	5	10	5	15	10	10	20	20	25
à 1500m																												

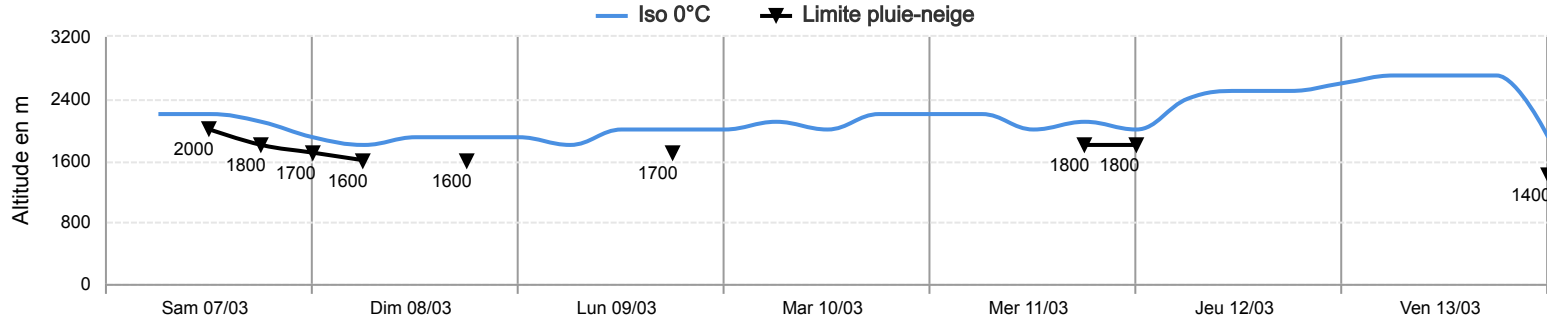

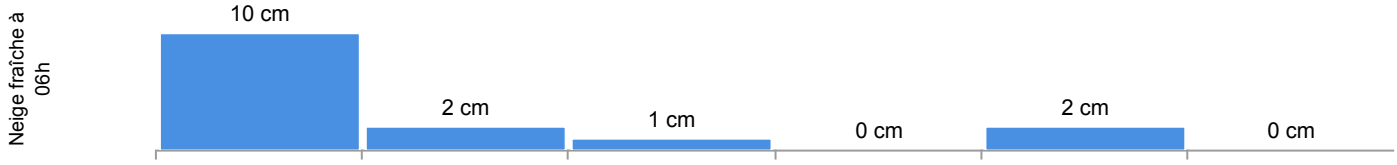

Risque d'avalanche	sam. 07/03	dim. 08/03	lun. 09/03	mar. 10/03	mer. 11/03	jeu. 12/03	ven. 13/03
	2	2	2	2	2	2	2

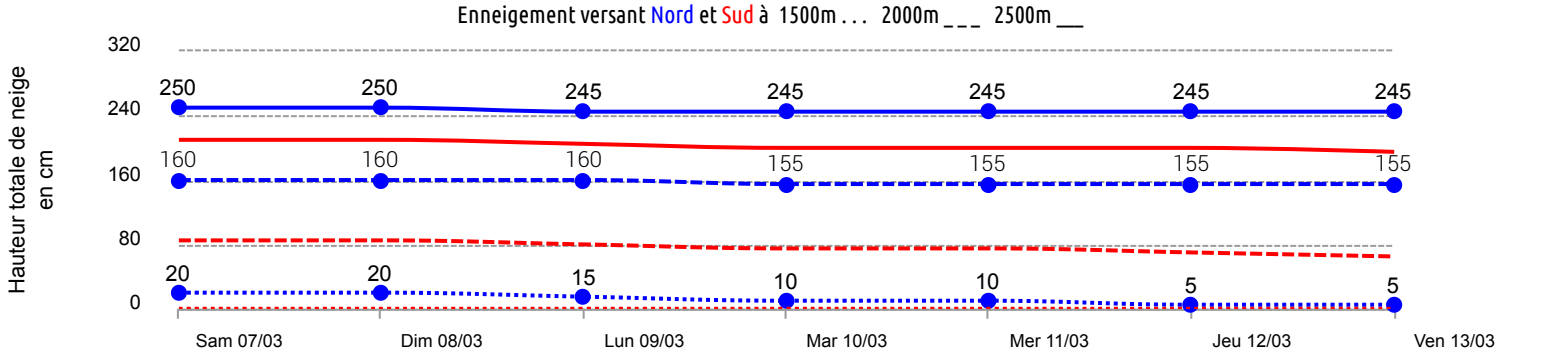

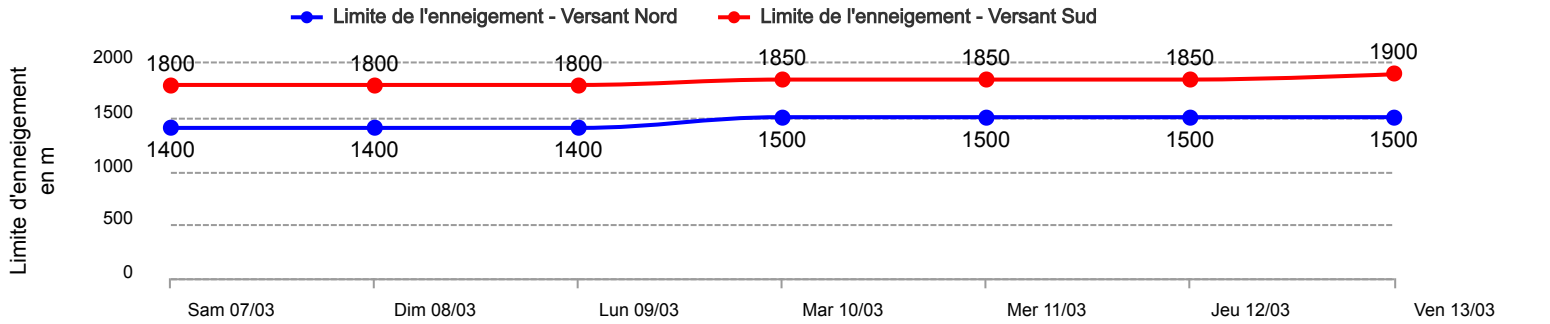

Pour consulter la vigilance en cours, veuillez vous rendre sur le site https://vigilance.meteofrance.fr/fr

Météo-France - 73 avenue de Paris, 94165 Saint-Mandé cedex - Contact : contact@meteo.fr

Rédigé par Météo-France avec la contribution des observateurs du réseau nivo-météorologiques. Partenariat : ANMSM (Maires de Stations de Montagne), DSF (Domaines Skiables de France), ADSP (Directeurs de Pistes et de la Sécurité des Stations de Sports d'Hiver) et autres acteurs de la montagne.

Bulletin neige & avalanches par téléphone au
0 892 68 10 20 Service 0,35 € / min + prix appel