Bulletin d'estimation du risque d'avalanche

(valable en dehors des pistes balisées et ouvertes)

MASSIF : Cerdagne Canigou

Rédigé le vendredi 13 mars 2026 à 16h

Estimation des risques pour le : SAMEDI 14 MARS

STRUCTURES DE PLAQUE EN COURS DE FORMATION AU FIL DES CHUTES DE NEIGE DE LA JOURNÉE DE SAMEDI

3

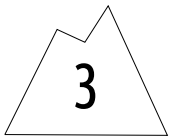

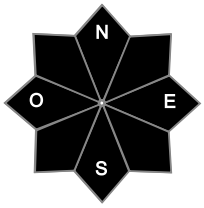

Indice de risque marqué.

Départs spontanés : Départs de plus en plus probables au fil des chutes

Déclenchements provoqués : Plaques de plus en plus nombreuses et épaisses

Indices de risque : 5 très fort - 4 fort - 3 marqué - 2 limité - 1 faible -- En noir : les pentes les plus dangereuses

Stabilité du manteau neigeux

Situation avalancheuse typique : neige fraîche

Déclenchements provoqués :
Dans de nombreuses pentes, plutôt dans les secteurs à l'abri du vent de nord-ouest mais pas seulement, des structures de plaque se forment au fil des chutes de neige de ce samedi et sont facilement déclenchables au passage d'un pratiquant. Elles engendrent des avalanches de taille moyenne avec cassure linéaire. En effet, des instabilités temporaires peuvent effectivement être présentes au sein des accumulations de neige fraîche, plutôt peu ventée dans un premier temps puis de plus en plus dense et cohésive par le travail du vent. Par ailleurs, il est possible que les nuits claires de cette semaine aient favorisé dans les secteurs ombragés d'altitude la formation de grains facettés en surface sur laquelle va reposer la couche de neige fraîche.

Départs spontanés : Au fil des chutes de neige de ce samedi, des départs spontanés de taille petite à moyenne se produisent dans les pentes raides par surcharge.

Qualité de la neige

Enneigement :
La montagne va retrouver un bel aspect hivernal ce samedi avec les chutes de neige qui se produisent à relativement basse altitude. L'enneigement est nettement excédentaire. On peut souvent trouver une sous-couche suffisante à partir de 1600/1900m.

Qualité de la neige :
La couche de neige fraîche va être hétérogène en altitude à cause du transport par le vent de secteur nord-ouest de plus en plus fort. La neige sera frittée au vent, mais légère en altitude dans les endroits déventés à la faveur du net refroidissement.

Aperçu météo pour le samedi 14 mars

	nuit	matin	après-midi	soir
	Net refroidissement; Chutes de neige, surtout en matinée			
Pluie-Neige	1 500 m	1 200 m	1 100 m	800 m
Iso 0 °C	1 800 m	1 600 m	1 400 m	1 100 m
Vent 2000 m	↘ 30 km/h	↘ 30 km/h	↘ 35 km/h	↘ 45 km/h
Vent 3000 m	↘ 50 km/h	↘ 50 km/h	↘ 55 km/h	↘ 70 km/h

Épaisseur de neige hors-piste

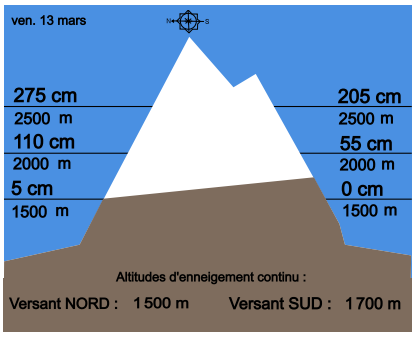

Précipitations à 1800 m

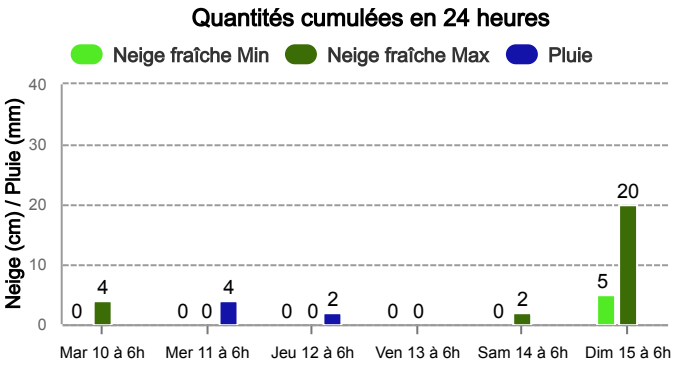

Tendance du dimanche 15 mars

3 **Indice de risque marqué**

Maintien d'un risque avalancheux marqué par la persistance d'un fort vent de nord dimanche

Pour consulter la vigilance en cours, veuillez vous rendre sur le site https://vigilance.meteofrance.fr/fr

Météo-France - 73 avenue de Paris, 94165 Saint-Mandé cedex - Contact : contact@meteo.fr

Rédigé par Météo-France avec la contribution des observateurs du réseau nivo-météorologiques. Partenariat : ANMSM (Maires de Stations de Montagne), DSF (Domaines Skiables de France), ADSP (Directeurs de Pistes et de la Sécurité des Stations de Sports d'Hiver) et autres acteurs de la montagne.

Bulletin neige & avalanches par téléphone au
0 892 68 10 20 Service 0,35 € / min + prix appel

RÉPUBLIQUE FRANÇAISE
Liberté Égalité Fraternité

METEO FRANCE
À VOS CÔTÉS, DANS UN CLIMAT QUI CHANGE

Bulletin d'estimation du risque d'avalanche

(valable en dehors des pistes balisées et ouvertes)

MASSIF : Cerdagne Canigou

Rédigé le vendredi 13 mars 2026 à 16h

Conditions nivo-météo des 7 derniers jours

	sam. 07/03				dim. 08/03				lun. 09/03				mar. 10/03				mer. 11/03				jeu. 12/03				ven. 13/03			
	03h	09h	15h	21h	03h	09h	15h	21h	03h	09h	15h	21h	03h	09h	15h	21h	03h	09h	15h	21h	03h	09h	15h	21h	03h	09h	15h	21h
Météo																												
Vent (km/h)	40	40	30	25	30	25	25	20	20	15	15	10	15	15	15	15	20	25	35	45	40	30	25	25	25	25	30	40
à 3000m	↑	↑	↑	↑	↑	↑	↑	↑	↑	↑	↑	↑	↗	↑	→	→	↑	→	→	↘	↘	↘	↘	↘	↓	→	→	↘
Vent (km/h)	25	30	20	15	20	20	15	10	10	10	10	5	10	10	10	5	10	10	15	25	30	20	15	15	15	15	15	25
à 2000m	↖	↖	↑	↑	↑	↑	↑	↑	↑	↑	↑	↑	↑	←	↖	←	↗	↗	↘	↘	↘	↘	↘	↙	↓	→	→	↘

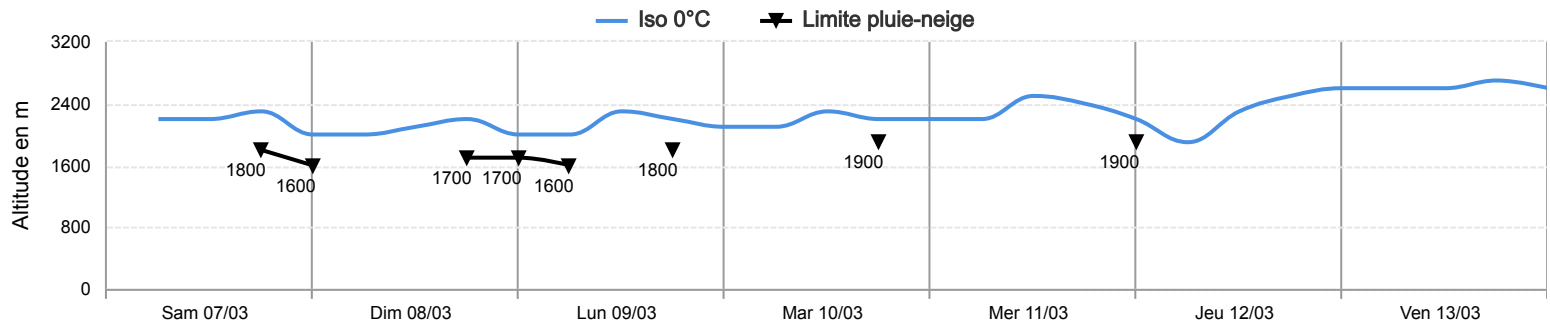

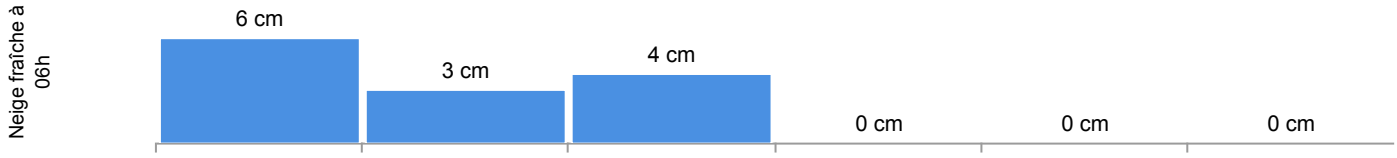

Risque d'avalanche	sam. 07/03	dim. 08/03	lun. 09/03	mar. 10/03	mer. 11/03	jeu. 12/03	ven. 13/03
	3	3	3	2	2	2	2

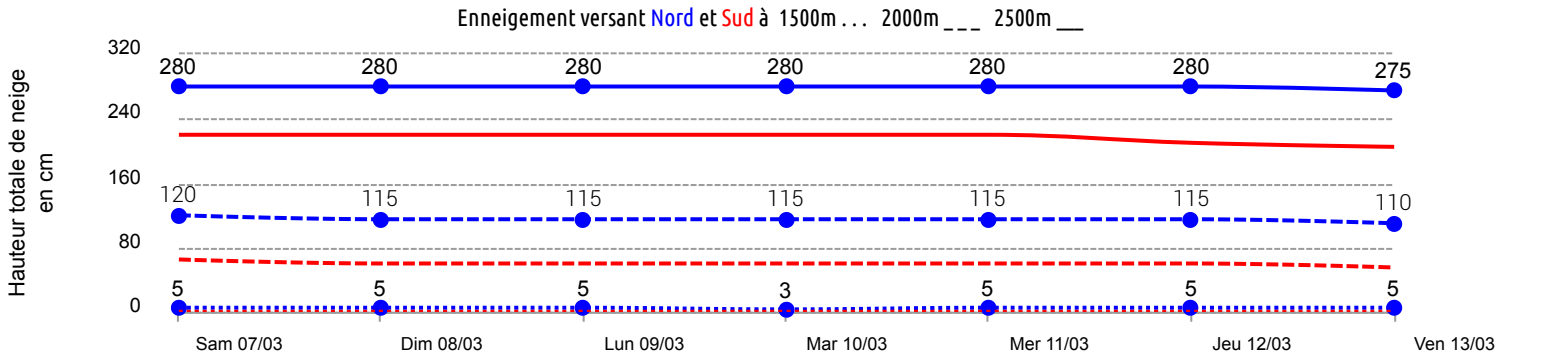

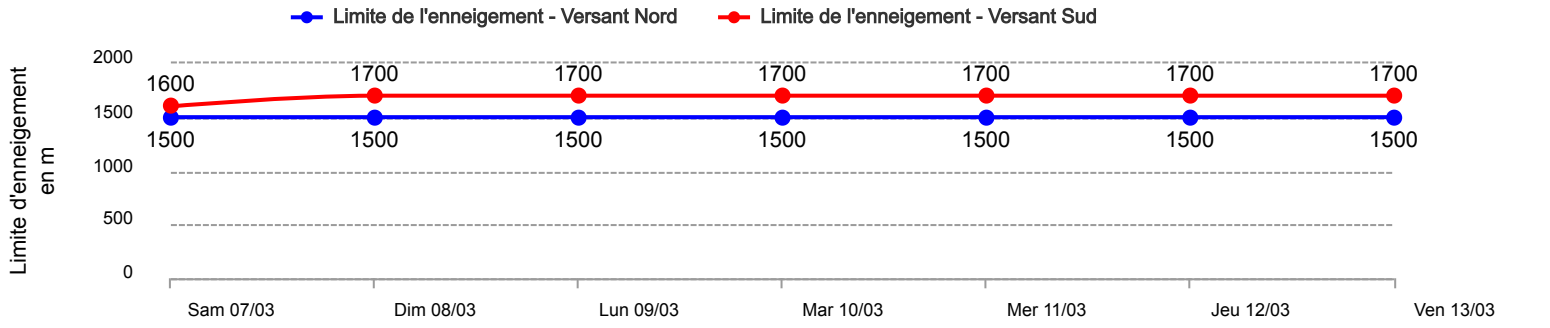

Pour consulter la vigilance en cours, veuillez vous rendre sur le site https://vigilance.meteofrance.fr/fr

Météo-France - 73 avenue de Paris, 94165 Saint-Mandé cedex - Contact : contact@meteo.fr

Rédigé par Météo-France avec la contribution des observateurs du réseau nivo-météorologiques. Partenariat : ANMSM (Maires de Stations de Montagne), DSF (Domaines Skiables de France), ADSP (Directeurs de Pistes et de la Sécurité des Stations de Sports d'Hiver) et autres acteurs de la montagne.

Bulletin neige & avalanches par téléphone au
0 892 68 10 20 Service 0,35 € / min + prix appel