RÉPUBLIQUE FRANÇAISE
*Liberté Égalité Fraternité*

METEO FRANCE
À VOS CÔTÉS, DANS UN CLIMAT QUI CHANGE

# Bulletin d'estimation du risque d'avalanche
## (valable en dehors des pistes balisées et ouvertes)

# MASSIF : Cinto Rotondo

Rédigé le vendredi 13 mars 2026 à 16h

## Estimation des risques pour le : SAMEDI 14 MARS

**DÉPARTS POSSIBLES EN NEIGE FRAÎCHE ET HUMIDE, PETITES INSTABILITÉS EN ALTITUDE**

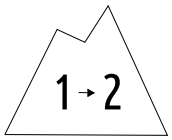


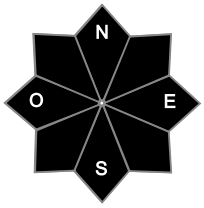


Indice de risque faible évoluant en limité.

**Départs spontanés :** Coulées et avalanches de neige fraîche et humide

**Déclenchements provoqués :** Petites plaques à vent en altitude, risque de départs ponctuels sous les skis en neige humide

Indices de risque : 5 très fort - 4 fort - 3 marqué - 2 limité - 1 faible -- En noir : les pentes les plus dangereuses

## Stabilité du manteau neigeux

**Situation avalancheuse typique :** neige fraîche neige humide

**Départs spontanés :** En dessous de 1800 m, des coulées de neige humide sont attendues surtout dans les pentes ensoleillées. Au-dessus de 1800 m, des coulées et avalanches de neige fraîche sont attendues durant les averses, essentiellement dans les pentes raides.
**Déclenchements provoqués :** des départs ponctuels sous les skis ou raquettes en neige humide peuvent se produire, notamment dans les pentes raides et ensoleillés (taille 1 à 2 suivant l'altitude). De petites plaques à vent formées dans les pentes orientées Ouest à Nord-ouest, au-dessus de 2000 m, sont à présent recouvertes par les nouvelles chutes de neige. Des déclenchement sont possibles surtout par forte surcharge, pouvant engendrer une coulée mobilisant peu de neige (taille 1).
**Autres :** Nombreuses surfaces glacées.

## Qualité de la neige

**Qualification de l'enneigement :** L'enneigement est excellent pour la saison au-dessus de 1600 m. Sur la Maniccia, à 2400 m d'altitude dans le massif du Rotondo, on relève plus de 3 mètres de hauteur de neige totale.
**Limite d'enneigement skiable :** 1500 à 1600 m selon le versant.
**État de la neige** : Le manteau neigeux est à présent tassé et bien consolidé. En dessous de 1800 m, la pluie a humidifié le manteau sur toute son épaisseur, la neige y est souvent lourde et humide. Au-dessus de 1800 à 2000 m, le refroidissement permet une consolidation par regel des couches de neige humide. Des croûtes épaisses se forment et des surfaces dures et glacées se généralisent parfois recouverte d'un peu de neige fraîche. on observe de nombreuses zones de neige colorée avec les dernières remontées de sable. À noter également la présence de corniches parfois volumineuses.

## Aperçu météo pour le samedi 14 mars

| | nuit | matin | après-midi | soir |
|---|---|---|---|---|
| Pluie-Neige | | | 1 700 m | 1 500 m |
| Iso 0 °C | 2 300 m | 2 200 m | 2 100 m | 1 900 m |
| Vent 1500 m | 10 km/h | 25 km/h | 50 km/h | 35 km/h |
| Vent 3000 m | 10 km/h | 30 km/h | 65 km/h | 45 km/h |

## Épaisseur de neige hors-piste

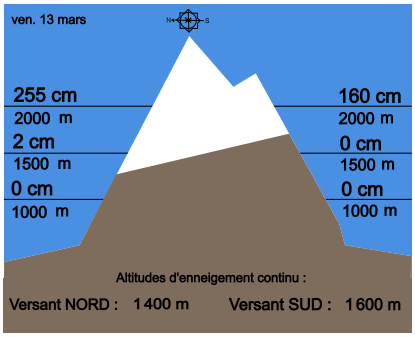


## Précipitations à 1800 m

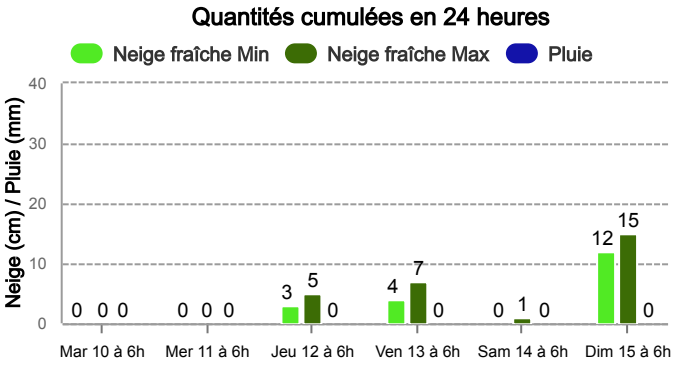


## Tendance du dimanche 15 mars

**Indice de risque limité**

Pas d'évolution notable en termes de risque.

Pour consulter la vigilance en cours, veuillez vous rendre sur le site https://vigilance.meteofrance.fr/fr

Météo-France - 73 avenue de Paris, 94165 Saint-Mandé cedex - Contact : contact@meteo.fr

Rédigé par Météo-France avec la contribution des observateurs du réseau nivo-météorologiques. Partenariat : ANMSM (Maires de Stations de Montagne), DSF (Domaines Skiables de France), ADSP (Directeurs de Pistes et de la Sécurité des Stations de Sports d'Hiver) et autres acteurs de la montagne.

Bulletin neige & avalanches par téléphone au
**0 892 68 10 20** Service 0,35 € / min + prix appel

RÉPUBLIQUE FRANÇAISE
*Liberté Égalité Fraternité*

METEO FRANCE
À VOS CÔTÉS, DANS UN CLIMAT QUI CHANGE

# Bulletin d'estimation du risque d'avalanche

## (valable en dehors des pistes balisées et ouvertes)

# MASSIF : Cinto Rotondo

Rédigé le vendredi 13 mars 2026 à 16h

## Conditions nivo-météo des 7 derniers jours

| | sam. 07/03 | | | | dim. 08/03 | | | | lun. 09/03 | | | | mar. 10/03 | | | | mer. 11/03 | | | | jeu. 12/03 | | | | ven. 13/03 | | | |
|---|---|---|---|---|---|---|---|---|---|---|---|---|---|---|---|---|---|---|---|---|---|---|---|---|---|---|---|---|
| | 03h | 09h | 15h | 21h | 03h | 09h | 15h | 21h | 03h | 09h | 15h | 21h | 03h | 09h | 15h | 21h | 03h | 09h | 15h | 21h | 03h | 09h | 15h | 21h | 03h | 09h | 15h | 21h |
| Météo | | | | | | | | | | | | | | | | | | | | | | | | | | | | |
| Vent (km/h) | 30 | 30 | 20 | 15 | 15 | 10 | 15 | 10 | 10 | 10 | 15 | 25 | 20 | 40 | 30 | 20 | 20 | 30 | 40 | 40 | 30 | 30 | 30 | 20 | 20 | 10 | 10 | 5 |
| à 3000m | | | | | | | | | | | | | | | | | | | | | | | | | | | | |
| Vent (km/h) | 20 | 20 | 10 | 10 | 10 | 5 | 10 | 0 | 5 | 5 | 10 | 15 | 15 | 20 | 20 | 10 | 15 | 20 | 25 | 30 | 20 | 10 | 20 | 15 | 15 | 15 | 15 | 5 |
| à 1500m | | | | | | | | | | | | | | | | | | | | | | | | | | | | |

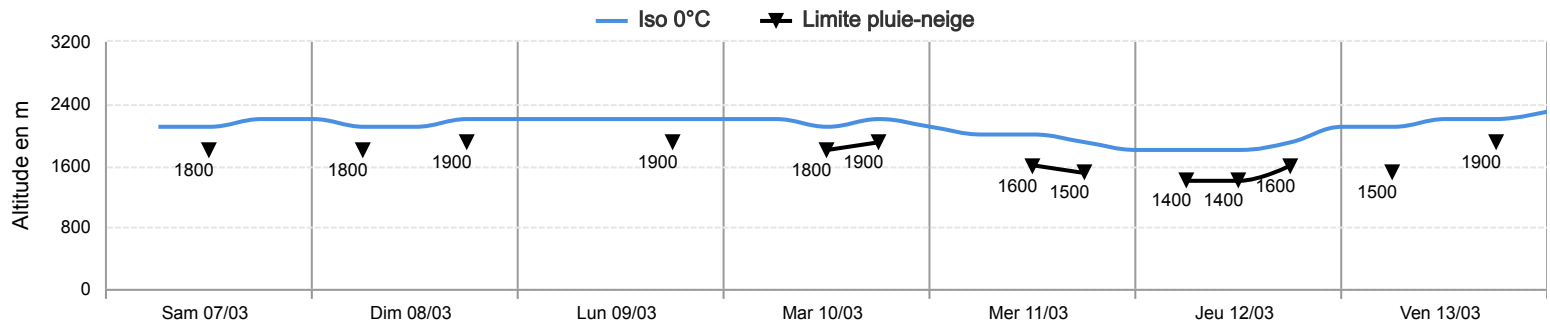


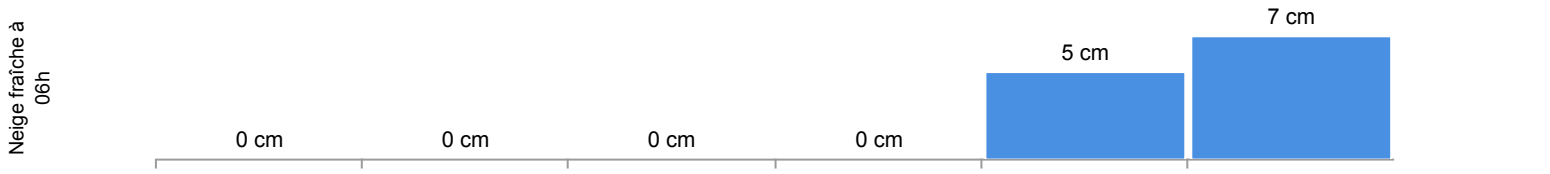


| Risque d'avalanche | sam. 07/03 | dim. 08/03 | lun. 09/03 | mar. 10/03 | mer. 11/03 | jeu. 12/03 | ven. 13/03 |
|---|---|---|---|---|---|---|---|
| | 2 | 1 | 1 | 1 | 1 | 1 | 1 |

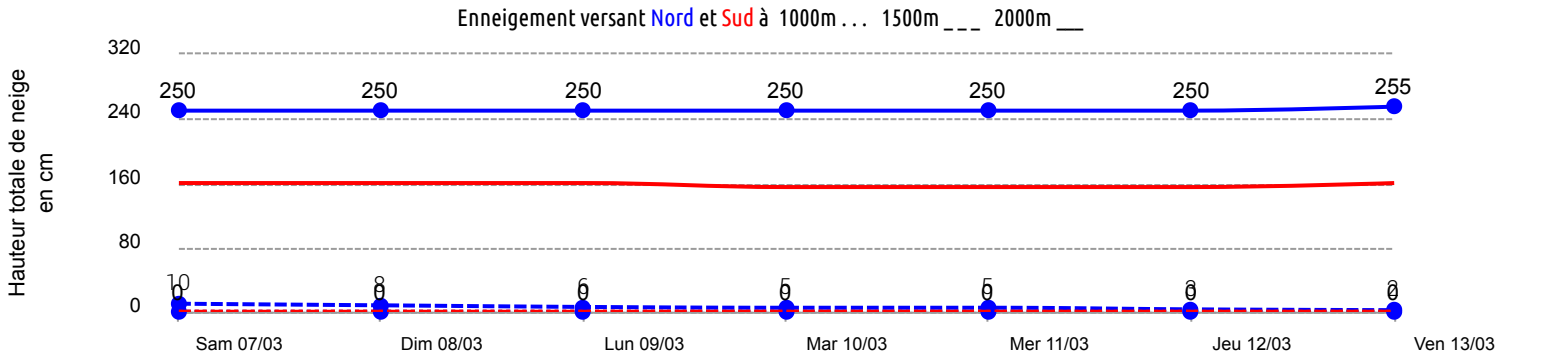


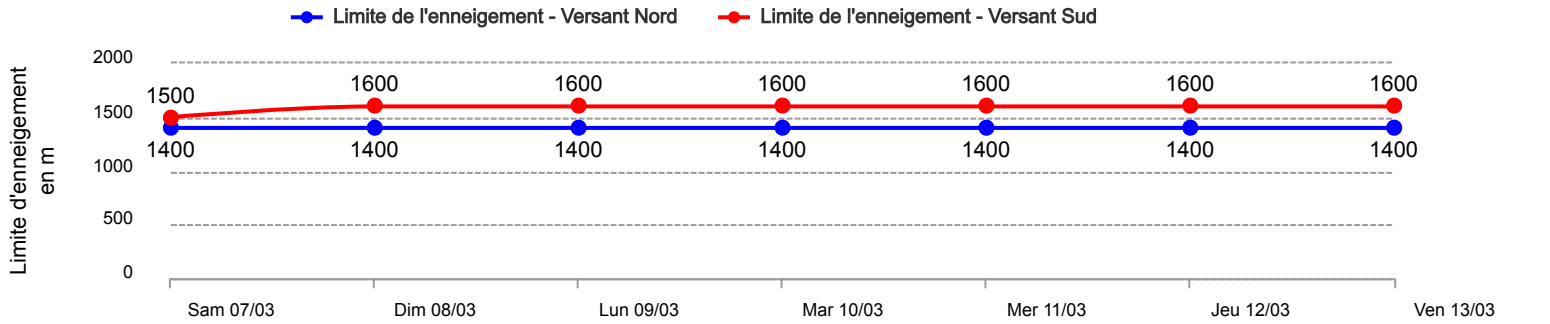


Pour consulter la vigilance en cours, veuillez vous rendre sur le site https://vigilance.meteofrance.fr/fr


**Météo-France - 73 avenue de Paris, 94165 Saint-Mandé cedex - Contact : contact@meteo.fr**



Rédigé par Météo-France avec la contribution des observateurs du réseau nivo-météorologiques. Partenariat : ANMSM (Maires de Stations de Montagne), DSF (Domaines Skiables de France), ADSP (Directeurs de Pistes et de la Sécurité des Stations de Sports d'Hiver) et autres acteurs de la montagne.



Bulletin neige & avalanches par téléphone au
0 892 68 10 20 Service 0,35 € / min + prix appel