Bulletin d'estimation du risque d'avalanche
(valable en dehors des pistes balisées et ouvertes)

MASSIF : Haut-Var Haut-Verdon

Rédigé le vendredi 13 mars 2026 à 16h

Estimation des risques pour le : SAMEDI 14 MARS

INSTABILITÉ EN HAUSSE DANS LA NEIGE FRAICHE. DÉPARTS ET DÉCLENCHEMENTS PLUS NOMBREUX ET VOLUMINEUX EN UBACS D'ALTITUDE

3

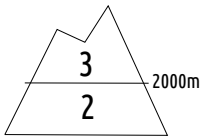

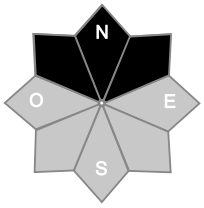

+nombreuses/épaisses

Au-dessus de 2000m indice de risque marqué, plus bas indice limité.

Départs spontanés : départs ponctuels en neige fraiche devenant nombreux en cours de journée de samedi + possibles avalanches de plaque

Déclenchements provoqués : avalanches de plaque devenant plus nombreuses samedi, facile à déclencher

Indices de risque : 5 très fort - 4 fort - 3 marqué - 2 limité - 1 faible -- En noir : les pentes les plus dangereuses

Stabilité du manteau neigeux

Situation avalancheuse typique : neige fraîche couche fragile persistante

Déclenchements provoqués :
- quelques plaques dans la neige récente ventée, essentiellement en ubac au-dessus de 2000/2200 m. Ces instabilités peuvent être déclenchées au passage d'un skieur, mais sont en général de petite taille, plus rarement moyenne.
- **Samedi, nouvelles plaques en formation**, conséquences des chutes de neige ventées. Possibles dans de multiples pentes, mais plus nombreuses et volumineuses dès 2000 m environ notamment dans les orientations nord-est / nord / nord-ouest (où avant la chute, on retrouve de la neige récente encore poudreuse faisant office de couche fragile). Toutes ces instabilités sont facilement déclenchables et peuvent être d'aspect poudreux. Avalanches de plaque de taille petite à moyenne. Plus rarement grande en ubac d'altitude, aussi par la sollicitation en cascade d'une plaque ancienne plus enfouie reposant sur des couches fragiles persistantes.

Départs spontanés :
- Jusqu'en fin de nuit de vendredi à samedi, peu probables.
- **Samedi, avalanches de neige fraîche** devenant plus nombreuses et volumineuses au fil des chutes dans les pentes raides. Taille petite à moyenne, le plus souvent en départ ponctuel. Grande avalanche possible en orientation de large nord d'altitude plus chargée, rupture linéaire.

Qualité de la neige

Enneigement plutôt excédentaire sur le Haut-Verdon, dans les normales pour le Haut Var.
Données observées : vers 2000 m, 172 cm en fond de vallon dans le Haut Verdon, 115 cm dans le Haut Var.

Enneigement skiable : vers 1400/1500 m en ubacs, 1800/1900 m en adrets peu pentus.

État de la neige en surface : neige fraiche en quantité attendue ce samedi en journée se déposant sur de la neige récente poudreuse ou densifiée par le vent en ubacs au-dessus de 2000/2200 m, croutée en dessous ainsi que dans les adrets. Sur les crêtes, d'anciennes corniches épaisses côtoient des zones dégarnies.

Aperçu météo pour le samedi 14 mars

	nuit	matin	après-midi	soir

Retour de l'hiver ! Chutes de neige d'intensité modérée à forte en matinée, faiblissant ensuite.
Cumuls d'ici la fin de journée de samedi : 15/25 cm

Pluie-Neige		1 100 m	1 300 m	1 000 m
Iso 0 °C	1 800 m	1 600 m	1 700 m	1 400 m
Vent 2000 m	↑ 15 km/h	↗ 25 km/h	↘ 20 km/h	↓ 15 km/h
Vent 3000 m	↖ 40 km/h	↑ 40 km/h	↑ 25 km/h	← 20 km/h

Épaisseur de neige hors-piste

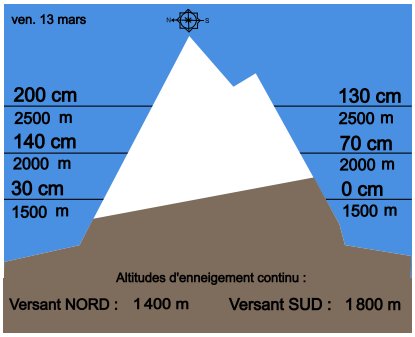

Précipitations à 1800 m

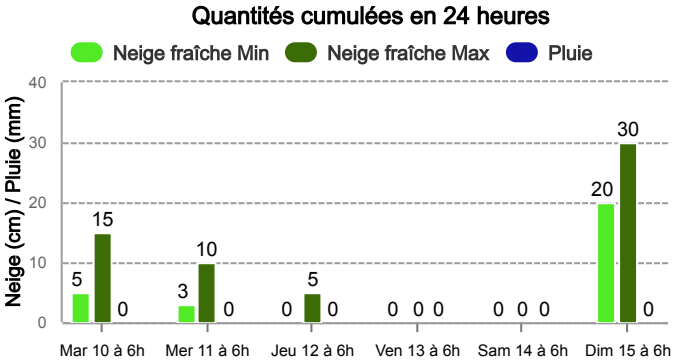

Tendance du dimanche 15 mars

3 **Indice de risque marqué**

Maintien d'un risque marqué. Nouvelles plaques avec encore un peu de neige et le transport de la neige par le fort vent d'est + activité naturelle dont retour d'éclaircies.

Pour consulter la vigilance en cours, veuillez vous rendre sur le site https://vigilance.meteofrance.fr/fr

Météo-France - 73 avenue de Paris, 94165 Saint-Mandé cedex - Contact : contact@meteo.fr

Rédigé par Météo-France avec la contribution des observateurs du réseau nivo-météorologiques. Partenariat : ANMSM (Maires de Stations de Montagne), DSF (Domaines Skiables de France), ADSP (Directeurs de Pistes et de la Sécurité des Stations de Sports d'Hiver) et autres acteurs de la montagne.

Bulletin neige & avalanches par téléphone au
0 892 68 10 20 Service 0,35 € / min + prix appel

RÉPUBLIQUE FRANÇAISE
Liberté Égalité Fraternité

METEO FRANCE
À VOS CÔTÉS, DANS UN CLIMAT QUI CHANGE

Bulletin d'estimation du risque d'avalanche

(valable en dehors des pistes balisées et ouvertes)

MASSIF : Haut-Var Haut-Verdon

Rédigé le vendredi 13 mars 2026 à 16h

Conditions nivo-météo des 7 derniers jours

	sam. 07/03				dim. 08/03				lun. 09/03				mar. 10/03				mer. 11/03				jeu. 12/03				ven. 13/03			
	03h	09h	15h	21h	03h	09h	15h	21h	03h	09h	15h	21h	03h	09h	15h	21h	03h	09h	15h	21h	03h	09h	15h	21h	03h	09h	15h	21h
Météo																												
Vent (km/h)	35	30	25	15	20	15	15	15	15	20	30	50	40	25	20	20	15	30	45	40	40	30	20	20	20	10	15	15
à 3000m	←	←	↖	←	↖	↖	↖	↖	↑	↑	↖	↖	↑	↑	↑	↗	↗	→	→	↘	↓	↓	↓	↓	↓	↘	↗	↑
Vent (km/h)	25	20	15	10	15	10	15	10	15	15	20	35	5	15	20	5	5	10	20	15	25	25	20	10	10	5	15	10
à 2000m	←	↖	←	←	←	↖	↖	←	←	↖	↖	←	↓	↑	↑	↑	↑	→	→	↘	↘	↓	↙	↻	↓	→	↑	↑

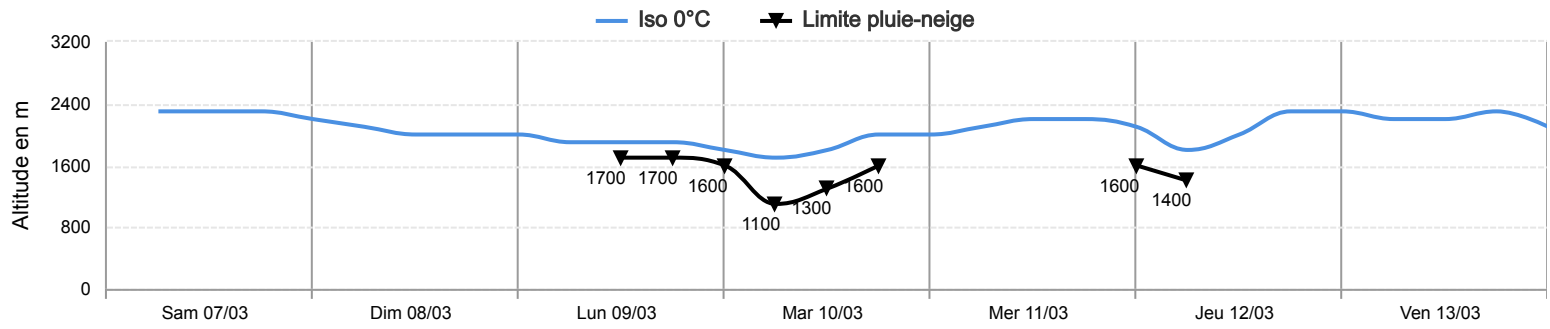

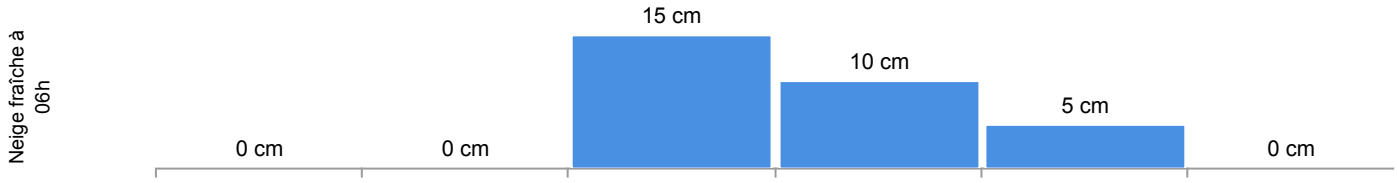

Risque d'avalanche	sam. 07/03	dim. 08/03	lun. 09/03	mar. 10/03	mer. 11/03	jeu. 12/03	ven. 13/03
	2	2	1	2	2	2	2

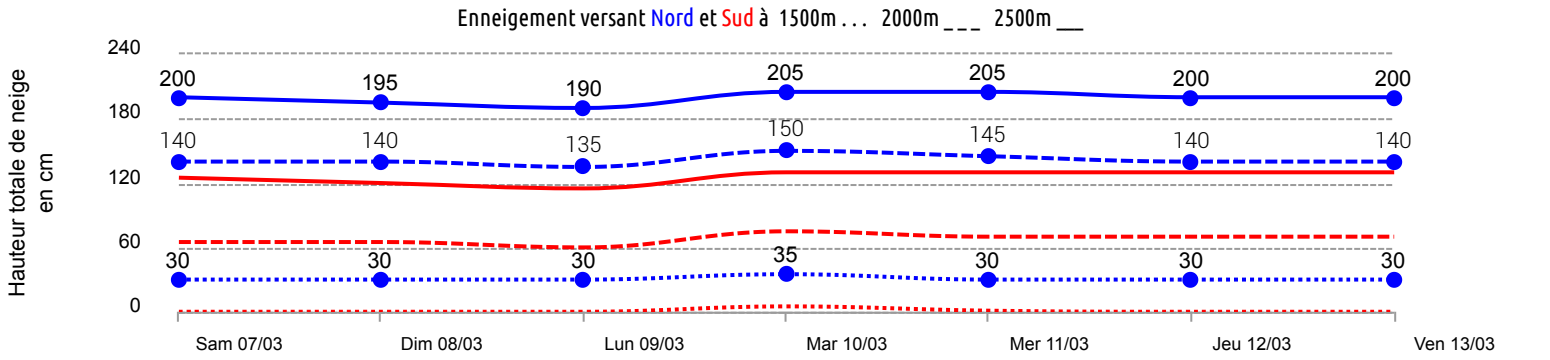

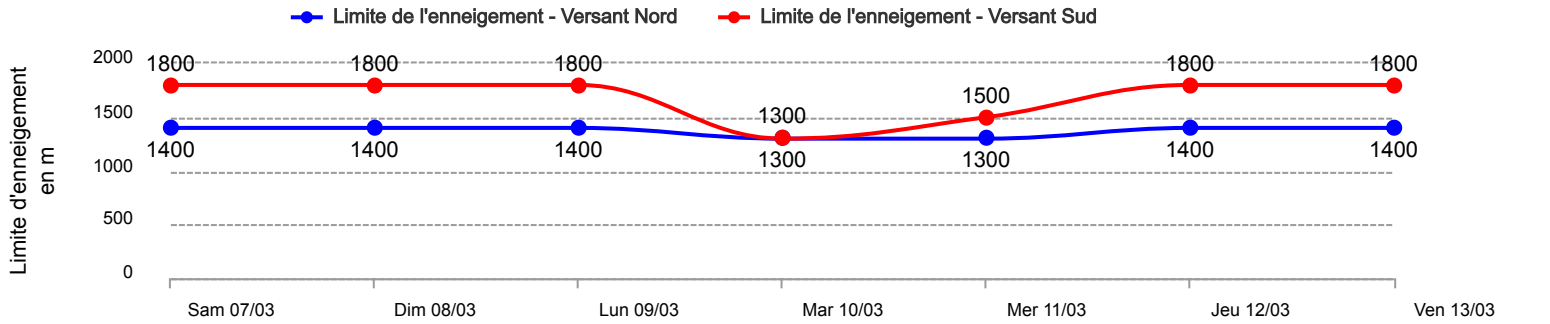

Pour consulter la vigilance en cours, veuillez vous rendre sur le site https://vigilance.meteofrance.fr/fr

Météo-France - 73 avenue de Paris, 94165 Saint-Mandé cedex - Contact : contact@meteo.fr

Rédigé par Météo-France avec la contribution des observateurs du réseau nivo-météorologiques. Partenariat : ANMSM (Maires de Stations de Montagne), DSF (Domaines Skiables de France), ADSP (Directeurs de Pistes et de la Sécurité des Stations de Sports d'Hiver) et autres acteurs de la montagne.

Bulletin neige & avalanches par téléphone au

0 892 68 10 20 Service 0,35 € / min + prix appel