Bulletin d'estimation du risque d'avalanche
(valable en dehors des pistes balisées et ouvertes)

MASSIF : Haute-Tarentaise

Rédigé le vendredi 13 mars 2026 à 16h

Estimation des risques pour le : SAMEDI 14 MARS

CHUTE DE NEIGE EN COURS : NOUVELLES INSTABILITÉS DE PLUS EN PLUS RÉACTIVES.

3

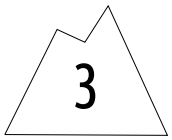

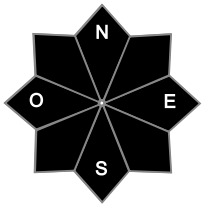

Indice de risque marqué.

Départs spontanés : au cours de chutes, puis avec le vent.

Déclenchements provoqués : quelques plaques réactives d'aspect poudreux.

Indices de risque : 5 très fort - 4 fort - 3 marqué - 2 limité - 1 faible -- En noir : les pentes les plus dangereuses

Stabilité du manteau neigeux

Situation avalancheuse typique : neige fraîche couche fragile persistante

Déclenchement provoqués : **quelques plaques de neige friable facilement déclenchables**. Elles sont de **plus en plus nombreuses et épaisses au fil des heures**. Elles sont plus réactives en ubac où la neige était restée poudreuse (grains parfois anguleux), mais également en toute orientation en fin d'après-midi avec le renforcement du vent. Avalanche de taille petite à moyenne le matin, moyenne à rarement grande l'après-midi, surtout en ubac d'altitude. Cassures de 30 à 60 cm.
Au-dessus de 2400 m en ubac, plus haut en adret, près des crêtes ou des croupes dégarnies (là où d'anciennes couches fragiles persistantes sont moins profondément enfouie) une grande avalanche est possible. Cassure pouvant dépasser 1 m.

Départs spontanés : Quelques petits départs dans les pentes raides au cours des chutes (départs ponctuels), puis à nouveau en fin d'après-midi avec le renforcement du vent (départs linéaires). Petites à moyennes avalanches. Exceptionnellement une grande avalanche en cas de départ en cascade sur la couche fragile persistante en altitude et en versants froids.

Qualité de la neige

Enneigement : en général légèrement excédentaire pour la saison, mais en train de devenir déficitaire en basse montagne et en versant sud.

Limite skiable : encore skiable dès 1100/1200 m dans les prairies orientées nord, plutôt 1500/1600 m en sud pas trop raide.

Qualité de la neige : couche de neige fraîche peu ventée s'épaississant en cours de journée. La sous-couche est dure ou croutée en adret mais elle sera de moins en moins perceptible au fil des heures. En fin d'après-midi, le vent modéré de nord-ouest densifie un peu la neige.

Aperçu météo pour le samedi 14 mars

	nuit	matin	après-midi	soir
Chutes de neige modérées à temporairement fortes le matin jusqu'en milieu d'après midi.				
Pluie-Neige	1 300 m	1 200 m	1 000 m	700 m
Iso 0 °C	2 100 m	1 800 m	1 500 m	1 000 m
Vent 2500 m	↘ 30 km/h	↘ 20 km/h	↘ 15 km/h	← 20 km/h
Vent 3500 m	↘ 50 km/h	↘ 35 km/h	↘ 30 km/h	← 35 km/h

Épaisseur de neige hors-piste

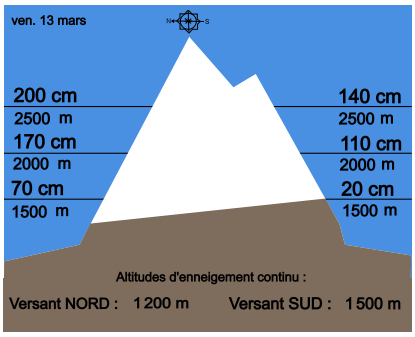

Précipitations à 1800 m

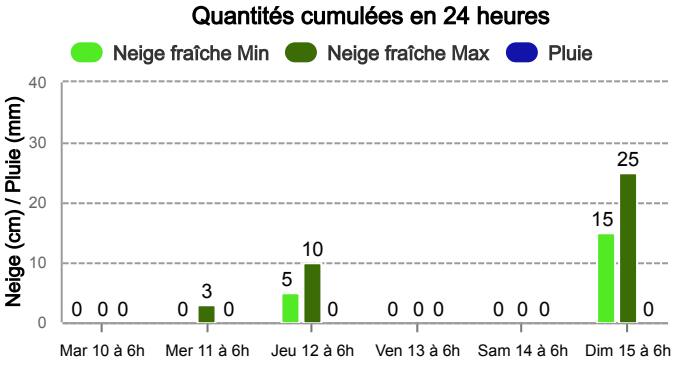

Tendance du dimanche 15 mars

3

Indice de risque marqué

Le vent alimente les instabilités. Risque restant marqué.

Pour consulter la vigilance en cours, veuillez vous rendre sur le site https://vigilance.meteofrance.fr/fr

Météo-France - 73 avenue de Paris, 94165 Saint-Mandé cedex - Contact : contact@meteo.fr

Rédigé par Météo-France avec la contribution des observateurs du réseau nivo-météorologiques. Partenariat : ANMSM (Maires de Stations de Montagne), DSF (Domaines Skiables de France), ADSP (Directeurs de Pistes et de la Sécurité des Stations de Sports d'Hiver) et autres acteurs de la montagne.

Bulletin neige & avalanches par téléphone au 0 892 68 10 20 Service 0,35 € / min + prix appel

RÉPUBLIQUE FRANÇAISE
Liberté Égalité Fraternité

METEO FRANCE
À VOS CÔTÉS, DANS UN CLIMAT QUI CHANGE

Bulletin d'estimation du risque d'avalanche

(valable en dehors des pistes balisées et ouvertes)

MASSIF : Haute-Tarentaise

Rédigé le vendredi 13 mars 2026 à 16h

Conditions nivo-météo des 7 derniers jours

	sam. 07/03				dim. 08/03				lun. 09/03				mar. 10/03				mer. 11/03				jeu. 12/03				ven. 13/03			
	03h	09h	15h	21h	03h	09h	15h	21h	03h	09h	15h	21h	03h	09h	15h	21h	03h	09h	15h	21h	03h	09h	15h	21h	03h	09h	15h	21h
Météo																												
Vent (km/h)	20	20	25	25	20	20	20	20	20	20	20	30	40	40	30	30	20	25	35	50	45	30	30	25	20	25	35	65
à 3500m																												
Vent (km/h)	25	25	20	15	20	15	15	15	15	15	20	40	25	20	10	5	10	10	25	40	30	15	15	10	10	15	20	45
à 2500m																												

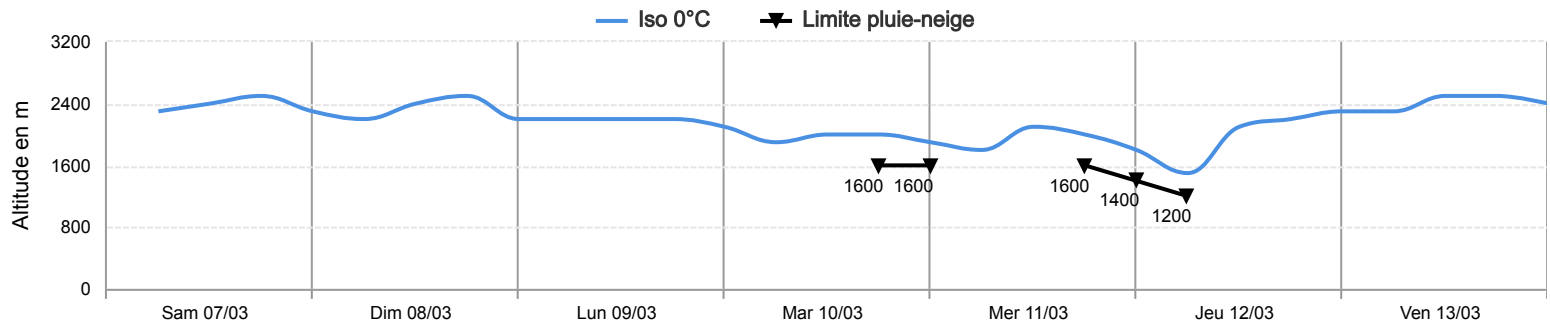

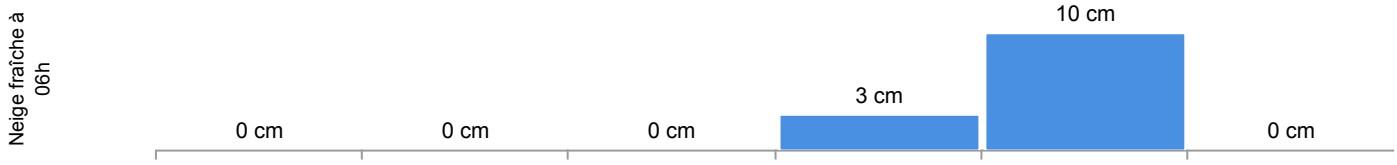

Risque d'avalanche	sam. 07/03	dim. 08/03	lun. 09/03	mar. 10/03	mer. 11/03	jeu. 12/03	ven. 13/03
	2	2	2	2	2	2	2

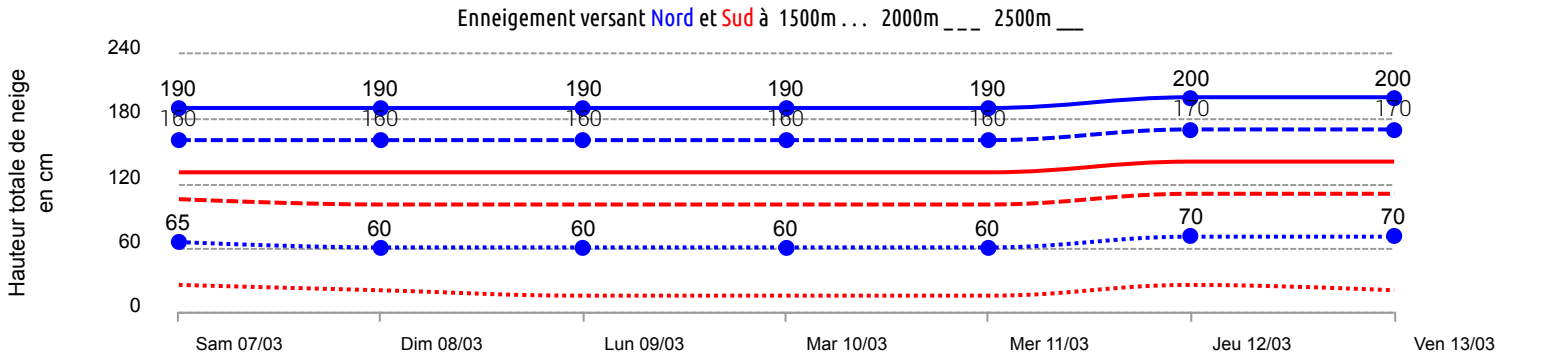

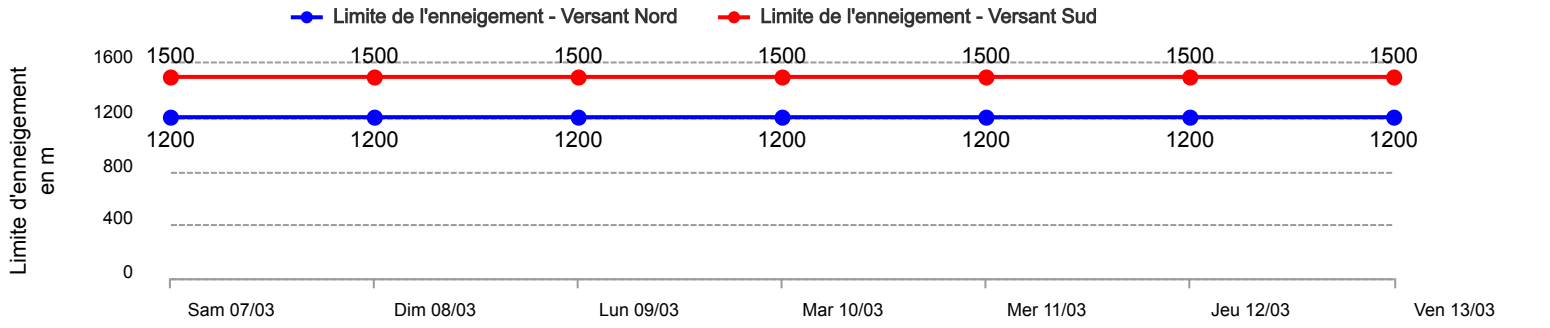

Pour consulter la vigilance en cours, veuillez vous rendre sur le site https://vigilance.meteofrance.fr/fr

Météo-France - 73 avenue de Paris, 94165 Saint-Mandé cedex - Contact : contact@meteo.fr

Rédigé par Météo-France avec la contribution des observateurs du réseau nivo-météorologiques. Partenariat : ANMSM (Maires de Stations de Montagne), DSF (Domaines Skiables de France), ADSP (Directeurs de Pistes et de la Sécurité des Stations de Sports d'Hiver) et autres acteurs de la montagne.

Bulletin neige & avalanches par téléphone au

0 892 68 10 20 Service 0,35 € / min + prix appel