Bulletin d'estimation du risque d'avalanche

(valable en dehors des pistes balisées et ouvertes)

MASSIF : Vercors

Rédigé le vendredi 13 mars 2026 à 16h

Estimation des risques pour le : SAMEDI 14 MARS

INSTABILITES DANS LA NEIGE RECENTE, DE PLUS EN PLUS REACTIVES AU FIL DE LA JOURNEE. QUELQUES DEPARTS SPONTANES SOUS LES CHUTES DE NEIGE

3

2 → 3

N O E S

Indice de risque limité évoluant en marqué.

Départs spontanés : Quelques départs en neige fraîche sous les chutes de neige en matinée

Déclenchements provoqués : Instabilités dans la neige fraîche, devenant plus nombreuses et réactives avec le renforcement du vent en journée

Indices de risque : 5 très fort - 4 fort - 3 marqué - 2 limité - 1 faible -- En noir : les pentes les plus dangereuses

Stabilité du manteau neigeux

Situation avalancheuse typique : neige fraîche — neige ventée

Déclenchements provoqués : En faces Nord sommitales, de rares fines plaques peuvent se former sous le vent de Sud / Sud-Ouest dans la nuit de samedi à dimanche. Samedi matin, une perturbation apporte 20 à 30cm de neige fraîche sur le haut du massif. Cette neige se dépose avec peu de vent, et repose sur un manteau généralement sain (hormis là où de petites plaques se sont formées dans la nuit). De petites instabilités seront toutefois présentes là où ces chutes s'accompagnent d'un léger vent de Nord-Ouest, à priori surtout vers les crêtes. En revanche, le vent se lève en journée et le manteau deviendra alors rapidement instable, avec la formation de nouvelles plaques très réactives et difficilement identifiables.

Observables : Transport en cours, neige densifiée par le vent en surface, fissures devant les skis.

Départs spontanés : Quelques avalanches de petites tailles ou de tailles moyennes peuvent partir spontanément sous les chutes de neige en matinée de samedi. Le risque deviendra nettement moins marqué l'après-midi avec l'afaiblissement des chutes de neige .

Qualité de la neige

Qualification de l'enneigement : L'enneigement est bon pour la saison en versants ombragés au dessus de 1300 m. Il est correct en Sud mais les sous-couches sont rares sous 1700 / 1800m.

Limites skiables : Vers 1100/1500m hors sapins.

Qualité de la neige samedi : Fortes chutes de neige samedi matin, donnant 10cm de neige fraîche dés 1000m, 15cm vers 1500m, et 20 à 30cm sur le haut du massif. Neige légère, peu ventée, s'alourdissant un peu l'après-midi dans les nuages.

Aperçu météo pour le samedi 14 mars

	nuit	matin	après-midi	soir
	Fortes chutes de neige en matinée. Flocons devenant plus rare l'après-midi, sous un ciel toujours très nuageux.			
Pluie-Neige	1 400 m	900 m	1 000 m	
Iso 0 °C	2 300 m	1 400 m	1 300 m	1 100 m
Vent 1500 m	↑ 45 km/h	↓ 20 km/h	↓ 30 km/h	↓ 45 km/h
Vent 2000 m	↗ 65 km/h	↘ 25 km/h	↓ 40 km/h	↻ 55 km/h

Épaisseur de neige hors-piste

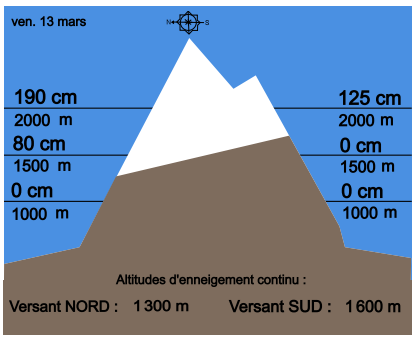

Précipitations à 1800 m

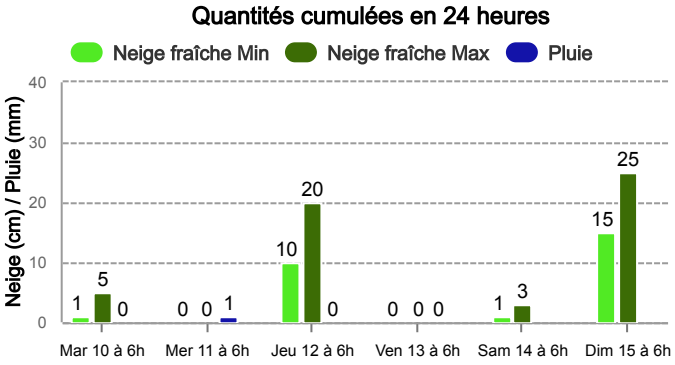

Tendance du dimanche 15 mars

3

Indice de risque marqué

Dimanche, risque marqué. Le vent de Nord souffle fort dans la nuit de samedi à dimanche, et forme de nombreuses nouvelles plaques dans la neige récente.

Pour consulter la vigilance en cours, veuillez vous rendre sur le site https://vigilance.meteofrance.fr/fr

Météo-France - 73 avenue de Paris, 94165 Saint-Mandé cedex - Contact : contact@meteo.fr

Rédigé par Météo-France avec la contribution des observateurs du réseau nivo-météorologiques. Partenariat : ANMSM (Maires de Stations de Montagne), DSF (Domaines Skiables de France), ADSP (Directeurs de Pistes et de la Sécurité des Stations de Sports d'Hiver) et autres acteurs de la montagne.

Bulletin neige & avalanches par téléphone au 0 892 68 10 20 Service 0,35 € / min + prix appel

RÉPUBLIQUE FRANÇAISE
Liberté Égalité Fraternité

METEO FRANCE
À VOS CÔTÉS, DANS UN CLIMAT QUI CHANGE

Bulletin d'estimation du risque d'avalanche

(valable en dehors des pistes balisées et ouvertes)

MASSIF : Vercors

Rédigé le vendredi 13 mars 2026 à 16h

Conditions nivo-météo des 7 derniers jours

	sam. 07/03				dim. 08/03				lun. 09/03				mar. 10/03				mer. 11/03				jeu. 12/03				ven. 13/03			
	03h	09h	15h	21h	03h	09h	15h	21h	03h	09h	15h	21h	03h	09h	15h	21h	03h	09h	15h	21h	03h	09h	15h	21h	03h	09h	15h	21h
Météo																												
Vent (km/h)	20	5	10	10	10	20	20	15	25	35	35	35	35	25	25	15	20	30	30	30	45	35	25	10	15	25	40	55
à 2000m																												
Vent (km/h)	5	5	5	5	10	10	20	15	20	30	30	30	30	20	20	15	20	25	30	20	30	30	20	10	10	15	25	40
à 1500m																												

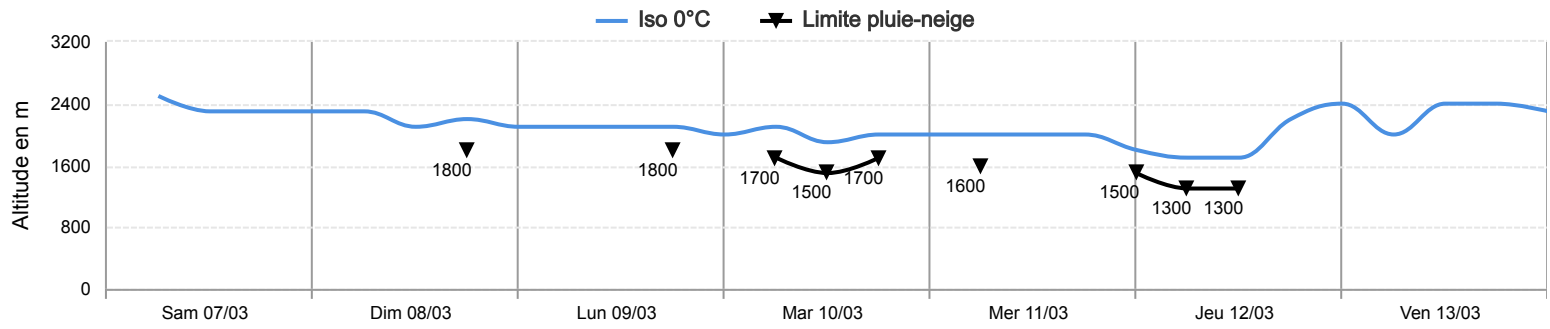

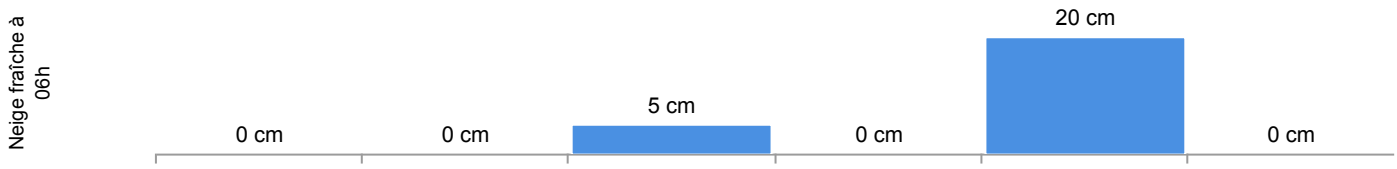

Risque d'avalanche	sam. 07/03	dim. 08/03	lun. 09/03	mar. 10/03	mer. 11/03	jeu. 12/03	ven. 13/03
	2	1	1	1	1	2	2

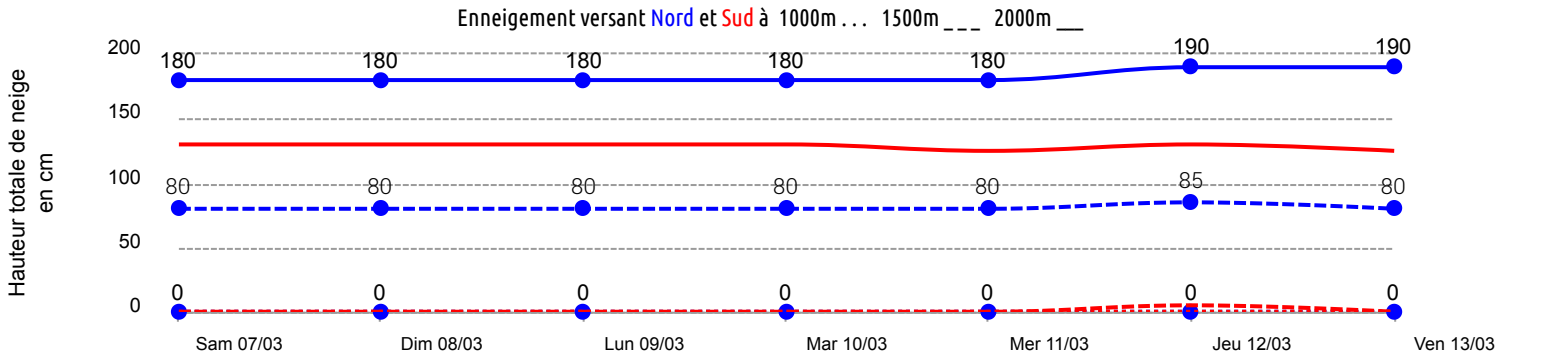

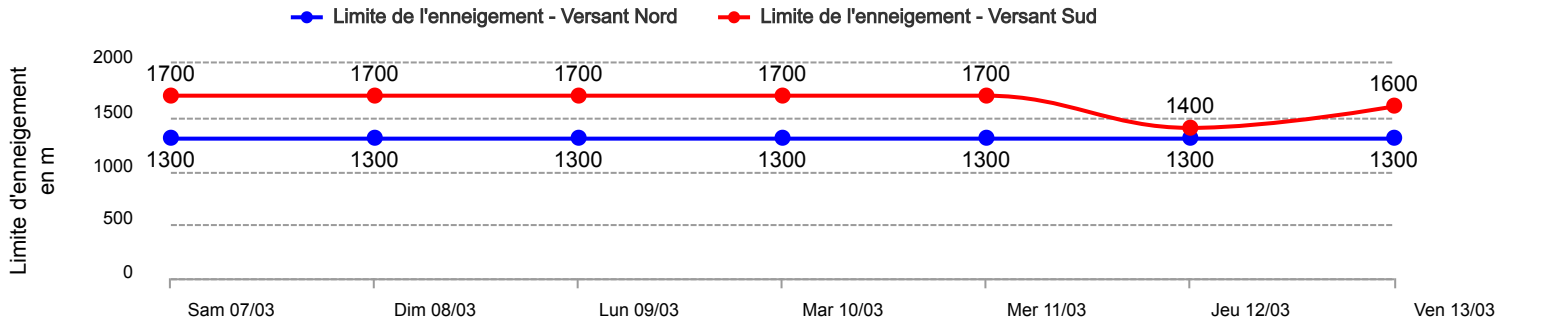

Pour consulter la vigilance en cours, veuillez vous rendre sur le site https://vigilance.meteofrance.fr/fr

Météo-France - 73 avenue de Paris, 94165 Saint-Mandé cedex - Contact : contact@meteo.fr

Rédigé par Météo-France avec la contribution des observateurs du réseau nivo-météorologiques. Partenariat : ANMSM (Maires de Stations de Montagne), DSF (Domaines Skiables de France), ADSP (Directeurs de Pistes et de la Sécurité des Stations de Sports d'Hiver) et autres acteurs de la montagne.

Bulletin neige & avalanches par téléphone au
0 892 68 10 20 Service 0,35 € / min + prix appel