GOBIERNO DE ESPAÑA
VICEPRESIDENCIA TERCERA DEL GOBIERNO
MINISTERIO PARA LA TRANSICIÓN ECOLÓGICA Y EL RETO DEMOGRÁFICO

Boletín de información nivológica y de peligro de aludes

# Pirineo Catalán

aemet Agencia Estatal de Meteorología

## sábado, 14 de marzo de 2026

## Pronóstico hasta las 24 horas del domingo, día 15 de marzo

(Válido fuera de pistas de esquí balizadas y abiertas)

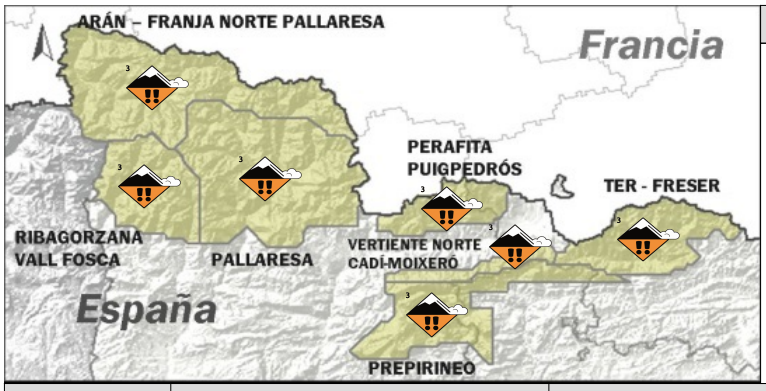


### Problemas de aludes

- Nieve reciente
- Placas de viento
- Capas débiles persistentes

| Macizo | Peligro | Problemas de aludes, cota, orientación, tamaño | Innivación observada (m) |
|---|---|---|---|
| **Arán - Franja norte Pallaresa** | 3 **Notable** | **Nieve reciente** 3 (N, O, E, S)<br>**Placas de viento** 1800 3 (N, O, E, S) | 2026-03-14<br>N S<br>Cota más baja caras N |
| **Ribagorzana - Vall Fosca** | 3 **Notable** | **Nieve reciente** 1800 3 / 2 (N, O, E, S) 2<br>**Placas de viento** 1800 (N, O, E, S) 2 | 2026-03-14<br>N S<br>Cota más baja caras N |
| **Pallaresa** | 3 **Notable** | **Nieve reciente** 1800 3 / 2 (N, O, E, S) 2<br>**Placas de viento** 1800 (N, O, E, S) 2 | 2026-03-14<br>N S<br>Cota más baja caras N |



AEMET. Se autoriza la reproducción de su contenido citando la fuente.

Boletín de información nivológica y de peligro de aludes

# Pirineo Catalán



| | | | |
|---|---|---|---|
| **Perafita - Puigpedrós** | 3 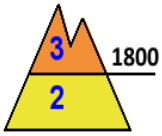  **Notable** | **Nieve reciente**   **Placas de viento** 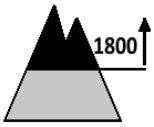   | 2026-03-14 Cota más baja caras N |
| **Ter - Freser** | 3 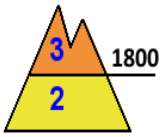  **Notable** | **Placas de viento**   **Capas débiles persistentes**   | 2026-03-14 Cota más baja caras N |
| **Vertiente norte Cadí - Moixeró** | 3 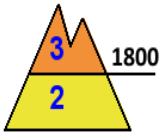  **Notable** | **Placas de viento** 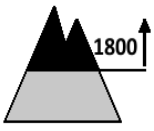   **Capas débiles persistentes**   | 2026-03-14 Cota más baja caras N |
| **Prepirineo** | 3 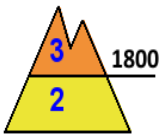  **Notable** | **Placas de viento** 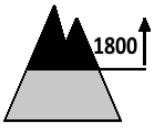   **Capas débiles persistentes**   | 2026-03-14 Cota más baja caras N |

## Estado del manto y observaciones recientes

Durante esta madrugada se han registrado precipitaciones, que hasta las 08 UTC habían dejado unos 5-10 l/m2, algo más en el Ripollés, lo que se ha traducido en unos 5-10 cm de nieve nueva. Estas precipitaciones van a continuar durante el día de hoy, bajando la cota de nieve hasta unos 700-800 metros.


AEMET. Se autoriza la reproducción de su contenido citando la fuente.

Por lo general, el manto es continuo desde cotas medias, mostrando cierta disimetría entre solanas y umbrías, aunque gracias a los últimos depósitos, la nieve está llegando a cotas algo más bajas. Los espesores están muy por encima de lo esperado a estas alturas de la temporada, alcanzando los 120-180 cm en muchas zonas a 2200-2400 metros, pudiendo ser sensiblemente mayores en ventisqueros, hoyas y otras zonas propensas a la acumulación.

La nieve reciente se ha depositado sobre un manto muy humedecido, salvo en las umbrías de cotas altas, donde permanecía más frío y seco. En estas zonas existen estratos superficiales de granos facetados y escarcha, así como algunas capas débiles persistentes en profundidad. También se han formado placas de viento, normalmente pequeñas, pero que pueden colapsar al paso de un solo esquiador.

## Evolución del manto y peligro de aludes para el domingo, día 15

Problema de nieve reciente. Problema de placas de viento y capas débiles persistentes en cotas altas.

Durante las próximas horas van a continuar las nevadas, que podrán dejar entre hoy y la primera mitad de mañana alrededor de 25-40 cm en el Arán y Franja Norte de la Pallaresa, y unos 10-20 cm en el resto de los macizos occidentales, algo menos en los orientales, aunque localmente se pueden superar estos valores. Con estas condiciones serán frecuentes las purgas de nieve reciente en las laderas suficientemente inclinadas, generalmente de tamaño pequeño (riesgo de caída) o mediano (capaz de enterrar a una persona), que localmente podrán llegar a ser grandes (capaz de dañar un vehículo) en las áreas de más acumulación.

Acompañando a las nevadas soplarán vientos fuertes o muy fuertes de componente norte, que levantarán ventiscas y generarán numerosas placas en todas las orientaciones, aunque en mayor medida en las vertientes este, sur y oeste, y que a veces se podrían localizar alejadas de crestas y cordales. Estas formaciones irán aumentando de tamaño conforme pasen las horas, y serán fáciles de fracturar ante una sobrecarga débil (paso de un solo esquiador) u ocasionalmente de manera natural por el peso de las nevadas posteriores, provocando aludes medianos, o incluso grandes, especialmente aquellas que descansen sobre capas débiles persistentes.

## Predicción meteorológica para el domingo, día 15

Muy nuboso o cubierto, con nubes bajas y visibilidad localmente reducida, tendiendo a disminuir la nubosidad por la mañana, hasta quedar poco nuboso o despejado, salvo en el Arán y norte de la Pallaresa que se mantendrán intervalos de nubosidad de retención. Se esperan nevadas débiles o localmente moderadas en los macizos occidentales y resto de la divisoria, siendo más frecuentes e intensas en el Arán y norte de la Pallaresa, principalmente durante la primera mitad del día, sin descartar algunas ocasionales en las demás zonas. Temperaturas en descenso, localmente ligero en las mínimas y puntualmente notable en las máximas. Heladas generalizadas, fuertes y persistentes en cotas altas. Viento de componente norte, muy fuerte en cotas altas, con probables rachas huracanadas (más de 120 km/h), soplando fuerte con rachas muy fuertes en el resto.


AEMET. Se autoriza la reproducción de su contenido citando la fuente.

Datos en la atmósfera libre:

Altitud de la isoterma de 0 ºC: 1300 m
Altitud de la isoterma de -10 ºC: 2600 m (N) - 3600 m (S)

Viento a 1500 m: N 80 km/h
Viento a 3000 m: N 120 km/h

## Evolución para el lunes día 16

Con el cese de las precipitaciones y la mayor insolación y ascenso de las temperaturas, el problema de nieve reciente irá dando paso al problema de nieve húmeda. El peligro asociado a las placas de viento se mantendrá.

Escala europea de peligro de aludes

Débil | Limitado | Notable | Fuerte | Muy Fuerte

Problemas de aludes

Nieve reciente | Placas de viento | Capas débiles persistentes | Nieve húmeda | Deslizamientos basales | Sin problema evidente

Nota1: Se recuerda que, siempre que haya nieve, la ausencia total de peligro no existe. Hay que tener presente que en circunstancias desfavorables, con aludes de tamaño 1 (alud pequeño o colada) y tamaño 2 (alud mediano), se pueden sufrir severos daños personales.

Nota2: Los BPA se elaboran en base a información meteorológica así como al estado del manto nivoso a través de sondeos puntuales. Se advierte a los usuarios de la variabilidad de esta información al extrapolarla a zonas extensas de montaña. Por ello, AEMET no se hace responsable de su uso para la toma de decisiones que conciernen a la seguridad personal, ni de los riesgos físicos o materiales de ellas derivadas.


AEMET. Se autoriza la reproducción de su contenido citando la fuente.