GOBIERNO DE ESPAÑA
VICEPRESIDENCIA TERCERA DEL GOBIERNO
MINISTERIO PARA LA TRANSICIÓN ECOLÓGICA Y EL RETO DEMOGRÁFICO

Boletín de información nivológica y de peligro de aludes

Pirineo Navarro y Aragonés

aemet Agencia Estatal de Meteorología

sábado, 14 de marzo de 2026

Pronóstico hasta las 24 horas del domingo, día 15 de marzo

(Válido fuera de pistas de esquí balizadas y abiertas)

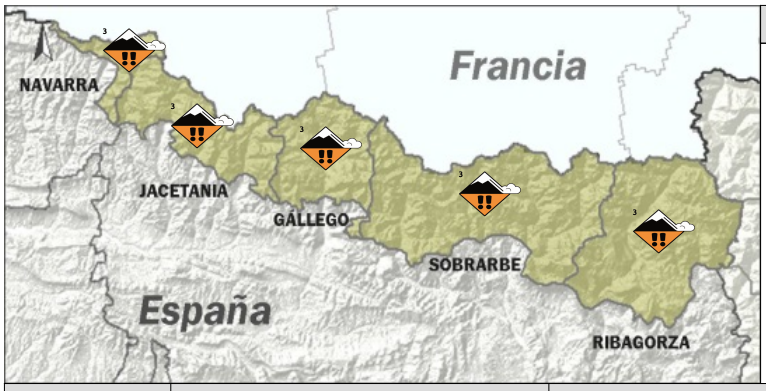

Problemas de aludes

Nieve reciente

Placas de viento

Macizo	Peligro	Problemas de aludes, cota, orientación, tamaño	Innivación observada (m)
Navarra	3 Notable	Nieve reciente: 3	2026-03-14
		Placas de viento: 1800, 3	Cota más baja caras N
Jacetania	3 Notable	Nieve reciente: 2	2026-03-14
		Placas de viento: 1800, 3	Cota más baja caras N
Gállego	3 Notable	Nieve reciente: 2	2026-03-14
		Placas de viento: 1800, 3	Cota más baja caras N

AEMET. Se autoriza la reproducción de su contenido citando la fuente.

Sobrarbe	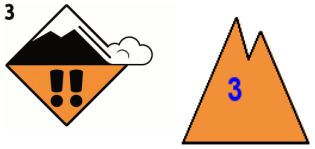 **Notable**	**Nieve reciente**		2026-03-14
		Placas de viento	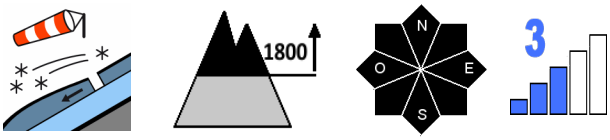	Cota más baja caras N
Ribagorza	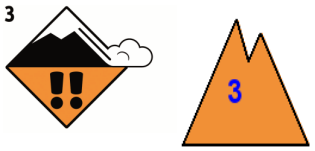 **Notable**	**Nieve reciente**		2026-03-14
		Placas de viento	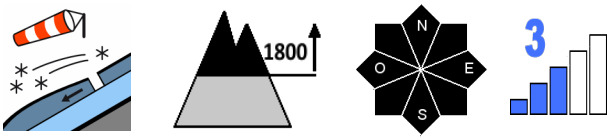	Cota más baja caras N

Estado del manto y observaciones recientes

A últimas horas de ayer comenzaron a producirse precipitaciones en la cordillera, que hasta las 08 UTC de hoy habían dejado unos 15-30 l/m2 en Navarra y Jacetania, alrededor de 10-15 l/m2 en Gállego y Sobrarbe, y en torno a 5-10 l/m2 en Ribagorza, lo que se ha traducido en unos 5-10 cm de nieve nueva en los puntos de observación. Estas precipitaciones van a continuar durante el día de hoy, bajando la cota de nieve hasta unos 700-900 metros.

Con el actual episodio, la nieve está llegando a cotas bajas en muchas zonas, pero con depósitos muy discretos. En medianías y cotas altas los espesores están por encima de lo esperado a estas alturas de la temporada, alcanzando los 60-140 cm a unos 1800 metros, y los 130-220 cm por encima de 2100 metros, pudiendo ser sensiblemente mayores en ventisqueros, hoyas y otras zonas propensas a la acumulación.

La nieve reciente se ha depositado sobre un manto muy humedecido, salvo en las umbrías de cotas altas, donde permanecía más frío y seco. En estas zonas existen estratos superficiales de granos facetados y escarcha, así como algunas capas débiles persistentes en profundidad, por lo general inactivas. También se han formado placas de viento, normalmente pequeñas, pero que pueden colapsar al paso de un solo esquiador.

Evolución del manto y peligro de aludes para el domingo, día 15

Problema de nieve reciente, y de placas de viento en cotas altas.

Durante las próximas horas van a continuar las nevadas, que podrán dejar entre hoy y la primera mitad de mañana alrededor de 25-40 cm en Navarra y en el entorno de la divisoria, y unos 10-15 cm en el resto, localmente más. Con estas condiciones serán frecuentes las purgas de nieve reciente en las laderas suficientemente inclinadas, generalmente de tamaño pequeño (riesgo de caída) o mediano (capaz de enterrar a una persona), que localmente

AEMET. Se autoriza la reproducción de su contenido citando la fuente.

podrán llegar a ser grandes (capaz de dañar un vehículo) en las áreas de más acumulación.

Acompañando a las nevadas soplarán vientos fuertes o muy fuertes de componente norte, que levantarán ventiscas y generarán numerosas placas en todas las orientaciones, aunque en mayor medida en las vertientes este, sur y oeste, y que a veces se podrían localizar alejadas de crestas y cordales. Estas formaciones irán aumentando de tamaño conforme pasen las horas, y serán fáciles de fracturar ante una sobrecarga débil (paso de un solo esquiador) u ocasionalmente de manera natural por el peso de las nevadas posteriores, provocando aludes medianos, o incluso grandes, especialmente aquellas que descansen sobre capas débiles persistentes.

Predicción meteorológica para el domingo, día 15

Pirineo navarro:

Predomino de cielos muy nubosos o cubiertos, con nubes bajas y visibilidad localmente reducida. Se esperan precipitaciones débiles o localmente moderadas, menos intensas y frecuentes por la tarde, que tenderán a remitir a últimas horas. Cota de nieve en torno a 800 metros, subiendo a 900-1000 metros por la tarde. Temperaturas sin cambios, o máximas en ligero descenso. Heladas débiles, moderadas o localmente fuertes en cotas altas. Viento fuerte de componente norte, con rachas muy fuertes en cotas altas y zonas expuestas.

Pirineo aragonés:

Muy nuboso o cubierto, con nubes bajas y visibilidad localmente reducida, tendiendo a disminuir la nubosidad por la mañana, hasta quedar poco nuboso o despejado, salvo en el entorno de la divisoria con Francia que se mantendrá la nubosidad de retención. Se esperan nevadas débiles o localmente moderadas, más probables en el torno de la divisoria, que tenderán a remitir por la tarde. La cota de nieve subirá a 900-1000 metros por la tarde. Temperaturas mínimas en ligero descenso o sin cambios. Máximas en descenso. Heladas generalizadas, fuertes y persistentes en cotas altas. Viento de componente norte, muy fuerte en cotas altas, sin descartar rachas huracanadas (más de 120 km/h), soplando fuerte con rachas muy fuertes en el resto.

Datos en la atmósfera libre:

Altitud de la isoterma de 0 ºC: 1300 m
Altitud de la isoterma de -10 ºC: 3400 m (W) - 3000 m (E)

Viento a 1500 m: N 80 km/h
Viento a 3000 m: N 120 km/h

Evolución para el lunes día 16

Con el cese de las precipitaciones y la mayor insolación y ascenso de las temperaturas, el problema de nieve reciente irá dando paso al problema de nieve húmeda. El peligro asociado a las placas de viento se mantendrá.

(Información elaborada a partir de los datos recibidos de los refugios de Linza, Lizara, Panticosa, Bachimaña, Góriz, Pineta, Estós, Angel Orús, La Renclusa, Cap de Llauset y Belagua, de las estaciones de esquí de Candanchú, Astún, Formigal y Panticosa (lagos), de la estación de esquí de fondo de Llanos del Hospital y de Ordesa Pradera)

AEMET. Se autoriza la reproducción de su contenido citando la fuente.

Boletín de información nivológica y de peligro de aludes

Pirineo Navarro y Aragonés

Escala europea de peligro de aludes

Débil | Limitado | Notable | Fuerte | Muy Fuerte

Problemas de aludes

Nieve reciente | Placas de viento | Capas débiles persistentes | Nieve húmeda | Deslizamientos basales | Sin problema evidente

Nota1: Se recuerda que, siempre que haya nieve, la ausencia total de peligro no existe. Hay que tener presente que en circunstancias desfavorables, con aludes de tamaño 1 (alud pequeño o colada) y tamaño 2 (alud mediano), se pueden sufrir severos daños personales.

Nota2: Los BPA se elaboran en base a información meteorológica así como al estado del manto nivoso a través de sondeos puntuales. Se advierte a los usuarios de la variabilidad de esta información al extrapolarla a zonas extensas de montaña. Por ello, AEMET no se hace responsable de su uso para la toma de decisiones que conciernen a la seguridad personal, ni de los riesgos físicos o materiales de ellas derivadas.

AEMET. Se autoriza la reproducción de su contenido citando la fuente.