Sonntag 15.03.2026

Veröffentlicht am 14.03.2026 um 17:00

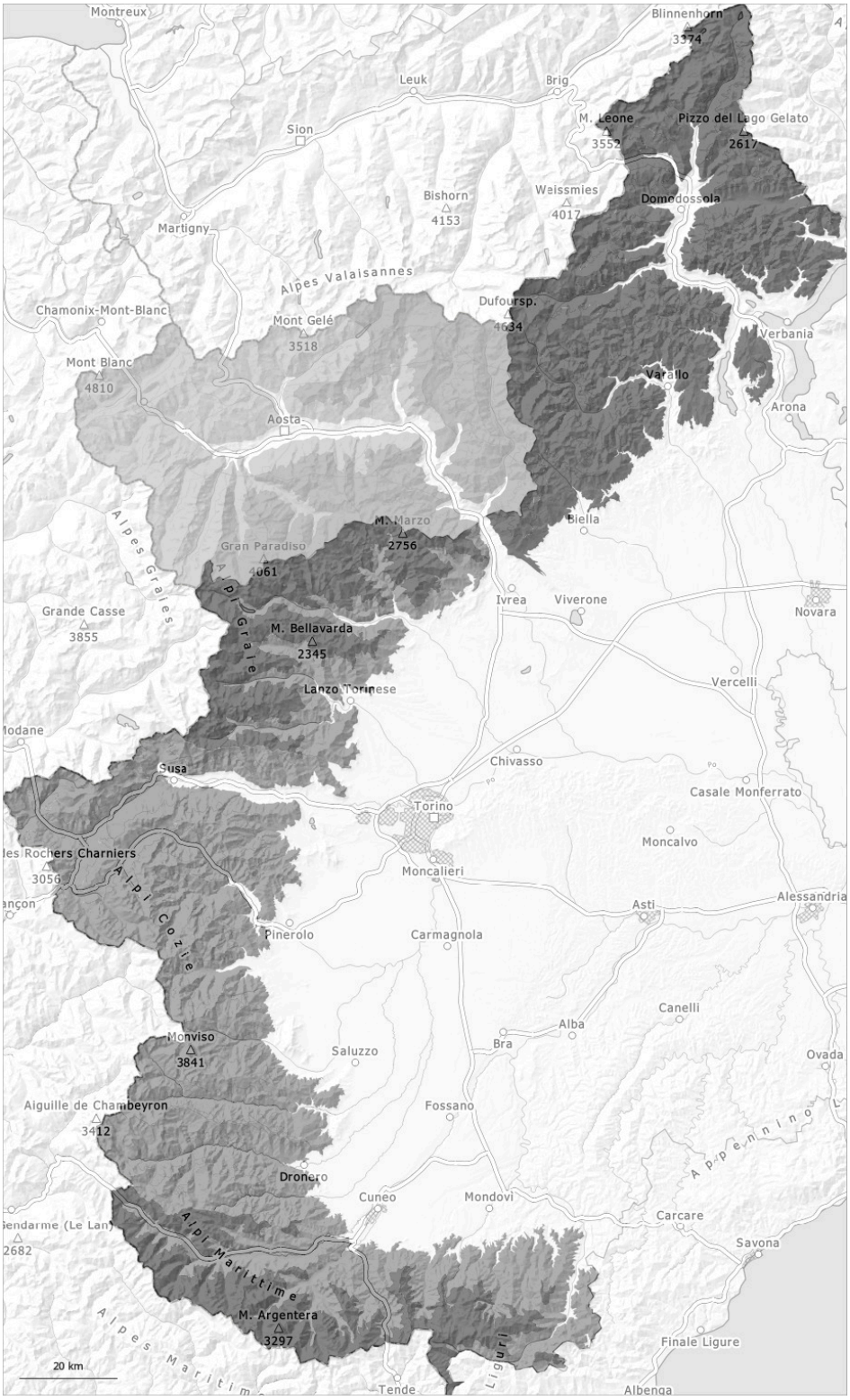

1	2	3	4	5
gering	mäßig	erheblich	groß	sehr groß

Gefahrenstufe 4 - Groß

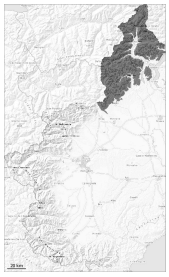

4

Tendenz: Lawinengefahr bleibt gleich
am Montag, den 16.03.2026

Neuschnee

In den Hauptniederschlagsgebieten sind die Gefahrenstellen häufig und die Gefahr "groß", Stufe 4.

Bis am Mittag fällt Schnee oberhalb von rund 1000 m.
Sehr viel Neuschnee sowie die teils mächtigen Triebschneeansammlungen sind an allen Expositionen sehr störanfällig. Der Neuschnee und die Triebschneeansammlungen können spontan abgleiten. In diesen Gebieten sind zahlreiche große und vereinzelt sehr große Lawinen zu erwarten.
Die Spitze der Lawinenaktivität wird voraussichtlich ab der zweiten Nachthälfte erreicht.
Lawinen können bis in Tallagen vorstoßen und exponierte Verkehrswege gefährden.

Von Skitouren, Freeriden und Schneeschuhwanderungen wird dringend abgeraten.

Schneedecke

Gefahrenmuster gm.6: lockerer schnee und wind

Die Altschneedecke ist gut verfestigt, mit einer oft tragfähigen Schmelzharschkruste an der Oberfläche. Gestern fiel viel Schnee. Bis am Mittag fällt verbreitet Schnee oberhalb von rund 1000 m. Der Neuschnee verbindet sich nur langsam mit dem Altschnee.
Der Ostwind verfrachtet den Neuschnee.

Mittlere und hohe Lagen: In der Altschneedecke sind besonders an Schattenhängen einzelne Schwachschichten vorhanden.

Tendenz

Viel Neuschnee und Triebschnee bleiben bis auf weiteres störanfällig.

Gefahrenstufe 4 - Groß

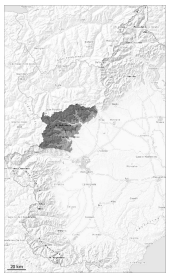

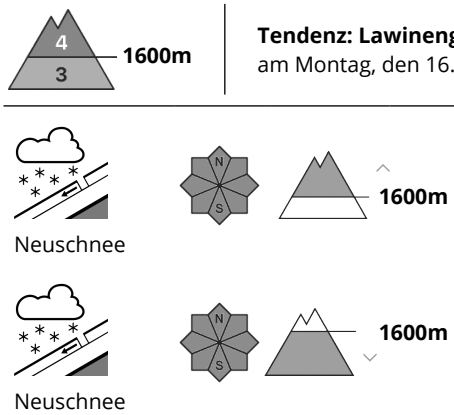

Tendenz: Lawinengefahr bleibt gleich
am Montag, den 16.03.2026

In mittleren und hohen Lagen große Lawinengefahr.

Intensiver Schneefall oberhalb von rund 1600 m: Gefahrenstellen und Auslösebereitschaft nehmen ab der zweiten Nachthälfte zu.
An allen Expositionen und in mittleren und hohen Lagen sind mit Neuschnee und starkem Wind mittlere und große spontane Lawinen zu erwarten.
Die Spitze der Lawinenaktivität wird voraussichtlich am Vormittag erreicht.
Lawinen können bis in Tallagen vorstoßen und exponierte Verkehrswege stellenweise gefährden.

Skitouren, Variantenabfahrten und Schneeschuhwanderungen erfordern viel Erfahrung in der Beurteilung der Lawinengefahr.

Schneedecke

Gefahrenmuster gm.6: lockerer schnee und wind

Die Altschneedecke ist gut verfestigt, mit einer oft tragfähigen Schmelzharschkruste an der Oberfläche.
Bis am Mittag fällt verbreitet Schnee oberhalb von rund 1000 m. Der Neuschnee verbindet sich nur langsam mit dem Altschnee.
Der Ostwind verfrachtet den Neuschnee.

Mittlere und hohe Lagen: In der Altschneedecke sind besonders an Schattenhängen einzelne Schwachschichten vorhanden.

Tendenz

Die Lawinengefahr nimmt noch nicht ab.

Gefahrenstufe 4 - Groß

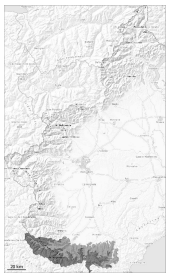

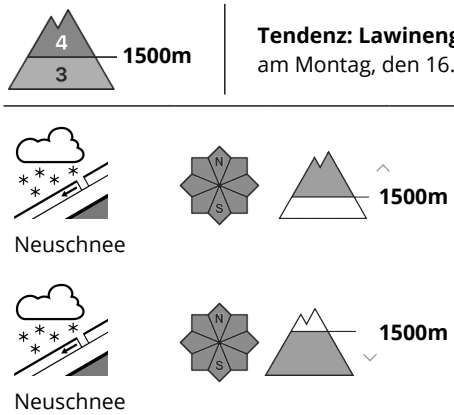

Tendenz: Lawinengefahr bleibt gleich
am Montag, den 16.03.2026

Mit dem Schneefall steigt die Lawinengefahr im Verlaufe der Nacht an auf die Stufe 4, "groß".

Bis am Mittag fällt Schnee oberhalb von rund 800 m.
Mit Neuschnee und mäßigem Wind aus östlichen Richtungen entstanden störanfällige Triebschneeansammlungen. An allen Expositionen und in mittleren und hohen Lagen sind mittlere und vereinzelt große Lawinen zu erwarten.
Gefahrenstellen und Auslösebereitschaft nehmen ab der zweiten Nachthälfte zu.
Die Spitze der Lawinenaktivität wird voraussichtlich am Vormittag erreicht.
Lawinen können bis in Tallagen vorstoßen und exponierte Verkehrswege stellenweise gefährden.

Skitouren, Variantenabfahrten und Schneeschuhwanderungen erfordern viel Erfahrung in der Beurteilung der Lawinengefahr.

Schneedecke

Gefahrenmuster gm.6: lockerer schnee und wind

Die Altschneedecke ist gut verfestigt, mit einer aus lockerem Schnee bestehenden Oberfläche, die auf einer oft tragfähigen Schmelzharschkruste liegt.
Bis Sonntag fällt verbreitet Schnee oberhalb von rund 800 m.
Der Neuschnee verbindet sich nur langsam mit dem Altschnee.
Der Ostwind verfrachtet den Neuschnee intensiv.

V.a. in mittleren und hohen Lagen liegt für die Jahreszeit viel Schnee.

Tendenz

Die Lawinenaktivität nimmt nach dem Ende der Schneefälle nur langsam ab.

Gefahrenstufe 3 - Erheblich

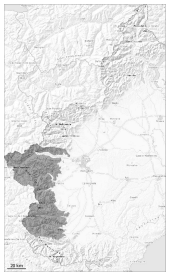

3

Tendenz: Lawinengefahr bleibt gleich
am Montag, den 16.03.2026

Neuschnee

Neu- und Triebschnee: In diesen Gebieten ist die Lawinengefahr "erheblich" (Stufe 3).

Bis am Mittag fällt Schnee oberhalb von rund 1200 m.
Der Neuschnee überlagert eine recht günstige Altschneedecke.
Mit Neuschnee und starkem Wind aus östlichen Richtungen entstanden seit Samstag vor allem in mittleren und hohen Lagen störanfällige Triebschneeansammlungen. An allen Expositionen sind mittlere Lawinen zu erwarten.
Lawinen können an vielen Stellen schon von einzelnen Wintersportlern ausgelöst werden.

Skitouren, Variantenabfahrten und Schneeschuhwanderungen erfordern Erfahrung in der Beurteilung der Lawinengefahr und eine vorsichtige Routenwahl.

Schneedecke

Gefahrenmuster gm.6: lockerer schnee und wind

Die Altschneedecke ist gut verfestigt, mit einer aus lockerem Schnee bestehenden Oberfläche, die auf einer oft tragfähigen Schmelzharschkruste liegt.
Bis am Mittag fällt verbreitet Schnee oberhalb von rund 1200 m. Der Neuschnee verbindet sich nur langsam mit dem Altschnee.
Der Ostwind verfrachtet den Neuschnee.

Mittlere und hohe Lagen: In der Altschneedecke sind besonders an Schattenhängen einzelne Schwachschichten vorhanden.

Tendenz

Die Lawinengefahr nimmt noch nicht ab.