Sonntag 15.03.2026

Veröffentlicht am 14.03.2026 um 17:00

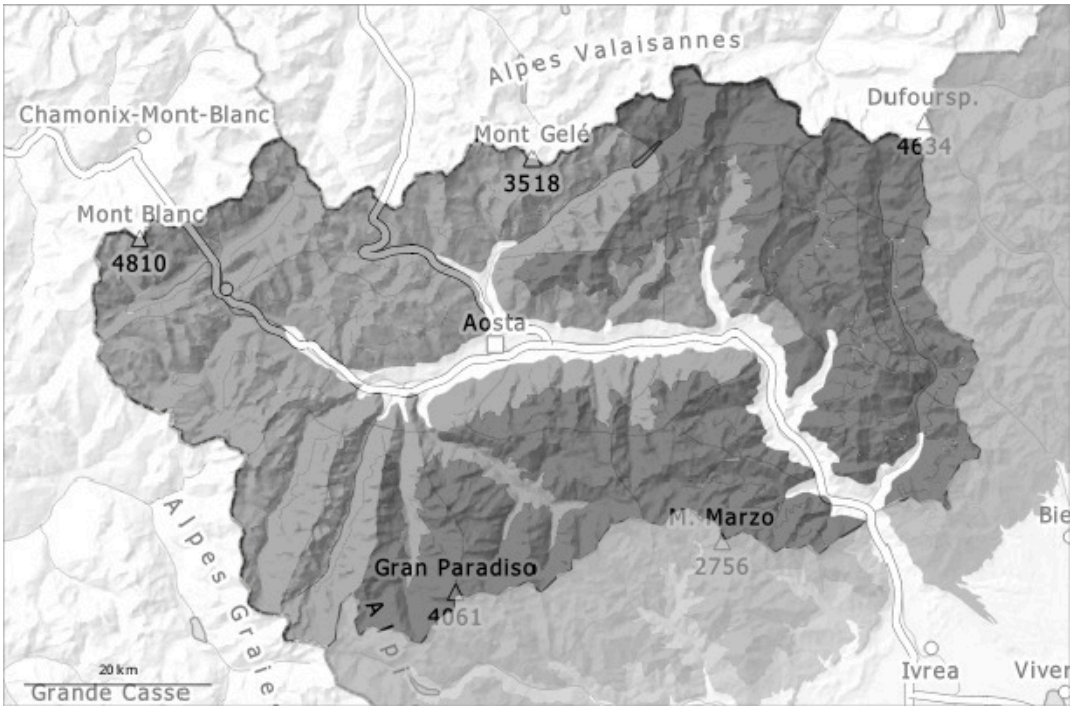

1	2	3	4	5
gering	mäßig	erheblich	groß	sehr groß

Gefahrenstufe 4 - Groß

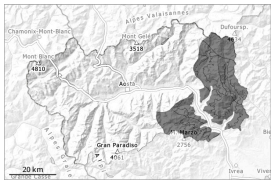

Tendenz: Lawinengefahr bleibt gleich
am Montag, den 16.03.2026

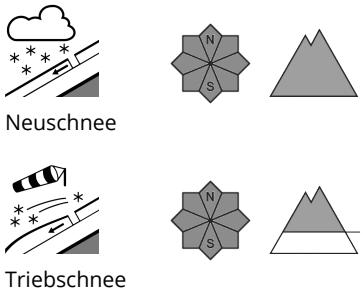

Intensiver Schneefall bis in tiefe Lagen: Es sind mittlere und große trockene Lawinen zu erwarten.

Bis am Morgen fallen oberhalb von rund 1000 m verbreitet 80 bis 120 cm Schnee. Er verbindet sich schlecht mit dem Altschnee. Der mäßige Wind verfrachtet den Neuschnee. Der viele Neuschnee sowie die Triebschneeansammlungen können spontan abgleiten. V.a. an steilen Schattenhängen sind vor allem aus hoch gelegenen Einzugsgebieten zahlreiche teils große Lawinen zu erwarten.
Die Spitze der Lawinenaktivität wird voraussichtlich in der zweiten Nachthälfte erreicht. Es sind Staublawinen zu erwarten. Die trockenen Lawinen können in den typischen Lawinenzügen bis in Tallagen vorstoßen. Exponierte Teile von Verkehrswegen können dort lokal gefährdet sein.
Von Skitouren, Freeriden und Schneeschuhwanderungen wird dringend abgeraten.

Schneedecke

Gefahrenmuster gm.6: lockerer schnee und wind

In diesen Gebieten sinkt die Schneefallgrenze auf etwa 500 m.
Der Neuschnee verbindet sich schlecht mit dem Altschnee.
Besonders steile Schattenhänge hohe Lagen und Hochgebirge: Der obere Teil der Schneedecke ist ungünstig geschichtet. In der Altschneedecke sind dort Schwachschichten vorhanden.
In Kamm- und Passlagen sowie in hohen Lagen liegen je nach Windeinfluss sehr unterschiedliche Schneehöhen.

Tendenz

Starker Nordwestwind: An Triebschneehängen ist die Auslösebereitschaft hoch. Zudem nimmt die Gefahr von feuchten und nassen Lawinen im Tagesverlauf zu.

Gefahrenstufe 4 - Groß

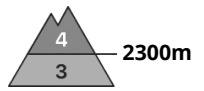

Tendenz: Lawinengefahr nimmt ab
am Montag, den 16.03.2026

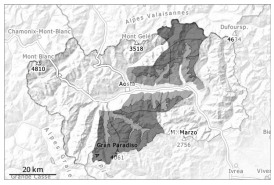

Triebschnee

Neuschnee

Mit Neuschnee und Wind gefährliche Lawinensituation. Es sind viele mittlere und vereinzelt große trockene Lawinen zu erwarten.

Bis am Morgen fallen oberhalb von rund 1000 m verbreitet 40 bis 60 cm Schnee. Er verbindet sich schlecht mit dem Altschnee. Der mäßige Wind verfrachtet den Neuschnee. Der Neuschnee sowie die Triebschneeansammlungen können spontan abgleiten. V.a. an steilen Schattenhängen sind vor allem aus hoch gelegenen Einzugsgebieten viele mittlere und vereinzelt große Lawinen zu erwarten. Es sind Staublawinen möglich. Sie können in den typischen Lawinenzügen teilweise bis in Tallagen vorstoßen.
Für Touren und Variantenabfahrten sind die Verhältnisse sehr gefährlich.

Schneedecke

In diesen Gebieten sinkt die Schneefallgrenze auf etwa 500 m.
Besonders steile Schattenhänge hohe Lagen und Hochgebirge: Der obere Teil der Schneedecke ist ungünstig geschichtet. In der Altschneedecke sind dort Schwachschichten vorhanden.
In Kamm- und Passlagen sowie in hohen Lagen liegen je nach Windeinfluss sehr unterschiedliche Schneehöhen.

Tendenz

Starker Nordwestwind: An Triebschneehängen ist die Auslösebereitschaft hoch. Zudem nimmt die Gefahr von feuchten und nassen Lawinen im Tagesverlauf zu.

Gefahrenstufe 3 - Erheblich

Tendenz: Lawinengefahr bleibt gleich
am Montag, den 16.03.2026

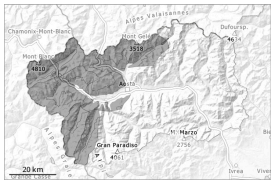

Triebschnee

Neuschnee

Neu- und Triebschnee: Die Tourenverhältnisse sind ungünstig.

Bis am Morgen fallen oberhalb von rund 1000 m verbreitet 25 bis 30 cm Schnee, lokal bis zu 40 cm. Der mäßige Wind verfrachtet den Neuschnee. Der Neuschnee sowie die Triebschneeansammlungen können leicht ausgelöst werden oder spontan abgleiten. Auch im Bereich der Waldgrenze sind diese Gefahrenstellen häufig. Fernauslösungen sind möglich.
Die trockenen Lawinen sind vereinzelt recht groß. Sie können vor allem in den an die Gefahrenstufe 4, "groß" angrenzenden Gebieten in den typischen Lawinenzügen bis in mittlere Lagen vorstoßen.
Skitouren, Variantenabfahrten und Schneeschuhwanderungen erfordern viel Erfahrung und Zurückhaltung.

Schneedecke

Gefahrenmuster gm.6: lockerer schnee und wind

Der obere Teil der Schneedecke ist ungünstig geschichtet. Der Neuschnee verbindet sich stellenweise schlecht mit dem Altschnee.
Besonders steile Schattenhänge hohe Lagen und Hochgebirge: In der Altschneedecke sind dort Schwachschichten vorhanden.
In Kamm- und Passlagen sowie in hohen Lagen liegen je nach Windeinfluss sehr unterschiedliche Schneehöhen.

Tendenz

Starker Nordwestwind: An Triebschneehängen ist die Auslösebereitschaft hoch. Zudem nimmt die Gefahr von feuchten und nassen Lawinen im Tagesverlauf zu.