ICGC Institut Cartogràfic i Geològic de Catalunya

Servei Meteorològic de Catalunya meteo.cat

Boletín de peligro de aludes para el Pirineo de Catalunya
Del 14/03/2026 al 16/03/2026

(Válido fuera pistas de esquí y zonas no controladas)

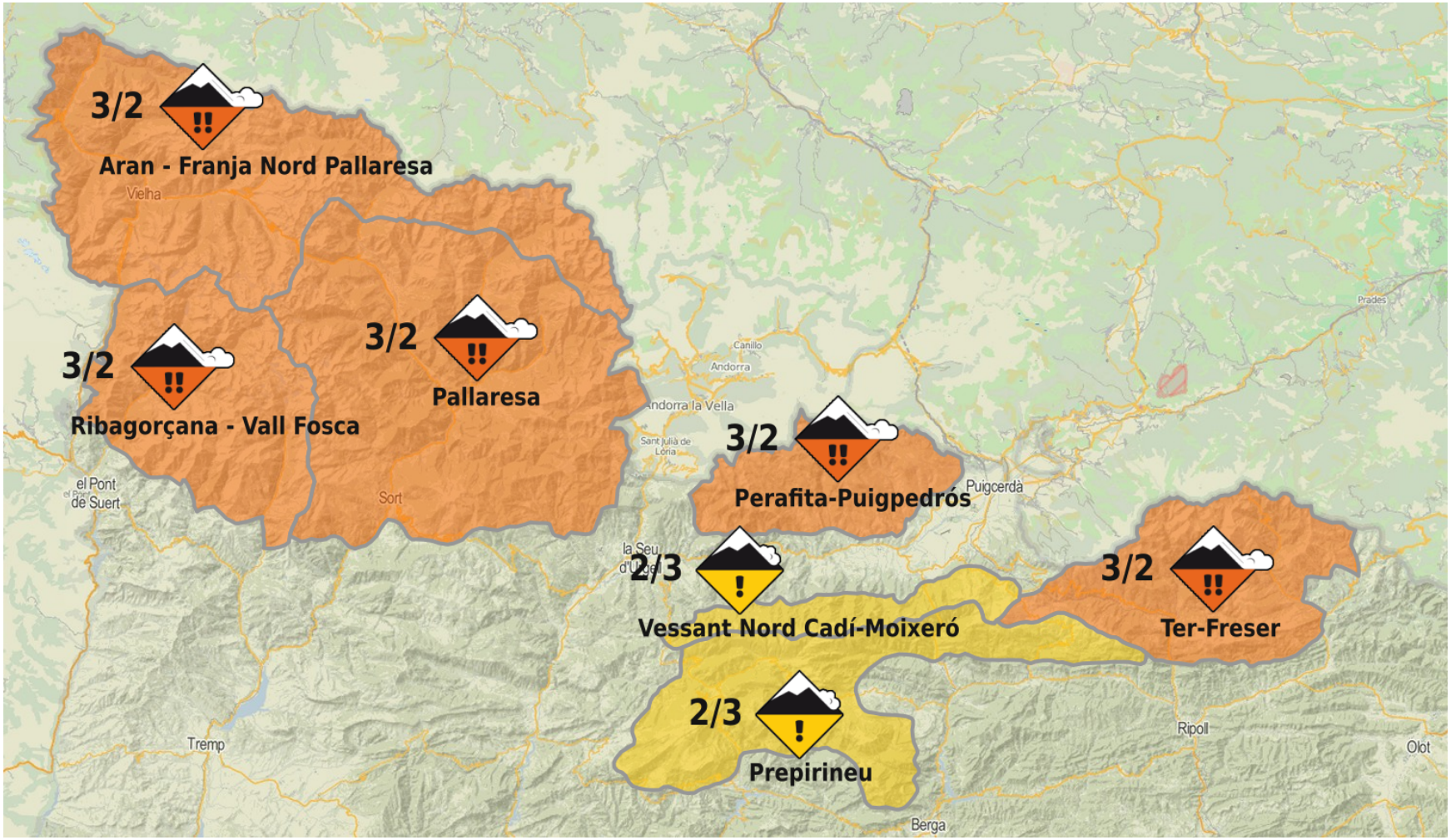

5 MUY FUERTE	4 FUERTE	3 NOTABLE	2 LIMITADO	1 DÉBIL

ICGC Institut Cartogràfic i Geològic de Catalunya

meteo.cat Servei Meteorològic de Catalunya

Boletín de peligro de aludes Aran - Franja Nord Pallaresa Del 14/03/2026 al 16/03/2026

(Válido fuera pistas de esquí y zonas no controladas)

Notable (3) por encima los 2000 m, Limitado (2) por debajo.

Situación primaria

Nieve venteada

Distribución

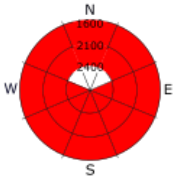

Tamaño

Origen

Tendencia

Situación secundaria

Capas débiles persistentes

Distribución

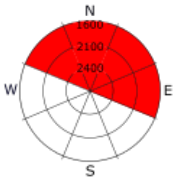

Tamaño

Origen

Tendencia

Estado del manto nivoso

El manto nivoso existente es susceptible de ser removido en cotas altas por el viento. Las nevadas del sábado hasta la mañana de Domingo con incremento de viento de NW y N, forma nuevas placas de viento en orientaciones E, S y W. Estas placas se encontrarán por encima de los 2100 m en las orientaciones antes indicadas. Podrán caer de forma natural el sábado y el domingo sobre todo, con tendencia a caer de forma accidental el lunes por el asentamiento previsto. Serán de tamaño suficiente para enterrar a una persona. Por debajo de los 2100-2000 m pueden caer purgas de nieve reciente en pendientes empinadas sin capacidad para cubrirnos. Caerán sobretodo con los claros el lunes. Hay varias capas débiles persistentes enterradas: escarcha o facetas sobre la costra marrón. Estas capas pueden fracturarse fácilmente a nuestro paso dando lugar a aludes de tamaño suficiente para cubrir a una persona o incluso a un grupo de personas a medida que se incremente el grosor de placa con las nevadas.

Distribución del manto nivoso

Hay nieve por encima de unos 1.400-1-500 ma umbrías y 1.700 ma solanas. Los espesores a unos 2.200 m son superiores a los normales en la Franja Norte de la Pallaresa y en la mitad sur del Aran donde rondan los 180-220 cm. En la mitad norte de Arán hay unos 120-140 cm de grosor total.

Tendencia para las próximas 48-72h

Las placas de viento se irán asentando. El frío mantendrá activas las débiles capas. Evolución del peligro: ESTACIONARIO

El próximo boletín será emitido el día 2026-03-16

5 MUY FUERTE	4 FUERTE	3 NOTABLE	2 LIMITADO	1 DÉBIL

EAWS EUROPEAN AVALANCHE WARNING SERVICES

ICGC Institut Cartogràfic i Geològic de Catalunya

Servei Meteorològic de Catalunya

Boletín de peligro de aludes Ribagorçana - Vall Fosca Del 14/03/2026 al 16/03/2026

(Válido fuera pistas de esquí y zonas no controladas)

Notable (3) per encima los 2200 m, Limitado (2) por debajo.

Situación primaria

Nieve venteada

Distribución

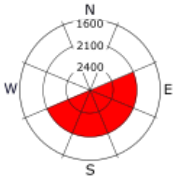

Tamaño

Origen

Tendencia

Situación secundaria

Capas débiles persistentes

Distribución

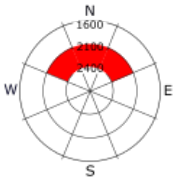

Tamaño

Origen

Tendencia

Estado del manto nivoso

Desde el viernes se ha iniciado una nevada que el sábado se prevé acompañada de viento en aumento y descenso de temperatura. Con el viento de NW y N se formarán nuevas placas de viento sobre los 2100 m en orientaciones que van de E hasta SW. El extremo norte de este sector, más influenciado por las nevadas, es donde las placas serán más gruesas así como también bajo collados y cordales de las orientaciones indicadas en la mitad sur del sector. Estas placas con el descenso térmico y el incremento del viento se presentarán frágiles. Pueden caer de forma natural y tener tamaño para enterrar a una persona. A medida que haya insolación el lunes las placas podrán asentarse ligeramente pero atención porque pasarán a poder caer a nuestro paso. La nieve granulada existente, que se concentra en umbrías resguardadas del viento, por debajo de 2400 m, queda enterrada por las placas y puede dar paso a caídas naturales de placas, con capacidad de enterrar a una persona, debido a esta capa dèbil.

Distribución del manto nivoso

Hay nieve en el suelo a 1.600 m en terreno umbrío, y por encima de unos 1.800 m en laderas soleadas. El manto es esquiable por encima de unos 1.800-1.900 ma umbrías. Los grosores alcanzan los 105-135 cm a unos 2.200 m. Estos valores son superiores a los normales para la época.

Tendencia para las próximas 48-72h

Se prevé una mejora de la situación de las placas de viento pero la situación de capa débil persisntente mantendrá. Peligro EN PROGRESIVO DESCENSO

El próximo boletín será emitido el día 2026-03-16

5 MUY FUERTE	4 FUERTE	3 NOTABLE	2 LIMITADO	1 DÉBIL

EAWS EUROPEAN AVALANCHE WARNING SERVICES

ICGC Institut Cartogràfic i Geològic de Catalunya

Servei Meteorològic de Catalunya

Boletín de peligro de aludes Pallaresa
Del 14/03/2026 al 16/03/2026

(Válido fuera pistas de esquí y zonas no controladas)

Notable (3) per encima los 2200 m, Limitado (2) por debajo.

Situación primaria

Nieve venteada

Distribución

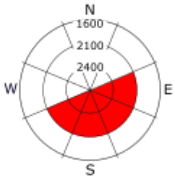

Tamaño

Origen

Tendencia

Estado del manto nivoso

Desde el viernes se ha iniciado una nevada que el sábado se prevé acompañada de viento en aumento y descenso de temperatura. Con el viento de NW y N se formarán nuevas placas de viento sobre los 2100 m en orientaciones que van de E hasta SW. El extremo norte de este sector, más influenciado por las nevadas, es donde las placas serán más gruesas así como también bajo collados y cordales de las orientaciones indicadas en la mitad sur del sector. Estas placas con el descenso térmico y el incremento del viento se presentarán frágiles. Pueden caer de forma natural y tener tamaño para enterrar a una persona. A medida que haya insolación el lunes las placas podrán asentarse ligeramente pero atención porque pasarán a poder caer a nuestro paso.

Distribución del manto nivoso

Hay nieve en el suelo a 1.600 m en N, ya 1.800-1.900 m en S. El manto es esquiable por encima de unos 1.800-1.900 m en umbrías. Los espesores alcanzan los 115-155 cm en cotas medias, variable según los efectos del viento.

Tendencia para las próximas 48-72h

Se prevé una mejora de la situación de las placas de viento. Possibilidad de que surja un problema de capa débil persistente. Peligro EN PROGRESIVO DESCENSO

El próximo boletín será emitido el día 2026-03-16

5 MUY FUERTE	4 FUERTE	3 NOTABLE	2 LIMITADO	1 DÉBIL

EAWS EUROPEAN AVALANCHE WARNING SERVICES

ICGC Institut Cartogràfic i Geològic de Catalunya

Servei Meteorològic de Catalunya

Boletín de peligro de aludes Perafita-Puigpedrós Del 14/03/2026 al 16/03/2026

(Válido fuera pistas de esquí y zonas no controladas)

Notable (3) per encima los 2200 m, Limitado (2) por debajo.

Situación primaria

Nieve venteada

Distribución

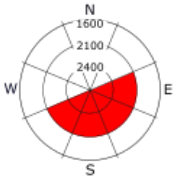

Tamaño

Origen

Tendencia

Estado del manto nivoso

Desde el viernes se ha iniciado una nevada que el sábado se prevé acompañada de viento en aumento y descenso de temperatura. Con el viento de NW y N se formarán nuevas placas de viento sobre los 2100 m en orientaciones que van de E hasta SW. El extremo norte de este sector, más influenciado por las nevadas, es donde las placas serán más gruesas así como también bajo collados y cordales de las orientaciones indicadas en la mitad sur del sector. Estas placas con el descenso térmico y el incremento del viento se presentarán frágiles. Pueden caer de forma natural y tener tamaño para enterrar a una persona. A medida que haya insolación el lunes las placas podrán asentarse ligeramente pero atención porque pasarán a poder caer a nuestro paso.

Distribución del manto nivoso

Hay nieve en el suelo por encima de unos 1.700 m en N y 1.900 en S. Los espesores, aunque irregulares, rondan los 85-105 cm en cotas medias. Son grosores por encima de los habituales para la época.

Tendencia para las próximas 48-72h

Se prevé una mejora de la situación de las placas de viento. Posibilidad de aparecer la situación de capa débil persistente. Peligro EN PROGRESIVO DESCENSO

El próximo boletín será emitido el día 2026-03-16

5 MUY FUERTE	4 FUERTE	3 NOTABLE	2 LIMITADO	1 DÉBIL

EAWS EUROPEAN AVALANCHE WARNING SERVICES

ICGC Institut Cartogràfic i Geològic de Catalunya

Servei Meteorològic de Catalunya meteo.cat

Boletín de peligro de aludes Vessant Nord Cadí-Moixeró Del 14/03/2026 al 16/03/2026

(Válido fuera pistas de esquí y zonas no controladas)

Limitado (2) en todo el sector excepto, Notable (3) por encima de 2200 m

Situación primaria

Nieve venteada

Distribución

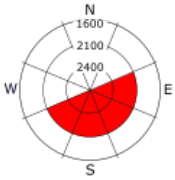

Tamaño

Origen

Tendencia

Situación secundaria

Capas débiles persistentes

Distribución

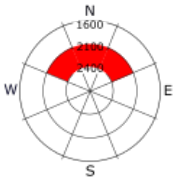

Tamaño

Origen

Tendencia

Estado del manto nivoso

El manto nivoso existente es susceptible de ser removido por el viento, especialmente de las cotas más altas. Las placas de viento ya formadas o las que se formen con el episodio de viento pueden caer a nuestro paso. Pueden alcanzar tamaño suficiente para enterrar a una persona. Se encuentran en orientaciones que van de E hasta SW y no se descarta que pueda haberlas puntualmente en las zonas de las canales muy protegidas del efecto erosivo del viento. En las umbrías, se conserva la nieve granulada caída durante los chubascos que se han dado durante la semana. Esta nieve granulada puede dar paso a aludes de placa que pueden caer a nuestro paso. Serán de tamaño suficiente para enterrar a una persona.

Distribución del manto nivoso

En umbrías hay nieve por encima de 1.600 m, esquiable por encima de unos 1.700 m. En solanas la nieve está presente por encima de 1.800 m. Los grosores están alrededor de 165-185 cm a 2.200 m. Estos valores son muy excedentarios para la época del año.

Tendencia para las próximas 48-72h

Se prevé una mejora de la situación de las placas de viento, pero la situación de capa débil persistente se mantendrá. Peligro EN PROGRESIVO DESCENSO

El próximo boletín será emitido el día 2026-03-16

5 MUY FUERTE	4 FUERTE	3 NOTABLE	2 LIMITADO	1 DÉBIL

EAWS EUROPEAN AVALANCHE WARNING SERVICES

ICGC Institut Cartogràfic i Geològic de Catalunya

meteo.cat Servei Meteorològic de Catalunya

Boletín de peligro de aludes Prepirineu
Del 14/03/2026 al 16/03/2026

(Válido fuera pistas de esquí y zonas no controladas)

Limitado (2) en todo el sector excepto, Notable (3) por encima de 2200 m

Situación primaria

Nieve venteada

Distribución

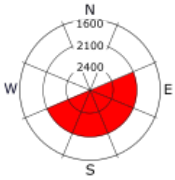

Tamaño

Origen

Tendencia

Situación secundaria

Capas débiles persistentes

Distribución

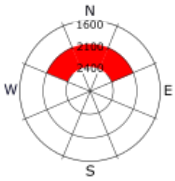

Tamaño

Origen

Tendencia

Estado del manto nivoso

El manto nivoso existente es susceptible de ser removido por el viento, especialmente de las cotas más altas. Las placas de viento ya formadas o las que se formen con el episodio de viento pueden caer a nuestro paso. Pueden alcanzar tamaño suficiente para enterrar a una persona. Se encuentran en orientaciones que van de E hasta SW. En las umbrías, se conserva la nieve granulada caída durante los chubascos que se han dado durante la semana. Esta nieve granulada puede dar paso a aludes de placa que pueden caer a nuestro paso. Serán de tamaño suficiente para enterrar a una persona.

Distribución del manto nivoso

En umbrías hay nieve por encima de 1.600-1700 m. En solanas la nieve está presente por encima de 1.800-1.900 m. Los espesores, aunque irregulares, rondan los 65-85 cm en cotas medias.

Tendencia para las próximas 48-72h

Se prevé una mejora de la situación de las placas de viento, pero la situación de capa débil persistente se mantendrá. Peligro EN PROGRESIVO DESCENSO

El próximo boletín será emitido el día 2026-03-16

5 MUY FUERTE	4 FUERTE	3 NOTABLE	2 LIMITADO	1 DÉBIL

EAWS EUROPEAN AVALANCHE WARNING SERVICES

ICGC Institut Cartogràfic i Geològic de Catalunya

meteo.cat Servei Meteorològic de Catalunya

Boletín de peligro de aludes Ter-Freser
Del 14/03/2026 al 16/03/2026

(Válido fuera pistas de esquí y zonas no controladas)

Notable (3) por encima los 2200 m, Limitado (2) por debajo.

Situación primaria

Nieve venteada

Distribución

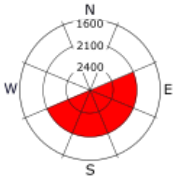

Tamaño

Origen

Tendencia

Situación secundaria

Capas débiles persistentes

Distribución

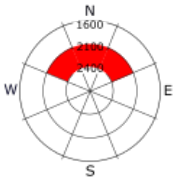

Tamaño

Origen

Tendencia

Estado del manto nivoso

Desde el viernes se ha iniciado una nevada con viento previsto en aumento y descenso de temperatura el s. Cerca del sector hubo actividad accidental de placas en orientaciones E por encima de los 2200. Con el viento de NW y N habrá nuevas placas por encima de los 2100 m en orientaciones que van de E hasta SW. Las placas más gruesas estarán bajo collados y cordales de las orientaciones indicadas y a resguardo del viento. Estas placas con el descenso térmico y el incremento del viento se presentarán frágiles. Pueden caer de forma espontánea y tener tamaño suficiente para enterrar a una persona. A medida que haya insolación el lunes las placas podrán asentarse ligeramente pero hay que tener cuidado porque pasarán a poder caer a nuestro paso. La nieve granulada existente, que se concentra en umbrías resguardadas del viento, por debajo de 2400 m, queda enterrada por las placas y puede dar paso a caídas naturales de placas, con capacidad de enterrar a una persona, debido a esta débil capa.

Distribución del manto nivoso

Hay nieve en el suelo por encima de 1.600-1.700 m. Es esquiable a partir de unos 1700 m. El manto nivoso presenta grosores muy excedentarios para la época del año. En lugares no afectados por el viento los grosores oscilan entre 85-105 cm a unos 2.000 my más de 150 cm por encima de 2.400 m.

Tendencia para las próximas 48-72h

Se prevé una mejora de la situación de las placas de viento, pero la situación de capa débil persistente se mantendrá. Peligro EN PROGRESIVO DESCENSO

El próximo boletín será emitido el día 2026-03-16

5 MUY FUERTE	4 FUERTE	3 NOTABLE	2 LIMITADO	1 DÉBIL

EAWS EUROPEAN AVALANCHE WARNING SERVICES