Bulletin d'estimation du risque d'avalanche

(valable en dehors des pistes balisées et ouvertes)

MASSIF : Cinto Rotondo

Rédigé le samedi 14 mars 2026 à 15h

Estimation des risques pour le : DIMANCHE 15 MARS

DÉPARTS POSSIBLES EN NEIGE FRAÎCHE ET HUMIDE, PETITES INSTABILITÉS EN ALTITUDE

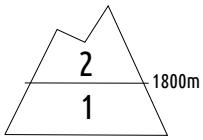

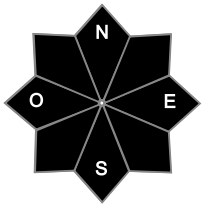

Au-dessus de 1800m indice de risque limité, plus bas indice faible.

Départs spontanés : Sous les précipitations, départs en neige fraîche ou humide

Déclenchements provoqués : Petites plaques à vent en altitude, risque de départs ponctuels sous les skis en neige humide

Indices de risque : 5 très fort - 4 fort - 3 marqué - 2 limité - 1 faible -- En noir : les pentes les plus dangereuses

Stabilité du manteau neigeux

Situation avalancheuse typique : neige fraîche neige humide

De nouvelles chutes de neige, 10 à 20 cm se produisent dans la nuit de samedi à dimanche au-dessus de 1800m.
Départs spontanés : Au-dessus de 1800 m, de nombreuses avalanches de neige fraîche taille 2 se produisent durant les chutes cette nuit. En dessous de 1800 m, de rares coulées de neige humide se produisent cette nuit et en versants Est dimanche après-midi.
Déclenchements provoqués : Les récentes petites plaques à vent formées dans les pentes orientées Ouest à Nord-Ouest, au-dessus de 1800 m, sont recouvertes par les nouvelles chutes de neige. Déclenchement possible par faible surcharge, pouvant engendrer une coulée ou avalanche de neige fraîche (taille 1 à 2). En dessous de 1800 m, départs ponctuels sous les skis ou raquettes en neige humide, notamment dans les pentes raides et ensoleillées.
Autres : Nombreuses surfaces glacées souvent près des crêtes ventées.

Qualité de la neige

Qualification de l'enneigement : L'enneigement est excellent pour la saison au-dessus de 1600 m. Sur la Maniccia, à 2400 m d'altitude dans le massif du Rotondo, on relève plus de 3 mètres de hauteur de neige totale.
Limite d'enneigement skiable : 1500 à 1600 m selon le versant.
État de la neige : Le manteau neigeux est à présent tassé et bien consolidé. En dessous de 1800 m, la pluie a humidifié le manteau sur toute son épaisseur, la neige y est souvent lourde et humide. Au-dessus de 1800 à 2000 m, le refroidissement a permis la consolidation des couches de neige humide enfouies. Des croûtes épaisses se sont formées, les surfaces dures et glacées sont maintenant recouvertes d'une récente couche de neige fraîche.
On observe de nombreuses zones de neige colorée avec les dernières remontées de sable. À noter également la présence de **corniches parfois volumineuses**.

Aperçu météo pour le dimanche 15 mars

	nuit	matin	après-midi	soir

Temps très nuageux et venté, averses de neige sur l'Est du massif.

Pluie-Neige	1 300 m	1 500 m	1 500 m	
Iso 0 °C	1 600 m	1 800 m	1 800 m	2 300 m
Vent 1500 m	↑ 35 km/h	← 35 km/h	← 50 km/h	↙ 30 km/h
Vent 3000 m	↑ 45 km/h	← 45 km/h	← 60 km/h	↙ 35 km/h

Épaisseur de neige hors-piste

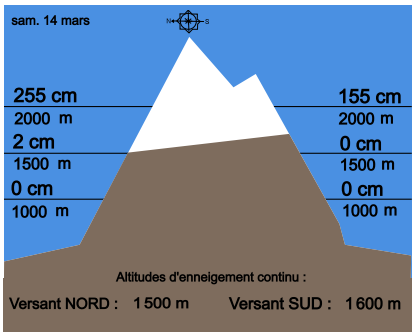

Précipitations à 1800 m

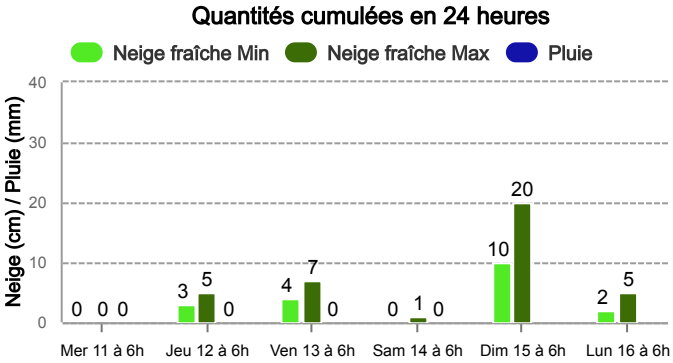

Tendance du lundi 16 mars

Indice de risque limité

Retour du soleil et de la douceur. Maintien d'un risque limité.

Pour consulter la vigilance en cours, veuillez vous rendre sur le site https://vigilance.meteofrance.fr/fr

Météo-France - 73 avenue de Paris, 94165 Saint-Mandé cedex - Contact : contact@meteo.fr

Rédigé par Météo-France avec la contribution des observateurs du réseau nivo-météorologiques. Partenariat : ANMSM (Maires de Stations de Montagne), DSF (Domaines Skiables de France), ADSP (Directeurs de Pistes et de la Sécurité des Stations de Sports d'Hiver) et autres acteurs de la montagne.

Bulletin neige & avalanches par téléphone au **0 892 68 10 20** Service 0,35 € / min + prix appel

RÉPUBLIQUE FRANÇAISE
Liberté Égalité Fraternité

METEO FRANCE
À VOS CÔTÉS, DANS UN CLIMAT QUI CHANGE

Bulletin d'estimation du risque d'avalanche

(valable en dehors des pistes balisées et ouvertes)

MASSIF : Cinto Rotondo

Rédigé le samedi 14 mars 2026 à 15h

Conditions nivo-météo des 7 derniers jours

	dim. 08/03				lun. 09/03				mar. 10/03				mer. 11/03				jeu. 12/03				ven. 13/03				sam. 14/03			
	03h	09h	15h	21h	03h	09h	15h	21h	03h	09h	15h	21h	03h	09h	15h	21h	03h	09h	15h	21h	03h	09h	15h	21h	03h	09h	15h	21h
Météo																												
Vent (km/h)	15	10	15	10	10	10	15	25	20	40	30	20	20	30	40	40	30	30	30	20	20	10	10	5	10	30	65	45
à 3000m																												
Vent (km/h)	10	5	10	0	5	5	10	15	15	20	20	10	15	20	25	30	20	10	20	15	15	15	15	5	10	25	50	35
à 1500m																												

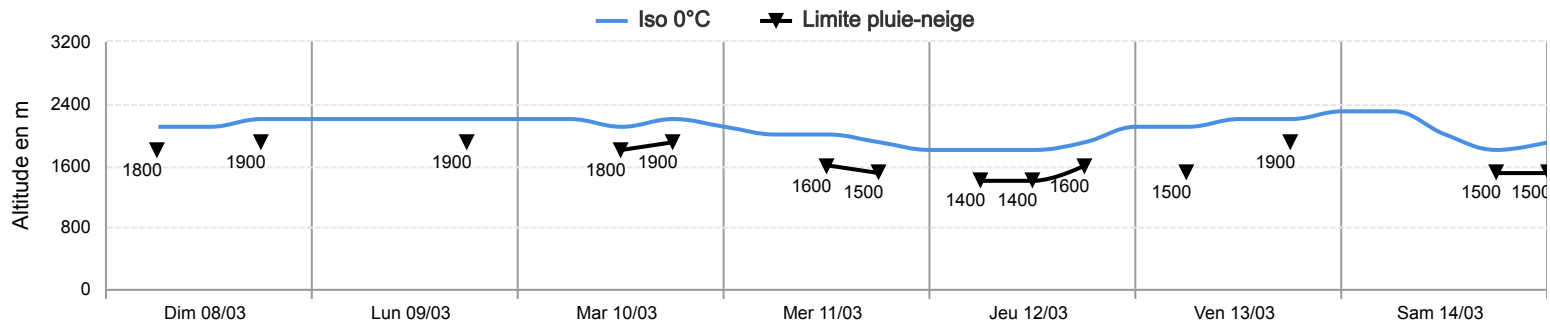



Risque d'avalanche	dim. 08/03	lun. 09/03	mar. 10/03	mer. 11/03	jeu. 12/03	ven. 13/03	sam. 14/03
	1	1	1	1	1	1	2

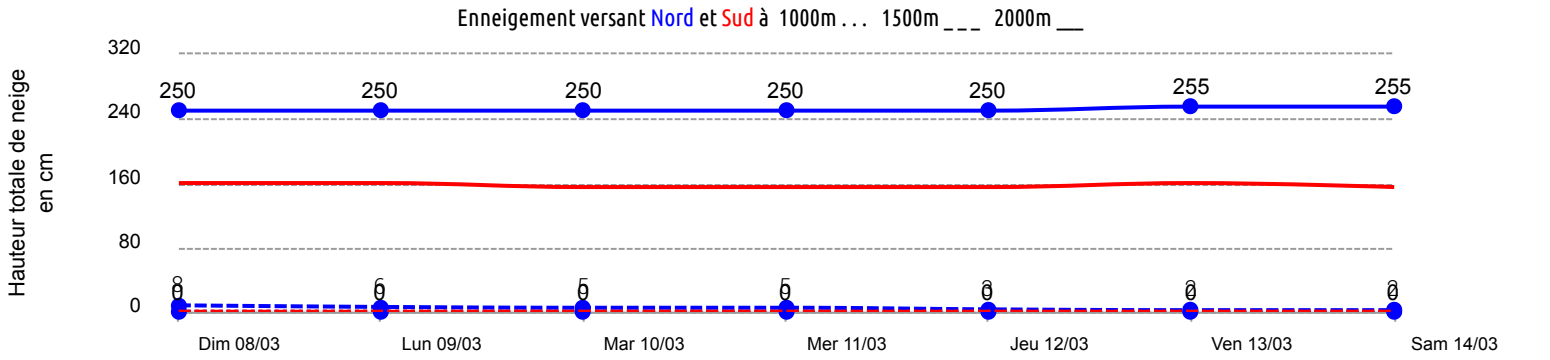

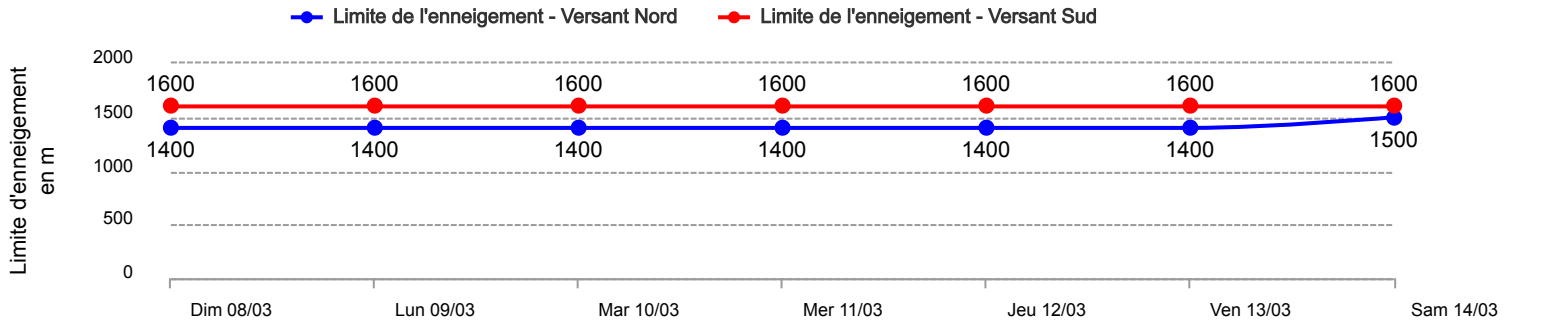

Pour consulter la vigilance en cours, veuillez vous rendre sur le site https://vigilance.meteofrance.fr/fr

Météo-France - 73 avenue de Paris, 94165 Saint-Mandé cedex - Contact : contact@meteo.fr

Bulletin neige & avalanches par téléphone au

0 892 68 10 20 Service 0,35 € / min + prix appel

Rédigé par Météo-France avec la contribution des observateurs du réseau nivo-météorologiques. Partenariat : ANMSM (Maires de Stations de Montagne), DSF (Domaines Skiables de France), ADSP (Directeurs de Pistes et de la Sécurité des Stations de Sports d'Hiver) et autres acteurs de la montagne.