RÉPUBLIQUE FRANÇAISE
Liberté Égalité Fraternité

METEO FRANCE
À VOS CÔTÉS, DANS UN CLIMAT QUI CHANGE

Bulletin d'estimation du risque d'avalanche
(valable en dehors des pistes balisées et ouvertes)
MASSIF : Capcir Puymorens

Rédigé le samedi 14 mars 2026 à 16h

Estimation des risques pour le : DIMANCHE 15 MARS

NOMBREUSES INSTABILITÉS DANS LA NEIGE RÉCENTE

3

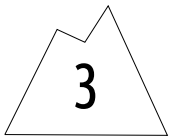

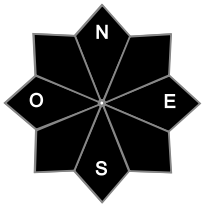

Indice de risque marqué.

Départs spontanés : Par surcharge du au transport de neige par le vent

Déclenchements provoqués : Nombreuses plaques facilement déclenchables

Indices de risque : 5 très fort - 4 fort - 3 marqué - 2 limité - 1 faible -- En noir : les pentes les plus dangereuses

Stabilité du manteau neigeux

Situation avalancheuse typique : neige fraîche neige ventée

Déclenchements provoqués :
Nombreuses structures de plaques facilement déclenchables dans la neige récente. Elles donneront principalement des avalanches de taille 1 à 2. Dans un large secteur sud, elles pourront localement donner des avalanches de taille 3 avec des accumulations plus importantes dues au transport qui perdure toute la journée. Ces plaques seront plutôt dures dans les zones ventées, plutôt friables dans des zones un peu plus protégées. La couche fragile est majoritairement constituée de neige fraiche moins ventée. Localement, il est possible que des grains facettés ou du givre de surface formés lors des nuits claires du début de semaine puissent aussi jouer ce rôle. On trouvera les accumulations les plus importantes dans les secteurs proches de l'Ariège.
(Observables : traces d'avalanches récentes, fissures sous les skis, affaissement accompagné de 'whoomf', signes de transport par le vent)

Départs spontanés :
- Départs spontanés linéaires attendus par surcharge d'une couche fragile présente au sein ou à la base de la couche de neige fraîche. En effet, malgré l'arrêt des précipitations dans la matinée, le transport par le vent restera efficace dans une neige qui reste froide et légère. Ces départs pourront conduire à des avalanches de taille 2, rarement 3 (grande) dans les accumulations les plus importantes (cf déclenchements provoqués).
(Observables : transport de neige par le vent)
- Départs ponctuels possibles en pente raide ensoleillée avec le retour des éclaircies. Avalanches de surface de taille 1 à 2, emportant la neige récente.

Autres :
Températures froides accentuées par le vent de nord-ouest à nord.

Qualité de la neige

Enneigement :
Après plusieurs hivers déficitaires, l'enneigement sur le massif est cette année largement excédentaire.
Les chutes de neige de la nuit ont encore donné une petite dizaine de cm. Sur le total de l'épisode qui a débuté dans la nuit de vendredi à samedi, une trentaine de cm sont tombés en altitude, mais les cumuls sont très hétérogènes à cause du vent.

Limites skiables :
Dimanche matin, on pourra envisager de chausser les skis dès 1300m en terrain herbeux, mais sans véritable sous-couche en dessous de 1500m en versants froids, 1700/1800m en versants Sud.

État de la neige :
Neige froide, déposée sur un fond souvent dur là où de la neige était présente avant les chutes. En surface, cette neige sera frittée à cartonnée près des crêtes, cols et sommets, restant meuble à l'abri du vent (clairières et combes déventées notamment). Elle s'humidifiera avec le soleil en journée, mais uniquement à basse altitude, et dans les pentes raides.

Aperçu météo pour le dimanche 15 mars

	nuit	matin	après-midi	soir
Conditions hivernales				
Pluie-Neige	600 m	500 m		
Iso 0 °C	1 000 m	1 000 m	1 400 m	1 700 m
Vent 2000 m	75 km/h	100 km/h	80 km/h	50 km/h
Vent 3000 m	95 km/h	115 km/h	85 km/h	65 km/h

Pour consulter la vigilance en cours, veuillez vous rendre sur le site https://vigilance.meteofrance.fr/fr

Météo-France - 73 avenue de Paris, 94165 Saint-Mandé cedex - Contact : contact@meteo.fr

Rédigé par Météo-France avec la contribution des observateurs du réseau nivo-météorologiques. Partenariat : ANMSM (Maires de Stations de Montagne), DSF (Domaines Skiables de France), ADSP (Directeurs de Pistes et de la Sécurité des Stations de Sports d'Hiver) et autres acteurs de la montagne.

Bulletin neige & avalanches par téléphone au
0 892 68 10 20 Service 0,35 € / min + prix appel

Bulletin d'estimation du risque d'avalanche

(valable en dehors des pistes balisées et ouvertes)

MASSIF : Capcir Puymorens

Rédigé le samedi 14 mars 2026 à 16h

Épaisseur de neige hors-piste

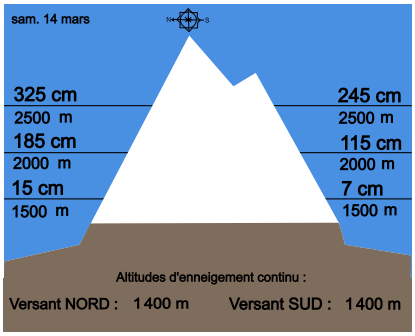

Précipitations à 1800 m

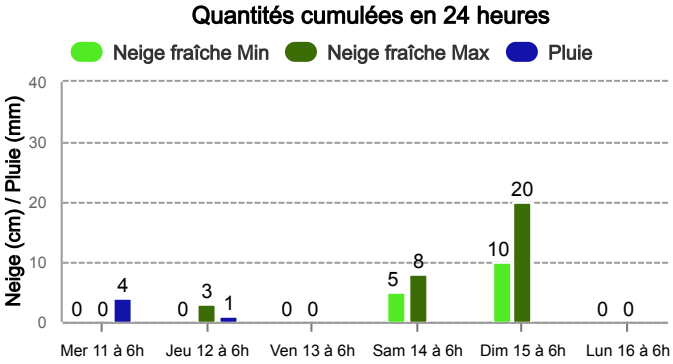

Tendance du lundi 16 mars

Indice de risque marqué

Stabilisation lente des structures de plaque, transport encore actif en altitude

Pour consulter la vigilance en cours, veuillez vous rendre sur le site https://vigilance.meteofrance.fr/fr

Météo-France - 73 avenue de Paris, 94165 Saint-Mandé cedex - Contact : contact@meteo.fr

Rédigé par Météo-France avec la contribution des observateurs du réseau nivo-météorologiques. Partenariat : ANMSM (Maires de Stations de Montagne), DSF (Domaines Skiables de France), ADSP (Directeurs de Pistes et de la Sécurité des Stations de Sports d'Hiver) et autres acteurs de la montagne.

Bulletin neige & avalanches par téléphone au

0 892 68 10 20 Service 0,35 € / min + prix appel

RÉPUBLIQUE FRANÇAISE
Liberté Égalité Fraternité

METEO FRANCE
À VOS CÔTÉS, DANS UN CLIMAT QUI CHANGE

Bulletin d'estimation du risque d'avalanche

(valable en dehors des pistes balisées et ouvertes)

MASSIF : Capcir Puymorens

Rédigé le samedi 14 mars 2026 à 16h

Conditions nivo-météo des 7 derniers jours

	dim. 08/03				lun. 09/03				mar. 10/03				mer. 11/03				jeu. 12/03				ven. 13/03				sam. 14/03			
	03h	09h	15h	21h	03h	09h	15h	21h	03h	09h	15h	21h	03h	09h	15h	21h	03h	09h	15h	21h	03h	09h	15h	21h	03h	09h	15h	21h
Météo																												
Vent (km/h)	30	25	25	20	20	15	15	15	15	15	20	15	15	25	40	55	40	30	25	25	25	25	30	40	50	50	55	70
à 3000m																												
Vent (km/h)	20	20	15	10	10	10	10	5	5	5	10	10	10	10	25	35	30	20	15	15	15	15	15	25	30	30	35	45
à 2000m																												

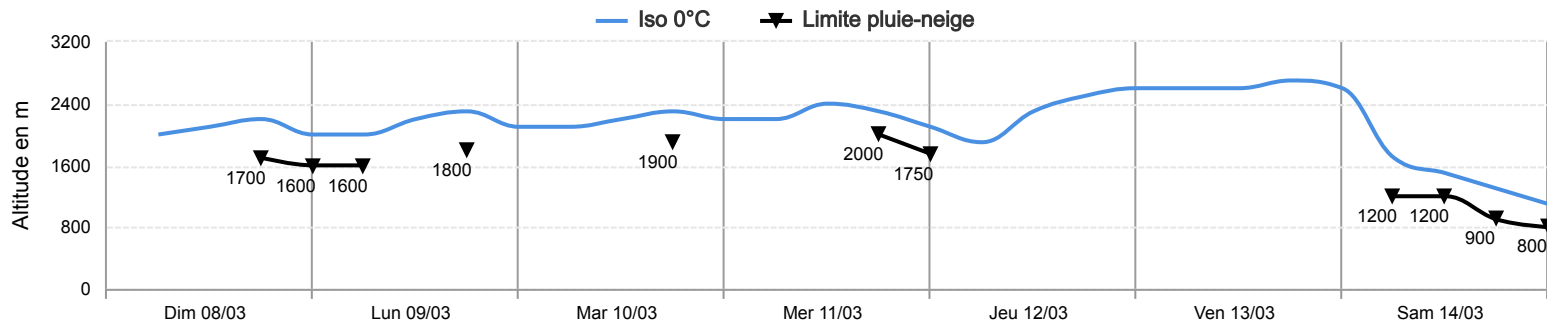

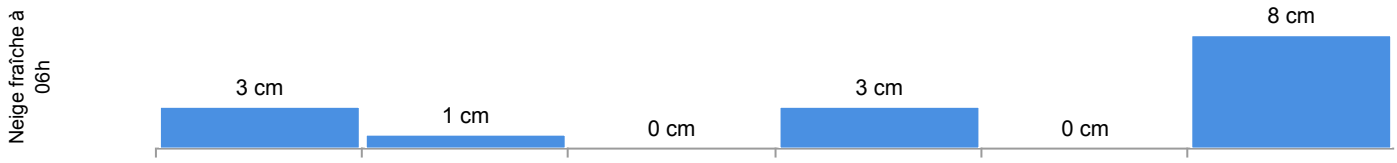

Risque d'avalanche	dim. 08/03	lun. 09/03	mar. 10/03	mer. 11/03	jeu. 12/03	ven. 13/03	sam. 14/03
	3	3	2	2	2	2	3

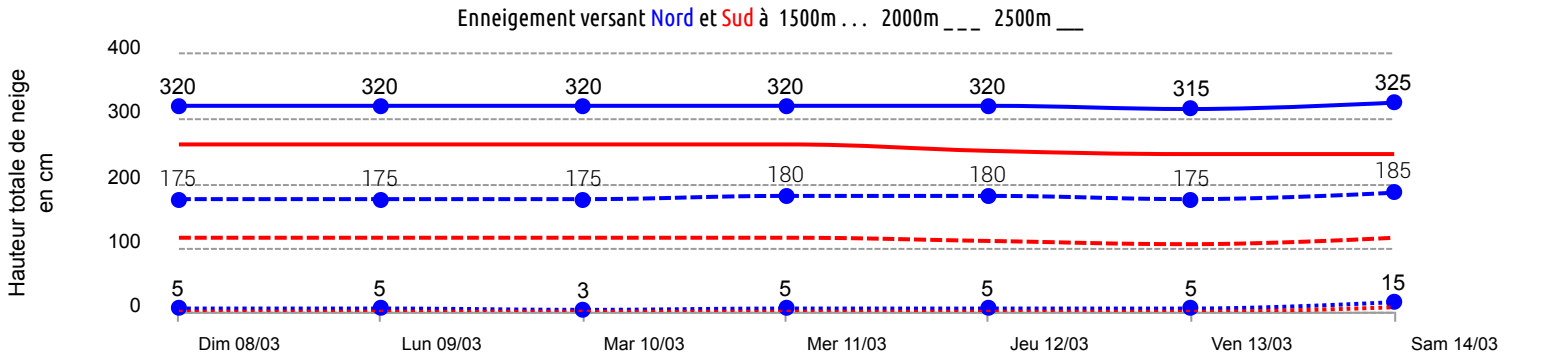

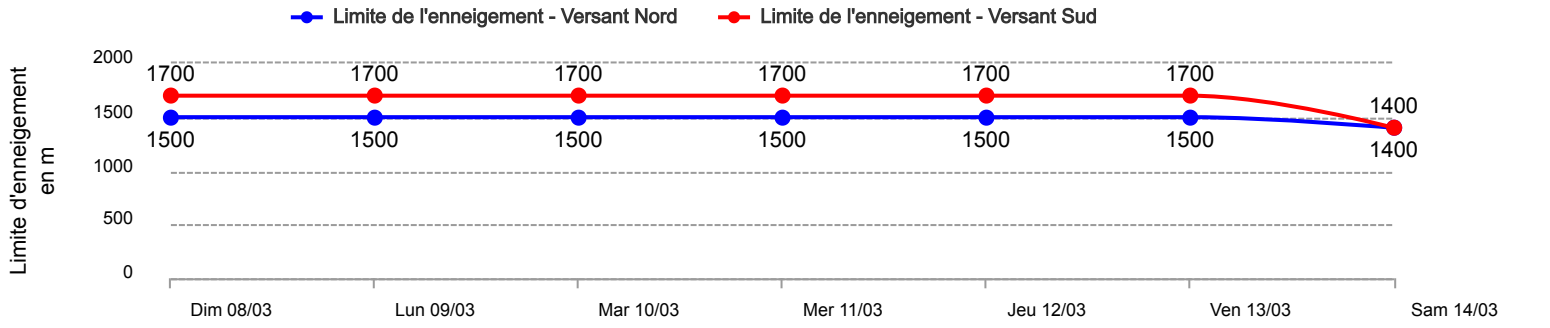

Pour consulter la vigilance en cours, veuillez vous rendre sur le site https://vigilance.meteofrance.fr/fr

Météo-France - 73 avenue de Paris, 94165 Saint-Mandé cedex - Contact : contact@meteo.fr

Rédigé par Météo-France avec la contribution des observateurs du réseau nivo-météorologiques. Partenariat : ANMSM (Maires de Stations de Montagne), DSF (Domaines Skiables de France), ADSP (Directeurs de Pistes et de la Sécurité des Stations de Sports d'Hiver) et autres acteurs de la montagne.

Bulletin neige & avalanches par téléphone au
0 892 68 10 20 Service 0,35 € / min + prix appel