Bulletin d'estimation du risque d'avalanche

(valable en dehors des pistes balisées et ouvertes)

MASSIF : Chablais

Rédigé le samedi 14 mars 2026 à 16h

Estimation des risques pour le : DIMANCHE 15 MARS

INSTABILITÉS DANS LA NEIGE DE SURFACE.

3

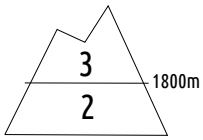

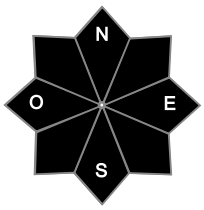

Au-dessus de 1800m indice de risque marqué, plus bas indice limité.

Départs spontanés : Quelques avalanches humides au soleil.

Déclenchements provoqués : Plaques friables dans la neige fraîche.

Indices de risque : 5 très fort - 4 fort - 3 marqué - 2 limité - 1 faible -- En noir : les pentes les plus dangereuses

Stabilité du manteau neigeux

Situation avalancheuse typique : neige fraîche — couche fragile persistante

Déclenchements provoqués :

* **Plaques friables temporaires** dans la neige fraîche. Elles sont facilement **déclenchables au passage d'un skieur**. Principalement de taille 1 et 2 (petites et moyennes) avec des cassures de 25/30 cm. On les retrouve en toutes orientations, car elles sont liées aux chutes de neige de la veille. Attention, des plaques à vent peuvent se cacher dans les zones d'accumulation, mais elles sont cachées sous la neige fraîche.
* Au-dessus de 1800m en NW/N/NE et 2500m ailleurs, une couche fragile est encore présente sous 50/60 cm de neige, mais très difficilement sollicitable. Dans le cas d'une avalanche en cascade, elle pourrait être sollicitée et engendrer des avalanches de taille 3 (grandes).

Départs spontanés :

* Quelques avalanches de neige humide sont attendues en matinée sous le soleil, principalement sous 1800/2000 m. Taille 1 à 2.
* Au fil de la journée, des **reptations** peuvent s'ouvrir et ainsi, des avalanches de fond sont possibles à toute heure et en tout versant. Taille 2.

Qualité de la neige

Enneigement :

Il est correct pour la saison. En matinée, on retrouve de la neige dès 800m, pas vraiment skiable et qui fondra très rapidement en matinée. On retrouve un manteau réellement skiable à partir de 1200m en Nord et 1500m en Sud.

Qualité de la neige ce dimanche :

- On retrouve une couche de neige fraîche présente en surface (20/25 cm à 2000m). Cette neige est d'aspect léger et poudreux, et s'humidifie rapidement en sud sous 1800m. En versant nord, elle a tendance à rester froide plus longtemps. Elle repose sur un manteau encore froid en ubac et en altitude, et sur un manteau humide en sud sous 2500 m.

Aperçu météo pour le dimanche 15 mars

	nuit	matin	après-midi	soir
Pluie-Neige	600 m			
Iso 0 °C	1 000 m	1 400 m	1 300 m	1 500 m
Vent 2000 m	40 km/h	15 km/h	5 km/h	10 km/h
Vent 2500 m	55 km/h	25 km/h	15 km/h	15 km/h

Matinée bien ensoleillée avec une relative fraîcheur. L'après-midi, le ciel se recouvre et les nuages accrochent facilement le relief et les sommets.

Épaisseur de neige hors-piste

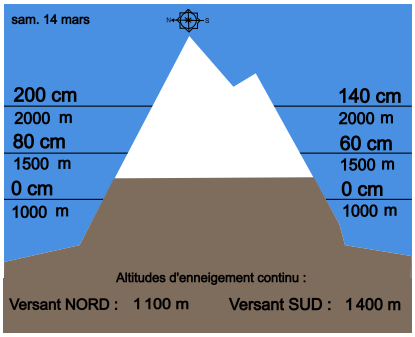

Précipitations à 1800 m

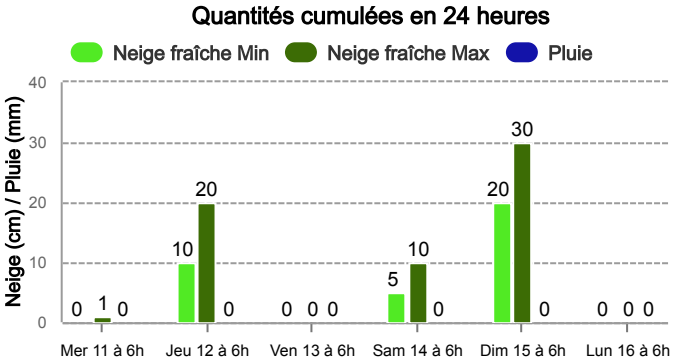

Tendance du lundi 16 mars

3

Indice de risque marqué

Les instabilités temporaires se stabilisent. Avec le retour du soleil, des coulées au fil de l'ensoleillement sont attendues.

Pour consulter la vigilance en cours, veuillez vous rendre sur le site https://vigilance.meteofrance.fr/fr

Météo-France - 73 avenue de Paris, 94165 Saint-Mandé cedex - Contact : contact@meteo.fr

Rédigé par Météo-France avec la contribution des observateurs du réseau nivo-météorologiques. Partenariat : ANMSM (Maires de Stations de Montagne), DSF (Domaines Skiables de France), ADSP (Directeurs de Pistes et de la Sécurité des Stations de Sports d'Hiver) et autres acteurs de la montagne.

Bulletin neige & avalanches par téléphone au

0 892 68 10 20 Service 0,35 € / min + prix appel

RÉPUBLIQUE FRANÇAISE
Liberté Égalité Fraternité

METEO FRANCE
À VOS CÔTÉS, DANS UN CLIMAT QUI CHANGE

Bulletin d'estimation du risque d'avalanche

(valable en dehors des pistes balisées et ouvertes)

MASSIF : Chablais

Rédigé le samedi 14 mars 2026 à 16h

Conditions nivo-météo des 7 derniers jours

	dim. 08/03				lun. 09/03				mar. 10/03				mer. 11/03				jeu. 12/03				ven. 13/03				sam. 14/03			
	03h	09h	15h	21h	03h	09h	15h	21h	03h	09h	15h	21h	03h	09h	15h	21h	03h	09h	15h	21h	03h	09h	15h	21h	03h	09h	15h	21h
Météo																												
Vent (km/h)	10	10	10	15	10	10	10	15	15	30	40	40	40	50	60	45	30	20	5	10	40	45	50	70	70	35	25	50
à 2500m																												
Vent (km/h)	5	5	5	5	5	5	5	10	10	20	30	30	30	40	50	30	20	10	5	5	25	40	40	60	50	20	15	40
à 2000m																												

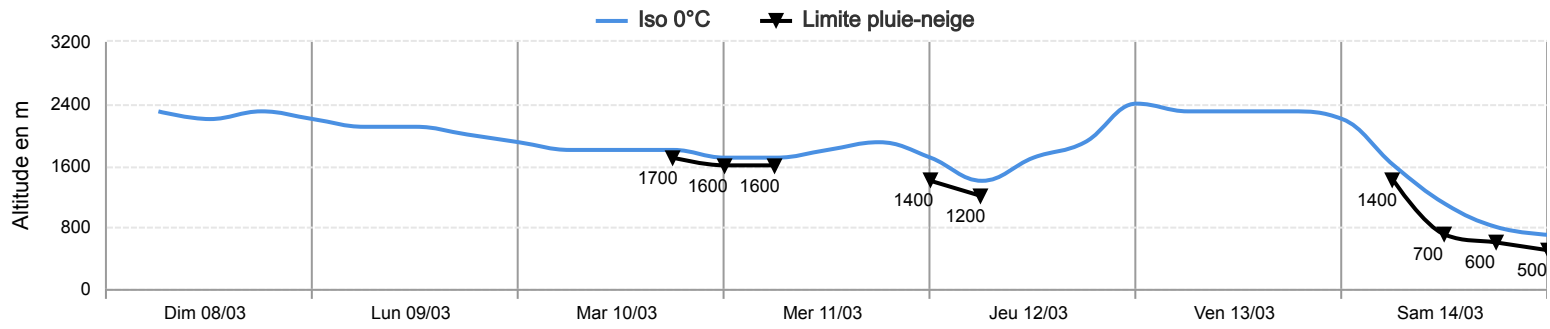

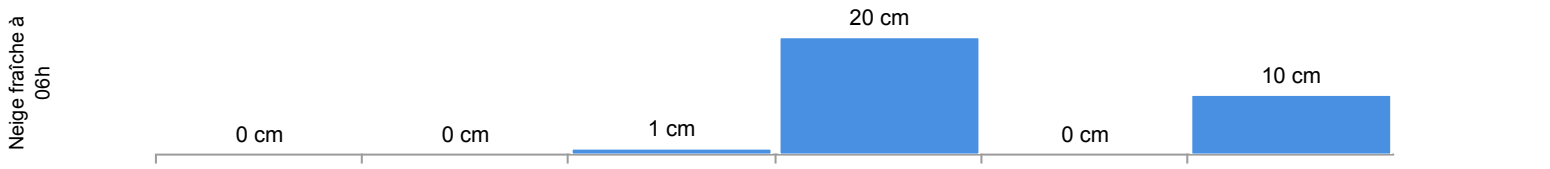

Risque d'avalanche	dim. 08/03	lun. 09/03	mar. 10/03	mer. 11/03	jeu. 12/03	ven. 13/03	sam. 14/03
	2	2	2	1	2	2	3

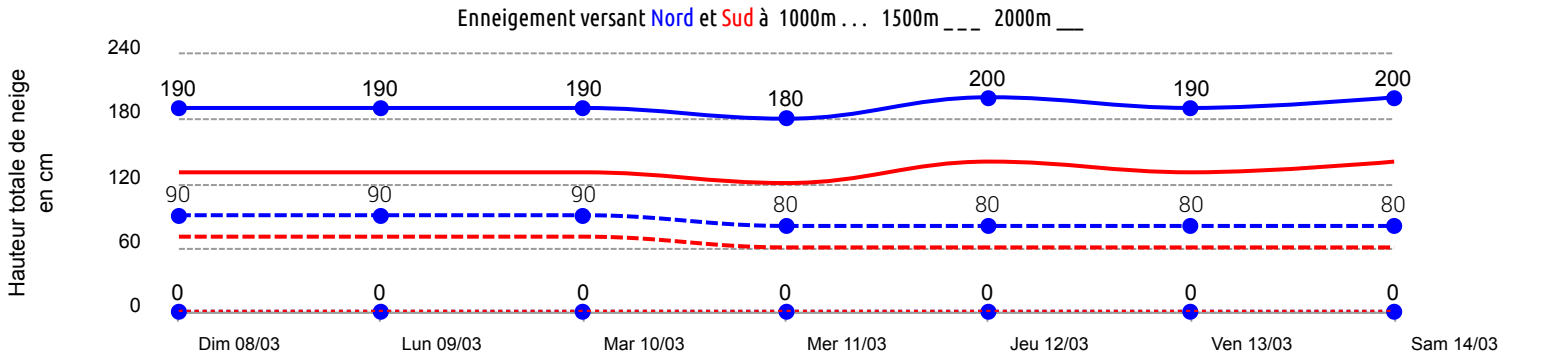

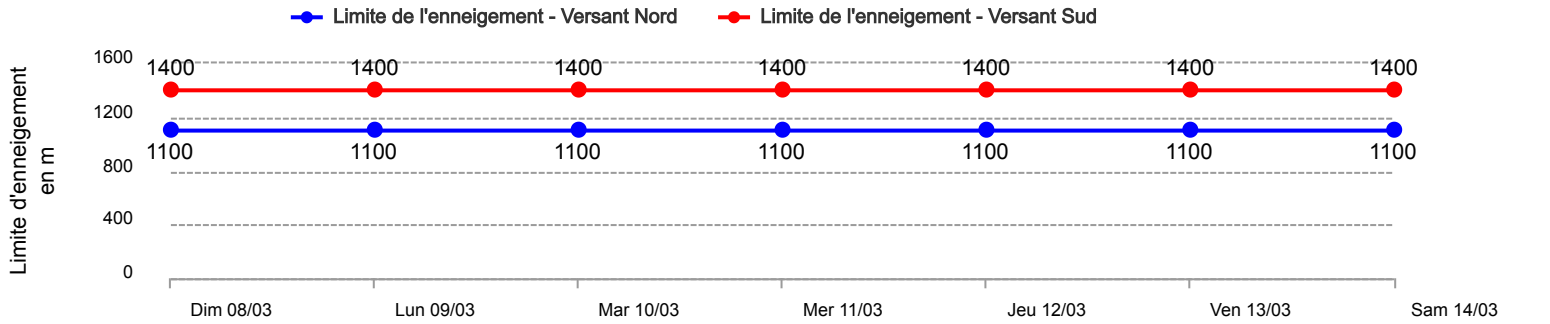

Pour consulter la vigilance en cours, veuillez vous rendre sur le site https://vigilance.meteofrance.fr/fr

Météo-France - 73 avenue de Paris, 94165 Saint-Mandé cedex - Contact : contact@meteo.fr

Rédigé par Météo-France avec la contribution des observateurs du réseau nivo-météorologiques. Partenariat : ANMSM (Maires de Stations de Montagne), DSF (Domaines Skiables de France), ADSP (Directeurs de Pistes et de la Sécurité des Stations de Sports d'Hiver) et autres acteurs de la montagne.

Bulletin neige & avalanches par téléphone au
0 892 68 10 20 Service 0,35 € / min + prix appel