Bulletin d'estimation du risque d'avalanche
(valable en dehors des pistes balisées et ouvertes)

MASSIF : Devoluy

Rédigé le samedi 14 mars 2026 à 16h

Estimation des risques pour le : DIMANCHE 15 MARS

NOMBREUSES INSTABILITÉS SUPERFICIELLES DANS LA NEIGE RÉCENTE VENTÉE

3

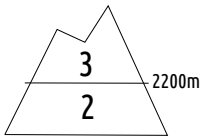

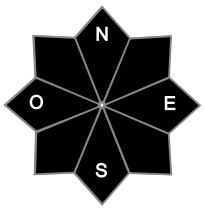

Au-dessus de 2200m indice de risque marqué, plus bas indice limité.

Départs spontanés : avalanches de taille petite à moyenne sous l'effet du vent

Déclenchements provoqués : instabilités facilement déclenchables en altitude

Indices de risque : 5 très fort - 4 fort - 3 marqué - 2 limité - 1 faible -- En noir : les pentes les plus dangereuses

Stabilité du manteau neigeux

Situation avalancheuse typique : neige ventée

Déclenchements provoqués : instabilités plus nombreuses au-dessus de 2200 m environ. Possibles en toute orientation, plutôt dans les zones d'accumulation par le vent. Facilement déclenchables par un seul skieur, ces plaques sont d'aspect durci par le vent, et plutôt identifiables. Elles ne mobilisent généralement que la chute de neige de samedi, et génèrent des avalanches de taille petite (taille 1) à moyenne (taille 2) dans les zones de plus forte accumulation par le vent.
Sous 2000 m, les instabilités, également déclenchables par un seul skieur, sont moins nombreuses et restent superficielles (taille 1).

Départs spontanés : plaques à vent de taille petite à moyenne. Petits départs ponctuels de neige récente humide sous les éclaircies en journée.

Qualité de la neige

L'enneigement est encore légèrement excédentaire pour un mois de mars sur le massif. Les fonds de vallée ont temporairement retrouvé un aspect hivernal suite à la chute ce samedi.
Hauteurs de neige observées : 220 cm à 2000 m à Superdévoluy.

Limite d'enneigement skiable : vers 1300 m en ubacs, 1700/1800 m en adrets pas trop raides.

État de la neige de surface : neige récente tombée humide sous 1800/2000 m, puis fortement densifiée voire durcie par le fort vent de nord. Elle repose généralement sur un fond dur, printanier ou durci par le vent.

Aperçu météo pour le dimanche 15 mars

	nuit	matin	après-midi	soir
	Averses de neige résiduelles samedi soir, puis fort vent de nord, se poursuivant dimanche			
Pluie-Neige	600 m			
Iso 0 °C	1 100 m	1 600 m	1 900 m	1 900 m
Vent 2000 m	55 km/h	30 km/h	15 km/h	10 km/h
Vent 3000 m	30 km/h	30 km/h	20 km/h	5 km/h

Épaisseur de neige hors-piste

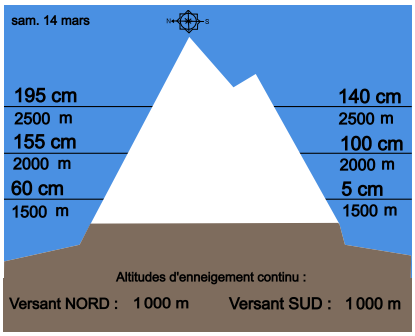

Précipitations à 1800 m

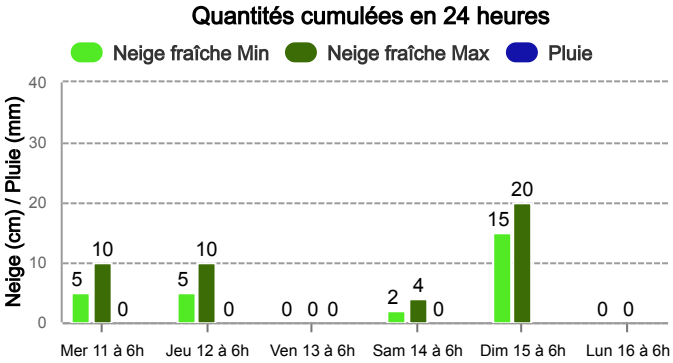

Tendance du lundi 16 mars

3

Indice de risque marqué

Stabilisation progressive des plaques formées ce week-end. Maintien d'un risque marqué en altitude.

Pour consulter la vigilance en cours, veuillez vous rendre sur le site https://vigilance.meteofrance.fr/fr

Météo-France - 73 avenue de Paris, 94165 Saint-Mandé cedex - Contact : contact@meteo.fr

Rédigé par Météo-France avec la contribution des observateurs du réseau nivo-météorologiques. Partenariat : ANMSM (Maires de Stations de Montagne), DSF (Domaines Skiables de France), ADSP (Directeurs de Pistes et de la Sécurité des Stations de Sports d'Hiver) et autres acteurs de la montagne.

Bulletin neige & avalanches par téléphone au 0 892 68 10 20 Service 0,35 € / min + prix appel

RÉPUBLIQUE FRANÇAISE
Liberté Égalité Fraternité

METEO FRANCE
À VOS CÔTÉS, DANS UN CLIMAT QUI CHANGE

Bulletin d'estimation du risque d'avalanche

(valable en dehors des pistes balisées et ouvertes)

MASSIF : Devoluy

Rédigé le samedi 14 mars 2026 à 16h

Conditions nivo-météo des 7 derniers jours

	dim. 08/03				lun. 09/03				mar. 10/03				mer. 11/03				jeu. 12/03				ven. 13/03				sam. 14/03			
	03h	09h	15h	21h	03h	09h	15h	21h	03h	09h	15h	21h	03h	09h	15h	21h	03h	09h	15h	21h	03h	09h	15h	21h	03h	09h	15h	21h
Météo																												
Vent (km/h)	30	25	25	30	25	30	40	50	40	25	15	15	15	25	30	40	50	50	30	15	15	20	25	40	70	5	20	35
à 3000m																												
Vent (km/h)	10	10	20	15	20	20	25	30	30	25	20	15	15	15	20	15	30	25	15	5	10	10	20	20	30	10	30	65
à 2000m																												

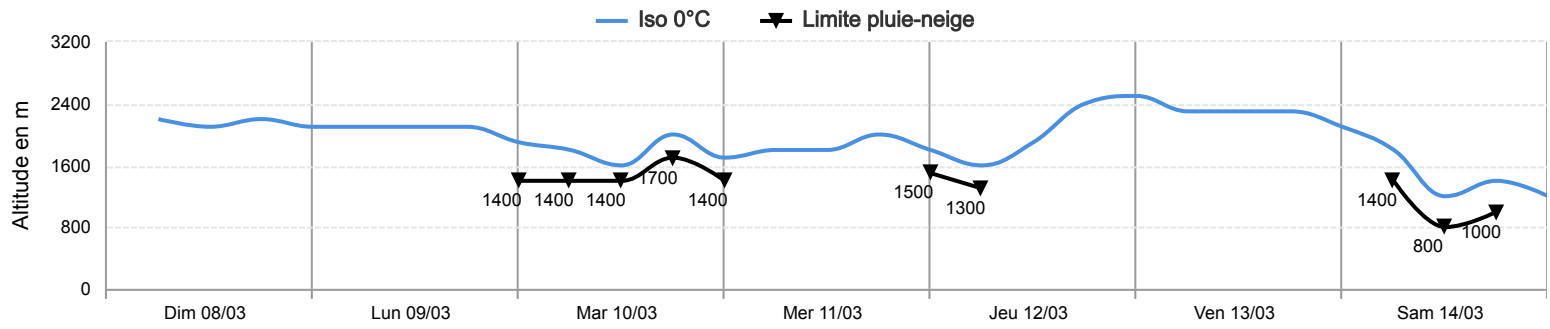

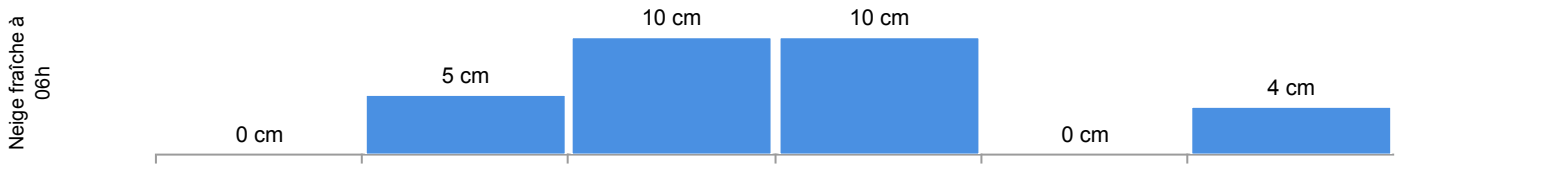

Risque d'avalanche	dim. 08/03	lun. 09/03	mar. 10/03	mer. 11/03	jeu. 12/03	ven. 13/03	sam. 14/03
	2	2	2	2	2	2	3

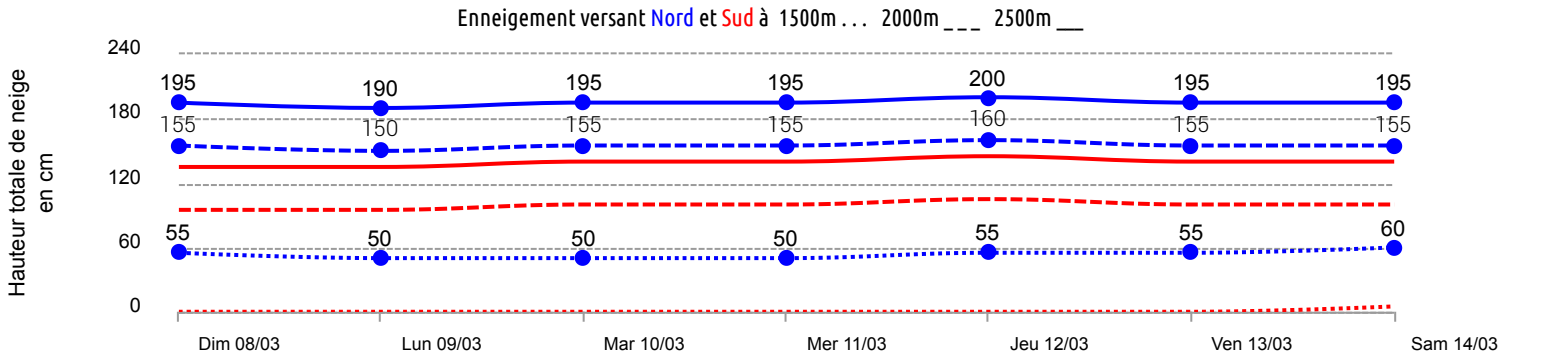

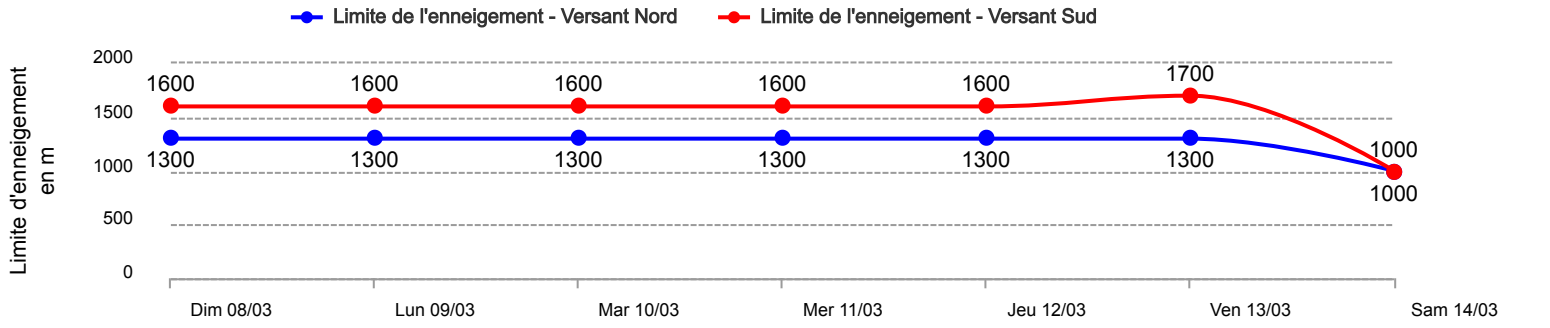

Pour consulter la vigilance en cours, veuillez vous rendre sur le site https://vigilance.meteofrance.fr/fr

Météo-France - 73 avenue de Paris, 94165 Saint-Mandé cedex - Contact : contact@meteo.fr

Rédigé par Météo-France avec la contribution des observateurs du réseau nivo-météorologiques. Partenariat : ANMSM (Maires de Stations de Montagne), DSF (Domaines Skiables de France), ADSP (Directeurs de Pistes et de la Sécurité des Stations de Sports d'Hiver) et autres acteurs de la montagne.

Bulletin neige & avalanches par téléphone au
0 892 68 10 20 Service 0,35 € / min + prix appel