RÉPUBLIQUE FRANÇAISE
Liberté Égalité Fraternité

METEO FRANCE
À VOS CÔTÉS, DANS UN CLIMAT QUI CHANGE

Bulletin d'estimation du risque d'avalanche
(valable en dehors des pistes balisées et ouvertes)
MASSIF : Haute-Maurienne

Rédigé le samedi 14 mars 2026 à 16h

Estimation des risques pour le : DIMANCHE 15 MARS

VARIATION DE VENT ET NEIGE RÉCENTE : QUELQUES INSTABILITÉS RÉACTIVES.

3

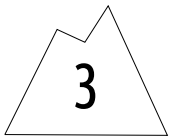

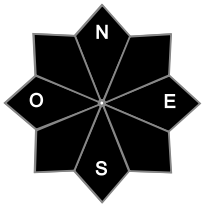

Indice de risque marqué.

Départs spontanés : purges avec les éclaircies, plaques sous le vent.

Déclenchements provoqués : quelques plaques réactives, d'aspect poudreux.

Indices de risque : 5 très fort - 4 fort - 3 marqué - 2 limité - 1 faible -- En noir : les pentes les plus dangereuses

Stabilité du manteau neigeux

Situation avalancheuse typique : neige ventée neige fraîche

Déclenchement provoqués : **quelques plaques facilement déclenchables** sont en place suite aux multiples variations de vent (encore en cours en matinée) sur la neige récente. Elles sont plus nombreuses et épaisses en allant vers la frontière Italienne. Elles sont d'aspect poudreux dans les pentes et plutôt dure près des crêtes. Elles sont plus réactives et épaisses en ubac où la neige était restée poudreuse (grains parfois anguleux). Avalanche de taille petite à moyenne, rarement grande en ubac d'altitude.
Au-dessus de 2400 m, préférentiellement en ubacs, ainsi que près des crêtes ou des croupes dégarnies (là où d'anciennes couches fragiles persistantes sont présentes et moins profondément enfouies), une grande avalanche est plus probable. Cassure pouvant dépasser 1 m.

Départs spontanés :
- Quelques petites purges dans les pentes raides, près des rochers, avec le retour du soleil à la mi-journée. Taille 1.
- Sous le vent des hautes crêtes, une rare plaque peut céder spontanément par surcharge par le transport de neige par le vent (jusqu'à la mi-journée). Taille 1 à 2.

Qualité de la neige

Enneigement : légèrement excédentaire pour la saison en moyenne montagne, mais en train de devenir déficitaire en basse montagne et en versants sud. Et très déficitaire en haute montagne près de la crête frontalière, voire carrément absent de certains cols ou faces très exposées au vent.

Limite skiable : encore skiable dès 1100/1200 m dans les prairies orientées nord, plutôt 1500/1600 m en sud pas trop raide.

Qualité de la neige : couche de neige fraîche légère de plus en plus conséquente avec l'altitude (20/30 cm vers 2500 m), parfois densifiée par le vent en surface ventée (risque de plaque!). Sous-couche dure en adret, voire très dure ou absente à haute altitude, près des crêtes. Épaisseur de neige meuble parfois importante en altitude.

Aperçu météo pour le dimanche 15 mars

	nuit	matin	après-midi	soir

Retour d'Est à l'agonie, très nuageux et neige faible. Rares éclaircies vers la mi-journée.

Pluie-Neige	500 m	900 m	1 200 m	
Iso 0 °C	900 m	1 300 m	1 700 m	1 400 m
Vent 2500 m	↘ 20 km/h	← 25 km/h	↖ 15 km/h	↘ 10 km/h
Vent 3500 m	← 25 km/h	← 40 km/h	↖ 20 km/h	→ 10 km/h

Épaisseur de neige hors-piste

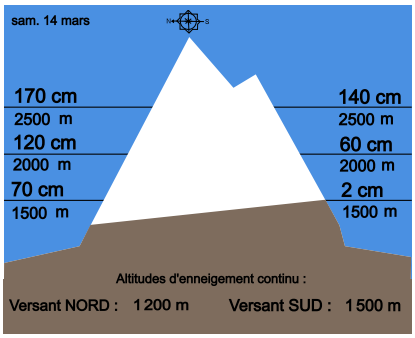

Précipitations à 1800 m

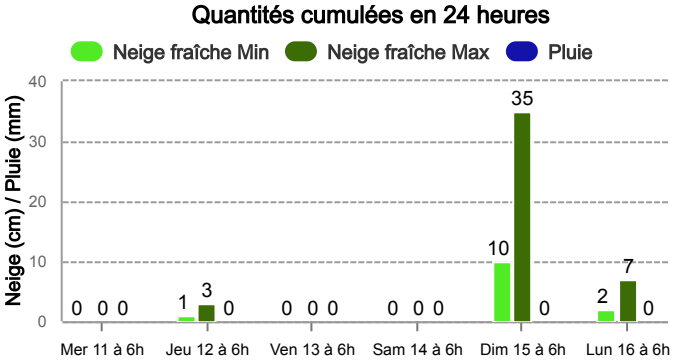

Tendance du lundi 16 mars

2

Indice de risque limité

Risque en baisse. Les instabilités issues de la neige récente est du vent se dissipent. Un peu d'activité attendue avec le retour du soleil.

Pour consulter la vigilance en cours, veuillez vous rendre sur le site https://vigilance.meteofrance.fr/fr

Météo-France - 73 avenue de Paris, 94165 Saint-Mandé cedex - Contact : contact@meteo.fr

Rédigé par Météo-France avec la contribution des observateurs du réseau nivo-météorologiques. Partenariat : ANMSM (Maires de Stations de Montagne), DSF (Domaines Skiables de France), ADSP (Directeurs de Pistes et de la Sécurité des Stations de Sports d'Hiver) et autres acteurs de la montagne.

Bulletin neige & avalanches par téléphone au
0 892 68 10 20 Service 0,35 € / min + prix appel

Bulletin d'estimation du risque d'avalanche

(valable en dehors des pistes balisées et ouvertes)

MASSIF : Haute-Maurienne

Rédigé le samedi 14 mars 2026 à 16h

Conditions nivo-météo des 7 derniers jours

	dim. 08/03				lun. 09/03				mar. 10/03				mer. 11/03				jeu. 12/03				ven. 13/03				sam. 14/03			
	03h	09h	15h	21h	03h	09h	15h	21h	03h	09h	15h	21h	03h	09h	15h	21h	03h	09h	15h	21h	03h	09h	15h	21h	03h	09h	15h	21h
Météo																												
Vent (km/h)	20	15	15	15	15	15	20	25	30	30	30	20	20	25	35	45	30	20	20	10	10	10	15	55	40	20	30	30
à 3500m																												
Vent (km/h)	20	15	15	15	15	15	20	30	25	20	15	10	10	10	25	35	20	10	10	5	5	5	10	40	30	10	25	25
à 2500m																												

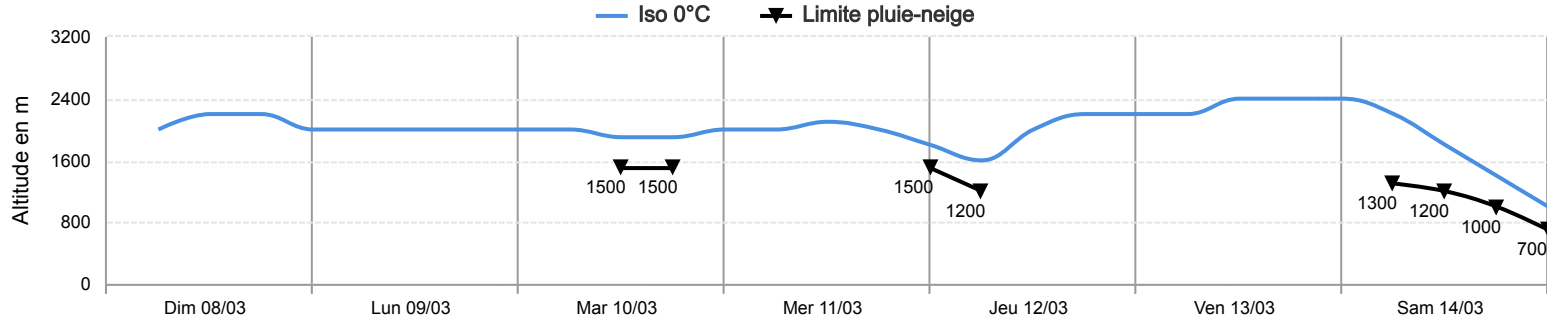

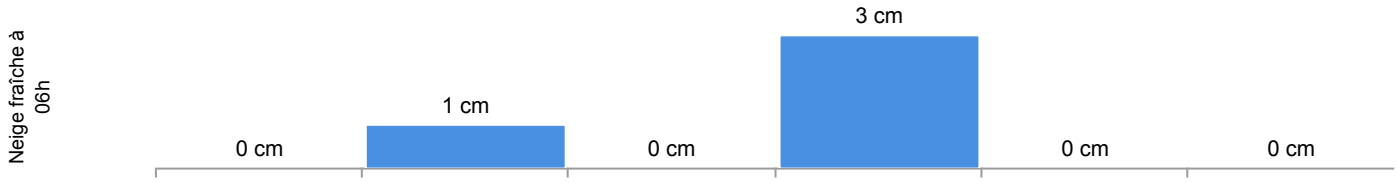

Risque d'avalanche	dim. 08/03	lun. 09/03	mar. 10/03	mer. 11/03	jeu. 12/03	ven. 13/03	sam. 14/03
	2	2	2	2	2	2	3

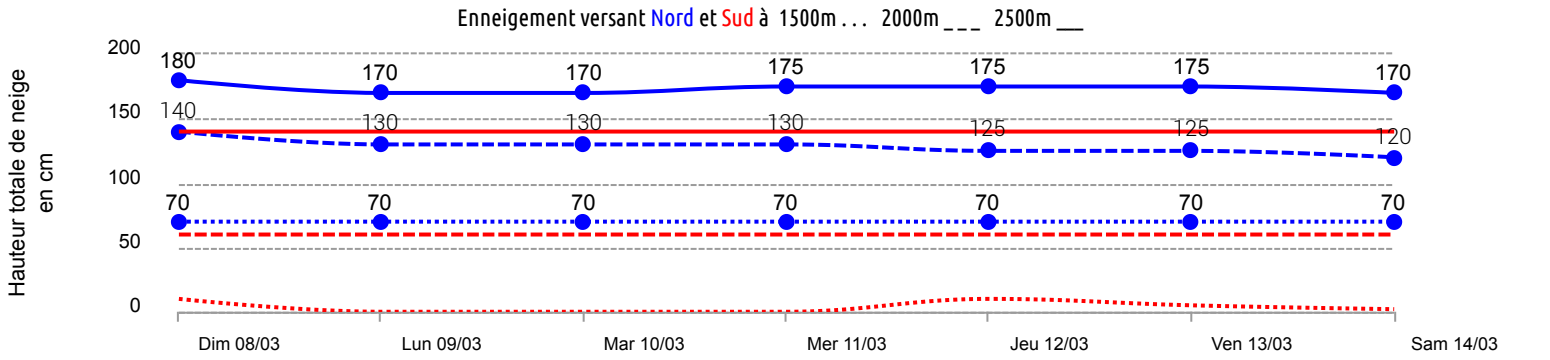

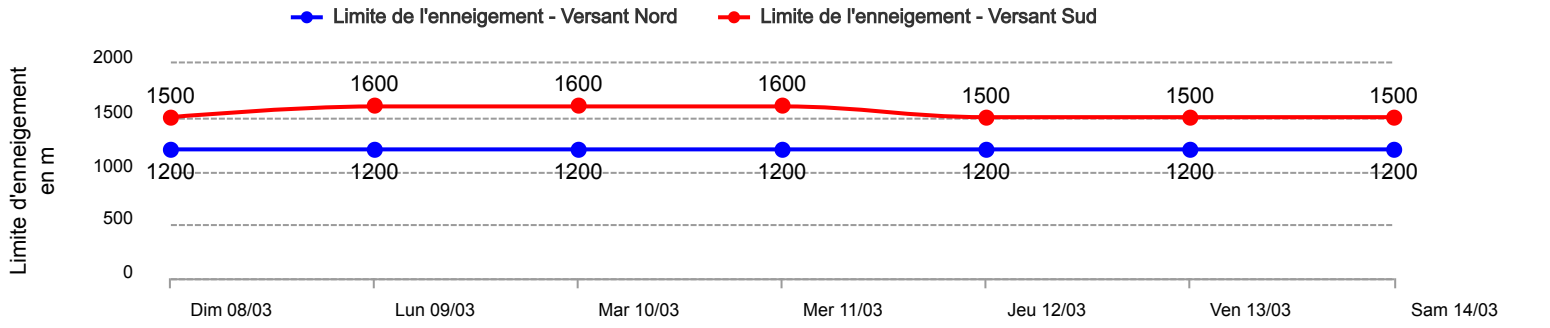

Pour consulter la vigilance en cours, veuillez vous rendre sur le site https://vigilance.meteofrance.fr/fr

Météo-France - 73 avenue de Paris, 94165 Saint-Mandé cedex - Contact : contact@meteo.fr

Rédigé par Météo-France avec la contribution des observateurs du réseau nivo-météorologiques. Partenariat : ANMSM (Maires de Stations de Montagne), DSF (Domaines Skiables de France), ADSP (Directeurs de Pistes et de la Sécurité des Stations de Sports d'Hiver) et autres acteurs de la montagne.

Bulletin neige & avalanches par téléphone au

0 892 68 10 20 Service 0,35 € / min + prix appel