Bulletin d'estimation du risque d'avalanche

(valable en dehors des pistes balisées et ouvertes)

MASSIF : Mercantour

Rédigé le samedi 14 mars 2026 à 16h

Estimation des risques pour le : DIMANCHE 15 MARS

INSTABILITÉ MARQUÉE DANS LA NEIGE FRAICHE VENTÉE. QUELQUES DÉPARTS NATUREL EN NEIGE FRAICHE OU HUMIDE.

3

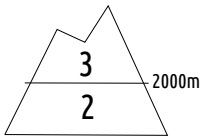

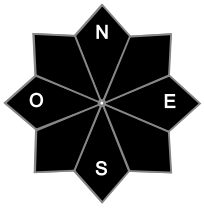

+nombreuses/épaisses

Au-dessus de 2000m indice de risque marqué, plus bas indice limité.

Départs spontanés : départs en neige fraiche à la frontière italienne, en neige humide au soleil ailleurs.

Déclenchements provoqués : nombreuses plaques faciles à déclencher.

Indices de risque : 5 très fort - 4 fort - 3 marqué - 2 limité - 1 faible -- En noir : les pentes les plus dangereuses

Stabilité du manteau neigeux

Situation avalancheuse typique : neige ventée

Déclenchements provoqués :

Nombreuses plaques en place et en formation dans la neige fraîche ventée, essentiellement au-dessus de 2000/2200 m, possibles en tous secteurs, mais plus fréquentes en versants nord et ouest. Ces plaques peuvent être déclenchées au passage d'un skieur, en particulier dans les versants nord où elles sont plus sensibles car reposant sur de la neige récente encore poudreuse faisant office de couche fragile. Elles peuvent être d'aspect poudreux dans les secteurs peu ventées, ou durcies par le vent en zones exposées. Elles sont de taille moyenne en général (taille 2).

Départs spontanés :

- Quelques avalanches de neige fraîche pendant les chutes à proximité de la frontière italienne, devenant moins probables l'après-midi. Départs ponctuels, ou parfois en plaque en particulier en versants nord à ouest, de taille petite à moyenne.
- Quelques avalanches de neige récente s'humidifiant au soleil sous les éclaircies sur le reste du massif. Départs ponctuels en pentes raides ensoleillées, de taille petite à rarement moyenne.

Qualité de la neige

Enneigement excédentaire dans la Roya, sinon dans les normales.
Données observées : 160 cm à la nivôse de Millefonts à 2430 m, 127 cm à Isola 2000 à 1912 m.

Enneigement skiable : vers 1300/1400 m en ubacs, 1600/1800 m en adrets peu pentus.

État de la neige en surface : dimanche matin, 20 à 35 cm de neige fraiche parfois travaillée par le vent. Elle repose sur de la neige récente poudreuse ou légèrement densifiée par le vent en ubacs au-dessus de 2000/2200 m, croutée en dessous ainsi que dans les adrets. Sur les crêtes, des corniches épaisses côtoient des zones dégarnies.

Aperçu météo pour le dimanche 15 mars

	nuit	matin	après-midi	soir

Ciel bouché avec encore un peu de neige le long de la frontière italienne, quelques éclaircies en cours de journée plus à l'ouest.

Pluie-Neige	1 200 m	1 200 m		
Iso 0 °C	1 700 m	1 900 m	2 000 m	2 200 m
Vent 2000 m	↙ 30 km/h	↙ 70 km/h	↓ 40 km/h	↓ 30 km/h
Vent 3000 m	↙ 60 km/h	↙ 65 km/h	↙ 50 km/h	↘ 15 km/h

Épaisseur de neige hors-piste

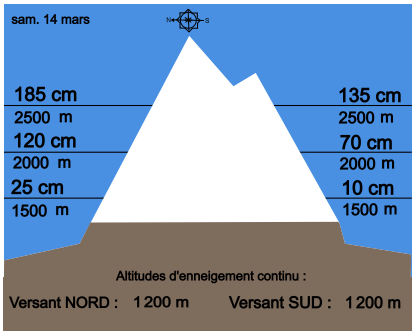

Précipitations à 1800 m

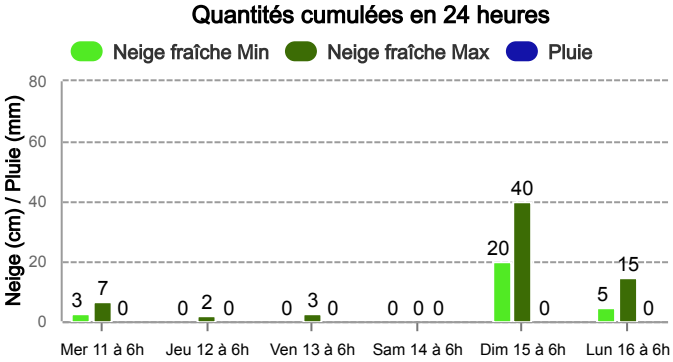

Tendance du lundi 16 mars

3

Indice de risque marqué

Risque encore marqué avec des plaques en place, mais se stabilisant rapidement en versants ensoleillés. Activité naturelle en neige s'humidifiant au soleil.

Pour consulter la vigilance en cours, veuillez vous rendre sur le site https://vigilance.meteofrance.fr/fr

Météo-France - 73 avenue de Paris, 94165 Saint-Mandé cedex - Contact : contact@meteo.fr

Rédigé par Météo-France avec la contribution des observateurs du réseau nivo-météorologiques. Partenariat : ANMSM (Maires de Stations de Montagne), DSF (Domaines Skiables de France), ADSP (Directeurs de Pistes et de la Sécurité des Stations de Sports d'Hiver) et autres acteurs de la montagne.

Bulletin neige & avalanches par téléphone au

0 892 68 10 20 Service 0,35 € / min + prix appel

RÉPUBLIQUE FRANÇAISE
Liberté Égalité Fraternité

METEO FRANCE
À VOS CÔTÉS, DANS UN CLIMAT QUI CHANGE

Bulletin d'estimation du risque d'avalanche

(valable en dehors des pistes balisées et ouvertes)

MASSIF : Mercantour

Rédigé le samedi 14 mars 2026 à 16h

Conditions nivo-météo des 7 derniers jours

	dim. 08/03				lun. 09/03				mar. 10/03				mer. 11/03				jeu. 12/03				ven. 13/03				sam. 14/03			
	03h	09h	15h	21h	03h	09h	15h	21h	03h	09h	15h	21h	03h	09h	15h	21h	03h	09h	15h	21h	03h	09h	15h	21h	03h	09h	15h	21h
Météo																												
Vent (km/h)	20	15	15	10	15	20	25	30	45	40	30	20	25	35	45	40	40	40	40	30	25	20	30	25	60	55	40	25
à 3000m																												
Vent (km/h)	20	15	15	10	15	15	15	15	20	10	15	10	10	15	20	15	20	40	35	25	30	10	15	10	15	35	25	15
à 2000m																												

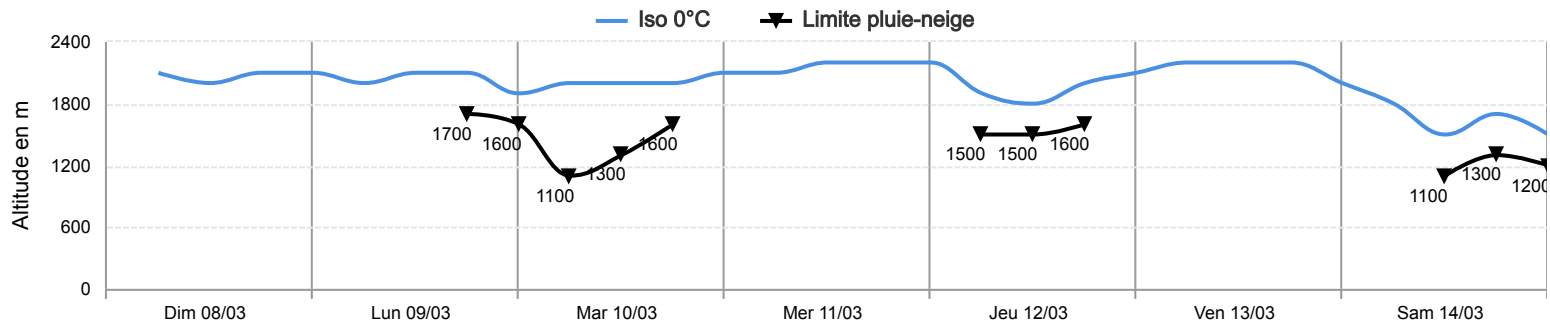

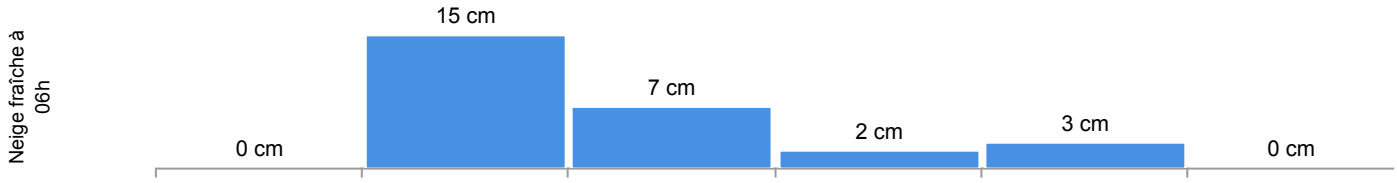

Risque d'avalanche	dim. 08/03	lun. 09/03	mar. 10/03	mer. 11/03	jeu. 12/03	ven. 13/03	sam. 14/03
	1	1	2	2	2	2	3

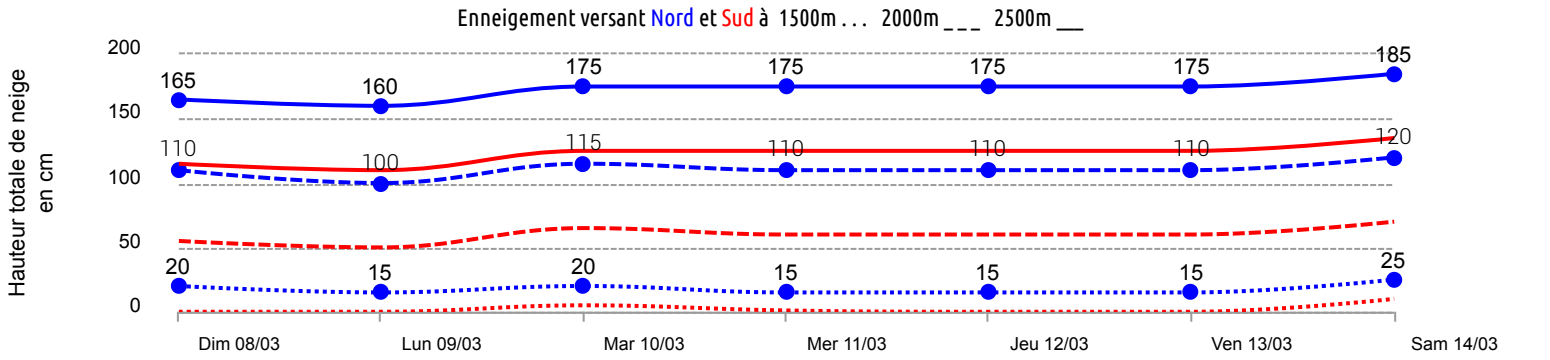

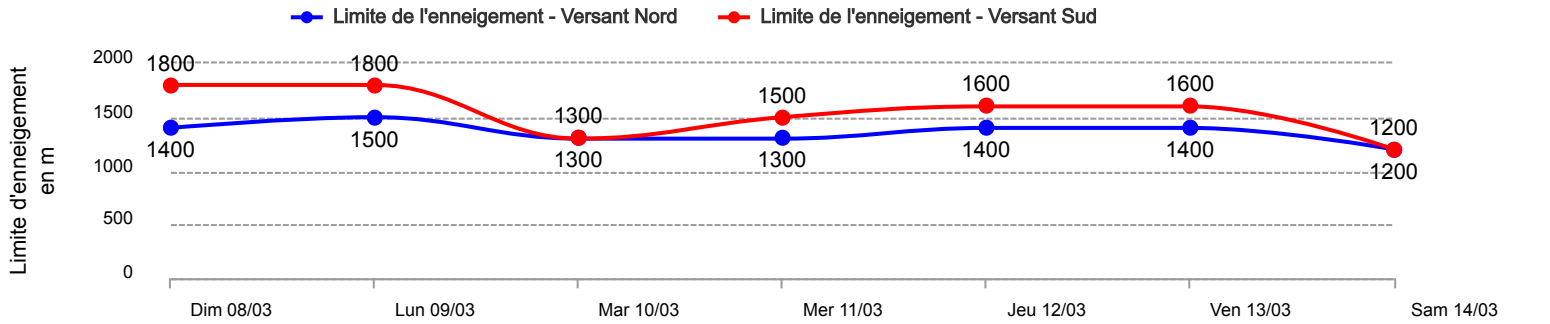

Pour consulter la vigilance en cours, veuillez vous rendre sur le site https://vigilance.meteofrance.fr/fr

Météo-France - 73 avenue de Paris, 94165 Saint-Mandé cedex - Contact : contact@meteo.fr

Rédigé par Météo-France avec la contribution des observateurs du réseau nivo-météorologiques. Partenariat : ANMSM (Maires de Stations de Montagne), DSF (Domaines Skiables de France), ADSP (Directeurs de Pistes et de la Sécurité des Stations de Sports d'Hiver) et autres acteurs de la montagne.

Bulletin neige & avalanches par téléphone au

0 892 68 10 20 Service 0,35 € / min + prix appel