Bulletin d'estimation du risque d'avalanche

(valable en dehors des pistes balisées et ouvertes)

MASSIF : Oisans

Rédigé le samedi 14 mars 2026 à 16h

Estimation des risques pour le : DIMANCHE 15 MARS

NOMBREUSES PLAQUES A VENT DANS LA NEIGE RECENTE

3

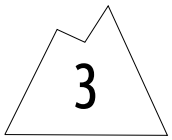

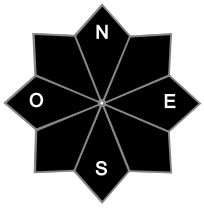

Indice de risque marqué.

Départs spontanés : Rares départs sous le vent de Nord. En journée, quelques purges possibles au soleil en moyenne montagne.

Déclenchements provoqués : Nombreuses plaques à vent réactives formées par le vent de Nord.

Indices de risque : 5 très fort - 4 fort - 3 marqué - 2 limité - 1 faible -- En noir : les pentes les plus dangereuses

Stabilité du manteau neigeux

Situation avalancheuse typique : neige ventée couche fragile persistante

Déclenchements provoqués : De nombreuses plaques se forment dans la neige récente sous l'effet du vent de Nord / Nord-Est. Elles sont d'épaisseurs limitées mais sont particulièrement réactives, et peuvent être présentes en tout versants, même loin des crêtes. Elles sont parfois bien identifiables (neige travaillée par le vent sur une neige plus meuble), mais sont parfois dure à repérer, d'aspect poudreuse, dans les secteurs où le vent est moins fort.
Observables : Transport en cours, neige travaillée par le vent, fissures devant les skis. Test du bâton éventuellement (neige plus dense en surface, plus meuble en profondeur) En versants Nord d'altitude, des couches fragiles restent profondément enfouies dans le manteau. Elles semblent maintenant franchement difficiles à solliciter, mais le risque d'un départ en cascade, provoqué par le départ d'une plaque de surface ne peut être exclu.
Départs spontanés : Quelques avalanches de petites taille, voire une de taille moyenne pourraient partir spontanément dans les pentes chargées par le vent de Nord / Nord-Est. En journée de dimanche, quelques coulées humides pourraient partir dans la neige de surface sous l'effet du soleil.

Qualité de la neige

Qualification de l'enneigement : L'enneigement est bon pour la saison en versants ombragés au dessus de 1300 m. Il est correct en Sud mais les sous-couches sont rares sous 1700 / 1800m.
Limites skiables : Vers 1200/1600m hors sapins.

Qualité de la neige dimanche : 15 à 30cm de neige récente, parfois encore en poudreuse légère en bas de pentes / combes abritées, mais plus souvent densifiée par le vent, voire cartonnée à l'approche des crêtes. En journée, la neige s'allourdie à basse altitude au gré des éclaircies.

Aperçu météo pour le dimanche 15 mars

	nuit	matin	après-midi	soir

Forte bise en début de journée. Eclaircies en matinée, avant un temps à nouveau plus nuageux l'après-midi.

Pluie-Neige	600 m			
Iso 0 °C	1 000 m	1 700 m	2 000 m	1 800 m
Vent 2500 m	↙ 55 km/h	↙ 40 km/h	← 15 km/h	← 10 km/h
Vent 3500 m	↙ 60 km/h	← 50 km/h	↖ 30 km/h	↑ 20 km/h

Épaisseur de neige hors-piste

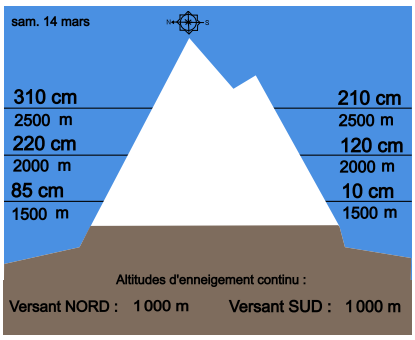

Précipitations à 1800 m

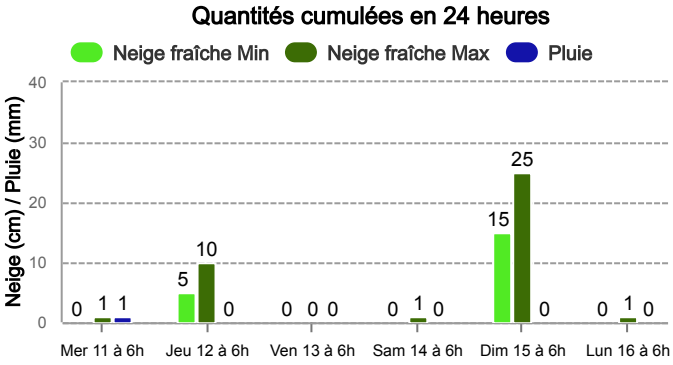

Tendance du lundi 16 mars

3

Indice de risque marqué

Lundi, la tendance générale est à la stabilisation du manteau, mais des plaques demeurent réactives en Nord. En journée, avec le retour du soleil et le redoux, de nombreuses purges sont à attendre dans la neige récente.

Pour consulter la vigilance en cours, veuillez vous rendre sur le site https://vigilance.meteofrance.fr/fr

Météo-France - 73 avenue de Paris, 94165 Saint-Mandé cedex - Contact : contact@meteo.fr

Rédigé par Météo-France avec la contribution des observateurs du réseau nivo-météorologiques. Partenariat : ANMSM (Maires de Stations de Montagne), DSF (Domaines Skiables de France), ADSP (Directeurs de Pistes et de la Sécurité des Stations de Sports d'Hiver) et autres acteurs de la montagne.

Bulletin neige & avalanches par téléphone au
0 892 68 10 20 Service 0,35 € / min + prix appel

RÉPUBLIQUE FRANÇAISE
Liberté Égalité Fraternité

METEO FRANCE
À VOS CÔTÉS, DANS UN CLIMAT QUI CHANGE

Bulletin d'estimation du risque d'avalanche
(valable en dehors des pistes balisées et ouvertes)

MASSIF : Oisans

Rédigé le samedi 14 mars 2026 à 16h

Conditions nivo-météo des 7 derniers jours

	dim. 08/03				lun. 09/03				mar. 10/03				mer. 11/03				jeu. 12/03				ven. 13/03				sam. 14/03			
	03h	09h	15h	21h	03h	09h	15h	21h	03h	09h	15h	21h	03h	09h	15h	21h	03h	09h	15h	21h	03h	09h	15h	21h	03h	09h	15h	21h
Météo																												
Vent (km/h)	25	15	15	15	20	20	40	40	35	35	20	15	20	25	30	25	35	35	25	15	15	20	40	55	60	45	25	60
à 3500m																												
Vent (km/h)	10	5	10	10	10	10	35	35	30	25	15	10	10	15	20	15	25	40	15	10	10	15	35	40	40	20	20	70
à 2500m																												

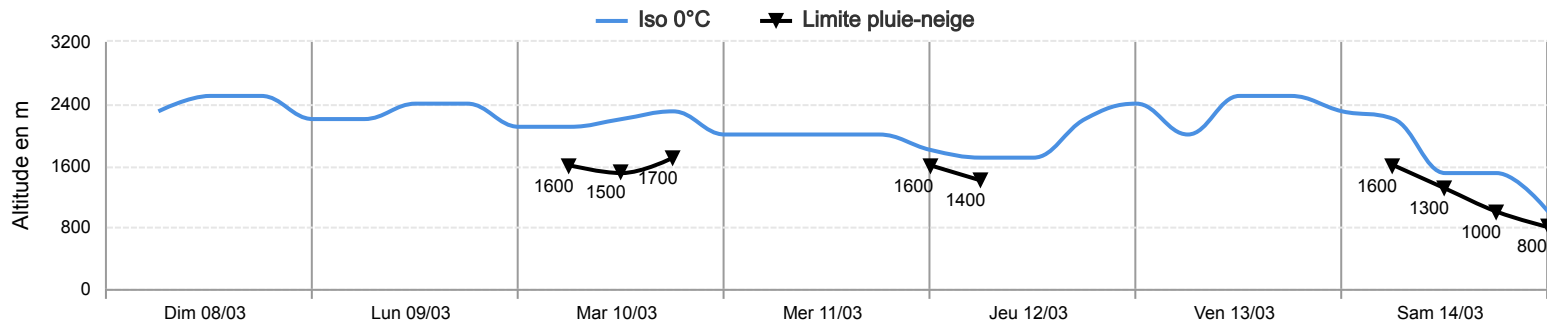

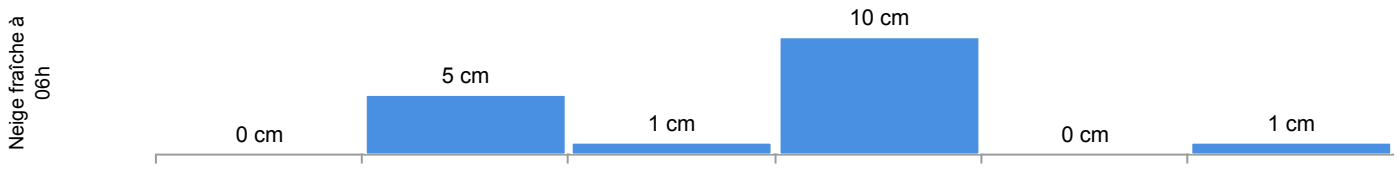

Risque d'avalanche	dim. 08/03	lun. 09/03	mar. 10/03	mer. 11/03	jeu. 12/03	ven. 13/03	sam. 14/03
	2	2	2	2	2	3	3

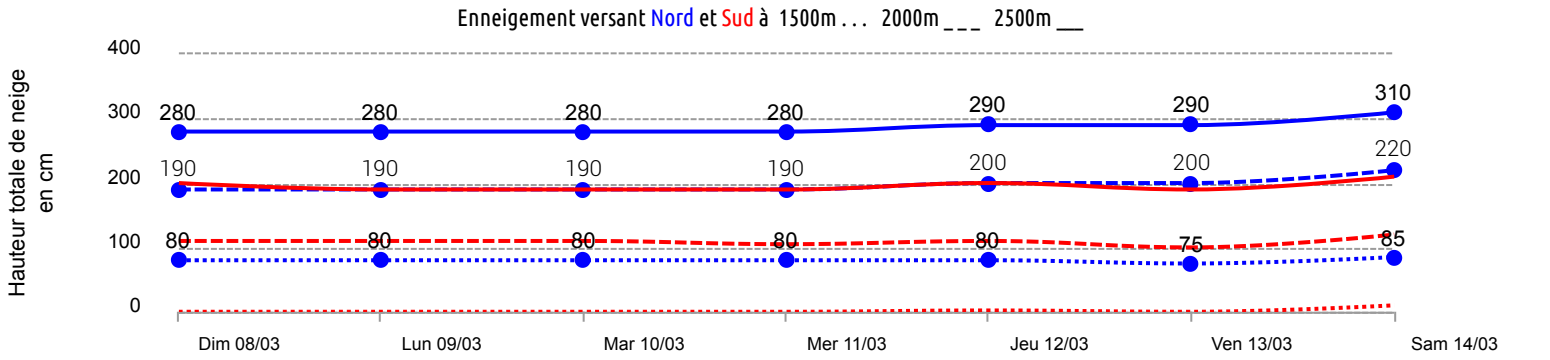

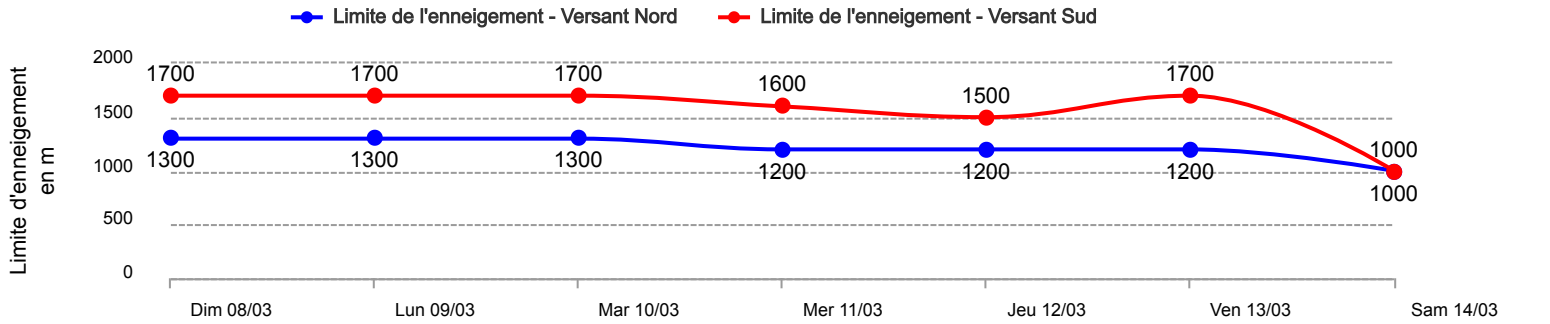

Pour consulter la vigilance en cours, veuillez vous rendre sur le site https://vigilance.meteofrance.fr/fr

Météo-France - 73 avenue de Paris, 94165 Saint-Mandé cedex - Contact : contact@meteo.fr

Rédigé par Météo-France avec la contribution des observateurs du réseau nivo-météorologiques. Partenariat : ANMSM (Maires de Stations de Montagne), DSF (Domaines Skiables de France), ADSP (Directeurs de Pistes et de la Sécurité des Stations de Sports d'Hiver) et autres acteurs de la montagne.

Bulletin neige & avalanches par téléphone au
0 892 68 10 20 Service 0,35 € / min + prix appel