Bulletin d'estimation du risque d'avalanche

(valable en dehors des pistes balisées et ouvertes)

MASSIF : Pays-Basque

Rédigé le samedi 14 mars 2026 à 16h

Estimation des risques pour le : DIMANCHE 15 MARS

CONDITIONS TRES HIVERNALES : CHUTES DE NEIGE VENTEES, FROID.

3

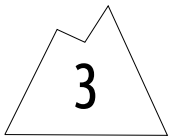

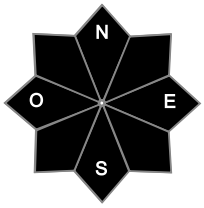

Indice de risque marqué.

Départs spontanés : En neige récente et avec les éclaircies.

Déclenchements provoqués : Plaques instables dans la neige récente et sous le vent.

Indices de risque : 5 très fort - 4 fort - 3 marqué - 2 limité - 1 faible -- En noir : les pentes les plus dangereuses

Stabilité du manteau neigeux

Situation avalancheuse typique : neige ventée neige fraîche

DECLENCHEMENTS PROVOQUES : risque **marqué** (3).
Déclenchements **faciles par un seul skieur ou randonneur d'avalanches de plaques instables en toutes orientations**, les chutes de neige se faisant avec du vent de nord-ouest à nord soutenu. Les **cassures linéaires** deviendront **plus importantes au cours de la nuit de samedi à dimanche et en journée dimanche avec le vent de nord fort**, donnant lieu à des avalanches possibles de **taille 2 à 3 (moyenne 20-50 cm de cassure) à grande (>50 cm).**
Départs de blocs dans les versants exposés au vent de nord-ouest à nord, blocs rapidement pulvérulents en glissant dans les pentes déventées.

Observables : plaques **parfois identifiables** avec les effets du vent Toutes **fissures devant les skis ou les raquettes ou Wahouffs sous les skis en fonds de vallons.** .

DEPARTS SPONTANES : risque modéré en matinée à marqué avec les éclaircies en **pentes raides en large sud**.
Départs ponctuels en général, provoquant des **avalanches de poudreuse petites à quelquefois moyennes** au cours de la journée, des avalanches **moyennes plus fréquentes** en après-midi parfois sous forme de cassures linéaires par dépôts complémentaires par le vent et surcharge des plaques en place.

Qualité de la neige

Enneigement : avec le retour de ce temps hivernal, l'enneigement redevient correct pour la saison, surtout au-dessus de 1500 m, mais reste assez maigre en versants exposés au vent d'Ouest et en versants Sud. Couche de 50cm vers 1800 m en versants sud au lever du jour
Limites skiables : A basse altitude, dès 1200m ce dimanche matin, mais sans sous-couche en dessous de 1600m en versants froids, 1900 m en versants Sud.
État de la neige : Neige froide,au lever du jour. Neige plus ou moins travaillée par le vent la nuit de samedi et au cours de la journée dimanche, frittée à cartonnée près des crêtes, cols et sommets, restant meuble à l'abri du vent (clairières et combes déventées notamment). neige molle sous les éclaircies de l'après-midi.

Aperçu météo pour le dimanche 15 mars

	nuit	matin	après-midi	soir

Temps nuageux avec quelques flocons en matinée, éclaircies en mi-journée et nuages plus denses en soirée avec de rares flocons. Vent soutenu.

Pluie-Neige	900 m	800 m	1 200 m	1 500 m
Iso 0 °C	1 200 m	1 200 m	1 400 m	1 700 m
Vent 1000 m	↓ 35 km/h	↓ 35 km/h	↓ 35 km/h	↓ 20 km/h
Vent 2000 m	↓ 65 km/h	↓ 65 km/h	↓ 60 km/h	↓ 40 km/h

Épaisseur de neige hors-piste

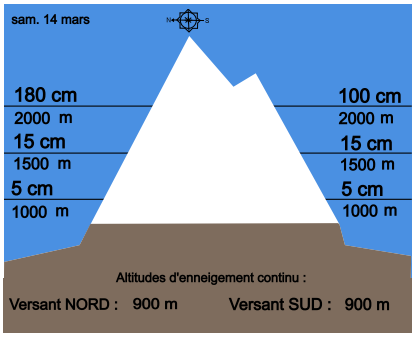

Précipitations à 1800 m

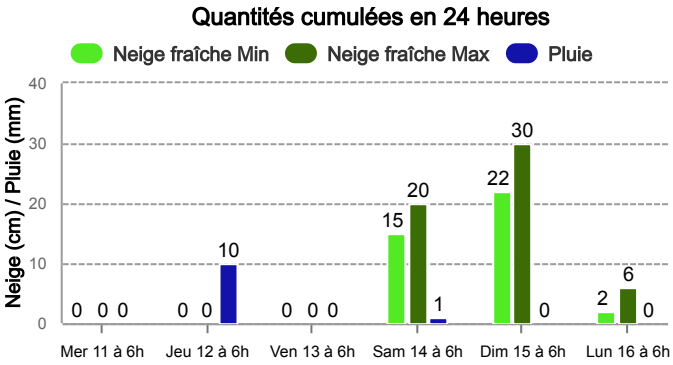

Tendance du lundi 16 mars

3

Indice de risque marqué

Maintien d'un risque accidentel marqué, le tassement et l'humidification sous le soleil se met progressivement en place cependant abondant des départs spontanés en large secteurs sud..

Pour consulter la vigilance en cours, veuillez vous rendre sur le site https://vigilance.meteofrance.fr/fr

Météo-France - 73 avenue de Paris, 94165 Saint-Mandé cedex - Contact : contact@meteo.fr

Rédigé par Météo-France avec la contribution des observateurs du réseau nivo-météorologiques. Partenariat : ANMSM (Maires de Stations de Montagne), DSF (Domaines Skiables de France), ADSP (Directeurs de Pistes et de la Sécurité des Stations de Sports d'Hiver) et autres acteurs de la montagne.

Bulletin neige & avalanches par téléphone au
0 892 68 10 20 Service 0,35 € / min + prix appel

RÉPUBLIQUE FRANÇAISE
Liberté Égalité Fraternité

METEO FRANCE
À VOS CÔTÉS, DANS UN CLIMAT QUI CHANGE

Bulletin d'estimation du risque d'avalanche
(valable en dehors des pistes balisées et ouvertes)
MASSIF : Pays-Basque

Rédigé le samedi 14 mars 2026 à 16h

Conditions nivo-météo des 7 derniers jours

	dim. 08/03				lun. 09/03				mar. 10/03				mer. 11/03				jeu. 12/03				ven. 13/03				sam. 14/03			
	03h	09h	15h	21h	03h	09h	15h	21h	03h	09h	15h	21h	03h	09h	15h	21h	03h	09h	15h	21h	03h	09h	15h	21h	03h	09h	15h	21h
Météo																												
Vent (km/h)	40	35	30	15	25	25	20	20	15	15	30	60	50	45	60	50	30	35	20	20	30	60	55	55	65	60	55	70
à 2000m																												
Vent (km/h)	10	5	5	5	10	10	5	5	10	10	15	10	15	10	20	15	10	15	5	5	15	20	20	15	25	20	20	25
à 1000m																												

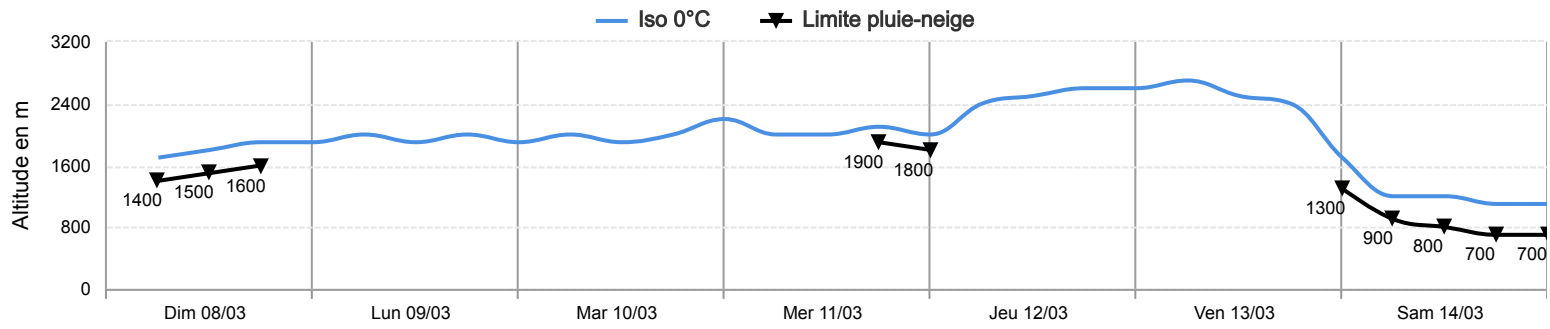

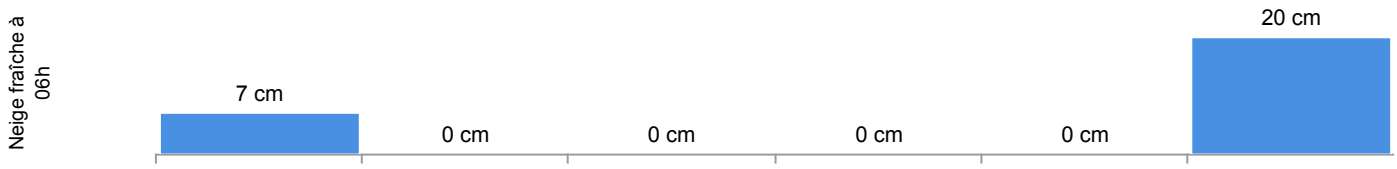

Risque d'avalanche	dim. 08/03	lun. 09/03	mar. 10/03	mer. 11/03	jeu. 12/03	ven. 13/03	sam. 14/03
	2	2	2	2	2	1	3

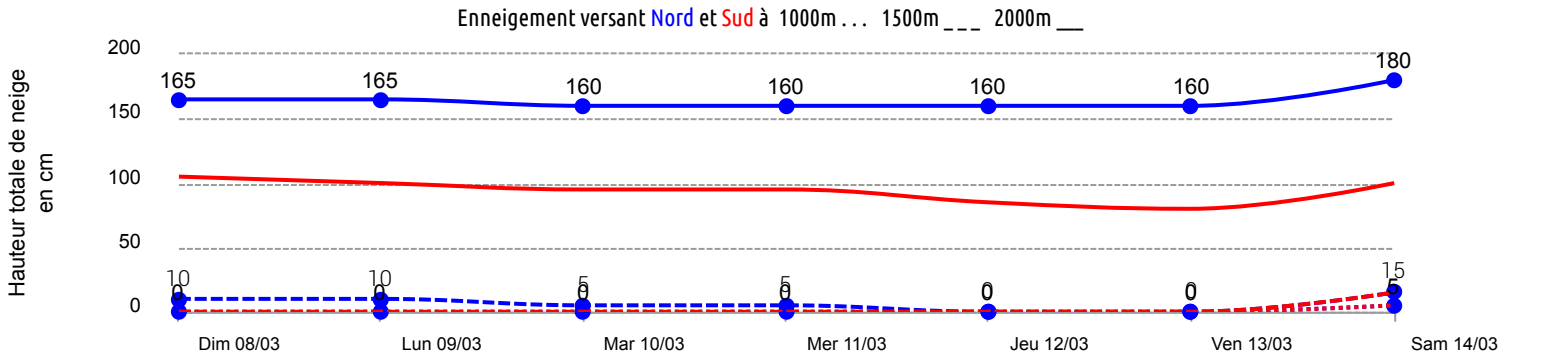

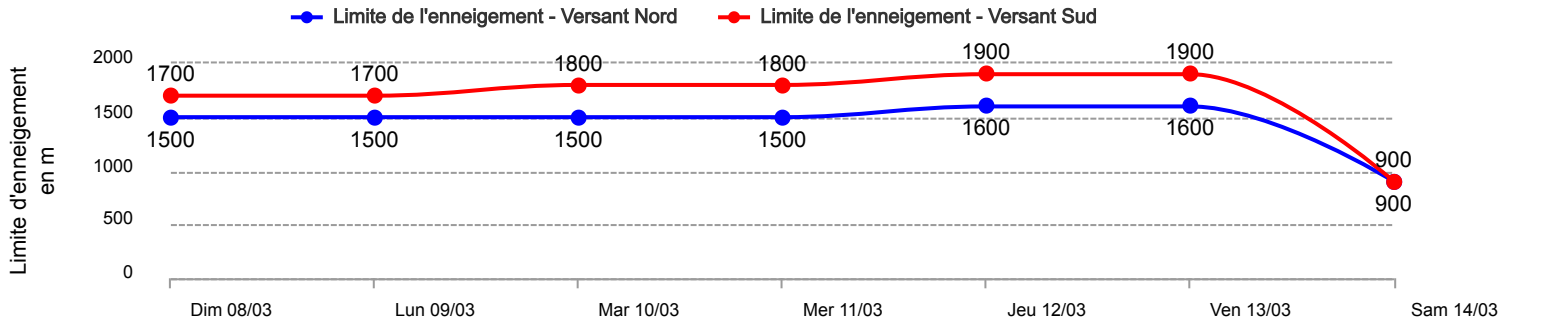

Pour consulter la vigilance en cours, veuillez vous rendre sur le site https://vigilance.meteofrance.fr/fr

Météo-France - 73 avenue de Paris, 94165 Saint-Mandé cedex - Contact : contact@meteo.fr

Bulletin neige & avalanches par téléphone au 0 892 68 10 20 Service 0,35 € / min + prix appel

Rédigé par Météo-France avec la contribution des observateurs du réseau nivo-météorologiques. Partenariat : ANMSM (Maires de Stations de Montagne), DSF (Domaines Skiables de France), ADSP (Directeurs de Pistes et de la Sécurité des Stations de Sports d'Hiver) et autres acteurs de la montagne.