# Lawinengefahr

Aktualisiert am 14.3.2026, 17:00

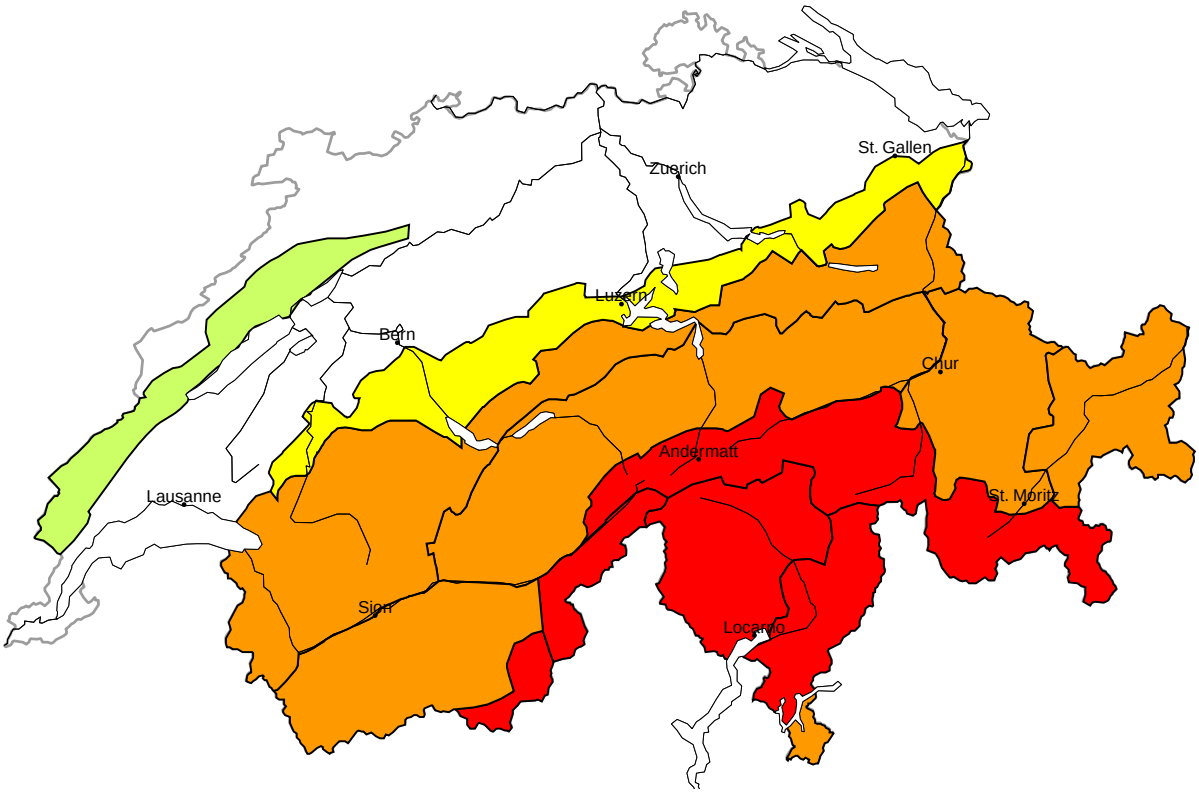


## Gebiet A — Gross (4=)

### Neuschnee, Altschnee

**Gefahrenstellen**

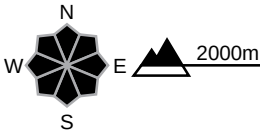


**Gefahrenbeschrieb**

Der viele Neuschnee und die Triebschneeansammlungen werden auf eine schwache Altschneedecke abgelagert. Es sind viele spontane Lawinen zu erwarten. Diese können in tiefen Schichten anreissen und vor allem an Schattenhängen sehr gross werden. Die Lawinen können in den typischen Lawinenzügen bis ins Grüne vorstossen und exponierte Verkehrswege gefährden. Die Spitze der Lawinenaktivität wird in der zweiten Nachthälfte erwartet.
Schon einzelne Wintersportler können sehr leicht Lawinen auslösen. Für Touren und Variantenabfahrten sind die Verhältnisse gefährlich.

**Gefahrenstufen** 1 gering | 2 mässig | 3 erheblich | 4 gross | 5 sehr gross

## Gebiet B

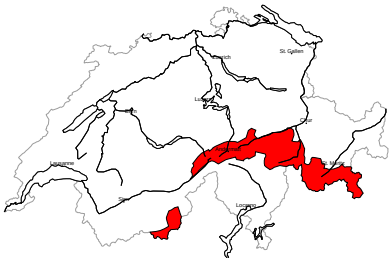

### Gross (4-)

#### Neuschnee, Altschnee

**Gefahrenstellen**

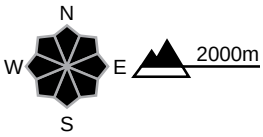


**Gefahrenbeschrieb**
Der viele Neuschnee und die Triebschneeansammlungen werden auf eine schwache Altschneedecke abgelagert. Es sind viele spontane Lawinen zu erwarten. Diese können in tiefen Schichten anreissen und vor allem an Schattenhängen vereinzelt sehr gross werden. Hoch gelegene Verkehrswege sind vereinzelt gefährdet.
Schon einzelne Wintersportler können sehr leicht Lawinen auslösen, auch grosse. Fernauslösungen sind zu erwarten. Für Touren und Variantenabfahrten sind die Verhältnisse gefährlich.

### Mässig (2)

#### Nassschnee

**Gefahrenstellen**

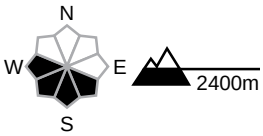


**Gefahrenbeschrieb**
Mit der Sonneneinstrahlung sind im Tagesverlauf zahlreiche feuchte Lockerschneelawinen zu erwarten, auch mittelgrosse.

## Gebiet C

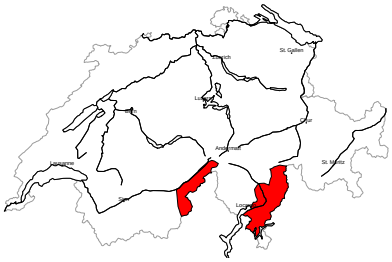

### Gross (4-)

#### Neuschnee, Altschnee

**Gefahrenstellen**

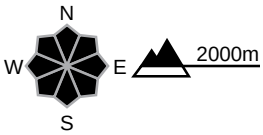


**Gefahrenbeschrieb**
Der viele Neuschnee und die Triebschneeansammlungen werden auf eine schwache Altschneedecke abgelagert. Es sind viele spontane Lawinen zu erwarten. Diese können in tiefen Schichten anreissen und vor allem an Schattenhängen vereinzelt sehr gross werden. Hoch gelegene Verkehrswege sind vereinzelt gefährdet.
Schon einzelne Wintersportler können sehr leicht Lawinen auslösen, auch grosse. Fernauslösungen sind zu erwarten. Für Touren und Variantenabfahrten sind die Verhältnisse gefährlich.

## Gebiet D

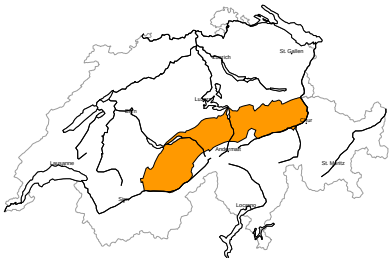

### Erheblich (3+)

#### Neuschnee

**Gefahrenstellen**

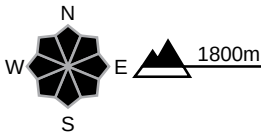


**Gefahrenbeschrieb**
Der viele Neuschnee und die Triebschneeansammlungen können sehr leicht ausgelöst werden. Lawinen können gross werden. Spontane Lawinen sind möglich, vor allem im Verlaufe der Nacht.
Für Touren und Variantenabfahrten sind die Verhältnisse kritisch.

### Mässig (2)

#### Nassschnee

**Gefahrenstellen**

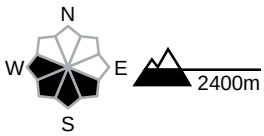


**Gefahrenbeschrieb**
Mit der Sonneneinstrahlung sind im Tagesverlauf zahlreiche feuchte Lockerschneelawinen zu erwarten, auch mittelgrosse.

## Gebiet E

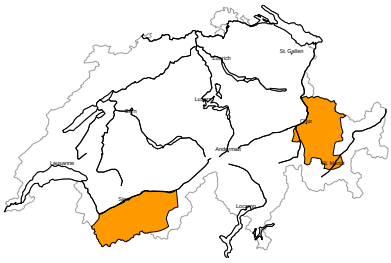

### Erheblich (3+)

#### Neuschnee, Altschnee

**Gefahrenstellen**

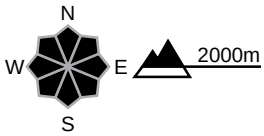


**Gefahrenbeschrieb**
Der Neuschnee wird auf eine schwache Altschneedecke abgelagert. Lawinen können in tiefen Schichten anreissen und gross werden. Spontane Lawinen sind möglich, vor allem im Verlaufe der Nacht. Lawinen können schon von einzelnen Wintersportlern ausgelöst werden. Touren erfordern Erfahrung in der Beurteilung der Lawinengefahr und Zurückhaltung.

### Mässig (2)

#### Nassschnee

**Gefahrenstellen**

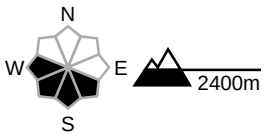


**Gefahrenbeschrieb**
Mit der Sonneneinstrahlung sind im Tagesverlauf zahlreiche feuchte Lockerschneelawinen zu erwarten, auch mittelgrosse.

## Gebiet F — Erheblich (3+)

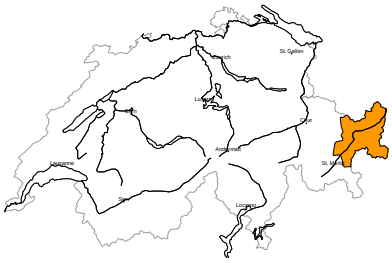

### Neuschnee, Altschnee

**Gefahrenstellen**

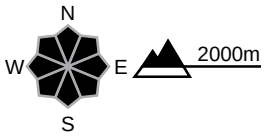


**Gefahrenbeschrieb**
Der Neuschnee wird auf eine schwache Altschneedecke abgelagert. Lawinen können in tiefen Schichten anreissen und gross werden. Spontane Lawinen sind möglich, vor allem im Verlaufe der Nacht. Lawinen können schon von einzelnen Wintersportlern ausgelöst werden. Touren erfordern Erfahrung in der Beurteilung der Lawinengefahr und Zurückhaltung.

## Gebiet G — Erheblich (3+)

### Neuschnee

**Gefahrenstellen**

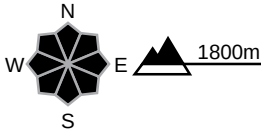


**Gefahrenbeschrieb**
Der viele Neuschnee und die Triebschneeansammlungen können sehr leicht ausgelöst werden. Lawinen können gross werden. Spontane Lawinen sind möglich, vor allem im Verlaufe der Nacht.
Für Touren und Variantenabfahrten sind die Verhältnisse kritisch.

## Gebiet H — Erheblich (3=)

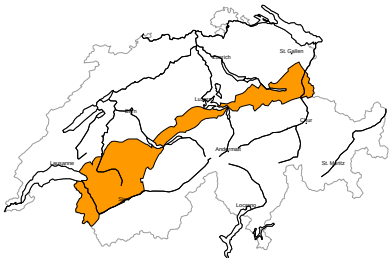

### Neuschnee

**Gefahrenstellen**

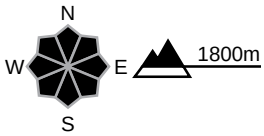


**Gefahrenbeschrieb**
Neu- und Triebschnee bilden die Hauptgefahr. Der Neuschnee liegt an windgeschützten Schattenhängen teilweise auf Oberflächenreif. Wintersportler können leicht Lawinen auslösen. Sie sind oft mittelgross. Touren und Variantenabfahrten erfordern Erfahrung in der Beurteilung der Lawinengefahr.

## Mässig (2)

### Nassschnee

**Gefahrenstellen**

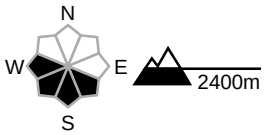


**Gefahrenbeschrieb**
Mit der Sonneneinstrahlung sind im Tagesverlauf zahlreiche feuchte Lockerschneelawinen zu erwarten, auch mittelgrosse.

## Gebiet I — Mässig (2=)

### Neuschnee

**Gefahrenstellen**

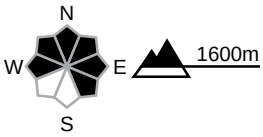


**Gefahrenbeschrieb**
Der Neuschnee ist teils störanfällig. Wintersportler können stellenweise Lawinen auslösen, auch solche mittlerer Grösse. Eine vorsichtige Routenwahl ist empfohlen.

## Gebiet J — Gering (1)

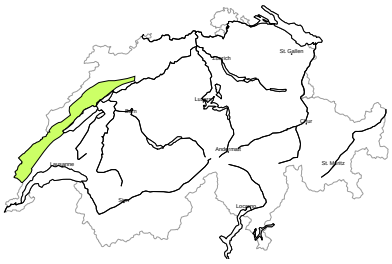

### Triebschnee

**Gefahrenstellen**

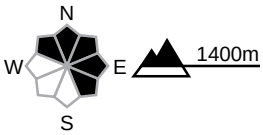


**Gefahrenbeschrieb**
Die Triebschneeansammlungen sind teils störanfällig. Lawinen sind meist klein. Die Gefahrenstellen liegen vor allem in Rinnen, Mulden und hinter Geländekanten. Nebst der Verschüttungsgefahr sollte vor allem die Mitreiss- und Absturzgefahr beachtet werden.

# Schneedecke und Wetter

Aktualisiert am 14.3.2026, 17:00

## Schneedecke

Die Altschneedecke enthält vielerorts grobkörnige Schwachschichten. Nördlich einer Linie Rhone-Rhein sind diese mächtig überdeckt und nur noch vereinzelt auslösbar. Hier geht die Gefahr vor allem vom Neu- und Triebschnee aus, welcher an Nordhängen teils auf Oberflächenreif abgelagert wird. Südlich einer Linie Rhone-Rhein werden mit den teils grossen Neuschneemengen am Wochenende wieder Brüche in den tiefen Schwachschichten erwartet. Entsprechend können Lawinen dort teils sehr gross werden.

## Wetter Rückblick auf Samstag

Es war meist stark bewölkt und verbreitet fiel Niederschlag, tagsüber im Süden intensiv. Die Schneefallgrenze sank im Norden von 1300 m in tiefe Lagen, im Süden von 1600 auf 1300 m.

**Neuschnee**
bis am Samstagnachmittag fielen oberhalb von 1800 m:
- Alpenhauptkamm vom Simplongebiet bis zum San Bernardino Pass und südlich davon: 20 bis 40 cm; im westlichen Tessin bis 50 cm
- westlicher und zentraler Alpennordhang, Unterwallis, Bergell: 10 bis 25 cm
- sonst weniger; in Nordbünden und im Unterengadin trocken

**Temperatur**
am Mittag auf 2000 m zwischen -6 °C im Nordwesten und -1 °C im Südosten

**Wind**
- oft starker Wind aus südlichen Richtungen, tagsüber im Westen und am Alpennordhang schwach bis mässig aus Nordwest
- im Jura starker bis stürmischer Wind, in der Nacht aus Südwest, tagsüber aus Nordwest

## Wetter Prognose bis Sonntag

In der Nacht fällt verbreitet Niederschlag. Dieser ist im Süden sehr intensiv, im Einfluss der Gegenstromlage greift er aber auch stark über den Alpenhauptkamm nach Norden über. Auch tagsüber fällt im Süden noch Niederschlag, aber weniger intensiv. In den übrigen Gebieten wird es teils sonnig. Im Norden fällt der Schnee bis in tiefe Lagen, im Süden oberhalb von 800 bis 1200 m.

**Neuschnee**
von Samstagnachmittag bis zum Niederschlagsende am Sonntag fallen oberhalb von 1000 m im Norden und 1500 m im Süden:
- Alpenhauptkamm vom Monte Rosa Gebiet bis zum San Bernardino Pass und südlich davon, Bergell bis Berninapass: 50 bis 70 cm; im westlichen Tessin bis zu 80 cm
- Unterwalliser Alpenhauptkamm, übriges Oberwallis, Alpennordhang vom östlichen Berner Oberland bis in die Glarner Alpen ohne Voralpen, Mittelbünden, übriges Oberengadin und Puschlav: 30 bis 50 cm
- sonst verbreitet 20 bis 30 cm; im Jura, den Waadtländer und Freiburger Alpen und im Unterengadin weniger

**Temperatur**
am Mittag auf 2000 m zwischen -6 °C im Norden und -2 °C im Süden

**Wind**
- in der Nacht mässig und im Süden teils stark aus östlichen Richtungen
- tagsüber in der Höhe mässiger und lokal starker Südwind

## Tendenz bis Dienstag

Im Norden ist es am Montagmorgen teils sonnig, dann stark bewölkt. Zwischen Montagmittag und Dienstagmorgen fallen am Alpennordhang oberhalb von 800 m 5 bis 15 cm Schnee. Am Dienstag hat es im Osten zu Beginn noch Restwolken; sonst ist es sonnig. Im Süden ist es an beiden Tagen sonnig. Der Wind weht am Montag tagsüber mässig bis stark aus West, in der Nacht auf Dienstag in der Höhe stark und im Süden teils stürmisch aus Nord. Der oft lockere Neuschnee vom Wochenende wird verfrachtet.
Die Lawinengefahr nimmt im Allgemeinen ab. Mit dem starken Wind entstehen aber störanfällige Triebschneeansammlungen, am Montag im Norden, am Dienstag im Süden. Mit der Sonneneinstrahlung sind zudem feuchte Lawinen aus dem Neuschnee zu erwarten. Am Montag im Süden sind diese zahlreich und teils gross.