Bollettino valanghe sino a domenica, 15. marzo 2026

Pericolo valanghe

aggiornato al 14.3.2026, 17:00

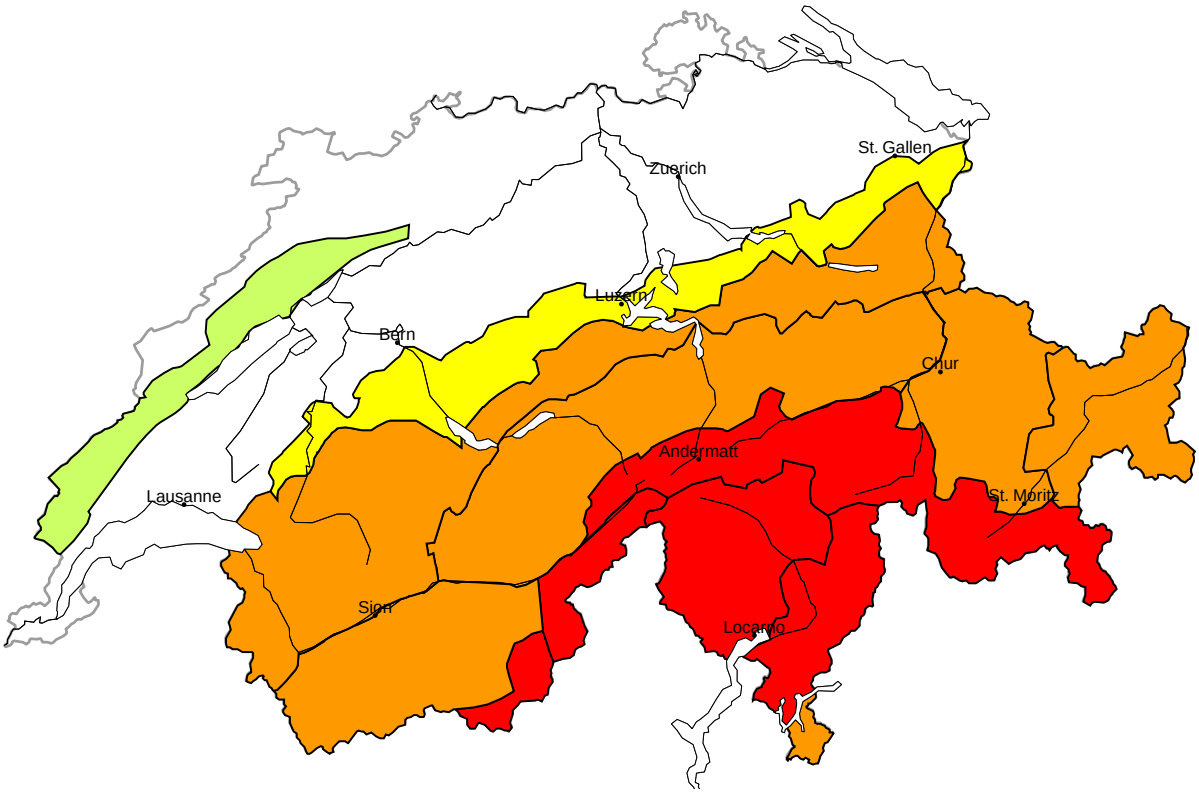

regione A — Forte (4=)

Neve fresca, Strati deboli persistenti

Punti pericolosi

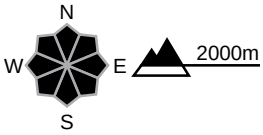

Descrizione del pericolo

L'abbondante neve fresca e gli accumuli di neve ventata verranno depositati su un debole manto di neve vecchia. Sono previste molte valanghe spontanee. Queste possono distaccarsi negli strati più profondi e, soprattutto sui pendii ombreggiati, raggiungere dimensioni molto grandi. Lungo i percorsi abituali le valanghe possono avanzare sino all'aperta campagna e minacciare le vie di comunicazione esposte. Il culmine dell'attività valanghiva verrà atteso nella seconda metà della notte.
Già un singolo appassionato di sport invernali può molto facilmente provocare il distacco di valanghe. Per le escursioni e le discese fuori pista, le condizioni sono pericolose.

Scala del pericolo 1 debole | 2 moderato | 3 marcato | 4 forte | 5 molto forte

regione B

Forte (4-)

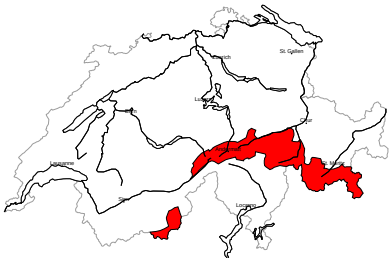

Neve fresca, Strati deboli persistenti

Punti pericolosi

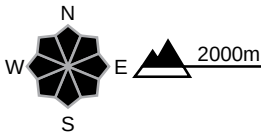

Descrizione del pericolo
L'abbondante neve fresca e gli accumuli di neve ventata verranno depositati su un debole manto di neve vecchia. Sono previste molte valanghe spontanee. Queste possono distaccarsi negli strati più profondi e, soprattutto sui pendii ombreggiati, raggiungere dimensioni molto grandi a livello isolato. Le vie di comunicazione in quota saranno a livello isolato in pericolo.
Già un singolo appassionato di sport invernali può molto facilmente provocare il distacco di valanghe, anche di grandi dimensioni. Si prevedono distacchi a distanza. Per le escursioni e le discese fuori pista, le condizioni sono pericolose.

Moderato (2)

Neve bagnata

Punti pericolosi

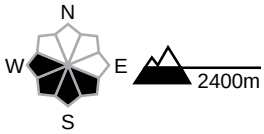

Descrizione del pericolo
Con l'irradiazione solare, nel corso della giornata sono previste numerose valanghe umide di neve a debole coesione, anche di medie dimensioni.

regione C

Forte (4-)

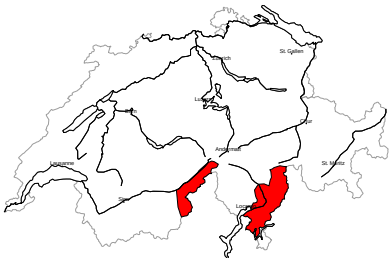

Neve fresca, Strati deboli persistenti

Punti pericolosi

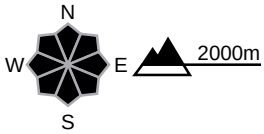

Descrizione del pericolo
L'abbondante neve fresca e gli accumuli di neve ventata verranno depositati su un debole manto di neve vecchia. Sono previste molte valanghe spontanee. Queste possono distaccarsi negli strati più profondi e, soprattutto sui pendii ombreggiati, raggiungere dimensioni molto grandi a livello isolato. Le vie di comunicazione in quota saranno a livello isolato in pericolo.
Già un singolo appassionato di sport invernali può molto facilmente provocare il distacco di valanghe, anche di grandi dimensioni. Si prevedono distacchi a distanza. Per le escursioni e le discese fuori pista, le condizioni sono pericolose.

regione D

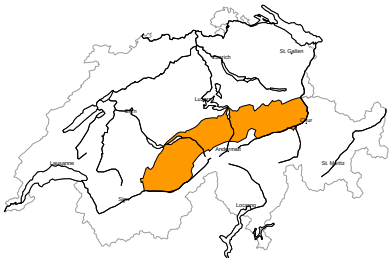

Marcato (3+)

Neve fresca

Punti pericolosi

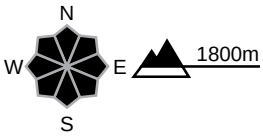

Descrizione del pericolo
L'abbondante neve fresca e gli accumuli di neve ventata possono subire molto facilmente un distacco provocato. Le valanghe possono raggiungere grandi dimensioni. Possibili valanghe spontanee, specialmente nel corso della notte.
Per le escursioni e le discese fuori pista, le condizioni sono critiche.

Moderato (2)

Neve bagnata

Punti pericolosi

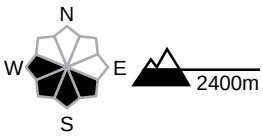

Descrizione del pericolo
Con l'irradiazione solare, nel corso della giornata sono previste numerose valanghe umide di neve a debole coesione, anche di medie dimensioni.

regione E

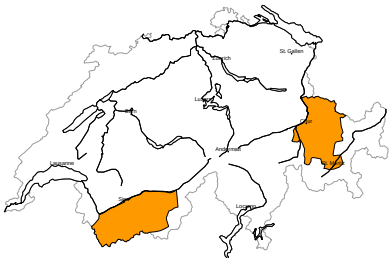

Marcato (3+)

Neve fresca, Strati deboli persistenti

Punti pericolosi

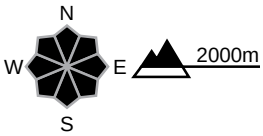

Descrizione del pericolo
La neve fresca verrà depositata su un debole manto di neve vecchia. Le valanghe possono distaccarsi negli strati più profondi e raggiungere grandi dimensioni. Possibili valanghe spontanee, specialmente nel corso della notte.
Le valanghe possono subire un distacco già in seguito al passaggio di un singolo appassionato di sport invernali. Le escursioni richiedono esperienza nella valutazione del pericolo di valanghe e cautela.

Moderato (2)

Neve bagnata

Punti pericolosi

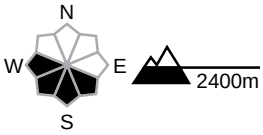

Descrizione del pericolo
Con l'irradiazione solare, nel corso della giornata sono previste numerose valanghe umide di neve a debole coesione, anche di medie dimensioni.

regione F — Marcato (3+)

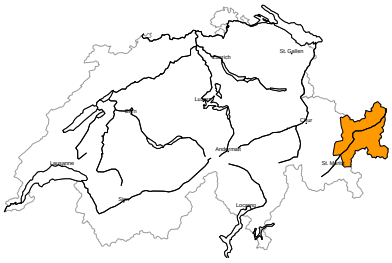

Neve fresca, Strati deboli persistenti

Punti pericolosi

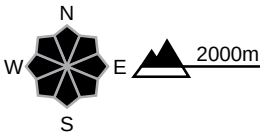

Descrizione del pericolo
La neve fresca verrà depositata su un debole manto di neve vecchia. Le valanghe possono distaccarsi negli strati più profondi e raggiungere grandi dimensioni. Possibili valanghe spontanee, specialmente nel corso della notte.
Le valanghe possono subire un distacco già in seguito al passaggio di un singolo appassionato di sport invernali. Le escursioni richiedono esperienza nella valutazione del pericolo di valanghe e cautela.

regione G — Marcato (3+)

Neve fresca

Punti pericolosi

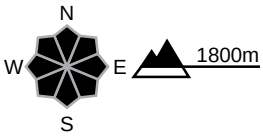

Descrizione del pericolo
L'abbondante neve fresca e gli accumuli di neve ventata possono subire molto facilmente un distacco provocato. Le valanghe possono raggiungere grandi dimensioni. Possibili valanghe spontanee, specialmente nel corso della notte.
Per le escursioni e le discese fuori pista, le condizioni sono critiche.

regione H — Marcato (3=)

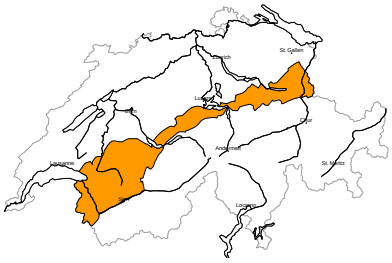

Neve fresca

Punti pericolosi

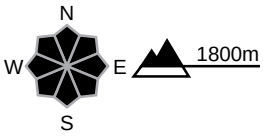

Descrizione del pericolo
La neve fresca e la neve ventata rappresentano la principale fonte di pericolo.
La neve fresca poggia in parte su brina superficiale sui pendii riparati dal vento ombreggiati. Un appassionato di sport invernali può facilmente provocare il distacco di valanghe. Esse sono sovente di dimensioni medie. Le escursioni e le discese fuori pista richiedono esperienza nella valutazione del pericolo di valanghe.

Moderato (2)

Neve bagnata

Punti pericolosi

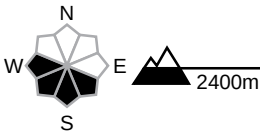

Descrizione del pericolo
Con l'irradiazione solare, nel corso della giornata sono previste numerose valanghe umide di neve a debole coesione, anche di medie dimensioni.

Bollettino valanghe sino a domenica, 15. marzo 2026

regione I — Moderato (2=)

Neve fresca

Punti pericolosi

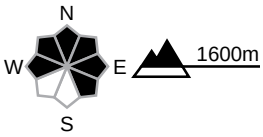

Descrizione del pericolo
La neve fresca è in parte instabile. Un appassionato di sport invernali può in alcuni punti provocare il distacco di valanghe, anche di medie dimensioni. Si raccomanda una prudente scelta dell'itinerario.

regione J — Debole (1)

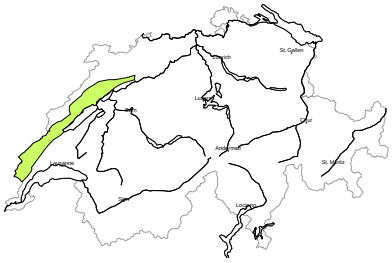

Lastroni da vento

Punti pericolosi

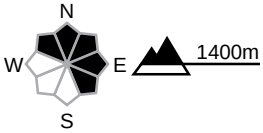

Descrizione del pericolo
Gli accumuli di neve ventata sono in parte instabili. Le valanghe sono per lo più di piccole dimensioni. I punti pericolosi si trovano soprattutto nelle conche, nei canaloni e dietro ai cambi di pendenza. Oltre al pericolo di seppellimento, occorre fare attenzione soprattutto al pericolo di trascinamento e caduta.

Manto nevoso e meteo

aggiornato al 14.3.2026, 17:00

Manto nevoso

In molti punti il manto di neve vecchia contiene strati fragili a grani grossi, che a nord di una linea Rodano-Reno sono stati abbondantemente ricoperti e che solo più a livello isolato possono subire un distacco in seguito al passaggio di persone. Qui la fonte principale di pericolo è rappresentata dalla neve fresca e ventata, che sui pendii esposti a nord si depositerà in alcuni casi su brina superficiale. A sud di una linea Rodano-Reno, con gli apporti in parte abbondanti di neve fresca previsti nel fine settimana, saranno nuovamente possibili fratture negli strati fragili basali. Di conseguenza, qui le valanghe possono raggiungere in alcuni casi dimensioni molto grandi.

Retrospettiva meteo fino a sabato

Il tempo è stato per lo più molto nuvoloso con precipitazioni in molte regioni, intense durante il giorno in quelle meridionali. Il limite delle nevicate è sceso dai 1300 m fino a bassa quota nelle regioni settentrionali e dai 1600 ai 1300 m in quelle meridionali.

Neve fresca
Fino a sabato pomeriggio, al di sopra dei 1800 m sono cadute le seguenti quantità di neve:
- Cresta principale delle Alpi dalla zona del Sempione al passo del San Bernardino e a sud di essa: dai 20 ai 40 cm, con punte fino ai 50 cm nel Ticino occidentale
- Versante nordalpino occidentale e centrale, Basso Vallese, valle Bregaglia: dai 10 ai 25 cm
- Altrove: meno. Nord dei Grigioni e Bassa Engadina: tempo asciutto

Temperatura
Sul mezzogiorno a 2000 m compresa tra -6 °C nelle regioni nord occidentali e -1 °C in quelle sud orientali

Vento
- Spesso forte proveniente dai quadranti meridionali, durante il giorno nelle regioni occidentali e sul versante nordalpino da debole a moderato proveniente da nord ovest
- Nel Giura da forte a tempestoso: durante la notte proveniente da sud ovest, durante il giorno da nord ovest

Previsioni meteo fino a domenica

Nella notte ci saranno precipitazioni in molte regioni, che saranno molto intense nelle regioni meridionali e che, sotto l'effetto della situazione caratterizzata da correnti antagoniste, si estenderanno con la stessa intensità, attraverso la cresta principale delle Alpi, anche alle regioni settentrionali. Nelle regioni meridionali le precipitazioni continueranno anche durante il giorno, ma in modo meno intenso. Nelle restanti regioni il cielo diventerà parzialmente soleggiato. Nelle regioni settentrionali la neve cadrà fino a bassa quota, in quelle meridionali dagli 800 ai 1200 m.

Neve fresca
Da sabato pomeriggio fino a domenica, quando cesseranno le precipitazioni, al di sopra dei 1000 m nelle regioni settentrionali e dei 1500 m in quelle meridionali cadranno le seguenti quantità di neve:
- Cresta principale delle Alpi dalla regione del Monte Rosa al passo del San Bernardino e a sud di essa, dalla valle Bregaglia al passo del Bernina: dai 50 ai 70 cm, con punte fino agli 80 cm nel Ticino occidentale
- Parte bassovallesana della cresta principale delle Alpi, restante Alto Vallese, versante nordalpino dall'Oberland Bernese orientale alle Alpi Glaronesi senza le Prealpi, centro dei Grigioni, restante Alta Engadina e val Poschiavo: dai 30 ai 50 cm
- In molte altre regioni: dai 20 ai 30 cm. Giura, Alpi Vodesi e Friborghesi così come Bassa Engadina: meno

Temperatura
Sul mezzogiorno a 2000 m compresa tra -6 °C nelle regioni settentrionali e -2 °C in quelle meridionali

Vento
- Durante la notte moderato, nelle regioni meridionali a tratti forte, proveniente dai quadranti orientali
- Durante il giorno in quota moderato e localmente forte proveniente da sud

Tendenza fino a martedì

Lunedì mattina il tempo nelle regioni settentrionali sarà parzialmente soleggiato, poi molto nuvoloso. Tra lunedì a mezzogiorno e martedì mattina cadranno sul versante nordalpino dai 5 ai 15 cm di neve al di sopra degli 800 m. Martedì il cielo nelle regioni orientali sarà inizialmente ancora offuscato da nuvolosità residua, altrove soleggiato. Nelle regioni meridionali il tempo sarà soleggiato in entrambi i giorni. Durante la giornata di lunedì il vento proveniente da ovest sarà da moderato a forte, nella notte fra lunedì e martedì in quota forte, nelle regioni meridionali a tratti tempestoso, proveniente da nord. La neve fresca spesso debolmente coesa del fine settimana verrà trasportata dal vento.
Anche se il pericolo di valanghe diminuirà a livello generale, il forte vento causerà la formazione di accumuli di neve ventata instabili: lunedì nelle regioni settentrionali, martedì in quelle meridionali. Con l'irradiazione solare si prevedono inoltre valanghe umide che coinvolgeranno la neve fresca e che lunedì nelle regioni meridionali saranno numerose e in alcuni casi di grandi dimensioni.