GOBIERNO DE ESPAÑA
VICEPRESIDENCIA TERCERA DEL GOBIERNO
MINISTERIO PARA LA TRANSICIÓN ECOLÓGICA Y EL RETO DEMOGRÁFICO

Boletín de información nivológica y de peligro de aludes

Pirineo Catalán

aemet Agencia Estatal de Meteorología

domingo, 15 de marzo de 2026

Pronóstico hasta las 24 horas del lunes, día 16 de marzo

(Válido fuera de pistas de esquí balizadas y abiertas)

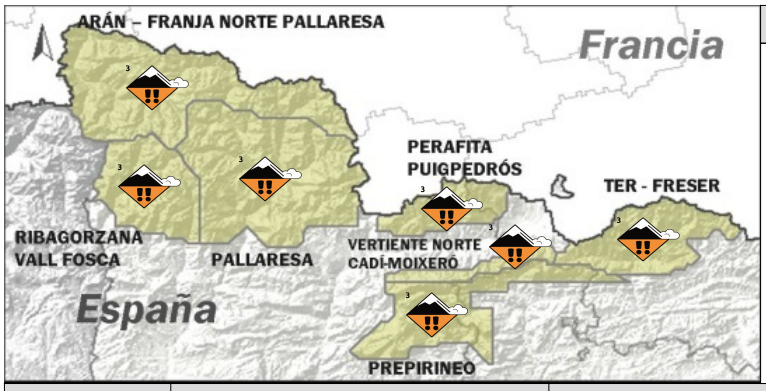

Problemas de aludes

- Nieve húmeda
- Placas de viento
- Capas débiles persistentes

Macizo	Peligro	Problemas de aludes, cota, orientación, tamaño	Innivación observada (m)
Arán - Franja norte Pallaresa	3 – Notable	**Nieve húmeda**: 2000 ↓, N O E S, 2 **Placas de viento**: 1800 ↑, N O E S, 3	2026-03-15 N / S Cotas bajas
Ribagorzana - Vall Fosca	3 – Notable	**Nieve húmeda**: 2000 ↓, N O E S, 2 **Placas de viento**: 1800 ↑, N O E S, 2	2026-03-15 N / S Cota más baja caras N
Pallaresa	3 – Notable	**Nieve húmeda**: 2000 ↓, N O E S, 2 **Placas de viento**: 1800 ↑, N O E S, 2	2026-03-15 N / S Cota más baja caras N

AEMET. Se autoriza la reproducción de su contenido citando la fuente.

Boletín de información nivológica y de peligro de aludes

Pirineo Catalán

Perafita - Puigpedrós	3 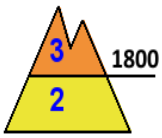 **Notable**	**Nieve húmeda**  **Placas de viento** 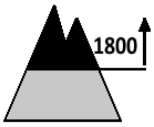 	2026-03-15 Cota más baja caras N
Ter - Freser	3 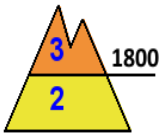 **Notable**	**Placas de viento**  **Capas débiles persistentes** 	2026-03-15 Cota más baja caras N
Vertiente norte Cadí - Moixeró	3 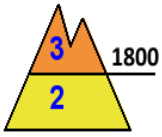 **Notable**	**Placas de viento** 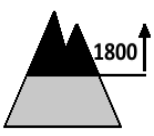  **Capas débiles persistentes** 	2026-03-15 Cota más baja caras N
Prepirineo	3 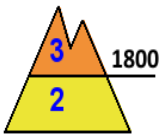 **Notable**	**Placas de viento** 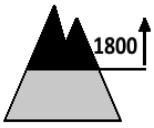  **Capas débiles persistentes** 	2026-03-15 Cota más baja caras N

Estado del manto y observaciones recientes

El sábado se produjeron precipitaciones en la zona, que han ido remitiendo durante esta mañana, y que han dejado unos 10-30 l/m2 en el norte de los macizos y alrededor de 5-10 l/m2 en el resto, aunque localmente han rondado los 40-50 l/m2. Acompañando a las nevadas han soplado vientos fuertes o muy fuertes de componente norte, que han levantado ventiscas y han redistribuido intensamente la nieve reciente, sobre todo en la alta montaña. En torno a 2100-2400 metros se han reportado depósitos de 10-30 cm de nieve nueva, superándose los 50 cm en algún enclave.

AEMET. Se autoriza la reproducción de su contenido citando la fuente.

Tras este episodio, hay nieve en cotas bajas, aunque con espesores discretos, que se van incrementando a medida que ascendemos, estando muy por encima de lo que cabría esperar a estas alturas de la temporada. A 2200-2400 metros se superan los 130-250 cm en los macizos occidentales, y los 100-180 cm en los orientales, aún más en ventisqueros, hoyas y otras zonas propensas a la acumulación.

Antes de este episodio el manto se encontraba muy humedecido, salvo en las umbrías de cotas altas, donde permanecía más frío y seco. En estas zonas existían estratos superficiales de granos facetados y escarcha, así como algunas capas débiles persistentes a mayor profundidad. Las últimas nevadas han caído con ambiente frío, lo que ha dificultado su cohesión, constituyendo un estrato débil para los posteriores depósitos. Así, en las últimas horas se han formado numerosas placas de viento en todas las orientaciones, aunque en mayor medida en las vertientes este, sur y oeste, en ocasiones alejadas de crestas y cordales. Estas estructuras han ido aumentando de tamaño con el paso de las horas y se muestran muy inestables, pudiendo colapsar ante una sobrecarga débil, o incluso de forma natural.

Evolución del manto y peligro de aludes para el lunes, día 16

Problema de nieve húmeda. Problema de placas de viento y capas débiles persistentes en cotas altas.

Mañana, lunes, predominarán los cielos poco nubosos o despejados, y las temperaturas máximas experimentarán un acusado ascenso, por lo que el manto irá humidificándose en el trascurso del día. Con estas condiciones, se podrán producir purgas de nieve húmeda, especialmente en las solanas, siendo más frecuentes a partir del mediodía. En general serán de tamaño pequeño (riesgo de caída) o mediano (capaz de enterrar a una persona), aunque en las zonas de más acumulación podría darse alguno mayor. Tampoco se descartan algunos deslizamientos basales en las áreas herbosas o de roca lisa.

No obstante, el mayor peligro lo encontraremos por encima de unos 1800 metros, donde se han formado numerosas placas de viento en todas las orientaciones, aunque en mayor medida en las vertientes este, sur y oeste. Estas estructuras pueden tener dimensiones considerables, y en algunos casos localizarse alejadas de crestas y cordales. Durante la primera mitad del lunes todavía se podrán generar algunas más. Todas estas formaciones se mantendrán inestables, y podrán colapsar ante una sobrecarga débil (paso de un solo esquiador), u ocasionalmente ceder de manera natural, provocando aludes medianos o incluso grandes (capaz de destruir un vehículo), especialmente si se activan las capas débiles persistentes, generalmente ubicadas en umbrías por encima de unos 2100 metros.

Predicción meteorológica para el lunes, día 16

Poco nuboso o despejado con intervalos de nubes altas, salvo por algunas nubes bajas a primeras horas en el Arán, que localmente podrían reducir la visibilidad. Temperaturas mínimas con pocos cambios. Máximas en notable ascenso, que localmente podría ser extraordinario. Heladas frecuentes, fuertes en cotas altas. Viento de componente norte, fuerte en cotas altas, con rachas muy fuertes a primeras horas, disminuyendo a moderado por la tarde, y flojo o moderado en el resto.

AEMET. Se autoriza la reproducción de su contenido citando la fuente.

Datos en la atmósfera libre:

Altitud de la isoterma de 0 ºC: 2700 m
Altitud de la isoterma de -10 ºC: 4300 m

Viento a 1500 m: N 20 km/h
Viento a 3000 m: N 40 km/h

Evolución para el martes día 17

Todavía se mantendrán los problemas de placas de viento y capas débiles persistentes. El problema de nieve húmeda se acentuará.

Escala europea de peligro de aludes

Débil | Limitado | Notable | Fuerte | Muy Fuerte

Problemas de aludes

Nieve reciente | Placas de viento | Capas débiles persistentes | Nieve húmeda | Deslizamientos basales | Sin problema evidente

Nota1: Se recuerda que, siempre que haya nieve, la ausencia total de peligro no existe. Hay que tener presente que en circunstancias desfavorables, con aludes de tamaño 1 (alud pequeño o colada) y tamaño 2 (alud mediano), se pueden sufrir severos daños personales.

Nota2: Los BPA se elaboran en base a información meteorológica así como al estado del manto nivoso a través de sondeos puntuales. Se advierte a los usuarios de la variabilidad de esta información al extrapolarla a zonas extensas de montaña. Por ello, AEMET no se hace responsable de su uso para la toma de decisiones que conciernen a la seguridad personal, ni de los riesgos físicos o materiales de ellas derivadas.

AEMET. Se autoriza la reproducción de su contenido citando la fuente.