GOBIERNO DE ESPAÑA
VICEPRESIDENCIA TERCERA DEL GOBIERNO
MINISTERIO PARA LA TRANSICIÓN ECOLÓGICA Y EL RETO DEMOGRÁFICO

Boletín de información nivológica y de peligro de aludes

Pirineo Navarro y Aragonés

aemet Agencia Estatal de Meteorología

domingo, 15 de marzo de 2026

Pronóstico hasta las 24 horas del lunes, día 16 de marzo

(Válido fuera de pistas de esquí balizadas y abiertas)

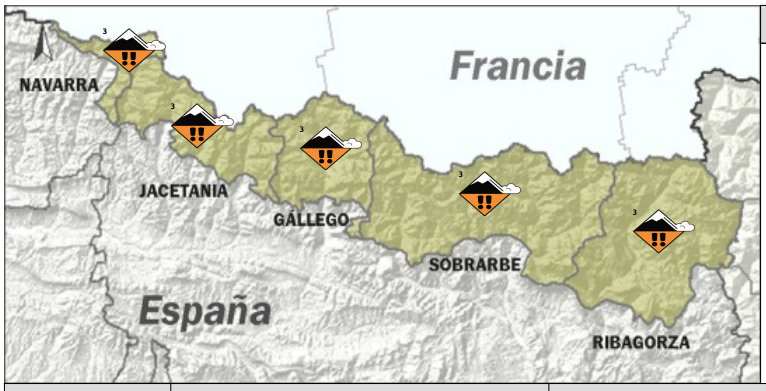

Problemas de aludes

Nieve húmeda

Placas de viento

Macizo	Peligro	Problemas de aludes, cota, orientación, tamaño	Innivación observada (m)
Navarra	3 Notable	**Nieve húmeda** 2000 N O E S 2 **Placas de viento** 1800 N O E S 3	2026-03-15 N S Cotas bajas
Jacetania	3 Notable	**Nieve húmeda** 2000 N O E S 2 **Placas de viento** 1800 N O E S 3	2026-03-15 N S Cotas bajas
Gállego	3 Notable	**Nieve húmeda** 2000 N O E S 2 **Placas de viento** 1800 N O E S 3	2026-03-15 N S Cotas bajas

Boletín de información nivológica y de peligro de aludes

Pirineo Navarro y Aragonés

Sobrarbe	3 **Notable**	**Nieve húmeda**  **Placas de viento** 	2026-03-15 Cotas bajas
Ribagorza	3 **Notable**	**Nieve húmeda**  **Placas de viento** 	2026-03-15 Cotas bajas

Estado del manto y observaciones recientes

Desde las últimas horas del viernes se han producido precipitaciones en la cordillera, que han ido remitiendo durante esta mañana. Han sido más persistentes en Navarra, Jacetania y las áreas abiertas al norte del resto de macizos, donde se han registrado 20-40 l/m2 en todo el episodio, localmente se han alcanzado los 50-60 l/m2 en el sector más occidental del Pirineo navarro. En las demás zonas han oscilado entre los 5 y los 20 l/m2, dándose los valores más discretos en el área oriental. Acompañando a las nevadas han soplado vientos fuertes o muy fuertes de componente norte, que han levantado ventiscas y han redistribuido intensamente la nieve reciente, sobre todo en la alta montaña. En cotas medias y bajas se han reportado depósitos de 20-30 cm de nieve nueva en 48 horas.

El manto comienza en cotas bajas, con espesores que rondan los 20 cm a 1300-1500 metros, y que se van incrementando a medida que ascendemos, estando por encima de lo que cabría esperar a estas alturas de la temporada en medianías y cotas altas. A unos 1800 metros se alcanzan los 90-150 cm y a 2100 metros los 140-210 cm, aún más en ventisqueros, hoyas y otras zonas propensas a la acumulación.

Antes de este episodio el manto se encontraba muy humedecido, salvo en las umbrías de cotas altas, donde permanecía más frío y seco. En estas zonas existían estratos superficiales de granos facetados y escarcha, así como algunas capas débiles persistentes a mayor profundidad. Las últimas nevadas han caído con ambiente frío, lo que ha dificultado su cohesión, constituyendo un estrato débil para los depósitos posteriores. Así, en las últimas horas se han formado numerosas placas de viento en todas las orientaciones, aunque en mayor medida en las vertientes este, sur y oeste, en ocasiones alejadas de crestas y cordales. Estas estructuras han ido aumentando de tamaño con el paso de las horas y se muestran muy inestables, pudiendo colapsar ante una sobrecarga débil, o incluso de forma natural.

En las últimas horas se han realizado algunos disparos preventivos, que han provocado un

AEMET. Se autoriza la reproducción de su contenido citando la fuente.

alud de placa friable a 2000-2250 metros en orientación sur.

Evolución del manto y peligro de aludes para el lunes, día 16

Problema de nieve húmeda. Problema de placas de viento y capas débiles persistentes en cotas altas.

Mañana, lunes, predominarán los cielos poco nubosos o despejados, y las temperaturas máximas experimentarán un acusado ascenso, por lo que el manto irá humidificándose en el trascurso del día. Con estas condiciones, se podrán producir purgas de nieve húmeda, especialmente en las solanas, siendo más frecuentes a partir del mediodía. En general serán de tamaño pequeño (riesgo de caída) o mediano (capaz de enterrar a una persona), aunque en las zonas de más acumulación podría darse alguno mayor. Tampoco se descartan algunos deslizamientos basales en las áreas herbosas o de roca lisa.

No obstante, el mayor peligro lo encontraremos por encima de unos 1800 metros, donde se han formado numerosas placas de viento en todas las orientaciones, aunque en mayor medida en las vertientes este, sur y oeste. Estas estructuras pueden tener dimensiones considerables, y en algunos casos localizarse alejadas de crestas y cordales. Durante la primera mitad del lunes todavía se podrán generar algunas más. Todas estas formaciones se mantendrán inestables, y podrán colapsar ante una sobrecarga débil (paso de un solo esquiador), u ocasionalmente ceder de manera natural, provocando aludes medianos o incluso grandes (capaz de destruir un vehículo), especialmente si se activan las capas débiles persistentes, generalmente ubicadas en umbrías por encima de unos 2100 metros.

Predicción meteorológica para el lunes, día 16

Pirineo navarro:

Intervalos de nubes bajas a primeras horas, que localmente podrían reducir la visibilidad y ocasionalmente dejar alguna precipitación débil en el norte y oeste, con la cota de nieve ascendiendo de 1000 a 1500 metros. En el transcurso de la mañana tenderán a predominar los cielos poco nubosos o despejados con nubes altas. Temperaturas en ascenso, ligero en las mínimas y notable en las máximas. Heladas débiles, moderadas en cotas altas. Viento fuerte de componente norte, con rachas muy fuertes en cotas altas y zonas expuestas a primeras horas, perdiendo intensidad por la tarde, hasta soplar flojo al final.

Pirineo aragonés:

Poco nuboso o despejado con intervalos de nubes altas, salvo por algunas nubes bajas a primeras horas en el entorno de la divisoria, que localmente podrían reducir la visibilidad. Temperaturas mínimas sin cambios o en ligero ascenso. Máximas en notable ascenso, que podría ser extraordinario. Heladas frecuentes, fuertes en cotas altas. Viento de componente norte, fuerte en cotas altas, con rachas muy fuertes a primeras horas, disminuyendo a moderado por la mañana, y flojo con intervalos moderados en el resto.

AEMET. Se autoriza la reproducción de su contenido citando la fuente.

Datos en la atmósfera libre:

Altitud de la isoterma de 0 ºC: 2800 m
Altitud de la isoterma de -10 ºC: 4400 m

Viento a 1500 m: N 40 km/h (Navarra) - N 20 km/h (Aragón)
Viento a 3000 m: N 40 km/h

Evolución para el martes día 17

Todavía se mantendrán los problemas de placas de viento y capas débiles persistentes. El problema de nieve húmeda se acentuará.

(Información elaborada a partir de los datos recibidos de los refugios de Linza, Lizara, Panticosa, Bachimaña, Góriz, Pineta, Estós, Angel Orús, La Renclusa y Belagua, de las estaciones de esquí de Astún y Formigal y de Ordesa Pradera)

Escala europea de peligro de aludes

Débil | Limitado | Notable | Fuerte | Muy Fuerte

Problemas de aludes

Nieve reciente | Placas de viento | Capas débiles persistentes | Nieve húmeda | Deslizamientos basales | Sin problema evidente

Nota1: Se recuerda que, siempre que haya nieve, la ausencia total de peligro no existe. Hay que tener presente que en circunstancias desfavorables, con aludes de tamaño 1 (alud pequeño o colada) y tamaño 2 (alud mediano), se pueden sufrir severos daños personales.

Nota2: Los BPA se elaboran en base a información meteorológica así como al estado del manto nivoso a través de sondeos puntuales. Se advierte a los usuarios de la variabilidad de esta información al extrapolarla a zonas extensas de montaña. Por ello, AEMET no se hace responsable de su uso para la toma de decisiones que conciernen a la seguridad personal, ni de los riesgos físicos o materiales de ellas derivadas.

AEMET. Se autoriza la reproducción de su contenido citando la fuente.