aineva.it

Sonntag 15.03.2026

Aktualisiert am 15.03.2026 um 07:48

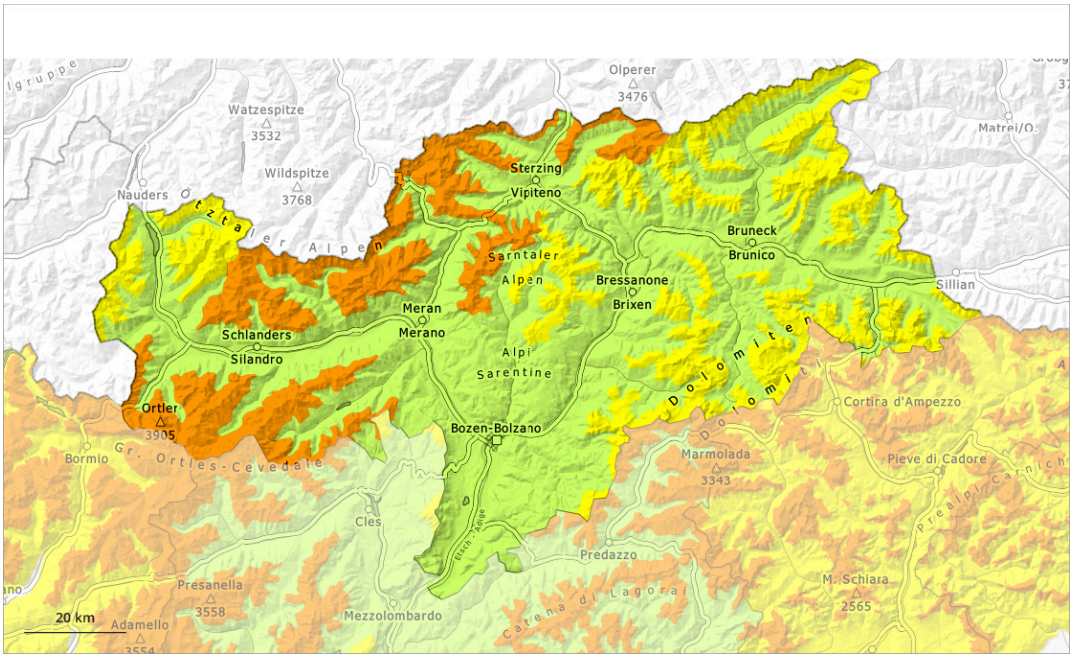

1	2	3	4	5
gering	mäßig	erheblich	groß	sehr groß

Gefahrenstufe 3 - Erheblich

Tendenz: Lawinengefahr bleibt gleich
am Montag, den 16.03.2026

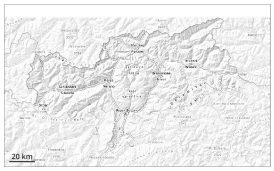

Altschnee

2000m

Triebschnee

2000m

Vorsicht vor Triebschnee und schwachem Altschnee.

Neu- und Triebschnee können schon von einzelnen Wintersportlern leicht ausgelöst werden. Lawinen können teilweise in bodennahe Schichten der Schneedecke durchreißen und vereinzelt groß werden. Die Gefahrenstellen liegen vor allem an sehr steilen West-, Nord- und Osthängen oberhalb von rund 2000 m. Vorsicht vor allem in Kammlagen und an Übergängen von wenig zu viel Schnee wie z.B. bei der Einfahrt in Rinnen und Mulden.

Zudem sind kleine und vereinzelt mittlere feuchte Lockerschneelawinen zu erwarten, vor allem an sehr steilen Sonnenhängen bei größeren Aufhellungen.

Schneedecke

Gefahrenmuster gm.1: bodennahe schwachschicht | gm.6: lockerer schnee und wind

Bis am Morgen fallen 15 bis 30 cm Schnee, lokal auch mehr. Der teilweise starke Wind verfrachtet den Neuschnee. Frische Triebschneeansammlungen entstehen in Kammlagen, Rinnen und Mulden. Sie werden an Schattenhängen auf eine ungünstige Altschneeoberfläche abgelagert.

Im unteren Teil der Schneedecke sind an West-, Nord- und Osthängen störanfällige Schwachschichten vorhanden. Dies oberhalb von rund 2000 m.

Unterhalb von rund 2000 m und steile Sonnenhänge: Die Altschneedecke ist feucht.

Tendenz

Vorsicht vor frischem Triebschnee. Schwachen Altschnee beachten.

Gefahrenstufe 3 - Erheblich

Tendenz: Lawinengefahr bleibt gleich
am Montag, den 16.03.2026

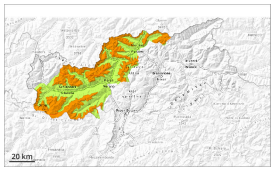

Altschnee

2000m

Triebschnee

2000m

Vorsicht vor Triebschnee und schwachem Altschnee.

Neu- und Triebschnee können schon von einzelnen Wintersportlern leicht ausgelöst werden. Lawinen können teilweise in bodennahe Schichten der Schneedecke durchreißen und vereinzelt groß werden. Die Gefahrenstellen liegen vor allem an sehr steilen West-, Nord- und Osthängen oberhalb von rund 2000 m. Vorsicht vor allem in Kammlagen und an Übergängen von wenig zu viel Schnee wie z.B. bei der Einfahrt in Rinnen und Mulden.

Zudem sind kleine und vereinzelt mittlere feuchte Lockerschneelawinen zu erwarten, vor allem an sehr steilen Sonnenhängen bei größeren Aufhellungen.

Schneedecke

Gefahrenmuster gm.1: bodennahe schwachschicht | gm.6: lockerer schnee und wind

Es fielen 20 bis 40 cm Schnee, lokal auch mehr. Der teilweise starke Wind hat den Neuschnee verfrachtet. Frische Triebschneeansammlungen entstanden vor allem in Kammlagen, Rinnen und Mulden. Sie liegen an Schattenhängen auf einer ungünstigen Altschneeoberfläche.

Im unteren Teil der Schneedecke sind an West-, Nord- und Osthängen störanfällige Schwachschichten vorhanden. Dies oberhalb von rund 2000 m.

Unterhalb von rund 2000 m und steile Sonnenhänge: Die Altschneedecke ist feucht.

Tendenz

Vorsicht vor frischem Triebschnee. Schwachen Altschnee beachten.

Gefahrenstufe 2 - Mäßig

Tendenz: Lawinengefahr bleibt gleich
am Montag, den 16.03.2026

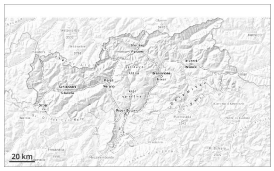

Altschnee

Triebschnee

Schwachen Altschnee beachten. Frischer Triebschnee an kammnahen Schattenhängen.

Lawinen können in bodennahen Schichten ausgelöst werden und recht groß werden. Die Gefahrenstellen liegen vor allem an sehr steilen West-, Nord- und Osthängen oberhalb von rund 2000 m. Solche Gefahrenstellen sind selten aber kaum zu erkennen. Vorsicht vor allem an Übergängen von wenig zu viel Schnee wie z.B. bei der Einfahrt in Rinnen und Mulden.

Die frischen Triebschneeansammlungen sind an sehr steilen Schattenhängen in der Höhe teils störanfällig. Sie können teilweise von einzelnen Wintersportlern ausgelöst werden. Sie können mittlere Größe erreichen. Solche Gefahrenstellen liegen besonders in Kammlagen. In den an die Gefahrenstufe 3, "erheblich" angrenzenden Gebieten ist die Lawinengefahr etwas höher.

An extrem steilen Hängen sind kleine Lockerschneelawinen möglich, vor allem bei Sonneneinstrahlung.

Schneedecke

Gefahrenmuster gm.7: schneearm neben schneereich | gm.6: lockerer schnee und wind

Es fielen 15 bis 25 cm Schnee. Der mäßige Wind hat den Neuschnee verfrachtet. Frische Triebschneeansammlungen entstanden besonders in Kamm- und Passlagen. Sie liegen an Schattenhängen auf einer ungünstigen Altschneeoberfläche.

Im unteren Teil der Schneedecke sind an West-, Nord- und Osthängen störanfällige Schwachschichten vorhanden. Dies oberhalb von rund 2000 m.

Unterhalb von rund 2000 m und steile Sonnenhänge: Die Altschneedecke ist feucht.

Tendenz

Triebschnee und schwachen Altschnee beachten.

Gefahrenstufe 2 - Mäßig

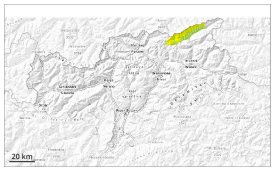

2000m

Tendenz: Lawinengefahr bleibt gleich
am Montag, den 16.03.2026

Altschnee

2000m

Schwacher Altschnee ist die Hauptgefahr.

Lawinen können in bodennahen Schichten ausgelöst werden und mittlere Größe erreichen. Die Gefahrenstellen liegen vor allem an sehr steilen West-, Nord- und Osthängen oberhalb von rund 2000 m. Solche Gefahrenstellen sind selten aber kaum zu erkennen. Vorsicht vor allem an Übergängen von wenig zu viel Schnee wie z.B. bei der Einfahrt in Rinnen und Mulden.

Die meist kleinen Triebschneeansammlungen sind an sehr steilen Schattenhängen in der Höhe vereinzelt störanfällig. Sie können teilweise von einzelnen Wintersportlern ausgelöst werden. Solche Gefahrenstellen liegen besonders in Kammlagen.

An extrem steilen Hängen sind kleine Lockerschneelawinen möglich, vor allem bei Sonneneinstrahlung.

Schneedecke

Gefahrenmuster gm.7: schneearm neben schneereich | gm.6: lockerer schnee und wind

Es fielen gebietsweise bis zu 15 cm Schnee. Der mäßige Wind hat nur wenig Schnee verfrachtet. Frische Triebschneeansammlungen entstanden in Kamm- und Passlagen. Sie liegen an Schattenhängen auf einer ungünstigen Altschneeoberfläche.

Im unteren Teil der Schneedecke sind an West-, Nord- und Osthängen störanfällige Schwachschichten vorhanden. Dies oberhalb von rund 2000 m.

Unterhalb von rund 2000 m und steile Sonnenhänge: Die Altschneedecke ist feucht.

Tendenz

Triebschnee und schwachen Altschnee beachten.

Gefahrenstufe 2 - Mäßig

Tendenz: Lawinengefahr bleibt gleich
am Montag, den 16.03.2026

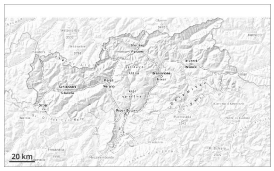

Altschnee

Triebschnee

Schwachen Altschnee beachten. Frischer Triebschnee an kammnahen Schattenhängen.

Lawinen können in bodennahen Schichten ausgelöst werden und vereinzelt groß werden. Die Gefahrenstellen liegen vor allem an sehr steilen West-, Nord- und Osthängen oberhalb von rund 2000 m. Solche Gefahrenstellen sind selten aber kaum zu erkennen. Vorsicht vor allem an Übergängen von wenig zu viel Schnee wie z.B. bei der Einfahrt in Rinnen und Mulden.

Frische Triebschneeansammlungen sind an kammnahen Schattenhängen teils störanfällig. Die Triebschneeansammlungen sind meist eher klein. In den an die Gefahrenstufe 3, "erheblich" angrenzenden Gebieten sind die Gefahrenstellen größer.

Besonders in den Hauptniederschlagsgebieten sind kleine bis mittlere Lockerschneelawinen möglich, vor allem an extrem steilen Hängen bei Sonneneinstrahlung.

Schneedecke

Gefahrenmuster gm.7: schneearm neben schneereich | gm.6: lockerer schnee und wind

Bis am Morgen fallen verbreitet 10 bis 20 cm Schnee. Der mäßige Wind verfrachtet den Neuschnee. Frische Triebschneeansammlungen entstehen besonders in Kamm- und Passlagen. Triebschneeansammlungen werden an Schattenhängen auf eine ungünstige Altschneeoberfläche abgelagert. Sie werden teilweise auf Oberflächenreif abgelagert.

Im unteren Teil der Schneedecke sind an West-, Nord- und Osthängen störanfällige Schwachschichten vorhanden. Dies oberhalb von rund 2000 m.

Unterhalb von rund 2000 m und steile Sonnenhänge: Die Altschneedecke ist feucht.

Tendenz

Vorsicht vor frischem Triebschnee. Schwachen Altschnee beachten.

Gefahrenstufe 2 - Mäßig

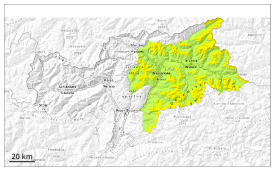

2000m

Tendenz: Lawinengefahr bleibt gleich
am Montag, den 16.03.2026

Altschnee

2000m

Schwacher Altschnee ist die Hauptgefahr.

Lawinen können in bodennahen Schichten ausgelöst werden und mittlere Größe erreichen. Die Gefahrenstellen liegen vor allem an sehr steilen West-, Nord- und Osthängen oberhalb von rund 2000 m. Solche Gefahrenstellen sind selten aber kaum zu erkennen. Vorsicht vor allem an Übergängen von wenig zu viel Schnee wie z.B. bei der Einfahrt in Rinnen und Mulden.

Die meist kleinen Triebschneeansammlungen sind an sehr steilen Schattenhängen in der Höhe vereinzelt störanfällig. Sie können teilweise von einzelnen Wintersportlern ausgelöst werden. Solche Gefahrenstellen liegen besonders in Kammlagen. Im Süden sind die Gefahrenstellen größer.

An extrem steilen Hängen sind kleine Lockerschneelawinen möglich, vor allem bei Sonneneinstrahlung.

Schneedecke

Gefahrenmuster gm.7: schneearm neben schneereich | gm.6: lockerer schnee und wind

Bis am Mittag fallen gebietsweise bis zu 15 cm Schnee. Es fallen vor allem im Süden lokal bis zu 20 cm Schnee. Der mäßige Wind verfrachtet nur wenig Schnee. Frische Triebschneeansammlungen entstehen in Kamm- und Passlagen. Sie werden an Schattenhängen auf eine ungünstige Altschneeoberfläche abgelagert.

Im unteren Teil der Schneedecke sind an West-, Nord- und Osthängen störanfällige Schwachschichten vorhanden. Dies oberhalb von rund 2000 m.

Unterhalb von rund 2000 m und steile Sonnenhänge: Die Altschneedecke ist feucht.

Tendenz

Triebschnee und schwachen Altschnee beachten.

Gefahrenstufe 2 - Mäßig

Tendenz: Lawinengefahr bleibt gleich
am Montag, den 16.03.2026

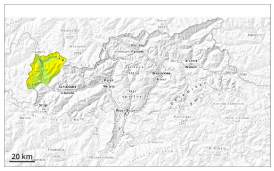

Altschnee

Triebschnee

Schwachen Altschnee beachten. Frischer Triebschnee an kammnahen Schattenhängen.

Lawinen können in bodennahen Schichten ausgelöst werden und vereinzelt groß werden. Die Gefahrenstellen liegen vor allem an sehr steilen West-, Nord- und Osthängen oberhalb von rund 2000 m. Solche Gefahrenstellen sind selten aber kaum zu erkennen. Vorsicht vor allem an Übergängen von wenig zu viel Schnee wie z.B. bei der Einfahrt in Rinnen und Mulden.

Frische Triebschneeansammlungen sind an kammnahen Schattenhängen teils störanfällig. Die Triebschneeansammlungen sind meist eher klein. In den an die Gefahrenstufe 3, "erheblich" angrenzenden Gebieten sind die Gefahrenstellen größer.

Besonders in den Hauptniederschlagsgebieten sind kleine bis mittlere Lockerschneelawinen möglich, vor allem an extrem steilen Hängen bei Sonneneinstrahlung.

Schneedecke

Gefahrenmuster gm.7: schneearm neben schneereich | gm.6: lockerer schnee und wind

Seit Sonntag fielen verbreitet 5 bis 20 cm Schnee, lokal auch mehr. Der mäßige Wind hat Schnee verfrachtet. Frische Triebschneeansammlungen liegen besonders in Kamm- und Passlagen. Triebschneeansammlungen liegen an Schattenhängen auf einer ungünstigen Altschneeoberfläche. Sie liegen teilweise auf Oberflächenreif.

Im unteren Teil der Schneedecke sind an West-, Nord- und Osthängen störanfällige Schwachschichten vorhanden. Dies oberhalb von rund 2000 m.

Unterhalb von rund 2000 m und steile Sonnenhänge: Die Altschneedecke ist feucht.

Tendenz

Vorsicht vor frischem Triebschnee. Schwachen Altschnee beachten.

Gefahrenstufe 1 - Gering

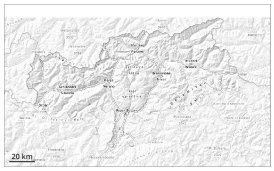

1

Tendenz: Lawinengefahr bleibt gleich
am Montag, den 16.03.2026

Geringe Lawinengefahr.

Lawinen können vor allem mit großer Belastung ausgelöst werden, sind aber meist klein. Einzelne Gefahrenstellen liegen an steilen Schattenhängen in hohen Lagen.
An extrem steilen Hängen sind kleine Lockerschneelawinen möglich, vor allem bei Sonneneinstrahlung.

Schneedecke

Gefahrenmuster gm.10: frühjahrssituation

Es fällt etwas Schnee.

Schattenhänge: In der Altschneedecke sind v.a. an Nordwest-, Nord- und Nordosthängen störanfällige Schwachschichten vorhanden.

Sonnenhänge: Die Schneedecke ist feucht.

Tendenz

Geringe Lawinengefahr.

Gefahrenstufe 1 - Gering

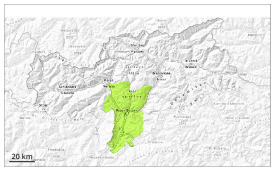

1

Tendenz: Lawinengefahr bleibt gleich
am Montag, den 16.03.2026

Geringe Lawinengefahr.

Lawinen können vor allem mit großer Belastung ausgelöst werden, sind aber meist klein. Einzelne Gefahrenstellen liegen an steilen Schattenhängen in hohen Lagen.
An extrem steilen Hängen sind kleine Lockerschneelawinen möglich, vor allem bei Sonneneinstrahlung.

Schneedecke

Gefahrenmuster gm.10: frühjahrssituation

Es fällt etwas Schnee.

Schattenhänge: In der Altschneedecke sind v.a. an Nordwest-, Nord- und Nordosthängen störanfällige Schwachschichten vorhanden.

Sonnenhänge: Die Schneedecke ist feucht.

Tendenz

Geringe Lawinengefahr.