# BUTLLETÍ DEL PERILL D'ALLAUS DEL PRINCIPAT D'ANDORRA

Préparé le 15/03/2026 16:00
Prochaine mise à jour le 16/03/2026 à 16h

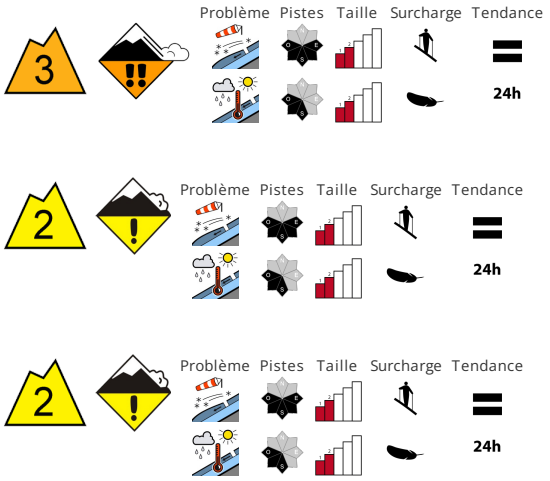


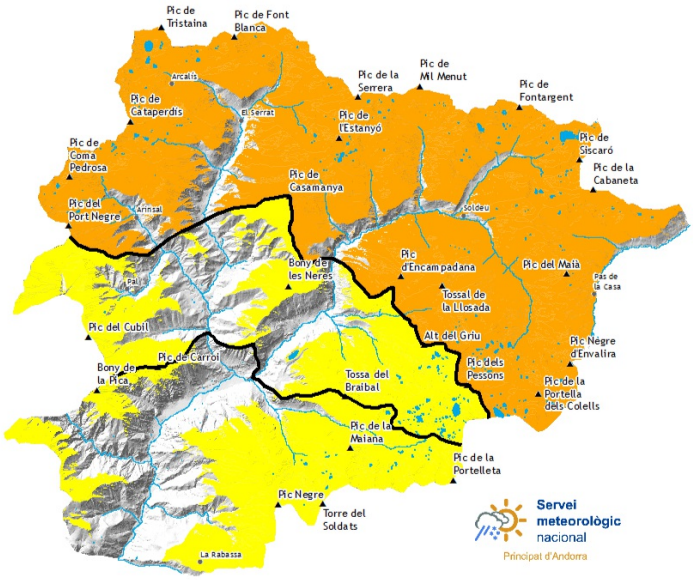


## STABILITÉ DU MANTEAU NEIGEUX

Le vent parfois tempétueux a transporté intensivement la neige fraîche et la neige ancienne.. Les accumulations de neige soufflée constituent le danger principal. Dans la partie supérieure du manteau neigeux des couches fragiles susceptibles d'être déclenchées sont présentes ils se rencontrent , surtout sur les pentes exposées à l'est , au sud et à l'ouest. Les accumulations de neige soufflée peuvent peut être déchaîné facilement et atteindre une taille moyenne.. Des avalanches petites et moyennes humides sont ils sont possibles avec le réchauffement diurne et le rayonnement solaire. Ceci sur les pentes raides ensoleillées comme au pied des parois rocheuses.

## QUALITÈ DE LA NEIGE

Le vent a soufflé tempétueusement en général. Les accumulations récentes de neige soufflée se situent à proximité des crêtes sur les pentes à proximité des crêtes exposées à l'est , au sud et à l'ouest et en général en haute montagne. À proximité des crêtes on trouve suivant l'influence du vent des hauteurs de neiges très différentes. Ce sont les pentes où la neige soufflée s'est accumulée qui sont particulièrement délicates. Les randonnées demandent un choix réfléchi des itinéraires. Des distances de délestage sont recommandées..

## EPAISSEUR DE NEIGE HORS PISTE

| Zone nord | | Epaisseur de neige | | |
|---|---|---|---|---|
| **Nival manteau** | | 1500m | 2000m | 2500m |
| N | 1600 m | 0 cm | 150 cm | 200 cm |
| S | 1900 m | 0 cm | 100 cm | 150 cm |

| Zone centre | | Epaisseur de neige | | |
|---|---|---|---|---|
| **Nival manteau** | | 1500m | 2000m | 2500m |
| N | 1600 m | 0 cm | 150 cm | 200 cm |
| S | 1900 m | 0 cm | 100 cm | 150 cm |

| Zone sud | | Epaisseur de neige | | |
|---|---|---|---|---|
| **Nival manteau** | | 1500m | 2000m | 2500m |
| N | 1600 m | 0 cm | 120 cm | 150 cm |
| S | 1900 m | 0 cm | 60 cm | 100 cm |

Govern d'Andorra

EAWS EUROPEAN AVALANCHE WARNING SERVICES

Aquest butlletí ha estat elaborat seguint les normes i recomanacions de l'**European Avalanche Warning Services**, del qual el **Servei meteorològic Nacional** n'és membre

# BUTLLETÍ DEL PERILL D'ALLAUS DEL PRINCIPAT D'ANDORRA

Servei meteorològic nacional
Principat d'Andorra

## Des informations détaillées par espace naturel protégé

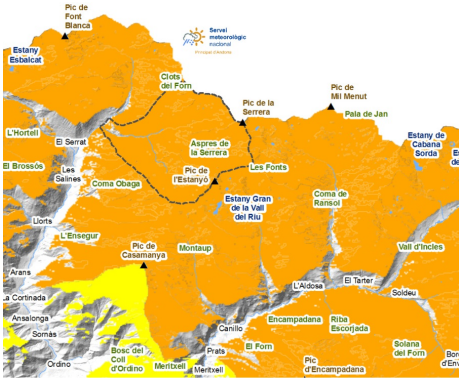


### SORTENY

L'atmosphère hivernale du week-end a enfoui la vieille neige, mais le vent l'a laissée exposée dans les changements de pente, les crêtes et les pentes exposées au nord. L'augmentation des températures diurnes rendra la texture de la neige très différente en quelques mètres, car la nouvelle neige s'humidifiera plus rapidement. Attention aux plaques de vent sur les versants est, sud et ouest, où ces premiers jours il faudra conduire plus prudemment. , , , , ,

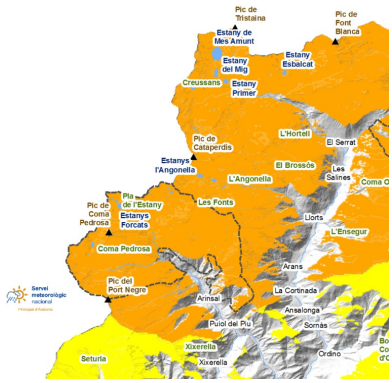


### COMAPEDROSA

La neige est revenue à tous les niveaux du Parc, mais près du village d'Arinsal il reste peu d'épaisseur qui aura tendance à fondre avec la hausse des températures lundi. À haute altitude, la vieille neige est bien gelée et a été exposée dans les zones venteuses. Nous l'identifierons par le changement de couleur avec la nouvelle neige. Il sera plus sûr et plus stable de rouler sur la vieille neige. , , , , , , ,

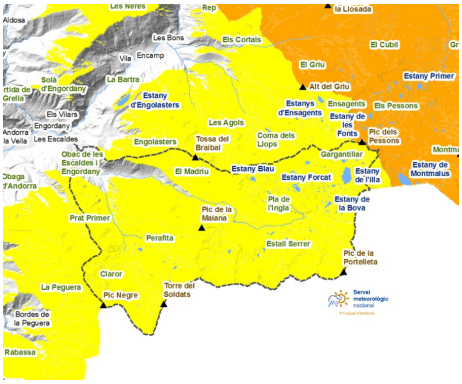


### MADRIU-PERAFITA-CLAROR

À Al Madriu, la neige a également atteint tous les niveaux. Les accès à ski depuis les Cortals d´Encamp, la Rabassa et Grau Roig sont encore bien enneigés, mais la poudrerie sur les versants est, sud et ouest doit nous inciter à conduire avec prudence. , , ,

Govern d'Andorra

EAWS
EUROPEAN AVALANCHE WARNING SERVICES

Aquest butlletí ha estat elaborat seguint les normes i recomanacions de l'**European Avalanche Warning Services**, del qual el **Servei meteorològic Nacional** n'és membre

# BUTLLETÍ DEL PERILL D'ALLAUS DEL PRINCIPAT D'ANDORRA

Servei meteorològic nacional
Principat d'Andorra

## Couche de neige fraiche des derniers jours (De 24 h mesurée à 06:00 h UTC)

| | 11/03/2026 | 12/03/2026 | 13/03/2026 | 14/03/2026 |
|---|---|---|---|---|
| **FEDA (Central)** | 0 cm | 0 cm | 0 cm | 0 cm |
| **Engolasters - FEDA** | 0 cm | 0 cm | 0 cm | 6 cm |
| **Bony de les Neres** | 0 cm | 0 cm | 3 cm | 14 cm |
| **Sorteny** | 7 cm | 0 cm | 8 cm | 25 cm |
| **Les Fonts d'Arinsal** | 5 cm | 0 cm | 9 cm | 26 cm |
| **Perafita** | 0 cm | 0 cm | 0 cm | 4 cm |
| **Tossa Espiolets** | 4 cm | 0 cm | 5 cm | 0 cm |
| **Grau Roig - FEDA** | 1 cm | 0 cm | 4 cm | 21 cm |
| **Fontverd** | 0 cm | 0 cm | 0 cm | 29 cm |
| **Ransol - FEDA** | 0 cm | 0 cm | 0 cm | 15 cm |
| **Caborreu** | 2 cm | 0 cm | 5 cm | 11 cm |
| **La Solana** | 3 cm | 0 cm | 3 cm | 29 cm |
| **Coll Pa** | 0 cm | 0 cm | 4 cm | 4 cm |
| **Envalira Antenes** | 0 cm | 0 cm | 0 cm | 37 cm |
| **Vall del Riu FEDA** | 0 cm | 0 cm | 9 cm | 14 cm |