MINISTERO DELLA DIFESA

meteomont Servizio Nazionale di previsione neve e valanghe

EAWS EUROPEAN AVALANCHE WARNING SERVICES

CARABINIERI

In collaborazione con: arpav

# DOLOMITI MERIDIONALI

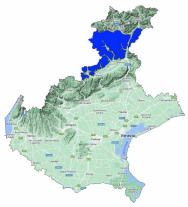

Bollettino Valanghe N. 376/2026 del 15/03/2026 ore 14.00
Validità 48 ore prossima emissione 16/03/2026

**A cura del Servizio METEOMONT dell'ARMA dei CARABINIERI**
**In collaborazione con Servizio Meteorologico dell'Aeronautica militare**

## SITUAZIONE alle 14:00 del 15/03/2026

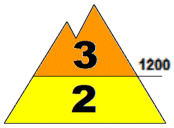


**SITUAZIONE TIPO: neve a debole coesione e vento.**




**SITUAZIONE TIPO: pioggia su neve.**

| Quota neve (mslm) | Nord | Sud |
|---|---|---|
| | 1100 - 1200 | 1100 - 1200 |

| Altezza Neve (cm) | Neve al suolo | Neve Fresca | Quota (mslm) |
|---|---|---|---|
| | 077 | 020 | 1860 |
| | 104 | 44 | 1757 |

**VALANGHE OSSERVATE: Nessuna valanga.**

## PREVISIONI 16/03/2026

# GRADO DI PERICOLO: MARCATO 3

## SITUAZIONE TIPO: neve a debole coesione e vento.

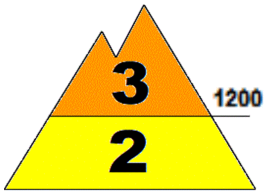





## SITUAZIONE TIPO: pioggia su neve.

**MANTO NEVOSO: La stabilità del manto nevoso è scarsa su molti punti (aree) per tutte le esposizioni al di sopra di 1200 mslm, possibili valanghe di dimensioni medie.**
**La stabilità del manto nevoso è scarsa su alcuni punti (aree) per tutte le esposizioni al di sotto di 1200 mslm, possibili valanghe di dimensioni medie.**

## AVVERTENZE

In considerazione dei recenti apporti di neve fresca, è richiesta un'ottima valutazione locale della stabilità ed individuazione dell'itinerario.

## SCALA EUROPEA DEL GRADO DI PERICOLO VALANGHE

## LEGENDA PROBLEMA

**Bollettino realizzato su scala sinottica-regionale (standard EAWS). La sua valutazione non può escludere in alcun modo la necessità di una seria e capace valutazione locale del pericolo (singolo pendio) che può essere anche sensibilmente diverso. Le previsioni meteorologiche sono relative all'orario UTC (per l'Italia +1 in inverno e +2 in estate).**

MINISTERO DELLA DIFESA

meteomont
Servizio Nazionale di previsione neve e valanghe

EAWS EUROPEAN AVALANCHE WARNING SERVICES

CARABINIERI

In collaborazione con: arpav

# DOLOMITI MERIDIONALI

## PREVISIONE METEO

| Quota | | 16/03/2026 h6:00 | 16/03/2026 h12:00 | 16/03/2026 h18:00 |
|---|---|---|---|---|
| 1000 | Venti | 01 Nodi da S-Ovest | 01 Nodi da Est | 01 Nodi da Nord |
| | Temperature | +05 °C | +05 °C | +05 °C |
| | Temp.percepita | 5 °C | 5 °C | 5 °C |
| 2000 | Venti | 01 Nodi da Nord | 01 Nodi da N-Est | 03 Nodi da N-Est |
| | Temperature | +00 °C | -01 °C | -01 °C |
| | Temp.percepita | 0 °C | -1 °C | -3 °C |
| 3000 | Venti | 02 Nodi da Est | 04 nodi da N-Ovest | 06 Nodi da Nord |
| | Temperature | -08 °C | -08 °C | -08 °C |
| | Temp.percepita | -8 °C | -12 °C | -13 °C |
| Zero termico | | 1900-2100 m. | 1800-2000 m. | 1800-2000 m. |
| Fenomeno | | — | | — |
| Stato del cielo | | | | |

## LEGENDA FENOMENI

— Assenza Fenomeni · Nebbia · Foschia · Pioggia debole · Pioggia moderata · Pioggia forte · Temporali

Nevicata debole · Nevicata moderata · Nevicata forte

## STATO DEL CIELO

Sereno · Poco nuvoloso · Nuvoloso · Molto nuvoloso · Coperto

## Parametri meteonivometrici registrati presso i campi di rilevamento il 15/03/2026.

| Località | Comune | Quota (m.s.l.m.) | Altezza neve (cm) | Neve caduta nelle 24 ore (cm) | Temp. Min (°C) | Temp. Max (°C) | Condizioni del tempo |
|---|---|---|---|---|---|---|---|
| ZINGARI BASSI * | Falcade (BL) | 1780 | 60 | 40 | N.P. | N.P. | Nevicata moderata |
| COL BALDI * | Selva di Cadore (BL) | 1920 | 122 | 47 | -1 | +2 | Nevicata moderata |
| MALGA FIORENTINA * | Borca di Cadore (BL) | 1790 | 93 | 35 | N.P. | N.P. | Nevicata debole continua |

(*) Rilievi fuori campo

**L'INFORMAZIONE E' PREVENZIONE - LEGGI L'ATTUALE GRADO DI PERICOLO VALANGHE!**

IL CAPO DEL CENTRO NAZIONALE METEOMONT
(Ten. Col. RFI Emanuela Gini)
FIRMA AUTOGRAFA OMESSA AI SENSI
DELL'ART.3 DEL D.LGS N.39/1993

Bollettino realizzato su scala sinottica-regionale (standard EAWS). La sua valutazione non può escludere in alcun modo la necessità di una seria e capace valutazione locale del pericolo (singolo pendio) che può essere anche sensibilmente diverso. Le previsioni meteorologiche sono relative all'orario UTC (per l'Italia +1 in inverno e +2 in estate).