MINISTERO DELLA DIFESA

meteomont Servizio Nazionale di previsione neve e valanghe

EAWS EUROPEAN AVALANCHE WARNING SERVICES

CARABINIERI

AERONAUTICA MILITARE SERVIZIO METEOROLOGICO

APPENNINO PAVESE

Bollettino Valanghe N. 318/2026 del 15/03/2026 ore 14.00
Validità 48 ore prossima emissione 16/03/2026

A cura del Servizio METEOMONT dell'ARMA dei CARABINIERI
In collaborazione con Servizio Meteorologico dell'Aeronautica militare

SITUAZIONE alle 14:00 del 15/03/2026

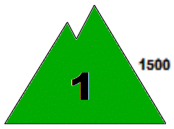

SITUAZIONE TIPO: neve a debole coesione e vento.



SITUAZIONE TIPO: pioggia su neve.

Quota neve (mslm)	Nord	Sud
	1200	1200

Altezza Neve (cm)	Neve al suolo	Neve Fresca	Quota (mslm)
	30	20	1441
	8	7	1363

VALANGHE OSSERVATE: -.

PREVISIONI 16/03/2026

GRADO DI PERICOLO: DEBOLE 1

SITUAZIONE TIPO: neve a debole coesione e vento.



SITUAZIONE TIPO: situazione primaverile.

MANTO NEVOSO: La stabilità del manto nevoso è scarsa su pochi punti (aree) per tutte le esposizioni al di sopra di 1500 mslm, possibili valanghe di dimensioni piccole.
La stabilità del manto nevoso è scarsa su pochi punti (aree) per isolati pendii al di sotto di 1500 mslm, possibili valanghe di dimensioni piccole.

AVVERTENZE

In considerazione degli importanti accumuli di neve ventata, sono da evitare conche, canaloni, cambi di pendenza e pendii sotto vento in genere.

SCALA EUROPEA DEL GRADO DI PERICOLO VALANGHE

LEGENDA PROBLEMA

Bollettino realizzato su scala sinottica-regionale (standard EAWS). La sua valutazione non può escludere in alcun modo la necessità di una seria e capace valutazione locale del pericolo (singolo pendio) che può essere anche sensibilmente diverso. Le previsioni meteorologiche sono relative all'orario UTC (per l'Italia +1 in inverno e +2 in estate).

MINISTERO DELLA DIFESA

meteomont
Servizio Nazionale di previsione neve e valanghe

EAWS EUROPEAN AVALANCHE WARNING SERVICES

CARABINIERI

APPENNINO PAVESE

PREVISIONE METEO

Quota		16/03/2026 h6:00	16/03/2026 h12:00	16/03/2026 h18:00
1000	Venti	04 Nodi da N-Est	03 Nodi da Nord	02 Nodi da Nord
	Temperature	+04 °C	+08 °C	+06 °C
	Temp.percepita	2 °C	7 °C	6 °C
2000	Venti	11 Nodi da N-Est	06 Nodi da Nord	13 Nodi da Nord
	Temperature	+00 °C	+01 °C	+04 °C
	Temp.percepita	-5 °C	-2 °C	-1 °C
3000	Venti	08 Nodi da Nord	04 Nodi da Nord	15 Nodi da Nord
	Temperature	-06 °C	-05 °C	-03 °C
	Temp.percepita	-12 °C	-8 °C	-10 °C
Zero termico		1900-2100 m.	2300-2500 m.	2400-2600 m.
Fenomeno		—	—	—
Stato del cielo				

LEGENDA FENOMENI

— Assenza Fenomeni · Nebbia · Foschia · Pioggia debole · Pioggia moderata · Pioggia forte · Temporali

Nevicata debole · Nevicata moderata · Nevicata forte

STATO DEL CIELO

Sereno · Poco nuvoloso · Nuvoloso · Molto nuvoloso · Coperto

Parametri meteonivometrici registrati presso i campi di rilevamento il 15/03/2026.

Località	Comune	Quota (m.s.l.m.)	Altezza neve (cm)	Neve caduta nelle 24 ore (cm)	Temp. Min (°C)	Temp. Max (°C)	Condizioni del tempo
PIAN DEL POGGIO	Santa Margherita di Staffora (PV)	1441	30	20	+0	+5	Assenza di precipitazioni

(*) Rilievi fuori campo

L'INFORMAZIONE E' PREVENZIONE - LEGGI L'ATTUALE GRADO DI PERICOLO VALANGHE!

IL CAPO DEL CENTRO NAZIONALE METEOMONT
(Ten. Col. RFI Emanuela Gini)
FIRMA AUTOGRAFA OMESSA AI SENSI
DELL'ART.3 DEL D.LGS N.39/1993