MINISTERO DELLA DIFESA

meteomont Servizio Nazionale di previsione neve e valanghe

EAWS EUROPEAN AVALANCHE WARNING SERVICES

CARABINIERI

In collaborazione con: MARCHE

## APPENNINO UMBRO-MARCHIG. MERID. - MONTI SIBILLINI

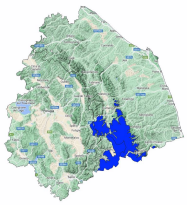

Bollettino Valanghe N. 328/2026 del 15/03/2026 ore 14.00
Validità 48 ore prossima emissione 16/03/2026

**A cura del Servizio METEOMONT dell'ARMA dei CARABINIERI**
**In collaborazione con Servizio Meteorologico dell'Aeronautica militare**

## SITUAZIONE alle 14:00 del 15/03/2026

**SITUAZIONE TIPO: situazione primaverile.**




**SITUAZIONE TIPO: situazione primaverile.**

| Quota neve (mslm) | Nord | Sud |
|---|---|---|
| | 1600 - 1800 | 1800 - 1900 |

| Altezza Neve (cm) | Neve al suolo | Neve Fresca | Quota (mslm) |
|---|---|---|---|
| | 80-100 | 005 | 2000 |
| | 010 - 030 | 000 | 1700 |

**VALANGHE OSSERVATE: Valanghe di piccole dimensioni, Valanghe a lastroni di fondo.**

## PREVISIONI 16/03/2026

## GRADO DI PERICOLO: MODERATO 2

## SITUAZIONE TIPO: situazione primaverile.




## SITUAZIONE TIPO: situazione primaverile.

**MANTO NEVOSO: La stabilità del manto nevoso è discreta su alcuni punti (aree) per tutte le esposizioni al di sopra di 1900 mslm, possibili valanghe di dimensioni medie.**
**La stabilità del manto nevoso è discreta su pochissimi punti (aree) per isolati pendii al di sotto di 1900 mslm, possibili valanghe di dimensioni piccole.**

## AVVERTENZE

Viste le condizioni del manto nevoso, le attività al di fuori delle piste battute e segnalate richiedono buone capacità di valutazione del pericolo locale.

## SCALA EUROPEA DEL GRADO DI PERICOLO VALANGHE

## LEGENDA PROBLEMA

**Bollettino realizzato su scala sinottica-regionale (standard EAWS). La sua valutazione non può escludere in alcun modo la necessità di una seria e capace valutazione locale del pericolo (singolo pendio) che può essere anche sensibilmente diverso. Le previsioni meteorologiche sono relative all'orario UTC (per l'Italia +1 in inverno e +2 in estate).**

MINISTERO DELLA DIFESA

meteomont
Servizio Nazionale di previsione neve e valanghe

EAWS EUROPEAN AVALANCHE WARNING SERVICES

CARABINIERI

In collaborazione con: MARCHE

# APPENNINO UMBRO-MARCHIG. MERID. - MONTI SIBILLINI

## PREVISIONE METEO

| Quota | | 16/03/2026 h6:00 | 16/03/2026 h12:00 | 16/03/2026 h18:00 |
|---|---|---|---|---|
| 1000 | Venti | 07 Nodi da Est | 06 Nodi da Est | 03 Nodi da Est |
| | Temperature | +03 °C | +03 °C | +02 °C |
| | Temp.percepita | -0 °C | 0 °C | 0 °C |
| 2000 | Venti | 14 Nodi da Est | 12 Nodi da Est | 10 Nodi da Est |
| | Temperature | +00 °C | -01 °C | +00 °C |
| | Temp.percepita | -6 °C | -7 °C | -5 °C |
| 3000 | Venti | 15 Nodi da Est | 11 Nodi da Est | 12 Nodi da Est |
| | Temperature | -07 °C | -06 °C | -05 °C |
| | Temp.percepita | -15 °C | -13 °C | -12 °C |
| Zero termico | | 1900-2100 m. | 1800-2000 m. | 1800-2000 m. |
| Fenomeno | | | — | — |
| Stato del cielo | | | | |

## LEGENDA FENOMENI

— Assenza Fenomeni · Nebbia · Foschia · Pioggia debole · Pioggia moderata · Pioggia forte · Temporali

Nevicata debole · Nevicata moderata · Nevicata forte

## STATO DEL CIELO

Sereno · Poco nuvoloso · Nuvoloso · Molto nuvoloso · Coperto

## Parametri meteonivometrici registrati presso i campi di rilevamento il 15/03/2026.

| Località | Comune | Quota (m.s.l.m.) | Altezza neve (cm) | Neve caduta nelle 24 ore (cm) | Temp. Min (°C) | Temp. Max (°C) | Condizioni del tempo |
|---|---|---|---|---|---|---|---|
| FORCA DI GUALDO | Castelsantangelo sul Nera (MC) | 1496 | 0 | 0 | -1 | +7 | Assenza di precipitazioni |
| COLLE | Montegallo (AP) | 1036 | 0 | 0 | -1 | +11 | Assenza di precipitazioni |
| PARCO GUARNIERI | Montemonaco (AP) | 980 | 0 | 0 | +4 | +13 | Assenza di precipitazioni |
| BELVEDERE DI FRONTIGNANO * | Ussita (MC) | 1709 | 5 | 0 | N.P. | N.P. | Assenza di precipitazioni |

(*) Rilievi fuori campo

**L'INFORMAZIONE E' PREVENZIONE - LEGGI L'ATTUALE GRADO DI PERICOLO VALANGHE!**

**IL CAPO DEL CENTRO NAZIONALE METEOMONT**
**(Ten. Col. RFI Emanuela Gini)**
**FIRMA AUTOGRAFA OMESSA AI SENSI**
**DELL'ART.3 DEL D.LGS N.39/1993**

Bollettino realizzato su scala sinottica-regionale (standard EAWS). La sua valutazione non può escludere in alcun modo la necessità di una seria e capace valutazione locale del pericolo (singolo pendio) che può essere anche sensibilmente diverso. Le previsioni meteorologiche sono relative all'orario UTC (per l'Italia +1 in inverno e +2 in estate).