Bulletin d'estimation du risque d'avalanche

(valable en dehors des pistes balisées et ouvertes)

MASSIF : Renoso Incudine

Rédigé le dimanche 15 mars 2026 à 15h

Estimation des risques pour le : LUNDI 16 MARS

INSTABILITÉS EN ALTITUDE DANS LA NEIGE FRAICHE VENTÉE.

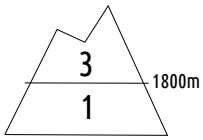

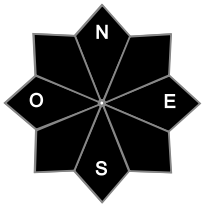

Au-dessus de 1800m indice de risque marqué, plus bas indice faible.

Départs spontanés : Départs en neige humide au soleil

Déclenchements provoqués : Nombreuses plaques à vent en altitude, risque de départs ponctuels sous les skis en neige humide

Indices de risque : 5 très fort - 4 fort - 3 marqué - 2 limité - 1 faible -- En noir : les pentes les plus dangereuses

Stabilité du manteau neigeux

Situation avalancheuse typique : neige ventée neige humide

Déclenchements provoqués : Le vent qui a soufflé de Sud puis d'Est, pendant les récentes chutes de neige, a formé de nouvelles plaques dans les pentes orientées Nord à Ouest. Ces plaques reposent sur une couche fragile principalement composée de neige roulée. Des déclenchements sont possibles par faible surcharge, au simple passage d'un randonneur ou skieur, pouvant engendrer des avalanches de neige fraîche (taille 1 à 2). En dessous de 1800 m, départs ponctuels sous les skis ou raquettes en neige humide, notamment dans les pentes raides et ensoleillées.

Départs spontanés : Au-dessus de 1800 m, rares départs en neige fraîche (taille 1 à 2). En dessous, quelques coulées ou avalanches de neige humide sont possibles dans les pentes raides bien ensoleillées.

Autres : Nombreuses surfaces glacées près des crêtes ventées.

Qualité de la neige

Qualification de l'enneigement : L'enneigement est excellent pour la saison au-dessus de 1600 m. Au Val d'Ese, on relève encore près d'un mètre de neige juste au-dessus de la station. À Ghisoni Capanelle, 1m70 au-dessus de 1800 m et près de 3 mètres dans les combes abritées.

Limite d'enneigement skiable : 1500 à 1600 m selon le versant.

État de la neige : Le manteau neigeux est recouvert d'une nouvelle couche de neige fraîche 10 à 20 cm localement plus dans les combes et endroits à l'abri du vent. En dessous de 1800 m, la neige est souvent lourde et humide. En altitude, la neige est sèche, souvent composée de neige roulée. Des **surfaces dures et glacées** sont présentes près des crêtes et dans les couloirs raides ne voyant pas le soleil.

À noter également la présence de **corniches parfois volumineuses**.

Aperçu météo pour le lundi 16 mars

nuit	matin	après-midi	soir

Temps ensoleillé, plus doux.

Pluie-Neige				
Iso 0 °C	2 200 m	2 300 m	2 500 m	2 600 m
Vent 1500 m	50 km/h	40 km/h	30 km/h	25 km/h
Vent 2000 m	60 km/h	45 km/h	35 km/h	45 km/h

Épaisseur de neige hors-piste

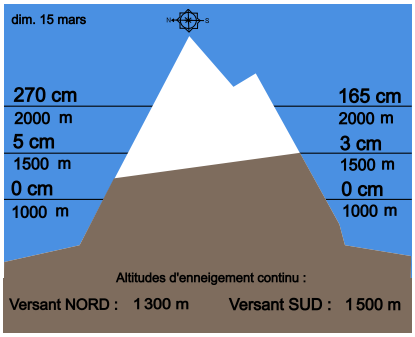

Précipitations à 1800 m

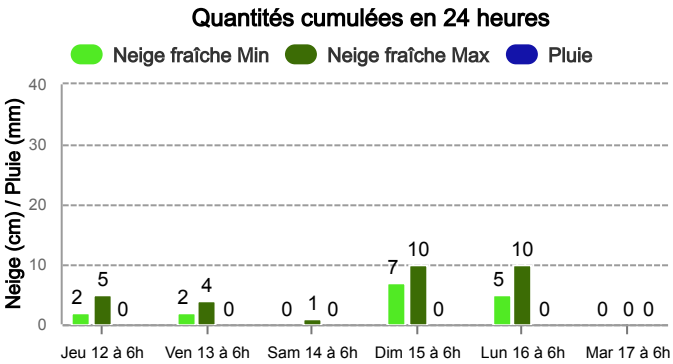

Tendance du mardi 17 mars

Indice de risque limité

Soleil et douceur favorisent la stabilisation des plaques. Baisse du risque d'avalanche.

Pour consulter la vigilance en cours, veuillez vous rendre sur le site https://vigilance.meteofrance.fr/fr

Météo-France - 73 avenue de Paris, 94165 Saint-Mandé cedex - Contact : contact@meteo.fr

Rédigé par Météo-France avec la contribution des observateurs du réseau nivo-météorologiques. Partenariat : ANMSM (Maires de Stations de Montagne), DSF (Domaines Skiables de France), ADSP (Directeurs de Pistes et de la Sécurité des Stations de Sports d'Hiver) et autres acteurs de la montagne.

Bulletin neige & avalanches par téléphone au

0 892 68 10 20 Service 0,35 € / min + prix appel

RÉPUBLIQUE FRANÇAISE
Liberté Égalité Fraternité

METEO FRANCE
À VOS CÔTÉS, DANS UN CLIMAT QUI CHANGE

Bulletin d'estimation du risque d'avalanche

(valable en dehors des pistes balisées et ouvertes)

MASSIF : Renoso Incudine

Rédigé le dimanche 15 mars 2026 à 15h

Conditions nivo-météo des 7 derniers jours

	lun. 09/03				mar. 10/03				mer. 11/03				jeu. 12/03				ven. 13/03				sam. 14/03				dim. 15/03			
	03h	09h	15h	21h	03h	09h	15h	21h	03h	09h	15h	21h	03h	09h	15h	21h	03h	09h	15h	21h	03h	09h	15h	21h	03h	09h	15h	21h
Météo																												
Vent (km/h)	15	15	15	20	20	30	20	20	20	30	40	40	30	30	30	30	25	15	5	5	10	30	50	35	25	40	70	60
à 2000m																												
Vent (km/h)	5	5	10	15	15	20	15	10	15	20	30	20	30	20	25	15	20	20	15	10	10	20	50	45	45	40	65	45
à 1500m																												

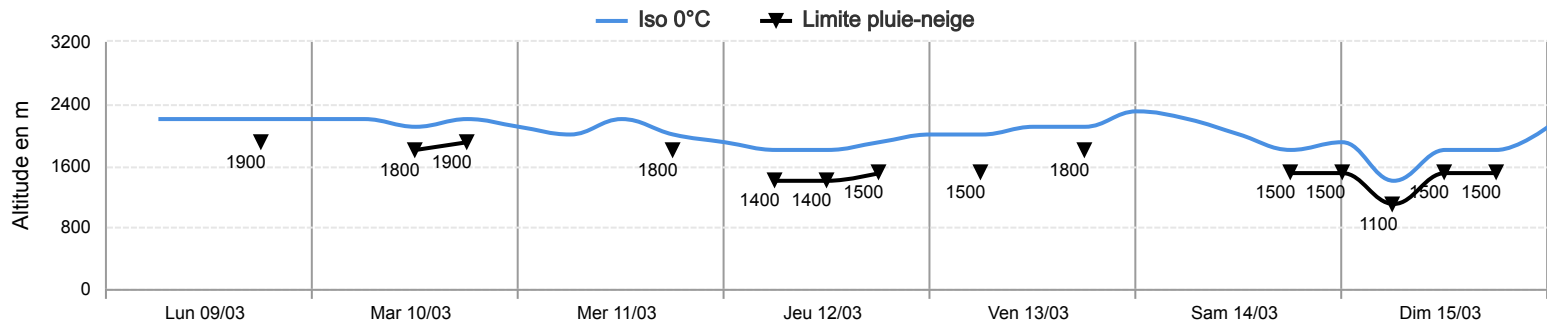

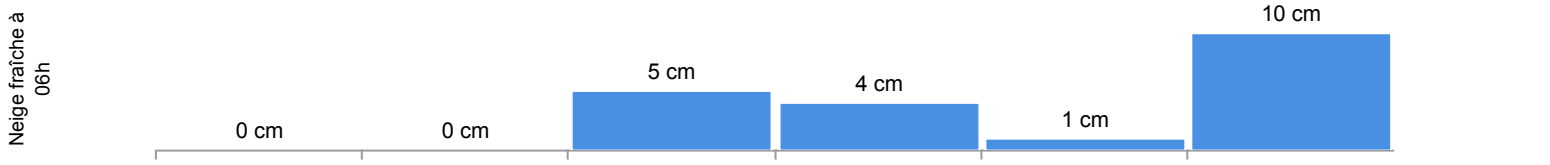

Risque d'avalanche	lun. 09/03	mar. 10/03	mer. 11/03	jeu. 12/03	ven. 13/03	sam. 14/03	dim. 15/03
	1	1	1	1	1	2	2

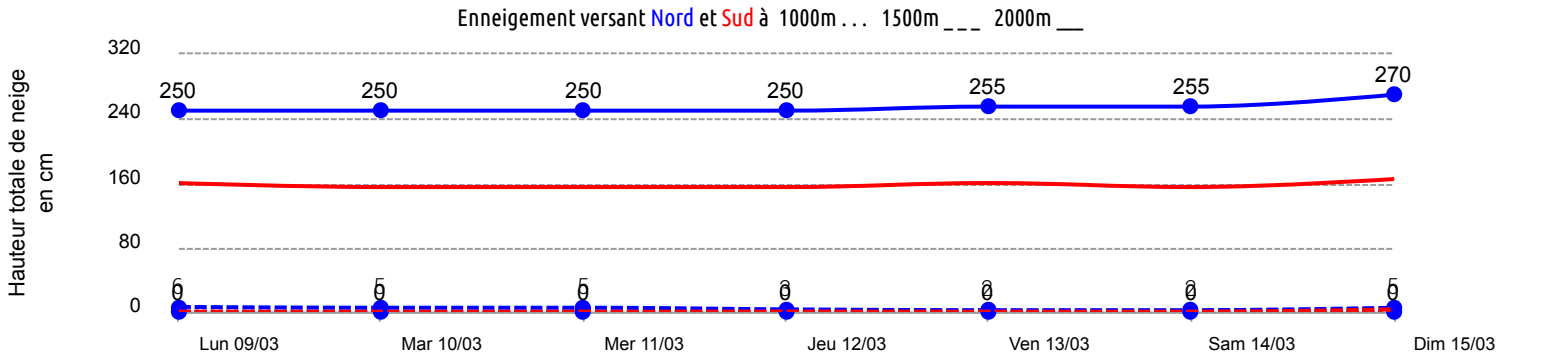

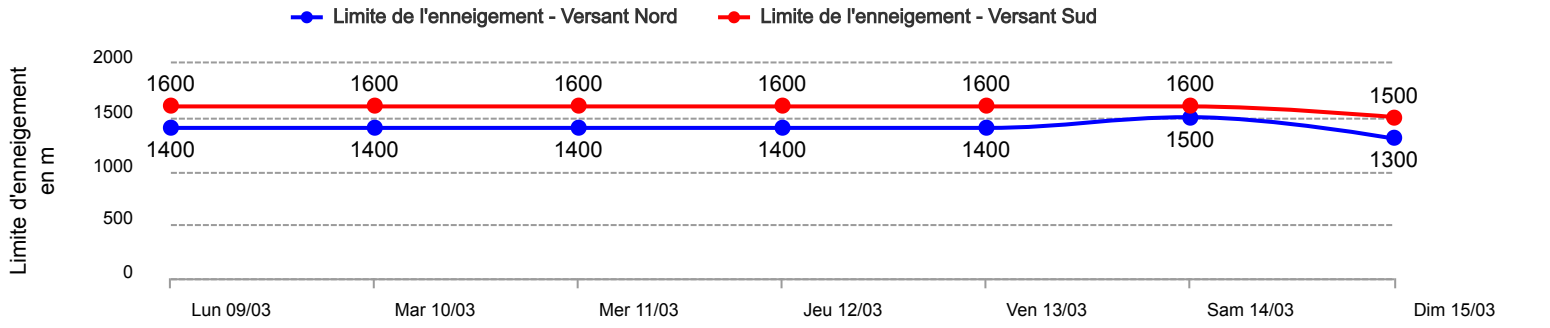

Pour consulter la vigilance en cours, veuillez vous rendre sur le site https://vigilance.meteofrance.fr/fr

Météo-France - 73 avenue de Paris, 94165 Saint-Mandé cedex - Contact : contact@meteo.fr

Rédigé par Météo-France avec la contribution des observateurs du réseau nivo-météorologiques. Partenariat : ANMSM (Maires de Stations de Montagne), DSF (Domaines Skiables de France), ADSP (Directeurs de Pistes et de la Sécurité des Stations de Sports d'Hiver) et autres acteurs de la montagne.

Bulletin neige & avalanches par téléphone au
0 892 68 10 20 Service 0,35 € / min + prix appel