Bulletin d'estimation du risque d'avalanche

(valable en dehors des pistes balisées et ouvertes)

MASSIF : Bauges

Rédigé le dimanche 15 mars 2026 à 16h

Estimation des risques pour le : LUNDI 16 MARS

INSTABILITÉS VENTÉES DANS LA NEIGE RÉCENTE.

2

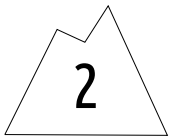

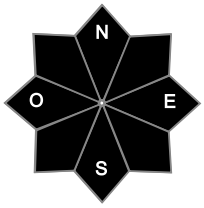

Indice de risque limité.

Départs spontanés : Quelques avalanches humides au soleil.

Déclenchements provoqués : Plaques à vent dans la neige récente.

Indices de risque : 5 très fort - 4 fort - 3 marqué - 2 limité - 1 faible -- En noir : les pentes les plus dangereuses

Stabilité du manteau neigeux

Situation avalancheuse typique : neige ventée neige humide

Déclenchements provoqués :

* **Plaques friables temporaires** dans la neige récente ventée. Elles sont facilement **déclenchables au passage d'un skieur**. Principalement de taille 1 et 2 (petites et moyennes) avec des cassures de 15/20 cm. On les retrouve principalement sous le vent de NW. Attention aux zones d'accumulations, où ces dernières sont un peu plus sensibles. Temporairement au soleil, ces plaques sont un peu plus réactives.

Départs spontanés :

* Des avalanches de neige humide peuvent partir spontanément sous l'effet du soleil dans les adrets au fil de l'ensoleillement. Taille 1 à 2.
* Au fil de la journée, des **reptations** peuvent s'ouvrir et ainsi, des avalanches de fond sont possibles à toute heure et en tout versant. Taille 2.

Qualité de la neige

Enneigement :

Il est correct pour la saison. On retrouve de la neige dès 1000/1200m. On retrouve un manteau réellement skiable à partir de 1200m en Nord et 1500m en Sud.

Qualité de la neige ce lundi :

- En surface, on retrouve une couche de neige récente un peu alourdit. Cette neige continue de se densifier en cours de journée, notamment dans les adrets. Dans les versants nord d'altitude qui ne voit que peu le soleil, cette neige reste encore un peu froide.
- Dans les adrets sous 1800m, évolution de printemps.
- Cette couche repose sur un manteau humide.

Aperçu météo pour le lundi 16 mars

nuit	matin	après-midi	soir

Globalement beaucoup de soleil, quelques passages nuageux en matinée.

Pluie-Neige				
Iso 0 °C	1 300 m	1 600 m	1 900 m	2 000 m
Vent 1500 m	↓ 10 km/h	↙ 15 km/h	↘ 15 km/h	↓ 10 km/h
Vent 2000 m	↘ 15 km/h	↘ 20 km/h	→ 20 km/h	↘ 15 km/h

Épaisseur de neige hors-piste

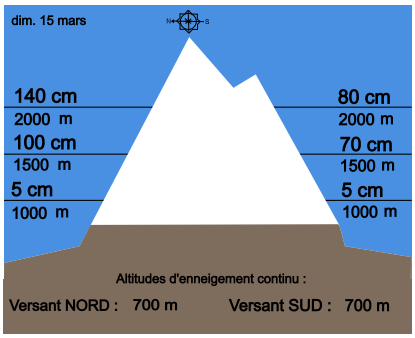

Précipitations à 1800 m

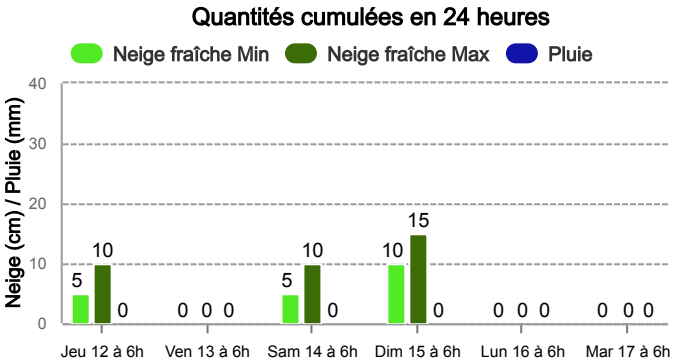

Tendance du mardi 17 mars

2

Indice de risque limité

Les instabilités temporaires de la neige de samedi se stabilisent. Les températures remontent nettement en journée de mardi, engendrant ainsi un risque de nombreuses coulées en adrets.

Pour consulter la vigilance en cours, veuillez vous rendre sur le site https://vigilance.meteofrance.fr/fr

Météo-France - 73 avenue de Paris, 94165 Saint-Mandé cedex - Contact : contact@meteo.fr

Rédigé par Météo-France avec la contribution des observateurs du réseau nivo-météorologiques. Partenariat : ANMSM (Maires de Stations de Montagne), DSF (Domaines Skiables de France), ADSP (Directeurs de Pistes et de la Sécurité des Stations de Sports d'Hiver) et autres acteurs de la montagne.

Bulletin neige & avalanches par téléphone au

0 892 68 10 20 Service 0,35 € / min + prix appel

RÉPUBLIQUE FRANÇAISE
Liberté Égalité Fraternité

METEO FRANCE
À VOS CÔTÉS, DANS UN CLIMAT QUI CHANGE

Bulletin d'estimation du risque d'avalanche
(valable en dehors des pistes balisées et ouvertes)

MASSIF : Bauges

Rédigé le dimanche 15 mars 2026 à 16h

Conditions nivo-météo des 7 derniers jours

	lun. 09/03				mar. 10/03				mer. 11/03				jeu. 12/03				ven. 13/03				sam. 14/03				dim. 15/03			
	03h	09h	15h	21h	03h	09h	15h	21h	03h	09h	15h	21h	03h	09h	15h	21h	03h	09h	15h	21h	03h	09h	15h	21h	03h	09h	15h	21h
Météo																												
Vent (km/h)	20	25	20	30	15	30	30	30	30	40	40	40	20	10	5	5	20	30	40	60	45	35	25	25	35	25	30	15
à 2000m																												
Vent (km/h)	5	20	15	25	10	20	20	20	20	20	30	30	15	5	0	0	10	20	25	50	35	25	20	20	30	20	25	10
à 1500m																												

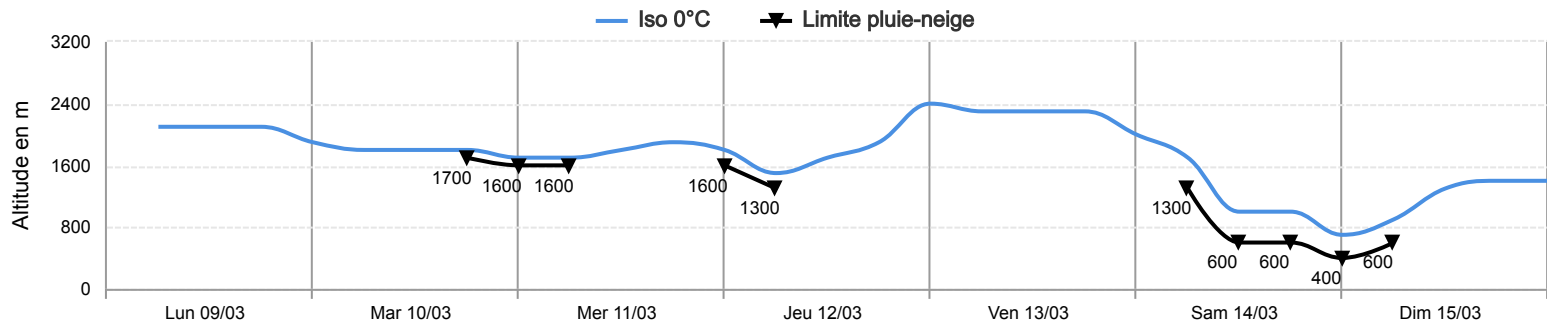

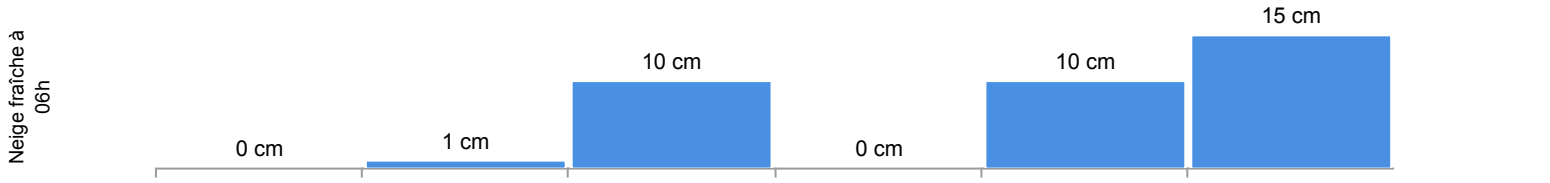

Risque d'avalanche	lun. 09/03	mar. 10/03	mer. 11/03	jeu. 12/03	ven. 13/03	sam. 14/03	dim. 15/03
	2	1	1	2	2	3	3

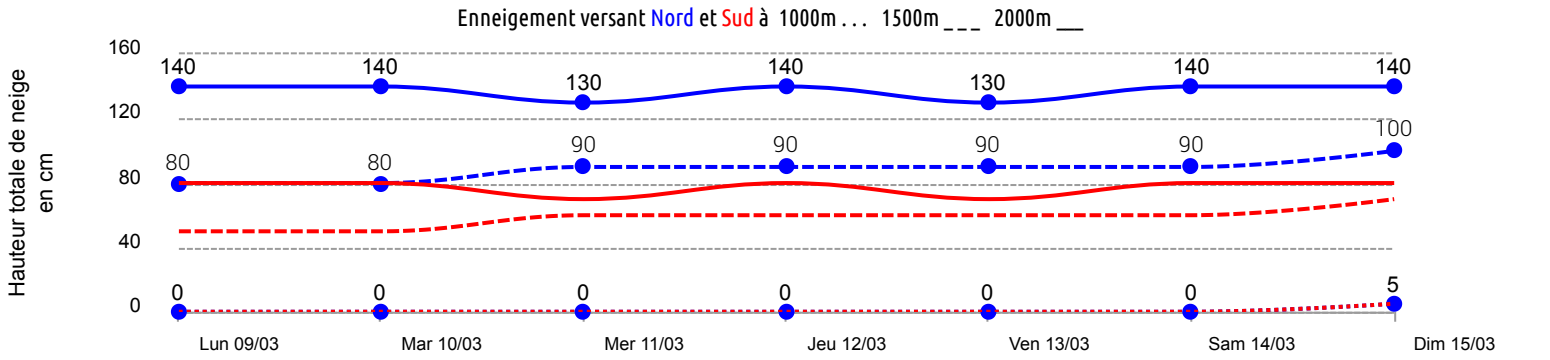

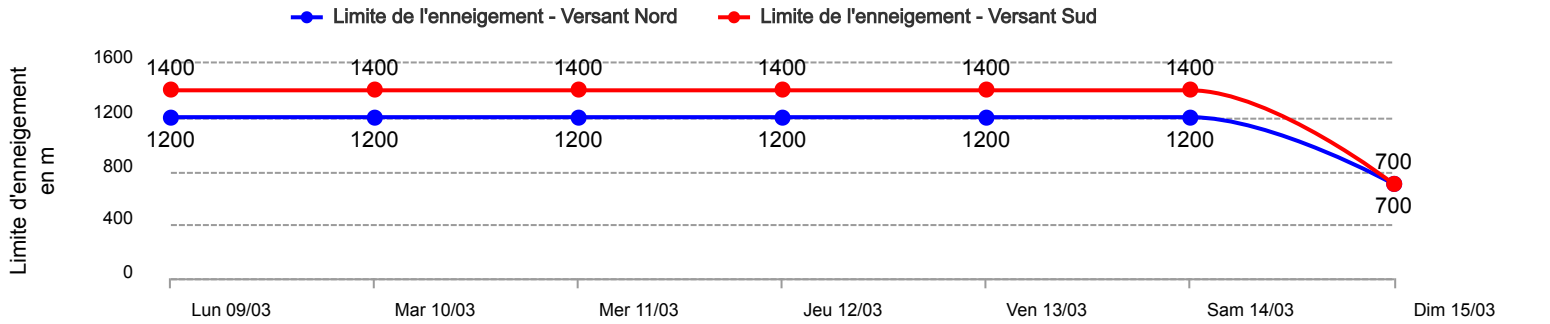

Pour consulter la vigilance en cours, veuillez vous rendre sur le site https://vigilance.meteofrance.fr/fr

Météo-France - 73 avenue de Paris, 94165 Saint-Mandé cedex - Contact : contact@meteo.fr

Rédigé par Météo-France avec la contribution des observateurs du réseau nivo-météorologiques. Partenariat : ANMSM (Maires de Stations de Montagne), DSF (Domaines Skiables de France), ADSP (Directeurs de Pistes et de la Sécurité des Stations de Sports d'Hiver) et autres acteurs de la montagne.

Bulletin neige & avalanches par téléphone au
0 892 68 10 20 Service 0,35 € / min + prix appel