Bulletin d'estimation du risque d'avalanche
(valable en dehors des pistes balisées et ouvertes)

MASSIF : Haut-Var Haut-Verdon

Rédigé le dimanche 15 mars 2026 à 16h

Estimation des risques pour le : LUNDI 16 MARS

INSTABILITÉ MARQUÉE DANS LA NEIGE RÉCENTE VENTÉE. QUELQUES DÉPARTS NATURELS EN NEIGE HUMIDE.

3

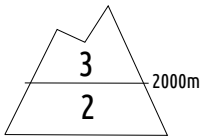

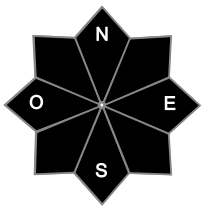

Au-dessus de 2000m indice de risque marqué, plus bas indice limité.

Départs spontanés : départs en neige récente s'humidifiant au soleil.

Déclenchements provoqués : nombreuses plaques faciles à déclencher.

Indices de risque : 5 très fort - 4 fort - 3 marqué - 2 limité - 1 faible -- En noir : les pentes les plus dangereuses

Stabilité du manteau neigeux

Situation avalancheuse typique : neige ventée neige humide

Déclenchements provoqués :
Nombreuses plaques en place dans la neige récente ventée, essentiellement au-dessus de 2000/2200 m, possibles en tous secteurs, mais plus fréquentes en de larges versants nord et ouest. Ces plaques peuvent être faciles à déclencher au passage d'un skieur, en particulier dans un large versant nord où elles sont plus sensibles car reposant sur la neige de la chute précédente restée poudreuse et faisant office de couche fragile. Elles peuvent être d'aspect poudreux et difficiles à détecter dans les secteurs peu ventées, ou durcies par le vent en zones exposées. Elles sont de taille petite à moyenne (taille 1 à 2).
A plus basse altitude, des plaques sont également possibles, mais moins nombreuses et généralement superficielles.

Départs spontanés :
Peu probables en début de journée après un bon regel nocturne, puis avalanches de neige récente s'humidifiant au soleil au fil de la journée. Départs ponctuels en pentes raides ensoleillées, de taille petite à parfois moyenne.

Qualité de la neige

Enneigement plutôt excédentaire sur le Haut-Verdon, dans les normales pour le Haut Var.
Données observées : vers 2000 m, 150 cm en fond de vallon dans le Haut Verdon, 135 cm dans le Haut Var.

Enneigement skiable : vers 1300/1500 m en ubacs, 1600/1800 m en adrets peu pentus.

État de la neige en surface : lundi matin, 20/25 cm de neige récente plus ou moins travaillée par le vent, répartie de manière hétérogène. Elle repose sur la neige de la semaine précédente, poudreuse ou légèrement densifiée par le vent en ubacs au-dessus de 2000/2200 m, croutée en dessous ainsi que dans les adrets. Sur les crêtes, des corniches épaisses côtoient des zones dégarnies par le vent.

Aperçu météo pour le lundi 16 mars

nuit	matin	après-midi	soir

Temps bien ensoleillé en journée, accompagné d'un redoux.

Pluie-Neige				
Iso 0 °C	2 200 m	2 500 m	2 600 m	2 800 m
Vent 2000 m	20 km/h	20 km/h	25 km/h	15 km/h
Vent 3000 m	50 km/h	30 km/h	35 km/h	30 km/h

Épaisseur de neige hors-piste

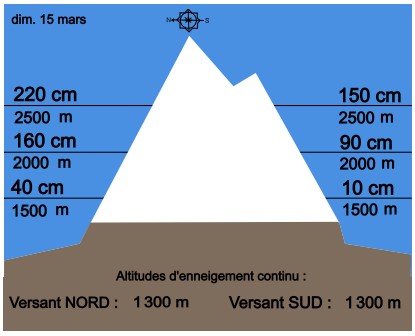

Précipitations à 1800 m

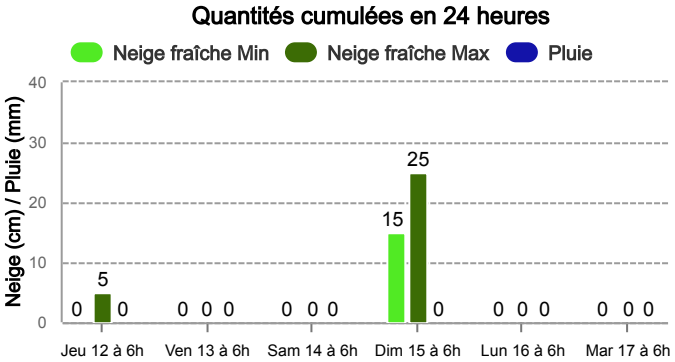

Tendance du mardi 17 mars

2

Indice de risque limité

Risque accidentel en baisse avec la stabilisation progressive des plaques en place. Activité naturelle modérée en neige humide, avec le bon ensoleillement et la douceur qui s'accentue.

Pour consulter la vigilance en cours, veuillez vous rendre sur le site https://vigilance.meteofrance.fr/fr

Météo-France - 73 avenue de Paris, 94165 Saint-Mandé cedex - Contact : contact@meteo.fr

Rédigé par Météo-France avec la contribution des observateurs du réseau nivo-météorologiques. Partenariat : ANMSM (Maires de Stations de Montagne), DSF (Domaines Skiables de France), ADSP (Directeurs de Pistes et de la Sécurité des Stations de Sports d'Hiver) et autres acteurs de la montagne.

Bulletin neige & avalanches par téléphone au
0 892 68 10 20 Service 0,35 € / min + prix appel

RÉPUBLIQUE FRANÇAISE
Liberté Égalité Fraternité

METEO FRANCE
À VOS CÔTÉS, DANS UN CLIMAT QUI CHANGE

Bulletin d'estimation du risque d'avalanche

(valable en dehors des pistes balisées et ouvertes)

MASSIF : Haut-Var Haut-Verdon

Rédigé le dimanche 15 mars 2026 à 16h

Conditions nivo-météo des 7 derniers jours

	lun. 09/03				mar. 10/03				mer. 11/03				jeu. 12/03				ven. 13/03				sam. 14/03				dim. 15/03			
	03h	09h	15h	21h	03h	09h	15h	21h	03h	09h	15h	21h	03h	09h	15h	21h	03h	09h	15h	21h	03h	09h	15h	21h	03h	09h	15h	21h
Météo																												
Vent (km/h)	15	20	30	50	40	25	20	20	15	30	45	40	40	30	20	20	20	10	15	15	40	50	30	20	60	70	45	25
à 3000m																												
Vent (km/h)	15	15	20	35	5	15	20	5	5	10	20	15	25	25	20	10	10	5	15	10	15	25	20	15	20	55	25	15
à 2000m																												

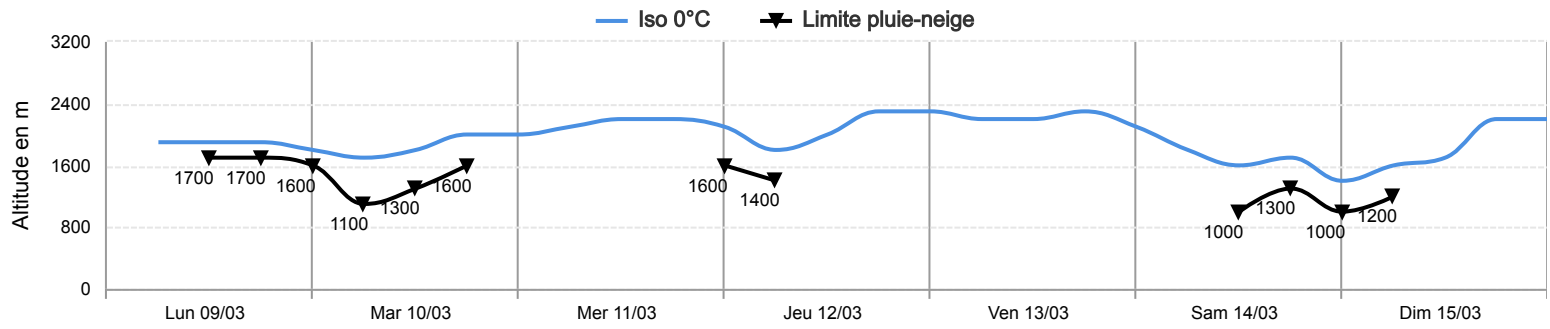

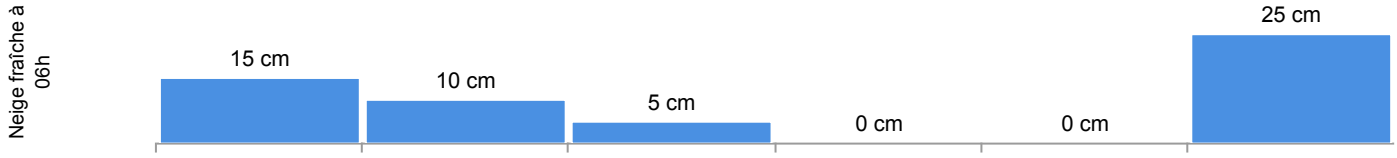

Risque d'avalanche	lun. 09/03	mar. 10/03	mer. 11/03	jeu. 12/03	ven. 13/03	sam. 14/03	dim. 15/03
	1	2	2	2	2	3	3

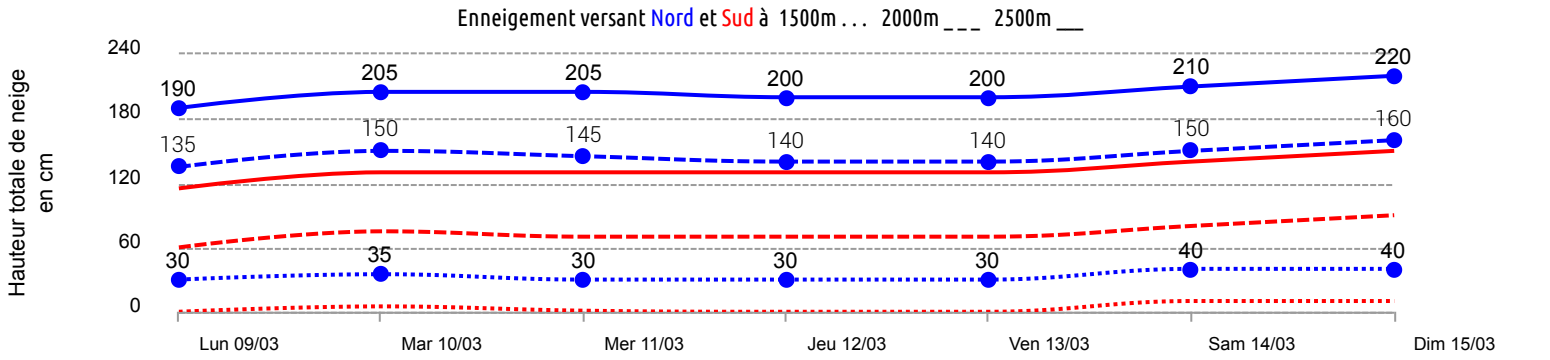

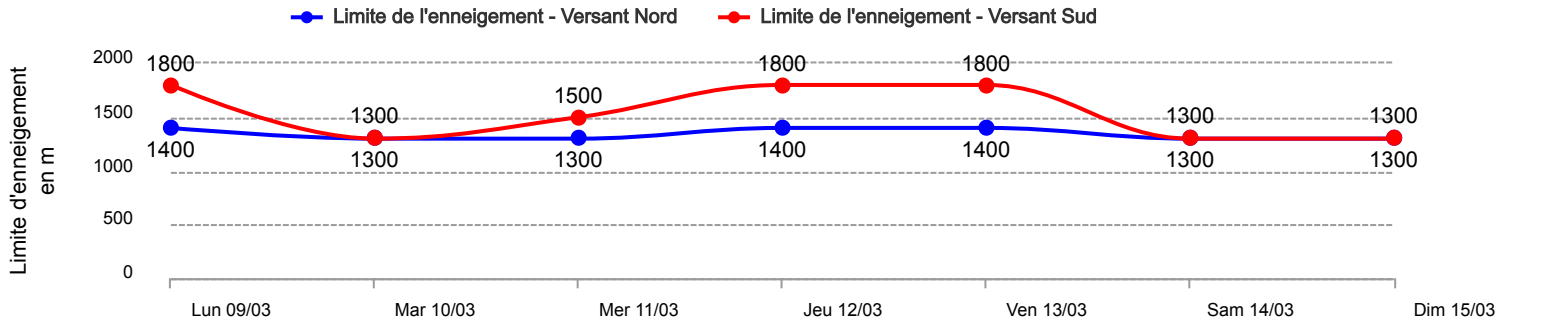

Pour consulter la vigilance en cours, veuillez vous rendre sur le site https://vigilance.meteofrance.fr/fr

Météo-France - 73 avenue de Paris, 94165 Saint-Mandé cedex - Contact : contact@meteo.fr

Bulletin neige & avalanches par téléphone au

0 892 68 10 20 Service 0,35 € / min + prix appel

Rédigé par Météo-France avec la contribution des observateurs du réseau nivo-météorologiques. Partenariat : ANMSM (Maires de Stations de Montagne), DSF (Domaines Skiables de France), ADSP (Directeurs de Pistes et de la Sécurité des Stations de Sports d'Hiver) et autres acteurs de la montagne.