Bulletin d'estimation du risque d'avalanche

(valable en dehors des pistes balisées et ouvertes)

MASSIF : Haute-Bigorre

Rédigé le dimanche 15 mars 2026 à 16h

Estimation des risques pour le : LUNDI 16 MARS

NEIGE VENTEE, NEIGE HUMIDE

3

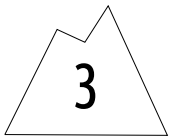

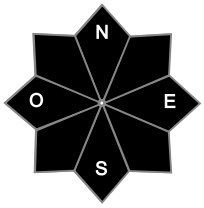

Indice de risque marqué.

Départs spontanés : Plaques ventées, neige s'humidifiant avec les éclaircies.

Déclenchements provoqués : Plaques instables dans la neige récente et sous le vent.

Indices de risque : 5 très fort - 4 fort - 3 marqué - 2 limité - 1 faible -- En noir : les pentes les plus dangereuses

Stabilité du manteau neigeux

Situation avalancheuse typique : neige ventée neige humide

DECLENCHEMENTS PROVOQUES : risque **marqué** (3).
Déclenchements **faciles par un seul skieur ou randonneur d'avalanches de plaques instables en toutes orientations**, sous le vent de nord. Les **plaques s'épaississent ce dimanche avec le vent de nord fort en altitude**, donnant lieu à des avalanches possibles de **taille 2 à 3 (moyenne 20-50 cm de cassure) à grande (>50 cm) en cas d'accumulations en pente raide (dépots plutôt en large sud à est) ou par emport du manteau jusqu'au sol en secteurs sud.**
Départs de blocs dans les versants exposés au vent de nord-ouest à nord, blocs rapidement pulvérulents en glissant dans les pentes déventées.

A noter au-dessus de 2400 m en secteurs froids, **possibles couches fragiles 15 cm sous la neige récente** des 36 dernières heures (donc situées **40 à 50 cm sous la surface**) avec des grains anguleux formées la semaine passée lors des nuits claires, les plaques y seront très facilement déclenchables.
Observables : plaques souvent **identifiables** avec les effets du vent, nombreux sastrugis et neige ridée. Toutes **fissures devant les skis ou les raquettes ou Wahouffs sous les skis en fonds de vallons.**

DEPARTS SPONTANES : risque modéré à marqué avec les éclaircies en **pentes raides en large sud**.
Départs ponctuels en général de neige humide avec les éclaircies, provoquant des **avalanches petites à quelquefois moyennes** au cours de la matinée. Des avalanches **moyennes plus fréquentes** en après-midi parfois sous forme de cassures linéaires. plus rarement de **grandes avalanches possibles** sous le vent en pentes **sud à sud-est sur le haut du massif.**

Qualité de la neige

Enneigement : L'enneigement est correct pour la saison, surtout au-dessus de 1800 m, mais reste assez maigre en versants exposés au vent d'Ouest et en versants Sud. Couche de 30 cm vers 1800 m en versants sud au lever du jour.
Limites skiables : A basse altitude, dès 1400 m ce lundi matin, mais sans sous-couche en-dessous de 1600 m en versants froids, 1900 m en versants Sud.
État de la neige : Fine croûte possible non portante en fin de nuit. Neige très travaillée par le vent de nord ce dimanche sur les sommets et pentes exposées, cartonnée près des crêtes, cols et sommets, restant meuble à l'abri du vent (clairières et combes déventées, notamment en sud). Neige rapidement molle en surface et s'humidifiant sous les éclaircies en journée lundi en versants ensoleillés.

Aperçu météo pour le lundi 16 mars

nuit	matin	après-midi	soir

Soleil en matinée lundi, des cumulus en journée et une mer de nuages en piémont en après-midi sous 1800 m, se dissipant en soirée.

Pluie-Neige				
Iso 0 °C	1 500 m	2 500 m	2 500 m	3 000 m
Vent 2000 m	20 km/h	15 km/h	15 km/h	10 km/h
Vent 3000 m	60 km/h	45 km/h	25 km/h	20 km/h

Épaisseur de neige hors-piste

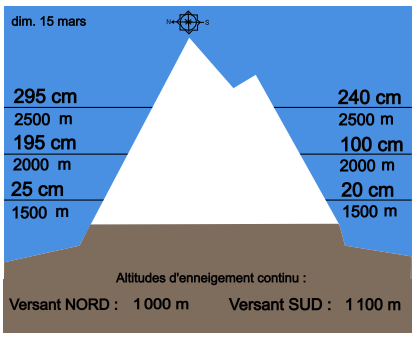

Précipitations à 1800 m

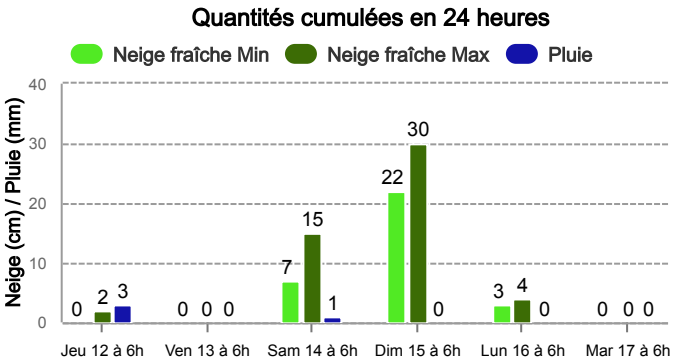

Tendance du mardi 17 mars

3 **Indice de risque marqué**

Humidification, les plaques deviennent plus rares et plus difficilement déclenchables sous le soleil, persitantes en raide nord. Avalanches de neige humide plus généralisées.

Pour consulter la vigilance en cours, veuillez vous rendre sur le site https://vigilance.meteofrance.fr/fr

Météo-France - 73 avenue de Paris, 94165 Saint-Mandé cedex - Contact : contact@meteo.fr

Rédigé par Météo-France avec la contribution des observateurs du réseau nivo-météorologiques. Partenariat : ANMSM (Maires de Stations de Montagne), DSF (Domaines Skiables de France), ADSP (Directeurs de Pistes et de la Sécurité des Stations de Sports d'Hiver) et autres acteurs de la montagne.

Bulletin neige & avalanches par téléphone au
0 892 68 10 20 Service 0,35 € / min + prix appel

RÉPUBLIQUE FRANÇAISE
Liberté Égalité Fraternité

METEO FRANCE
À VOS CÔTÉS, DANS UN CLIMAT QUI CHANGE

Bulletin d'estimation du risque d'avalanche

(valable en dehors des pistes balisées et ouvertes)

MASSIF : Haute-Bigorre

Rédigé le dimanche 15 mars 2026 à 16h

Conditions nivo-météo des 7 derniers jours

	lun. 09/03				mar. 10/03				mer. 11/03				jeu. 12/03				ven. 13/03				sam. 14/03				dim. 15/03			
	03h	09h	15h	21h	03h	09h	15h	21h	03h	09h	15h	21h	03h	09h	15h	21h	03h	09h	15h	21h	03h	09h	15h	21h	03h	09h	15h	21h
Météo																												
Vent (km/h)	10	15	20	15	15	10	45	35	40	65	60	55	40	30	55	60	35	60	60	50	55	60	80	95	95	90	85	60
à 3000m	↗	↗	↑	↗	↗	↑	↑	↗	→	→	↘	↓	↘	↘	↘	↘	→	↗	→	↗	↘	↘	↘	↓	↓	↓	↓	↙
Vent (km/h)	5	2	5	10	10	5	10	20	25	20	20	15	5	10	10	5	15	20	20	25	15	30	35	65	70	65	40	20
à 2000m	↑	↻	↻	↑	↑	↑	←	↗	↑	↗	↘	↓	↻	↘	↻	↻	→	↑	↗	↘	↓	↘	↘	↓	↓	↓	↓	↙

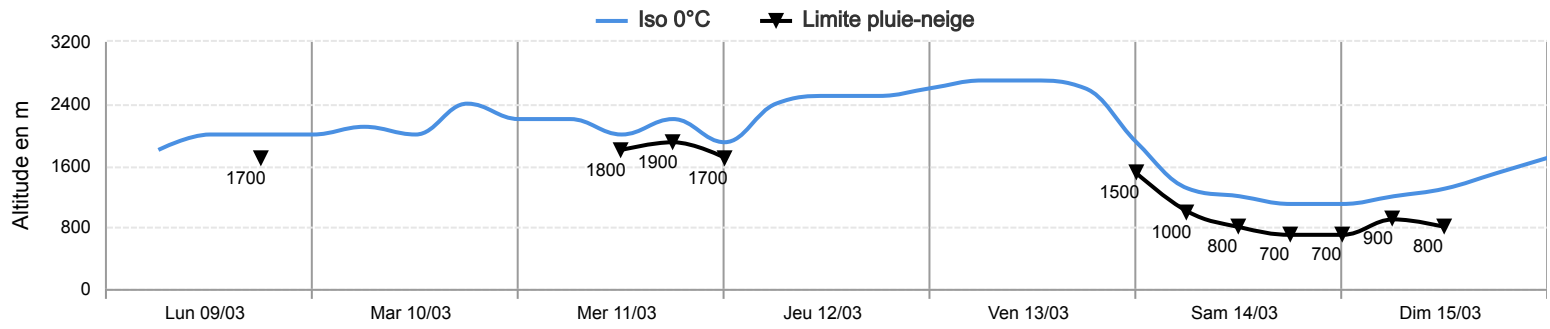

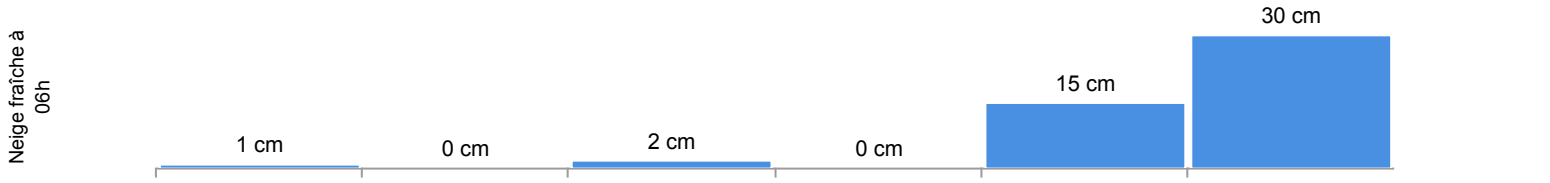

Risque d'avalanche	lun. 09/03	mar. 10/03	mer. 11/03	jeu. 12/03	ven. 13/03	sam. 14/03	dim. 15/03
	2	2	2	2	2	3	3

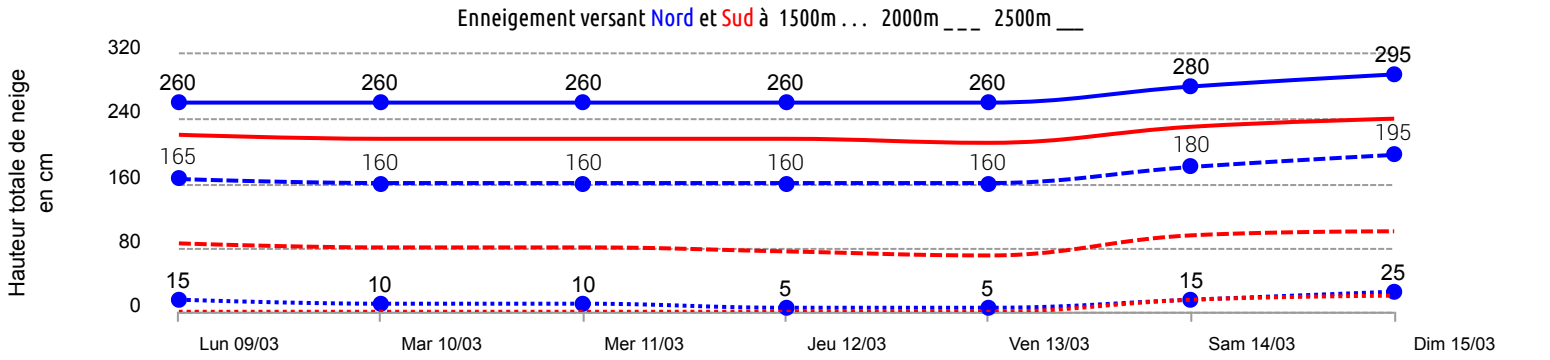

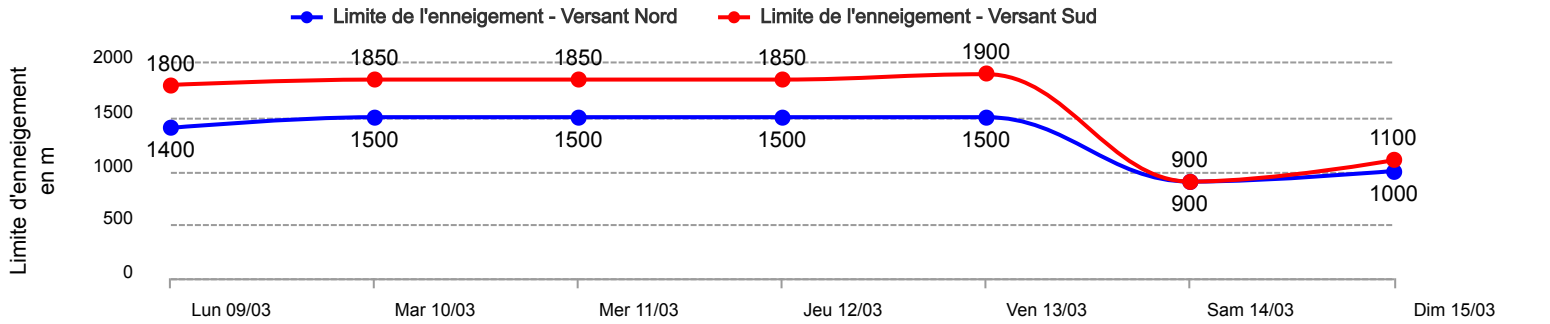

Pour consulter la vigilance en cours, veuillez vous rendre sur le site https://vigilance.meteofrance.fr/fr

Météo-France - 73 avenue de Paris, 94165 Saint-Mandé cedex - Contact : contact@meteo.fr

Rédigé par Météo-France avec la contribution des observateurs du réseau nivo-météorologiques. Partenariat : ANMSM (Maires de Stations de Montagne), DSF (Domaines Skiables de France), ADSP (Directeurs de Pistes et de la Sécurité des Stations de Sports d'Hiver) et autres acteurs de la montagne.

Bulletin neige & avalanches par téléphone au
0 892 68 10 20 Service 0,35 € / min + prix appel