Bulletin d'estimation du risque d'avalanche
(valable en dehors des pistes balisées et ouvertes)

MASSIF : Haute-Maurienne

Rédigé le dimanche 15 mars 2026 à 16h

Estimation des risques pour le : LUNDI 16 MARS

GRANDES QUANTITÉS DE NEIGE RÉCENTE, SURTOUT PRÈS DE LA FRONTIÈRE ITALIENNE : MANTEAU NEIGEUX INSTABLE.

3

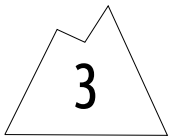

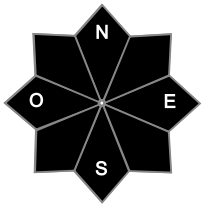

Indice de risque marqué.

Départs spontanés : nombreux départs dans la neige humide. // rares mais volumineux départs linéaires sous le vent.

Déclenchements provoqués : quelques plaques épaisses et encore faciles à déclencher.

Indices de risque : 5 très fort - 4 fort - 3 marqué - 2 limité - 1 faible -- En noir : les pentes les plus dangereuses

Stabilité du manteau neigeux

Situation avalancheuse typique : neige fraîche neige humide

Déclenchements provoqués : **quelques plaques faciles à déclencher dans la neige récente**, entretenues par le léger vent de nord-ouest qui se lève ce lundi. Ces plaques, d'**aspect poudreux**, sont très épaisses dans les secteurs frontaliers (notamment secteurs Avérole/Evettes/Carro/Bonneval) : **les cassures peuvent ici atteindre 1 m à 1 m 50** et engendrer de **grandes avalanches (taille 3)**. Dans les autres secteurs, les plaques sont moins épaisses : cassures max 50 à 80 cm. **A noter qu'en facteur aggravant,** cette chute de neige conséquente s'est localement déposée sur une fine couche de grains anguleux, ce qui rend les plaques particulièrement réactives dans les versants ombragés : un déclenchement à distance est alors possible.
Enfin, en journée dans les versants ensoleillés, il sera possible de déclencher une avalanche de neige humide en coupant une pente surchauffée.

Départs spontanés :
- **nombreux départs ponctuels en neige humide** dans les versants ensoleillés (est, sud puis ouest au fil de la journée). En particulier, les couloirs raides "se purgent". **Petites à moyennes avalanches, exceptionnellement une taille 3** si une plaque est ensuite mobilisée en cascade.
- **rares avalanches de plaque** près des crêtes ou au pied des barres rocheuses, sous le vent qui tourne au nord-ouest et se renforce en journée. Une **taille 3 est alors possible**.

Qualité de la neige

Enneigement : globalement très bon pour la saison.

Limite skiable : encore skiable dès 1100/1200 m dans les prairies orientées nord, plutôt 1400/1500 m en sud pas trop raide.

Qualité de la neige :
- en versants ombragés, grandes quantités de neige récente poudreuse, surtout dans les secteurs frontaliers (Carro/Evettes/Avérole), parfois légèrement densifiée près des crêtes (signe de plaque!)
- en versants ensoleillés, neige encore froide à l'aube qui va rapidement s'humidifier en journée (bottage jusqu'à haute altitude).

Aperçu météo pour le lundi 16 mars

nuit	matin	après-midi	soir

Quelques écharpes nuageuses le matin sous 2000/2500 m, puis du très beau temps. Vent de nord-ouest soutenu sur les crêtes, dès la matinée.

Pluie-Neige				
Iso 0 °C	1 800 m	1 900 m	2 000 m	2 000 m
Vent 2500 m	↘ 10 km/h	↘ 30 km/h	↘ 40 km/h	↘ 30 km/h
Vent 3500 m	↘ 20 km/h	↓ 50 km/h	↓ 50 km/h	↓ 40 km/h

Épaisseur de neige hors-piste

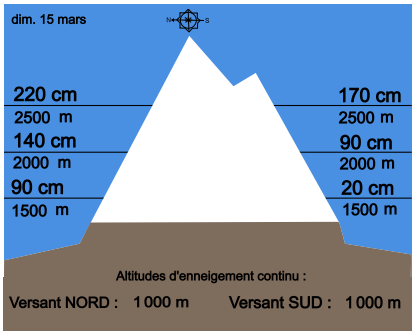

Précipitations à 1800 m

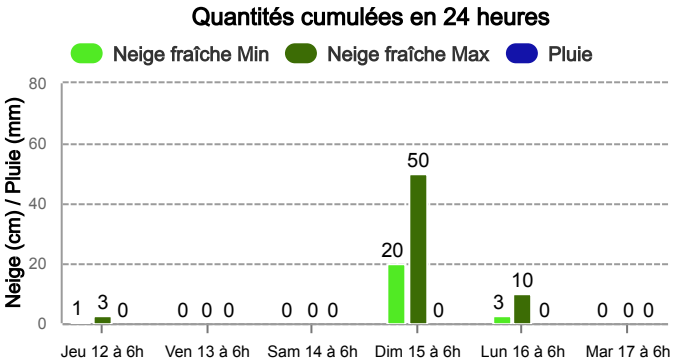

Tendance du mardi 17 mars

3

Indice de risque marqué

Stabilisation progressive du manteau, quelques plaques à vent bien réactives persistent encore en journée de mardi : le risque reste "marqué".

Pour consulter la vigilance en cours, veuillez vous rendre sur le site https://vigilance.meteofrance.fr/fr

Météo-France - 73 avenue de Paris, 94165 Saint-Mandé cedex - Contact : contact@meteo.fr

Rédigé par Météo-France avec la contribution des observateurs du réseau nivo-météorologiques. Partenariat : ANMSM (Maires de Stations de Montagne), DSF (Domaines Skiables de France), ADSP (Directeurs de Pistes et de la Sécurité des Stations de Sports d'Hiver) et autres acteurs de la montagne.

Bulletin neige & avalanches par téléphone au 0 892 68 10 20 Service 0,35 € / min + prix appel

RÉPUBLIQUE FRANÇAISE
Liberté Égalité Fraternité

METEO FRANCE
À VOS CÔTÉS, DANS UN CLIMAT QUI CHANGE

Bulletin d'estimation du risque d'avalanche

(valable en dehors des pistes balisées et ouvertes)

MASSIF : Haute-Maurienne

Rédigé le dimanche 15 mars 2026 à 16h

Conditions nivo-météo des 7 derniers jours

	lun. 09/03				mar. 10/03				mer. 11/03				jeu. 12/03				ven. 13/03				sam. 14/03				dim. 15/03			
	03h	09h	15h	21h	03h	09h	15h	21h	03h	09h	15h	21h	03h	09h	15h	21h	03h	09h	15h	21h	03h	09h	15h	21h	03h	09h	15h	21h
Météo																												
Vent (km/h)	15	15	20	25	30	30	30	20	20	25	35	45	30	20	20	10	10	10	15	55	40	20	30	30	20	40	30	20
à 3500m																												
Vent (km/h)	15	15	20	30	25	20	15	10	10	10	25	35	20	10	10	5	5	5	10	40	30	10	25	25	10	25	10	10
à 2500m																												

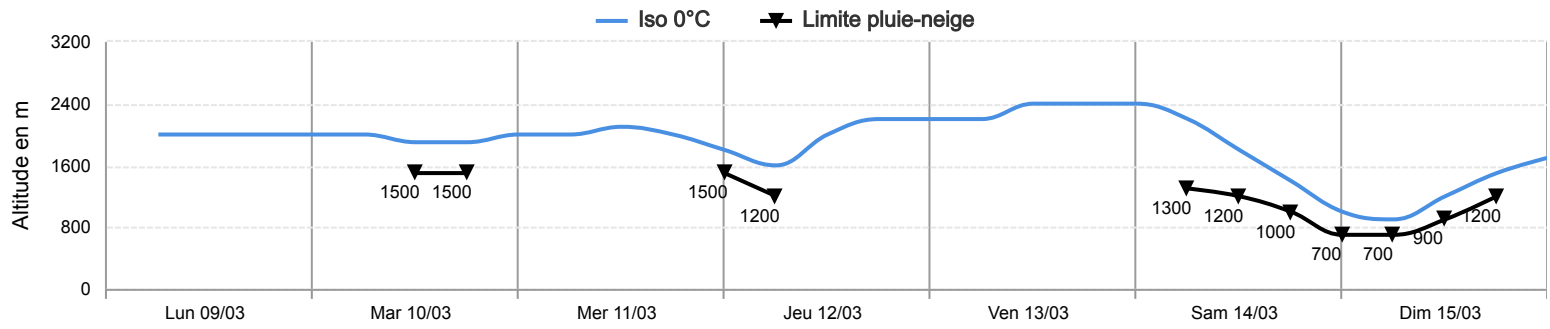

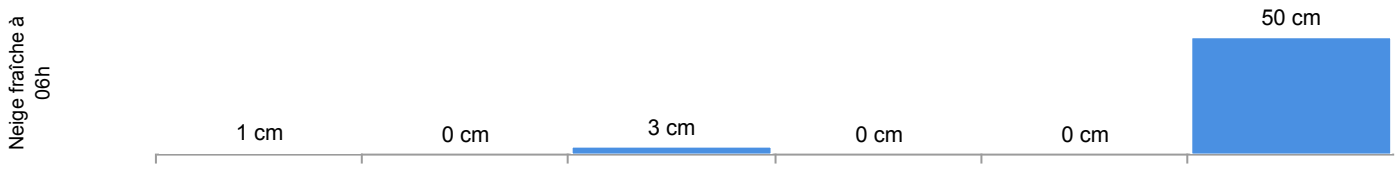

Risque d'avalanche	lun. 09/03	mar. 10/03	mer. 11/03	jeu. 12/03	ven. 13/03	sam. 14/03	dim. 15/03
	2	2	2	2	2	3	4

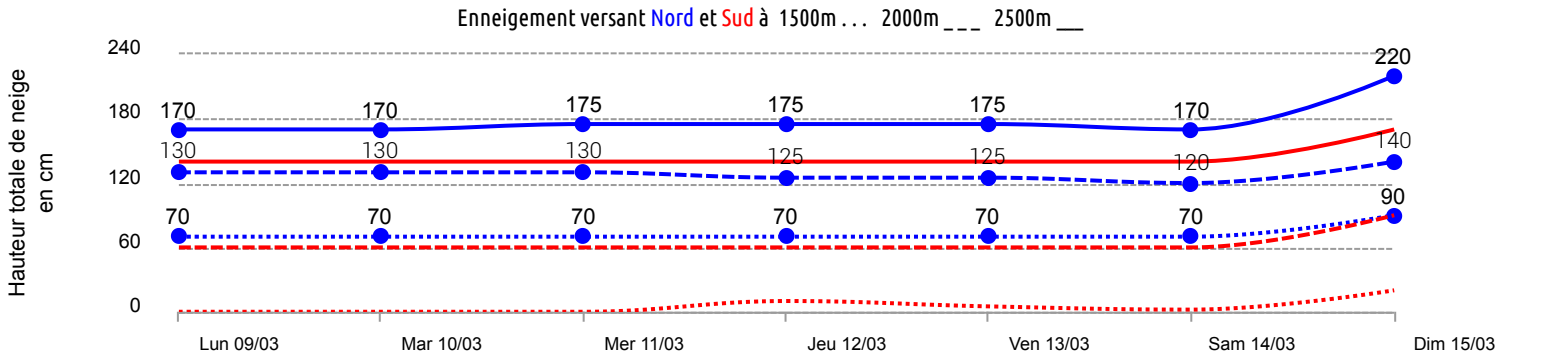

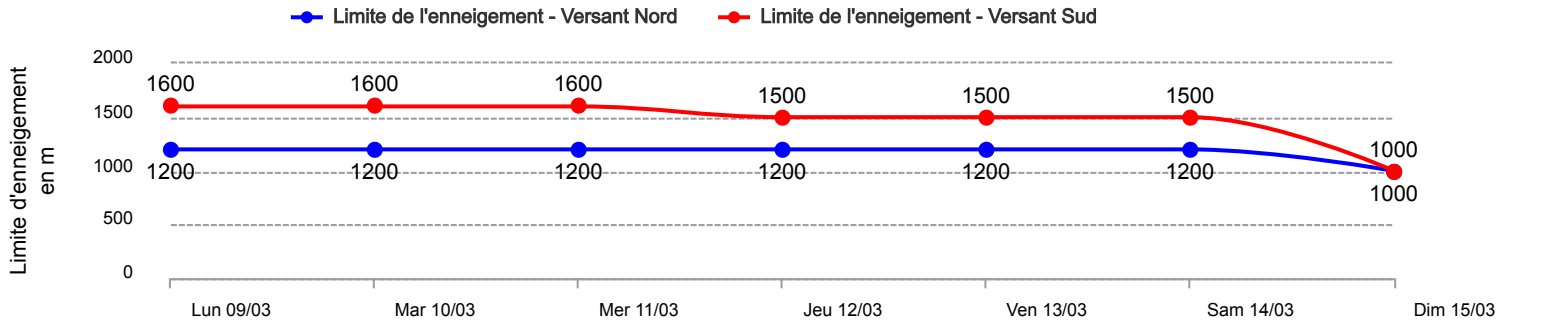

Pour consulter la vigilance en cours, veuillez vous rendre sur le site https://vigilance.meteofrance.fr/fr

Météo-France - 73 avenue de Paris, 94165 Saint-Mandé cedex - Contact : contact@meteo.fr

Rédigé par Météo-France avec la contribution des observateurs du réseau nivo-météorologiques. Partenariat : ANMSM (Maires de Stations de Montagne), DSF (Domaines Skiables de France), ADSP (Directeurs de Pistes et de la Sécurité des Stations de Sports d'Hiver) et autres acteurs de la montagne.

Bulletin neige & avalanches par téléphone au
0 892 68 10 20 Service 0,35 € / min + prix appel