Bulletin d'estimation du risque d'avalanche
(valable en dehors des pistes balisées et ouvertes)

MASSIF : Oisans

Rédigé le dimanche 15 mars 2026 à 16h

Estimation des risques pour le : LUNDI 16 MARS

NOMBREUSES PLAQUES A VENT FACILES A DECLENCHER, NOMBREUSES PURGES EN PENTES ENSOLEILLEES

3

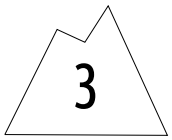

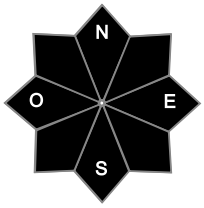

Indice de risque marqué.

Départs spontanés : Sous le soleil de très nombreuses purges sont à attendre en journée

Déclenchements provoqués : Nombreuses plaques à vent toujours réactives

Indices de risque : 5 très fort - 4 fort - 3 marqué - 2 limité - 1 faible -- En noir : les pentes les plus dangereuses

Stabilité du manteau neigeux

Situation avalancheuse typique : neige ventée neige humide

Déclenchements provoqués : De nombreuses plaques se sont formées dans la neige récente sous l'effet du vent (de Nord puis d'Est). Elles sont encore réactives en tout versants au lever du jour, mais se stabilisent dans les pentes ensoleillées au fil de la journée. Elles sont plus nombreuses en altitude, mais on peut les retrouver de partout dans les pentes et sont parfois difficiles à identifier (plutôt d'aspect dures vers les crête et d'aspect poudreuse dense plus bas dans les pentes). En journée, quelques plaques peuvent encore se former en altitude avec la reprise du vent de Nord. Ces dernières se retrouveront surtout près des crêtes, et seront plus réactives (car plus récentes) mais également plus faciles à identifier.
Observables : Transport en cours, neige travaillée par le vent, fissures devant les skis. Test du bâton éventuellement (neige plus dense en surface, plus meuble en profondeur)
En versants Nord d'altitude, des couches fragiles restent profondément enfouies dans le manteau. Elles semblent maintenant franchement difficiles à solliciter, mais le risque d'un départ en cascade, provoqué par le départ d'une plaque de surface ne peut être exclu.
Départs spontanés : Au fil de la journée de nombreux départs en poire (tailles petites, parfois moyennes) sont à attendre au soleil, principalement sous les rochers.

Qualité de la neige

Qualification de l'enneigement : L'enneigement est bon pour la saison en versants ombragés au dessus de 1300 m. Il est correct en Sud mais les sous-couches sont rares sous 1700 / 1800m.
Limites skiables : Vers 1100/1500m hors sapins.

Qualité de la neige lundi : Très variable. Encore poudreux en forêts / combes abritées. Ailleurs, souvent densifié par le vent voire cartonnée. Les crêtes sont mêmes pelées, en neige très dure / croûtées. En journée, le manteau s'alourdit puis s'humidifie rapidement au soleil.

Aperçu météo pour le lundi 16 mars

nuit	matin	après-midi	soir

Belle journée ensoleillée, quelques voiles d'altitude l'après-midi. Vent de Nord sensible en altitude.

Pluie-Neige				
Iso 0 °C	2 000 m	2 400 m	2 500 m	2 600 m
Vent 2500 m	← 20 km/h	↓ 20 km/h	↓ 20 km/h	↓ 35 km/h
Vent 3500 m	↓ 60 km/h	↓ 50 km/h	↓ 50 km/h	↓ 60 km/h

Épaisseur de neige hors-piste

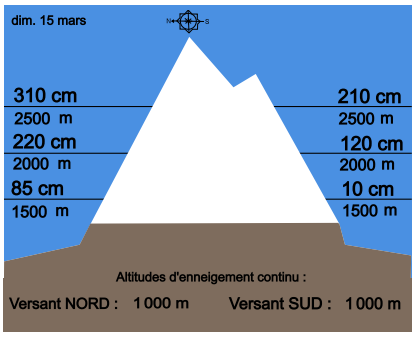

Précipitations à 1800 m

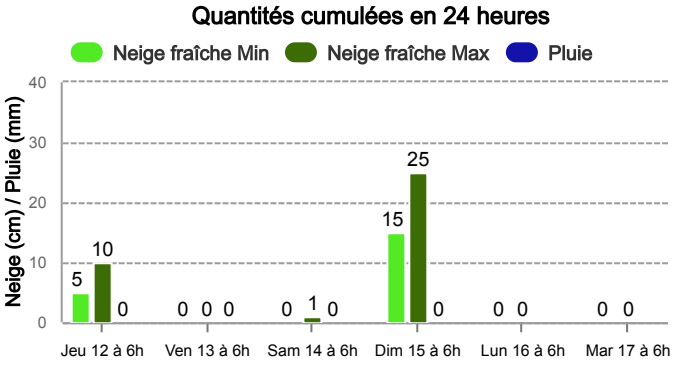

Tendance du mardi 17 mars

2

Indice de risque limité

Mardi, le redoux s'intensifie et les plaques présentes en versant froid se stabilisent. Au soleil, encore quelques purges. Quelques plaques de fond également possibles.

Pour consulter la vigilance en cours, veuillez vous rendre sur le site https://vigilance.meteofrance.fr/fr

Météo-France - 73 avenue de Paris, 94165 Saint-Mandé cedex - Contact : contact@meteo.fr

Rédigé par Météo-France avec la contribution des observateurs du réseau nivo-météorologiques. Partenariat : ANMSM (Maires de Stations de Montagne), DSF (Domaines Skiables de France), ADSP (Directeurs de Pistes et de la Sécurité des Stations de Sports d'Hiver) et autres acteurs de la montagne.

Bulletin neige & avalanches par téléphone au
0 892 68 10 20 Service 0,35 € / min + prix appel

RÉPUBLIQUE FRANÇAISE
Liberté Égalité Fraternité

METEO FRANCE
À VOS CÔTÉS, DANS UN CLIMAT QUI CHANGE

Bulletin d'estimation du risque d'avalanche
(valable en dehors des pistes balisées et ouvertes)

MASSIF : Oisans

Rédigé le dimanche 15 mars 2026 à 16h

Conditions nivo-météo des 7 derniers jours

	lun. 09/03				mar. 10/03				mer. 11/03				jeu. 12/03				ven. 13/03				sam. 14/03				dim. 15/03			
	03h	09h	15h	21h	03h	09h	15h	21h	03h	09h	15h	21h	03h	09h	15h	21h	03h	09h	15h	21h	03h	09h	15h	21h	03h	09h	15h	21h
Météo																												
Vent (km/h)	20	20	40	40	35	35	20	15	20	25	30	25	35	35	25	15	15	20	40	55	60	45	25	70	60	50	30	20
à 3500m																												
Vent (km/h)	10	10	35	35	30	25	15	10	10	15	20	15	25	40	15	10	10	15	35	40	40	20	20	55	50	35	15	10
à 2500m																												

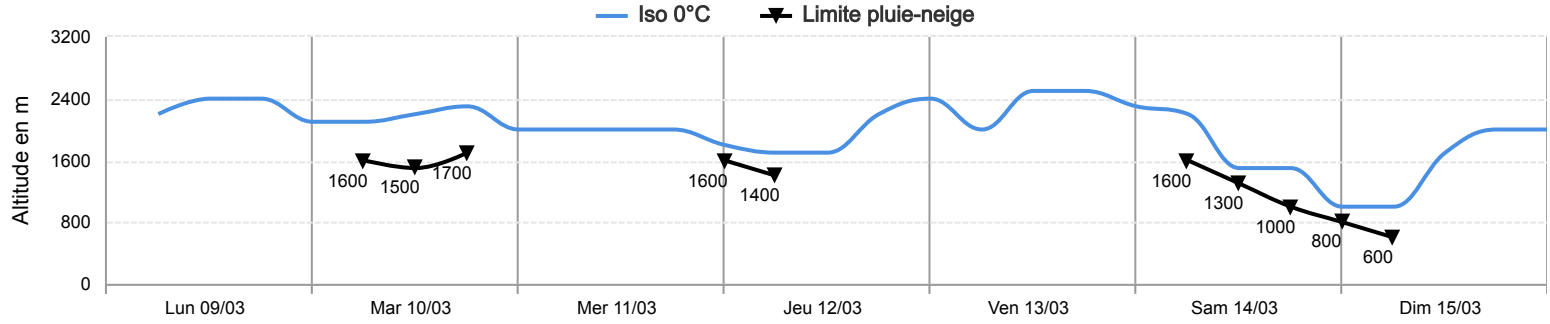

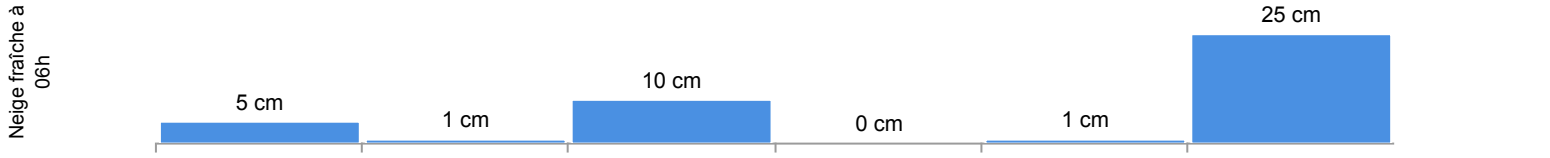

Risque d'avalanche	lun. 09/03	mar. 10/03	mer. 11/03	jeu. 12/03	ven. 13/03	sam. 14/03	dim. 15/03
	2	2	2	2	3	3	3

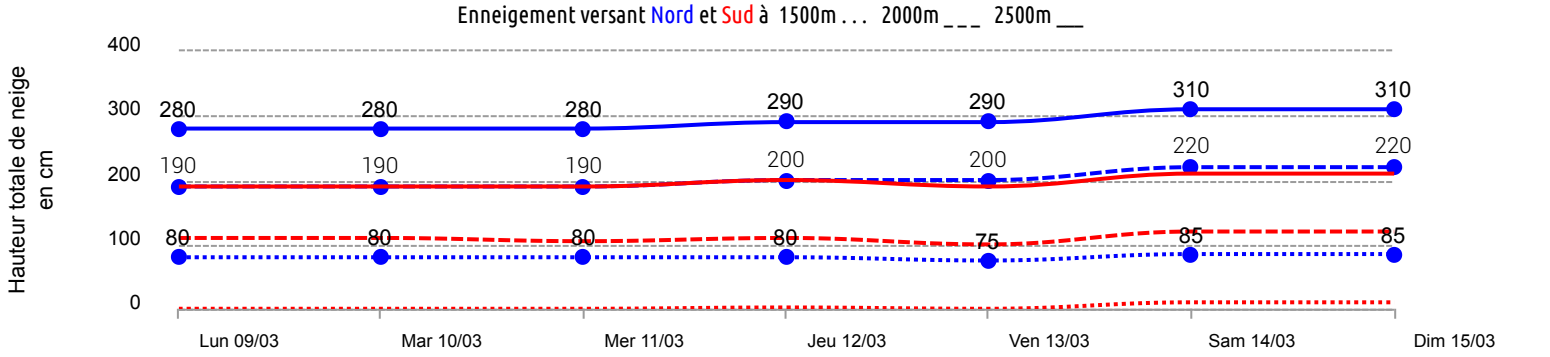

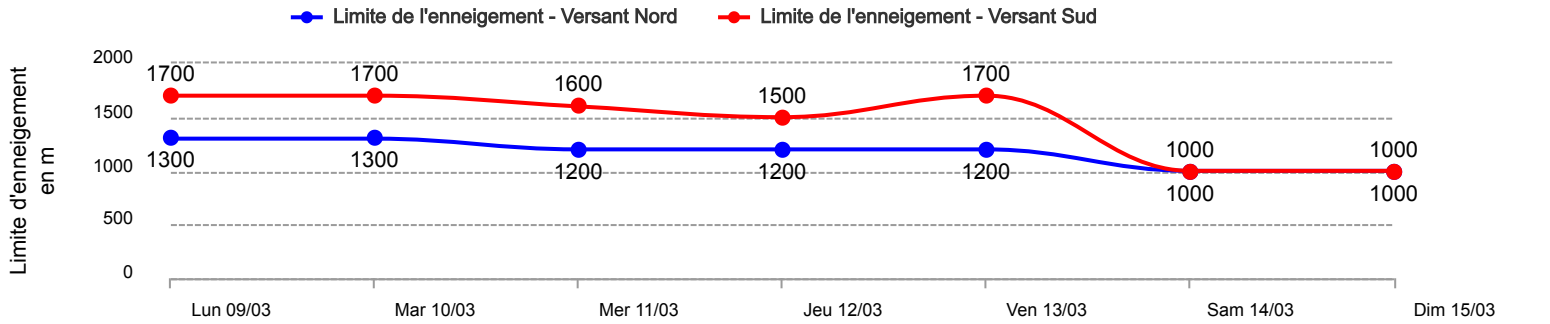

Pour consulter la vigilance en cours, veuillez vous rendre sur le site https://vigilance.meteofrance.fr/fr

Météo-France - 73 avenue de Paris, 94165 Saint-Mandé cedex - Contact : contact@meteo.fr

Rédigé par Météo-France avec la contribution des observateurs du réseau nivo-météorologiques. Partenariat : ANMSM (Maires de Stations de Montagne), DSF (Domaines Skiables de France), ADSP (Directeurs de Pistes et de la Sécurité des Stations de Sports d'Hiver) et autres acteurs de la montagne.

Bulletin neige & avalanches par téléphone au

0 892 68 10 20 Service 0,35 € / min + prix appel