RÉPUBLIQUE FRANÇAISE
Liberté Égalité Fraternité

METEO FRANCE
À VOS CÔTÉS, DANS UN CLIMAT QUI CHANGE

Bulletin d'estimation du risque d'avalanche

(valable en dehors des pistes balisées et ouvertes)

MASSIF : Orlu St-Barthelemy

Rédigé le dimanche 15 mars 2026 à 16h

Estimation des risques pour le : LUNDI 16 MARS

NOMBREUSES PLAQUES ET REDOUX

3

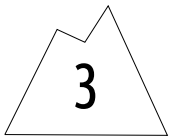

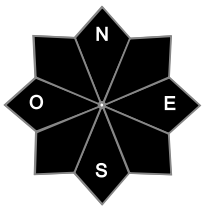

Indice de risque marqué.

Départs spontanés : Avec l'ensoleillement, et par surcharge du à un transport encore actif en début de journée

Déclenchements provoqués : Nombreuses plaques encore facilement déclenchables sous le vent et dans la neige récente

Indices de risque : 5 très fort - 4 fort - 3 marqué - 2 limité - 1 faible -- En noir : les pentes les plus dangereuses

Stabilité du manteau neigeux

Situation avalancheuse typique : neige ventée neige humide

Déclenchements provoqués :
Nombreuses structures de plaques facilement déclenchables dans la neige récente. Elles donneront principalement des avalanches de taille 1 à 2. En altitude, avec un vent turbulent qui a soufflé très fort dimanche proche de la frontière, elles pourront localement donner des avalanches de taille 3. A noter que ces plaque sont parfois situées loin des crêtes. Elles sont plutôt dures dans les zones ventées, plutôt friables dans des zones un peu plus protégées. La couche fragile est majoritairement constituée de neige fraiche moins ventée. Localement, dans les secteurs froids d'altitude (typiquement au dessus de 2400m dans un large secteur nord), il est possible que des grains facettés ou du givre de surface formés lors des nuits claires de la semaine dernière puissent aussi jouer ce rôle.
(Observables : traces d'avalanches récentes, fissures sous les skis, affaissement accompagné de 'whoomf', signes de transport par le vent)

Départs spontanés :
- Départs ponctuels ou linéaires possibles au soleil avec avec un manteau qui s'humidifie progressivement en dessous de 2400m environ. Avalanches de surface de taille 1 à 2 attendues, emportant la neige récente.
- Avalanches de fond possible en terrain herbeux ou sur des roches lisses préalablement découvertes avant les chutes du week-end (taille 1 à 2). *(Observable : fissures, reptations récentes)*
- Principalement en matinée et au dessus de 2000m, départs spontanés linéaires attendus par surcharge d'une couche fragile présente au sein ou à la base de la couche de neige fraîche. Le transport par le vent est en effet encore un peu actif en début de journée là où la neige est restée froide et légère. Ces départs pourront conduire à des avalanches de taille 2, voire 3 (grande) dans les accumulations les plus importantes (cf déclenchements provoqués).
(Observables : accumulations, transport de neige par le vent)

Qualité de la neige

Enneigement :
Après plusieurs hivers déficitaires, l'enneigement sur le massif est cette année largement excédentaire.
Une trentaine de cm sont tombé en altitude ce week-end, assez hétérogènes à cause du vent. La fonte débute avec le redoux prévu ce jour.

Limites skiables :
Lundi matin, on pourra envisager de chausser les skis vers 1200m en terrain herbeux, mais sans véritable sous-couche en dessous de 1500m en versants froids, 1800/1900m en versants sud.

État de la neige :
Neige restée froide et légère à l'ombre et en altitude. Bon regel matinal là où le soleil avait commencé à l'humidifier en surface dimanche. En altitude, la neige sera frittée à cartonnée près des crêtes, cols et sommets, restant meuble à l'abri du vent (clairières et combes déventées notamment). Elle s'humidifiera en surface avec le soleil en journée dans les pentes en dessous de 2400m environ.

Aperçu météo pour le lundi 16 mars

	nuit	matin	après-midi	soir
Redoux et diminution progressive du vent				
Pluie-Neige				
Iso 0 °C	1 300 m	2 100 m	2 500 m	2 800 m
Vent 2000 m	35 km/h	30 km/h	30 km/h	20 km/h
Vent 3000 m	85 km/h	50 km/h	50 km/h	45 km/h

Pour consulter la vigilance en cours, veuillez vous rendre sur le site https://vigilance.meteofrance.fr/fr

Météo-France - 73 avenue de Paris, 94165 Saint-Mandé cedex - Contact : contact@meteo.fr

Rédigé par Météo-France avec la contribution des observateurs du réseau nivo-météorologiques. Partenariat : ANMSM (Maires de Stations de Montagne), DSF (Domaines Skiables de France), ADSP (Directeurs de Pistes et de la Sécurité des Stations de Sports d'Hiver) et autres acteurs de la montagne.

Bulletin neige & avalanches par téléphone au
0 892 68 10 20 Service 0,35 € / min + prix appel

Bulletin d'estimation du risque d'avalanche

(valable en dehors des pistes balisées et ouvertes)

MASSIF : Orlu St-Barthelemy

Rédigé le dimanche 15 mars 2026 à 16h

Épaisseur de neige hors-piste

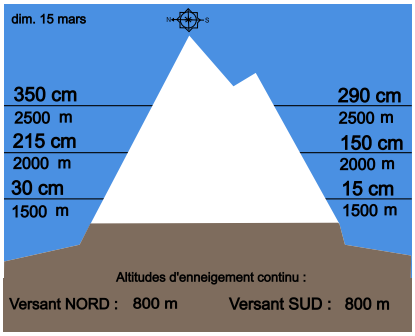

Précipitations à 1800 m

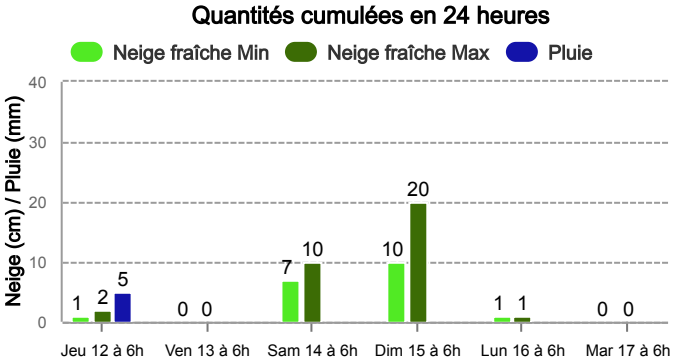

Tendance du mardi 17 mars

Indice de risque marqué

Maintien d'un risque marqué avec le redoux prévu et l'accentuation de l'humidification du manteau.

Pour consulter la vigilance en cours, veuillez vous rendre sur le site https://vigilance.meteofrance.fr/fr

Météo-France - 73 avenue de Paris, 94165 Saint-Mandé cedex - Contact : contact@meteo.fr

Rédigé par Météo-France avec la contribution des observateurs du réseau nivo-météorologiques. Partenariat : ANMSM (Maires de Stations de Montagne), DSF (Domaines Skiables de France), ADSP (Directeurs de Pistes et de la Sécurité des Stations de Sports d'Hiver) et autres acteurs de la montagne.

Bulletin neige & avalanches par téléphone au

0 892 68 10 20 Service 0,35 € / min + prix appel

RÉPUBLIQUE FRANÇAISE
Liberté Égalité Fraternité

METEO FRANCE
À VOS CÔTÉS, DANS UN CLIMAT QUI CHANGE

Bulletin d'estimation du risque d'avalanche

(valable en dehors des pistes balisées et ouvertes)

MASSIF : Orlu St-Barthelemy

Rédigé le dimanche 15 mars 2026 à 16h

Conditions nivo-météo des 7 derniers jours

	lun. 09/03				mar. 10/03				mer. 11/03				jeu. 12/03				ven. 13/03				sam. 14/03				dim. 15/03			
	03h	09h	15h	21h	03h	09h	15h	21h	03h	09h	15h	21h	03h	09h	15h	21h	03h	09h	15h	21h	03h	09h	15h	21h	03h	09h	15h	21h
Météo																												
Vent (km/h)	20	15	15	15	15	20	20	15	20	30	50	55	40	30	25	25	25	25	30	40	50	50	55	70	80	80	65	75
à 3000m																												
Vent (km/h)	10	10	10	5	5	5	10	10	10	15	25	35	30	20	15	15	15	15	15	25	30	30	35	45	70	65	50	30
à 2000m																												

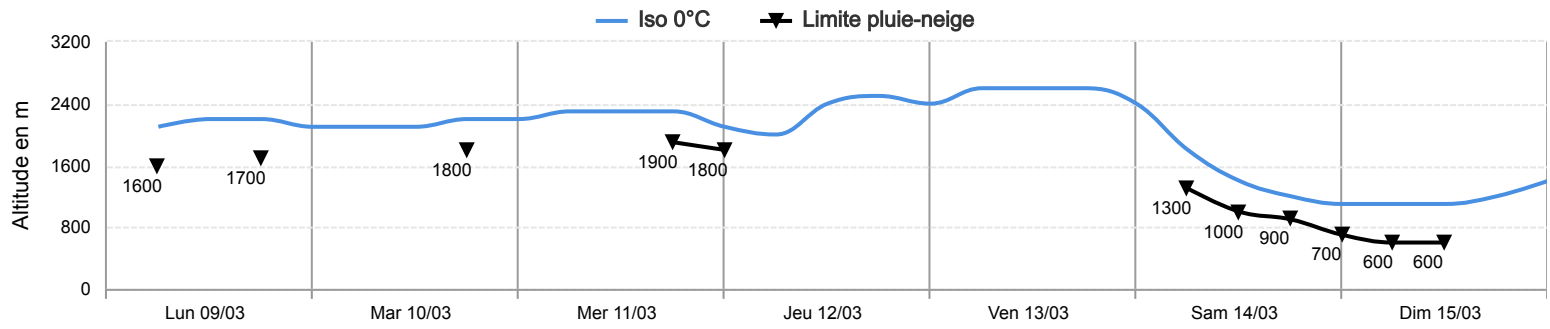

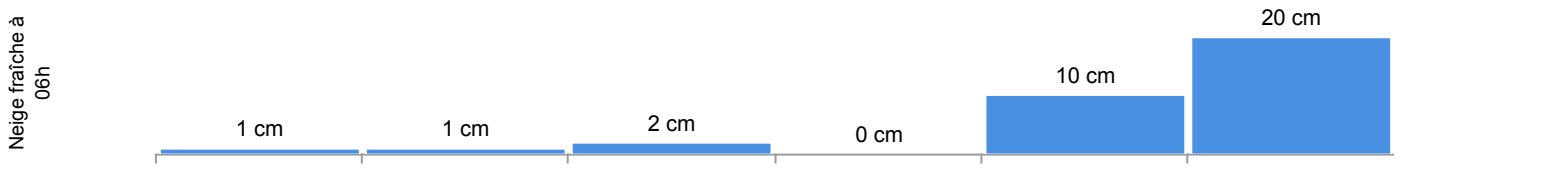

Risque d'avalanche	lun. 09/03	mar. 10/03	mer. 11/03	jeu. 12/03	ven. 13/03	sam. 14/03	dim. 15/03
	2	2	2	2	2	3	3

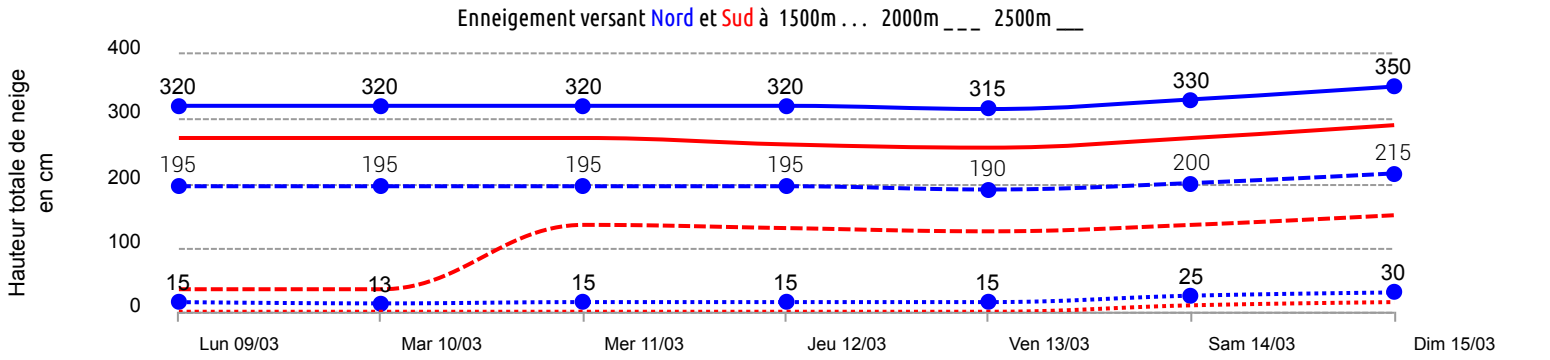

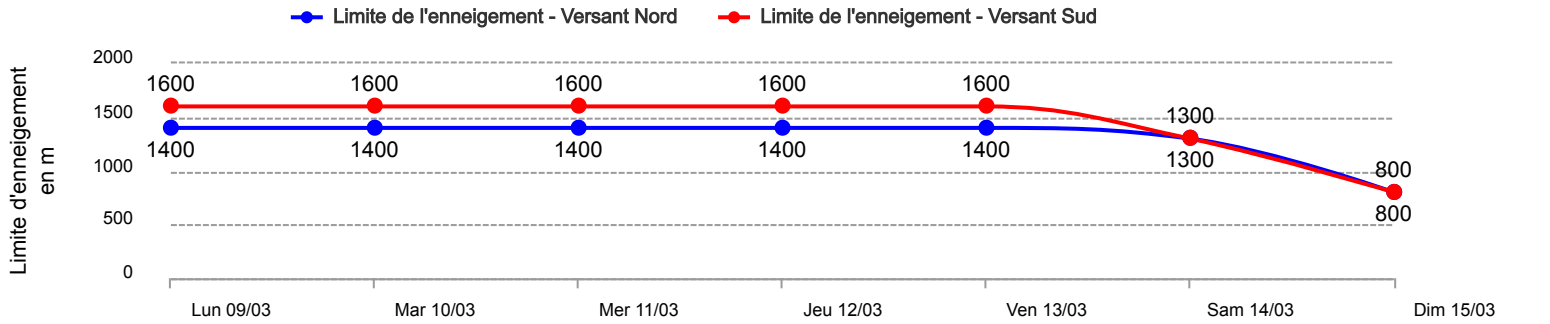

Pour consulter la vigilance en cours, veuillez vous rendre sur le site https://vigilance.meteofrance.fr/fr

Météo-France - 73 avenue de Paris, 94165 Saint-Mandé cedex - Contact : contact@meteo.fr

Rédigé par Météo-France avec la contribution des observateurs du réseau nivo-météorologiques. Partenariat : ANMSM (Maires de Stations de Montagne), DSF (Domaines Skiables de France), ADSP (Directeurs de Pistes et de la Sécurité des Stations de Sports d'Hiver) et autres acteurs de la montagne.

Bulletin neige & avalanches par téléphone au

0 892 68 10 20 Service 0,35 € / min + prix appel