# Bulletin d'estimation du risque d'avalanche

(valable en dehors des pistes balisées et ouvertes)

# MASSIF : Pays-Basque

Rédigé le dimanche 15 mars 2026 à 16h

## Estimation des risques pour le : LUNDI 16 MARS

**CONDITIONS TRES HIVERNALES : CHUTES DE NEIGE VENTEES, FROID.**

3

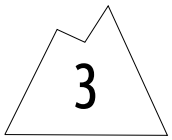


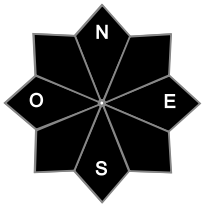


Indice de risque marqué.

**Départs spontanés :** En neige récente et avec les éclaircies.

**Déclenchements provoqués :** Plaques instables dans la neige récente et sous le vent.

Indices de risque : 5 très fort - 4 fort - 3 marqué - 2 limité - 1 faible -- En noir : les pentes les plus dangereuses

## Stabilité du manteau neigeux

**Situation avalancheuse typique :** neige ventée neige humide

**DECLENCHEMENTS PROVOQUES :** risque **marqué** (3).
Déclenchements **faciles par un seul skieur ou randonneur d'avalanches de plaques instables en toutes orientations**, sous le vent de nord. Les **plaques s'épaississent ce dimanche avec le vent de nord fort en altitude**, donnant lieu à des avalanches possibles de **taille 2 à 3 (moyenne 20-50 cm de cassure) à grande (>50 cm) en cas d'accumulations en pente raide (dépots plutôt en large sud à est) ou par emport du manteau jusqu'au sol en secteurs sud.**

**DEPARTS SPONTANES :** risque modéré à marqué avec les éclaircies lundi en **pentes raides en large sud**.
**Départs ponctuels en général de neige humide avec les éclaircies**, provoquant des **avalanches petites à quelquefois moyennes** au cours de la matinée. Des avalanches **moyennes plus fréquentes** en après-midi parfois sous forme de cassures linéaires. plus rarement de **grandes avalanches possibles** sous le vent en pentes **sud à sud-est sur le haut du massif.**

## Qualité de la neige

**Enneigement** : L'enneigement est correct pour la saison, surtout au-dessus de 1800 m, mais reste assez maigre en versants exposés au vent d'Ouest et en versants Sud. Couche de 30 à 40 cm vers 1800 m en versants sud au lever du jour.
**Limites skiables** : A basse altitude, dès 1400 m ce lundi matin, mais sans sous-couche en-dessous de 1600 m en versants froids, 1900 m en versants Sud.
**État de la neige** : Fine croûte possible non portante en fin de nuit. Neige plus ou moins travaillée par le vent de nord ce dimanche, frittée à cartonnée près des crêtes, cols et sommets, restant meuble à l'abri du vent (clairières et combes déventées notamment). Neige rapidement molle et s'humidifiant sous les éclaircies en journée.

## Aperçu météo pour le lundi 16 mars

| nuit | matin | après-midi | soir |
|---|---|---|---|
| | | | |

Soleil en matinée lundi, des cumulus en journée et une mer de nuages en après-midi sous 1800 m, se dissipant en soirée.

| Pluie-Neige | | | | |
|---|---|---|---|---|
| Iso 0 °C | 1 900 m | 2 800 m | 3 000 m | 3 200 m |
| Vent 1000 m | ↙ 20 km/h | ↓ 20 km/h | ↙ 20 km/h | ↙ 10 km/h |
| Vent 2000 m | ↓ 50 km/h | ↙ 35 km/h | ↙ 30 km/h | ← 20 km/h |

## Épaisseur de neige hors-piste

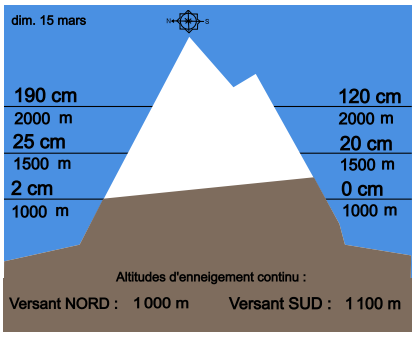


## Précipitations à 1800 m

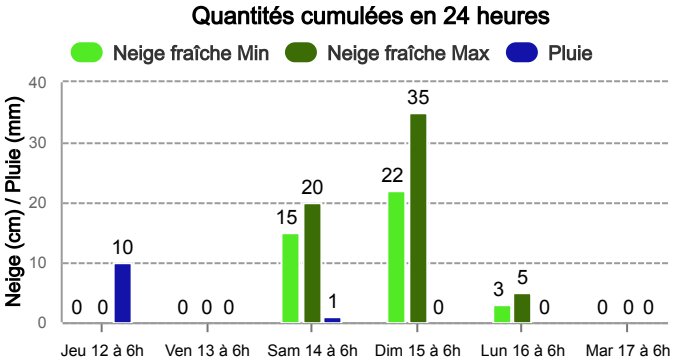


## Tendance du mardi 17 mars

**Indice de risque limité**

Humidification, les plaques deviennent plus rares et plus difficilement déclenchables. Avalanches de neige humide plus généralisées.

Pour consulter la vigilance en cours, veuillez vous rendre sur le site https://vigilance.meteofrance.fr/fr

Météo-France - 73 avenue de Paris, 94165 Saint-Mandé cedex - Contact : contact@meteo.fr

Rédigé par Météo-France avec la contribution des observateurs du réseau nivo-météorologiques. Partenariat : ANMSM (Maires de Stations de Montagne), DSF (Domaines Skiables de France), ADSP (Directeurs de Pistes et de la Sécurité des Stations de Sports d'Hiver) et autres acteurs de la montagne.

Bulletin neige & avalanches par téléphone au **0 892 68 10 20** Service 0,35 € / min + prix appel

RÉPUBLIQUE FRANÇAISE
*Liberté Égalité Fraternité*

METEO FRANCE
À VOS CÔTÉS, DANS UN CLIMAT QUI CHANGE

# Bulletin d'estimation du risque d'avalanche

## (valable en dehors des pistes balisées et ouvertes)

# MASSIF : Pays-Basque

Rédigé le dimanche 15 mars 2026 à 16h

## Conditions nivo-météo des 7 derniers jours

| | lun. 09/03 | | | | mar. 10/03 | | | | mer. 11/03 | | | | jeu. 12/03 | | | | ven. 13/03 | | | | sam. 14/03 | | | | dim. 15/03 | | | |
|---|---|---|---|---|---|---|---|---|---|---|---|---|---|---|---|---|---|---|---|---|---|---|---|---|---|---|---|---|
| | 03h | 09h | 15h | 21h | 03h | 09h | 15h | 21h | 03h | 09h | 15h | 21h | 03h | 09h | 15h | 21h | 03h | 09h | 15h | 21h | 03h | 09h | 15h | 21h | 03h | 09h | 15h | 21h |
| Météo | | | | | | | | | | | | | | | | | | | | | | | | | | | | |
| Vent (km/h) | 25 | 25 | 20 | 20 | 15 | 15 | 30 | 60 | 50 | 45 | 60 | 50 | 30 | 35 | 20 | 20 | 30 | 60 | 55 | 55 | 65 | 60 | 55 | 70 | 70 | 75 | 65 | 50 |
| à 2000m | | | | | | | | | | | | | | | | | | | | | | | | | | | | |
| Vent (km/h) | 10 | 10 | 5 | 5 | 10 | 10 | 15 | 10 | 15 | 10 | 20 | 15 | 10 | 15 | 5 | 5 | 15 | 20 | 20 | 15 | 25 | 20 | 20 | 35 | 40 | 50 | 35 | 20 |
| à 1000m | | | | | | | | | | | | | | | | | | | | | | | | | | | | |

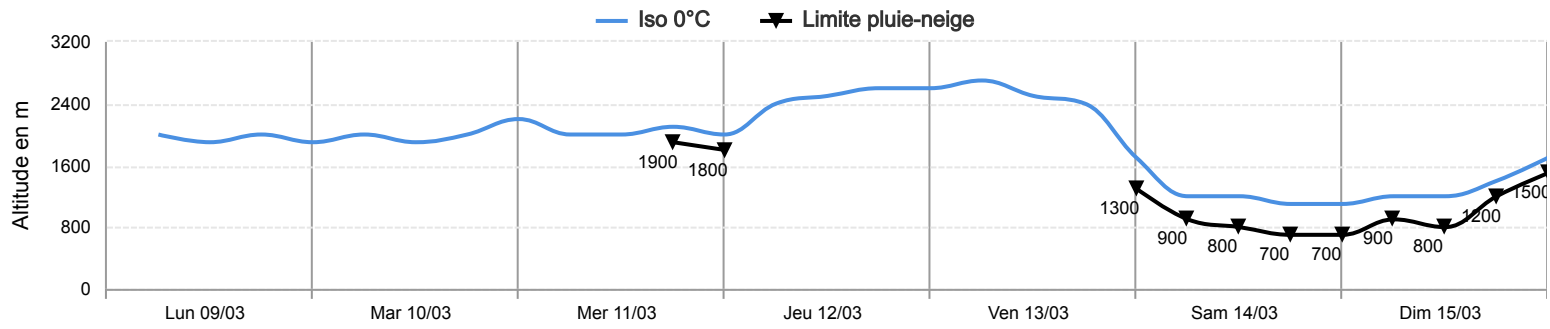


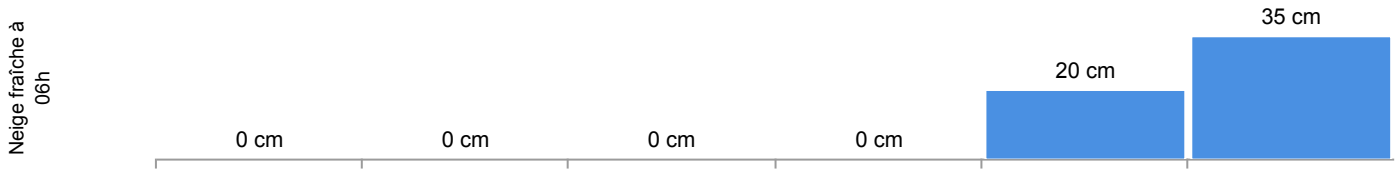


| Risque d'avalanche | lun. 09/03 | mar. 10/03 | mer. 11/03 | jeu. 12/03 | ven. 13/03 | sam. 14/03 | dim. 15/03 |
|---|---|---|---|---|---|---|---|
| | 2 | 2 | 2 | 2 | 1 | 3 | 3 |

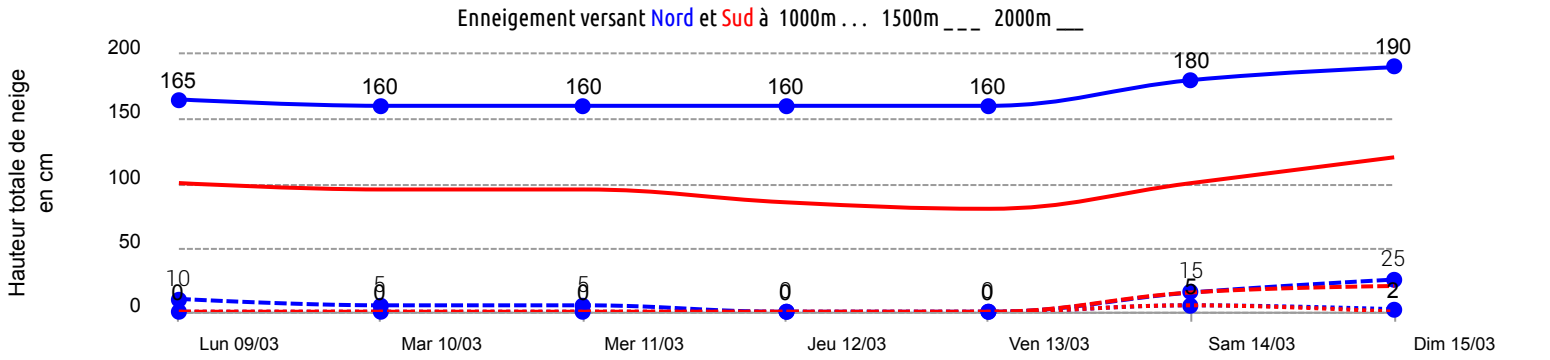


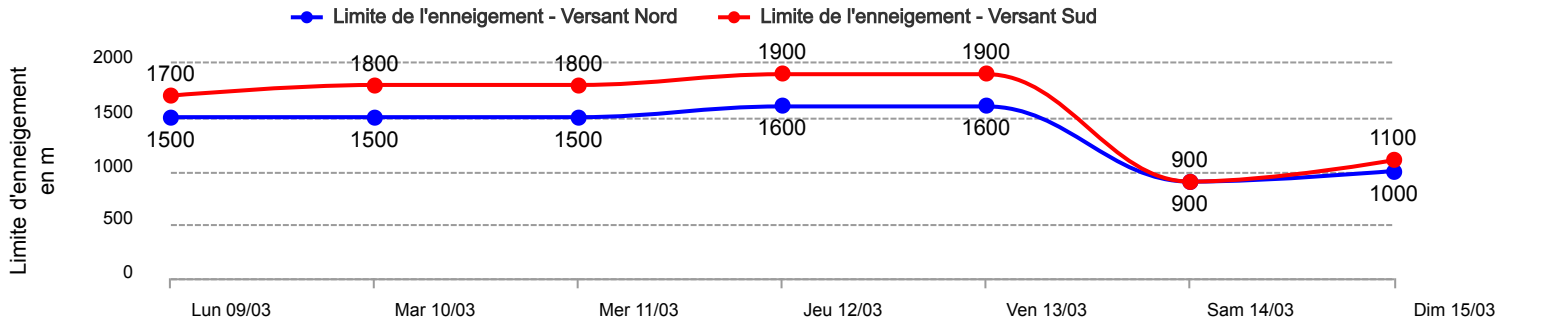


Pour consulter la vigilance en cours, veuillez vous rendre sur le site https://vigilance.meteofrance.fr/fr


**Météo-France - 73 avenue de Paris, 94165 Saint-Mandé cedex - Contact : contact@meteo.fr**



Rédigé par Météo-France avec la contribution des observateurs du réseau nivo-météorologiques. Partenariat : ANMSM (Maires de Stations de Montagne), DSF (Domaines Skiables de France), ADSP (Directeurs de Pistes et de la Sécurité des Stations de Sports d'Hiver) et autres acteurs de la montagne.



Bulletin neige & avalanches par téléphone au
0 892 68 10 20 Service 0,35 € / min + prix appel