Bulletin d'estimation du risque d'avalanche
(valable en dehors des pistes balisées et ouvertes)

MASSIF : Pelvoux

Rédigé le dimanche 15 mars 2026 à 16h

Estimation des risques pour le : LUNDI 16 MARS

INSTABILITÉS EN ALTITUDE DANS LA NEIGE RÉCENTE VENTÉE

3

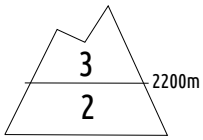

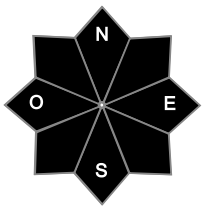

Au-dessus de 2200m indice de risque marqué, plus bas indice limité.

Départs spontanés : sous l'effet du vent à haute altitude, et en neige humide au soleil

Déclenchements provoqués : instabilités encore facilement déclenchables en altitude

Indices de risque : 5 très fort - 4 fort - 3 marqué - 2 limité - 1 faible -- En noir : les pentes les plus dangereuses

Stabilité du manteau neigeux

Situation avalancheuse typique : neige ventée

Déclenchements provoqués : instabilités encore fréquentes au-dessus de 2200 m environ. Possibles en toute orientation dans les zones d'accumulation par le vent, même loin des crêtes, elles sont facilement déclenchables par un seul skieur. Elles se présentent sous forme de plaques parfois d'aspect poudreux et difficilement identifiables et génèrent des avalanches de taille petite (taille 1) à moyenne (taille 2). Ces instabilités se sont formées suite à l'action du vent sur la couche de neige récente tombée légère. Sous 2200 m, les instabilités, également déclenchables par un seul skieur, sont moins nombreuses et restent superficielles et peu volumineuses (taille 1).

Départs spontanés : rares en plaques à vent, de taille petite à moyenne, dans les zones d'accumulation par le vent près des crêtes de haute altitude. Départs ponctuels de neige récente humide sous les éclaircies en journée, taille 1.

Qualité de la neige

L'enneigement est proche des normales pour une mi-mars.
Hauteurs de neige observées : 318 cm à la Nivôse des Écrins vers 3000 m, 218 cm au Pré de Mme Carle à 1900 m, 105 cm au hameau de Dormillouse à 1730 m.

Limite d'enneigement skiable : vers 1400 m en ubacs, 1700/1800 m en adrets pas trop raides.

État de la neige de surface : neige récente (15/30 cm) souvent densifiée par le vent en altitude et déjà alourdie sous 2200 m En journée, nette humidification au soleil jusqu'à haute altitude en adrets abrités du vent.

Aperçu météo pour le lundi 16 mars

nuit	matin	après-midi	soir

Ensoleillé, net redoux. Vent de secteur nord modéré à assez fort sur les crêtes.

Pluie-Neige				
Iso 0 °C	2 000 m	2 700 m	2 800 m	2 600 m
Vent 2000 m	↓ 10 km/h	↓ 25 km/h	↓ 30 km/h	↘ 25 km/h
Vent 3000 m	↓ 30 km/h	↘ 35 km/h	↘ 35 km/h	↘ 30 km/h

Épaisseur de neige hors-piste

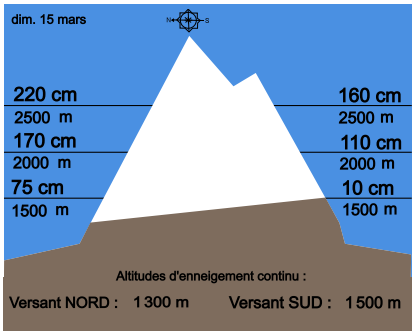

Précipitations à 1800 m

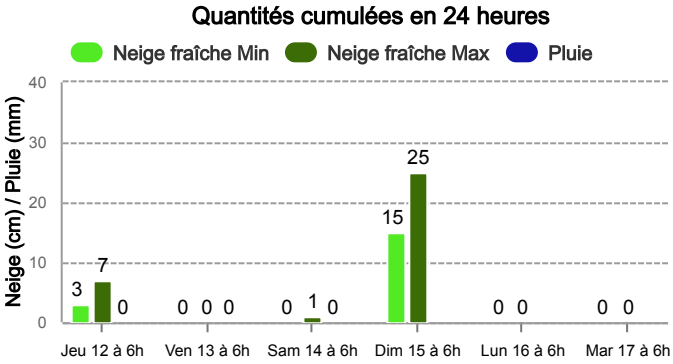

Tendance du mardi 17 mars

2

Indice de risque limité

Poursuite de la stabilisation du manteau neigeux. Risque limité.

Pour consulter la vigilance en cours, veuillez vous rendre sur le site https://vigilance.meteofrance.fr/fr

Météo-France - 73 avenue de Paris, 94165 Saint-Mandé cedex - Contact : contact@meteo.fr

Rédigé par Météo-France avec la contribution des observateurs du réseau nivo-météorologiques. Partenariat : ANMSM (Maires de Stations de Montagne), DSF (Domaines Skiables de France), ADSP (Directeurs de Pistes et de la Sécurité des Stations de Sports d'Hiver) et autres acteurs de la montagne.

Bulletin neige & avalanches par téléphone au
0 892 68 10 20 Service 0,35 € / min + prix appel

RÉPUBLIQUE FRANÇAISE
Liberté Égalité Fraternité

METEO FRANCE
À VOS CÔTÉS, DANS UN CLIMAT QUI CHANGE

Bulletin d'estimation du risque d'avalanche

(valable en dehors des pistes balisées et ouvertes)

MASSIF : Pelvoux

Rédigé le dimanche 15 mars 2026 à 16h

Conditions nivo-météo des 7 derniers jours

	lun. 09/03				mar. 10/03				mer. 11/03				jeu. 12/03				ven. 13/03				sam. 14/03				dim. 15/03			
	03h	09h	15h	21h	03h	09h	15h	21h	03h	09h	15h	21h	03h	09h	15h	21h	03h	09h	15h	21h	03h	09h	15h	21h	03h	09h	15h	21h
Météo																												
Vent (km/h)	20	20	25	30	20	25	20	15	15	20	30	35	35	25	20	10	10	15	20	20	45	10	5	15	30	35	20	5
à 3000m																												
Vent (km/h)	5	15	15	15	10	10	15	5	5	10	20	10	15	20	15	5	5	5	15	15	15	0	0	5	10	15	5	0
à 2000m																												

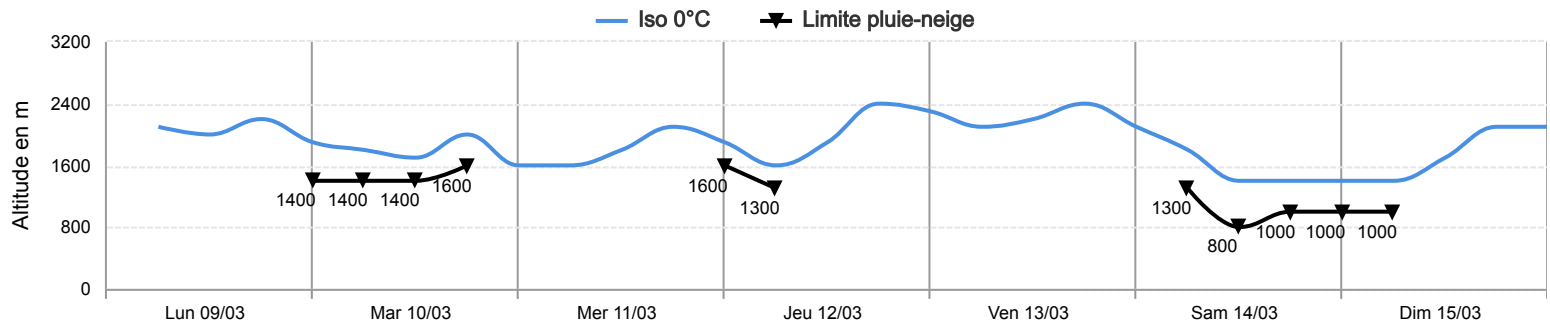

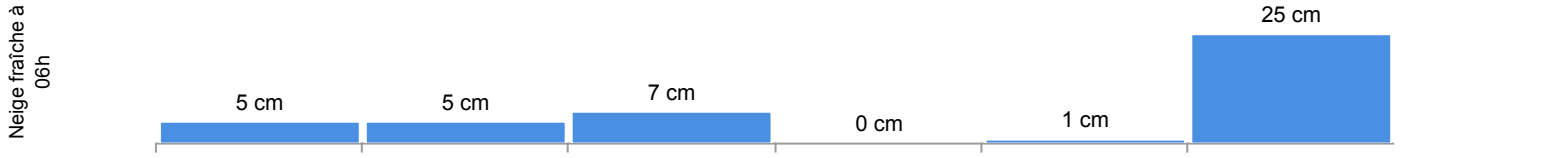

Risque d'avalanche	lun. 09/03	mar. 10/03	mer. 11/03	jeu. 12/03	ven. 13/03	sam. 14/03	dim. 15/03
	2	2	2	2	2	3	3

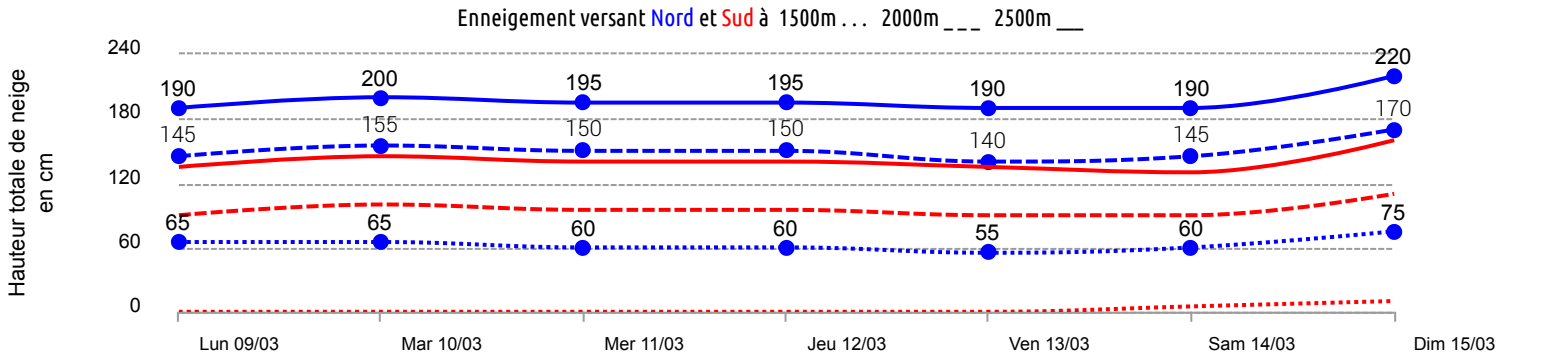

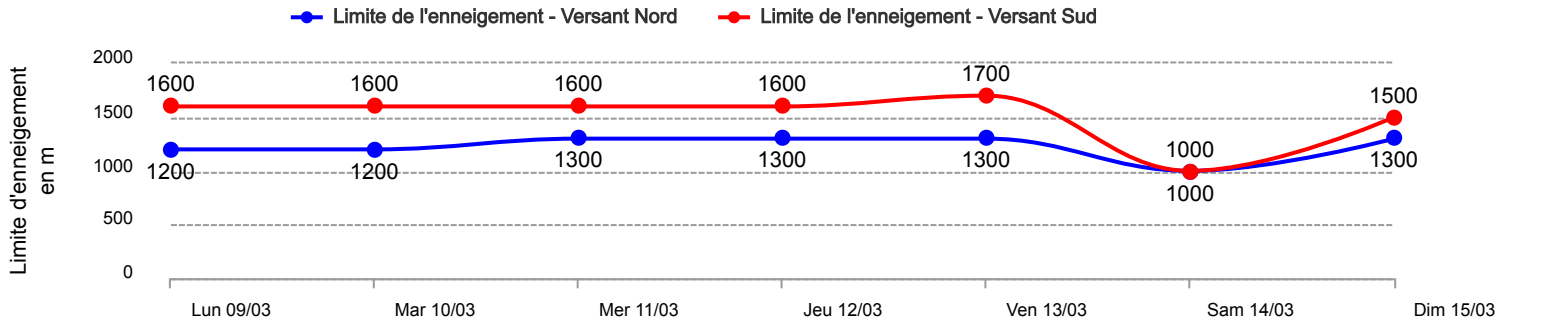

Pour consulter la vigilance en cours, veuillez vous rendre sur le site https://vigilance.meteofrance.fr/fr

Météo-France - 73 avenue de Paris, 94165 Saint-Mandé cedex - Contact : contact@meteo.fr

Rédigé par Météo-France avec la contribution des observateurs du réseau nivo-météorologiques. Partenariat : ANMSM (Maires de Stations de Montagne), DSF (Domaines Skiables de France), ADSP (Directeurs de Pistes et de la Sécurité des Stations de Sports d'Hiver) et autres acteurs de la montagne.

Bulletin neige & avalanches par téléphone au
0 892 68 10 20 Service 0,35 € / min + prix appel