Bulletin d'estimation du risque d'avalanche
(valable en dehors des pistes balisées et ouvertes)

MASSIF : Vanoise

Rédigé le dimanche 15 mars 2026 à 16h

Estimation des risques pour le : LUNDI 16 MARS

MANTEAU NEIGEUX ENCORE INSTABLE SUITE A LA RÉCENTE CHUTE DE NEIGE.

3

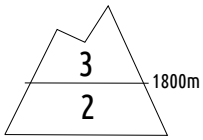

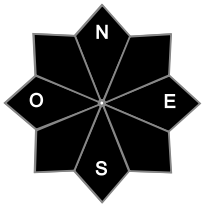

Au-dessus de 1800m indice de risque marqué, plus bas indice limité.

Départs spontanés : quelques départs en neige humide dans les versants ensoleillés.

Déclenchements provoqués : quelques plaques faciles à déclencher.

Indices de risque : 5 très fort - 4 fort - 3 marqué - 2 limité - 1 faible -- En noir : les pentes les plus dangereuses

Stabilité du manteau neigeux

Situation avalancheuse typique : neige fraîche neige humide

Déclenchements provoqués : encore **quelques plaques faciles à déclencher dans la neige récente, en tous versants mais plutôt au-dessus de 1800/2200 m selon l'orientation**. Ces plaques, d'**aspect généralement poudreux**, sont plus **fréquentes près des crêtes** où le vent a localement soufflé (la neige est alors ferme sous les skis). **Cassures généralement 20-50 cm**, avalanches de **taille moyenne**. **Facteur aggravant :** la dernière chute de neige s'est localement déposée sur une fine couche de grains anguleux, ce qui rend les plaques particulièrement réactives dans les versants ombragés : un déclenchement à distance est alors possible.

Départs spontanés : quelques départs ponctuels en neige humide dans les versants ensoleillés (est, sud puis ouest au fil de la journée). En particulier, les couloirs raides "se purgent". Petites à moyennes avalanches.

Qualité de la neige

Enneigement : globalement très bon pour la saison.

Limite skiable : encore skiable dès 1100/1200 m dans les prairies orientées nord, plutôt 1500/1600 m en sud pas trop raide.

Qualité de la neige :
- en versants ombragés, crouté sous 1600/1800 m puis couche de neige fraîche légère de plus en plus conséquente avec l'altitude (20/30 cm vers 2500 m), parfois redistribuée ou densifiée par le vent (risque de plaque!). Épaisseur de neige meuble parfois importante en altitude.
- en versants ensoleillés, neige encore froide en altitude à l'aube (mais déjà finement croutée et désagréable aux basses altitudes). En journée, humidification et bottage jusqu'à haute altitude.

Aperçu météo pour le lundi 16 mars

nuit	matin	après-midi	soir

Quelques écharpes nuageuses le matin voire une mer de nuages localisée, sous 2000/2500 m, puis du très beau temps.

Pluie-Neige				
Iso 0 °C	1 700 m	1 900 m	2 000 m	2 000 m
Vent 2500 m	↘ 10 km/h	↘ 20 km/h	↘ 25 km/h	↘ 20 km/h
Vent 3500 m	↓ 30 km/h	↘ 40 km/h	↓ 40 km/h	↓ 30 km/h

Épaisseur de neige hors-piste

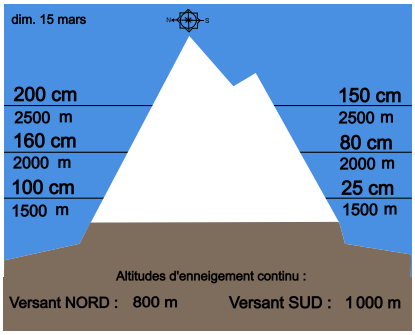

Précipitations à 1800 m

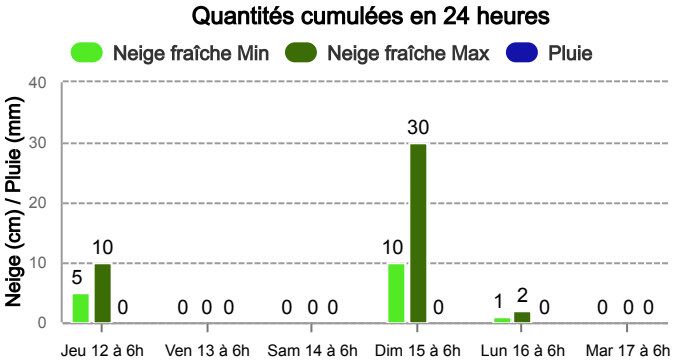

Tendance du mardi 17 mars

Indice de risque limité

La neige récente se stabilise rapidement avec le retour du temps calme. Le risque est "limité".

Pour consulter la vigilance en cours, veuillez vous rendre sur le site https://vigilance.meteofrance.fr/fr

Météo-France - 73 avenue de Paris, 94165 Saint-Mandé cedex - Contact : contact@meteo.fr

Rédigé par Météo-France avec la contribution des observateurs du réseau nivo-météorologiques. Partenariat : ANMSM (Maires de Stations de Montagne), DSF (Domaines Skiables de France), ADSP (Directeurs de Pistes et de la Sécurité des Stations de Sports d'Hiver) et autres acteurs de la montagne.

Bulletin neige & avalanches par téléphone au
0 892 68 10 20 Service 0,35 € / min + prix appel

RÉPUBLIQUE FRANÇAISE
Liberté Égalité Fraternité

METEO FRANCE
À VOS CÔTÉS, DANS UN CLIMAT QUI CHANGE

Bulletin d'estimation du risque d'avalanche
(valable en dehors des pistes balisées et ouvertes)

MASSIF : Vanoise

Rédigé le dimanche 15 mars 2026 à 16h

Conditions nivo-météo des 7 derniers jours

	lun. 09/03				mar. 10/03				mer. 11/03				jeu. 12/03				ven. 13/03				sam. 14/03				dim. 15/03			
	03h	09h	15h	21h	03h	09h	15h	21h	03h	09h	15h	21h	03h	09h	15h	21h	03h	09h	15h	21h	03h	09h	15h	21h	03h	09h	15h	21h
Météo																												
Vent (km/h)	20	30	30	30	35	40	40	30	20	25	35	50	45	30	30	25	20	25	35	65	50	15	35	40	30	40	20	15
à 3500m																												
Vent (km/h)	10	15	30	40	30	20	20	20	10	10	25	40	30	15	15	10	10	15	20	40	30	5	20	25	15	25	10	5
à 2500m																												

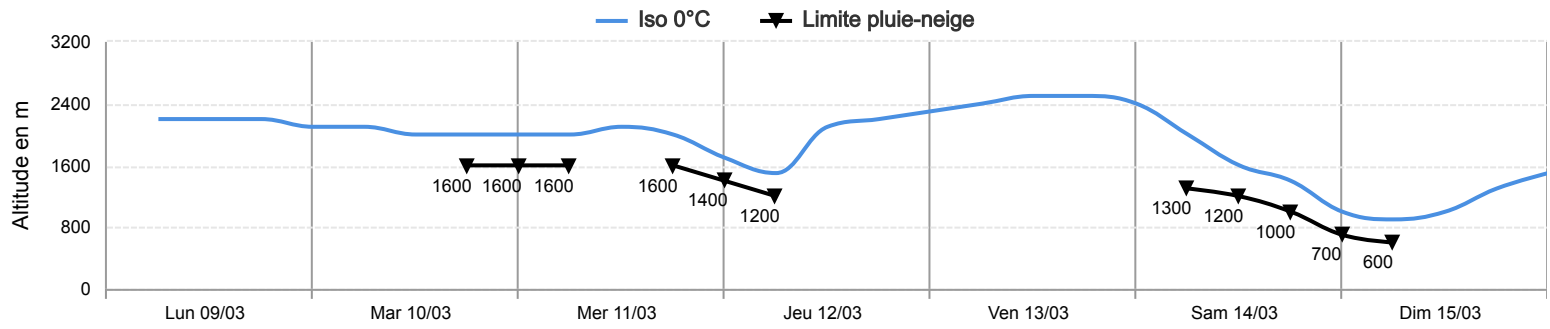

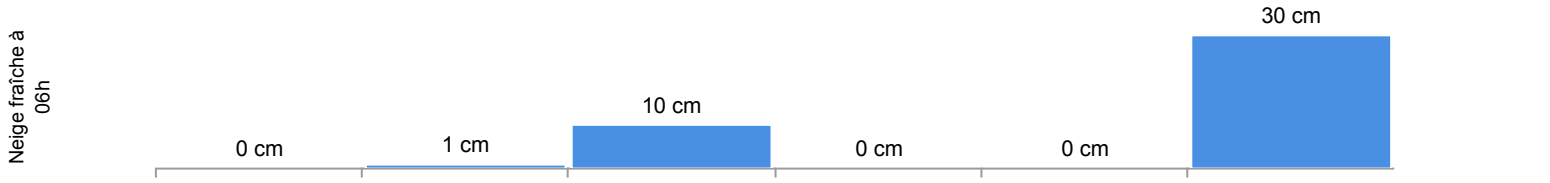

Risque d'avalanche	lun. 09/03	mar. 10/03	mer. 11/03	jeu. 12/03	ven. 13/03	sam. 14/03	dim. 15/03
	2	2	2	2	2	3	3

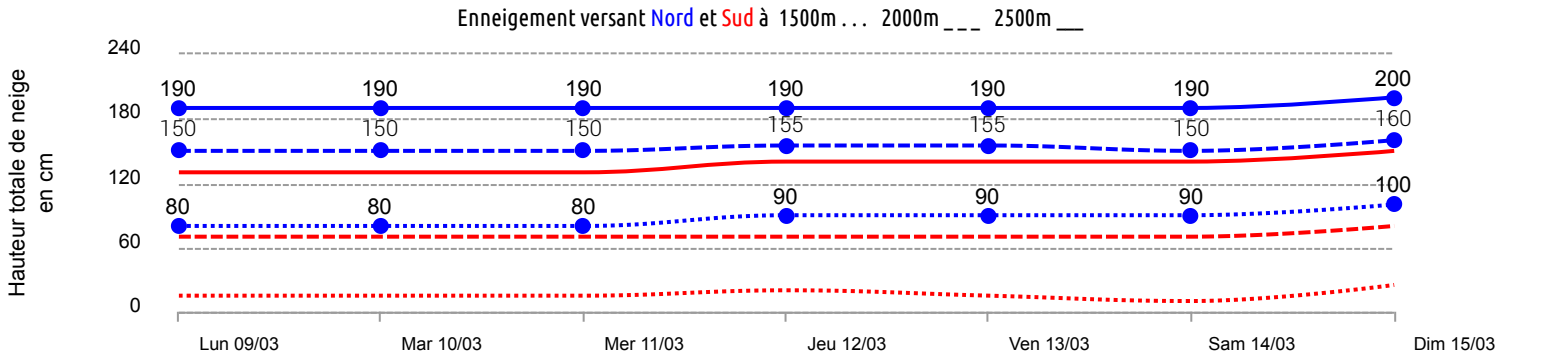

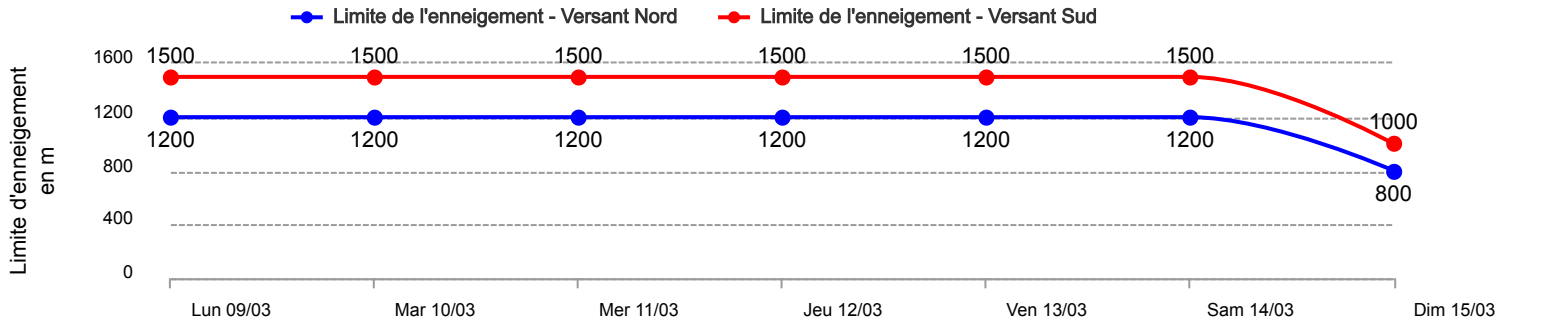

Pour consulter la vigilance en cours, veuillez vous rendre sur le site https://vigilance.meteofrance.fr/fr

Météo-France - 73 avenue de Paris, 94165 Saint-Mandé cedex - Contact : contact@meteo.fr

Rédigé par Météo-France avec la contribution des observateurs du réseau nivo-météorologiques. Partenariat : ANMSM (Maires de Stations de Montagne), DSF (Domaines Skiables de France), ADSP (Directeurs de Pistes et de la Sécurité des Stations de Sports d'Hiver) et autres acteurs de la montagne.

Bulletin neige & avalanches par téléphone au
0 892 68 10 20 Service 0,35 € / min + prix appel