GOBIERNO DE ESPAÑA
VICEPRESIDENCIA TERCERA DEL GOBIERNO
MINISTERIO PARA LA TRANSICIÓN ECOLÓGICA Y EL RETO DEMOGRÁFICO

Boletín de información nivológica y de peligro de aludes

Pirineo Navarro y Aragonés

aemet Agencia Estatal de Meteorología

lunes, 16 de marzo de 2026

Pronóstico hasta las 24 horas del martes, día 17 de marzo

(Válido fuera de pistas de esquí balizadas y abiertas)

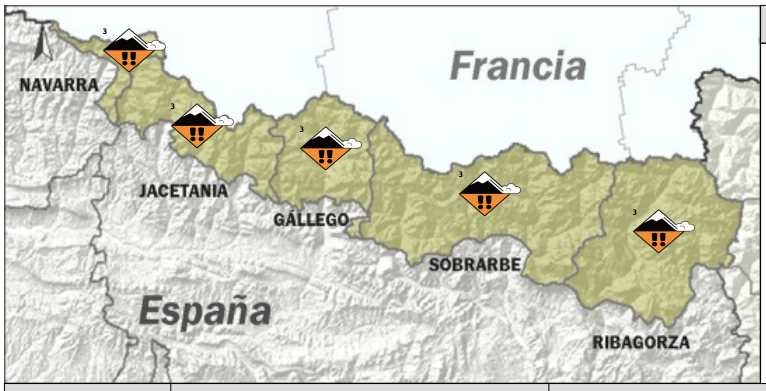

Problemas de aludes

Nieve húmeda

Placas de viento

Macizo	Peligro	Problemas de aludes, cota, orientación, tamaño	Innivación observada (m)
Navarra	3 Notable	Nieve húmeda: 2 — N, O, E, S Placas de viento: 3 — 2100 — N, O, E, S	2026-03-16 N S Cotas bajas
Jacetania	3 Notable	Nieve húmeda: 2 — N, O, E, S Placas de viento: 3 — 2100 — N, O, E, S	2026-03-16 N S Cotas bajas
Gállego	3 Notable	Nieve húmeda: 2 — N, O, E, S Placas de viento: 3 — 2100 — N, O, E, S	2026-03-16 N S Cotas bajas

AEMET. Se autoriza la reproducción de su contenido citando la fuente.

Boletín de información nivológica y de peligro de aludes

Pirineo Navarro y Aragonés

Sobrarbe	3 **Notable**	**Nieve húmeda**  **Placas de viento** 	2026-03-16 Cotas bajas
Ribagorza	3 **Notable**	**Nieve húmeda**  **Placas de viento** 	2026-03-16 Cotas bajas

Estado del manto y observaciones recientes

Este fin de semana las nevadas han dejado depósitos de 20-30 cm de nieve nueva con temperaturas bajas. Tras remitir el domingo por la mañana, continuaron soplando vientos fuertes o muy fuertes de componente norte, incluso con algunas rachas huracanadas, que produjeron importantes ventiscas y han redistribuido intensamente la nieve reciente hasta la madrugada de hoy, sobre todo en la alta montaña.

El manto comienza en cotas bajas, con espesores que rondan los 10-20 cm a 1300-1500 metros, y que se van incrementando a medida que ascendemos, estando por encima de lo que cabría esperar a estas alturas de la temporada en medianías y cotas altas. A unos 1800 metros se alcanzan los 80-150 cm y a 2100 metros los 120-210 cm, aún más en ventisqueros, hoyas y otras zonas propensas a la acumulación.

La superficie del manto con exposición al viento del norte está muy erosionada, y afloran las capas de costra y nieve vieja de días anteriores. Destacan las acumulaciones de nieve en orientaciones este, sur y oeste a sotavento, donde se han formado las placas de viento más gruesas, aunque existen también en las norte. El manto comenzará a humedecerse con la insolación del día de hoy, desactivando progresivamente las placas de viento en solanas. Las umbrías de cotas altas permanecerán más frías y secas, con estratos de granos facetados enterrados, así como algunas capas débiles persistentes a mayor profundidad generalmente inactivas.

En las últimas 24 horas se han observado dos aludes naturales de placa en orientaciones norte, uno mediano en cotas medias y otro grande en cotas altas.

AEMET. Se autoriza la reproducción de su contenido citando la fuente.

Evolución del manto y peligro de aludes para el martes, día 17

Problema de nieve húmeda. Problema de placas de viento y capas débiles persistentes en cotas altas.

En las laderas solanas y en las umbrías bajo 2200 metros continuará la humidificación con el ascenso de las temperaturas y la insolación, lo que agravará el problema de nieve húmeda y disminuirá el de placas de viento. En éstas serán pues probables las purgas o aludes medianos (capaz de enterrar a una persona) de nieve húmeda, sobre todo a partir de mediodía tras la fusión del rehielo nocturno. Tampoco se descartan algunos deslizamientos basales en las áreas herbosas o de roca lisa.

En zonas de acumulación de las umbrías por encima de 2100 metros y en algunas solanas de cotas muy altas se podrán mantener inestables las placas de viento, que además descansan sobre nieve reciente y en umbrías sobre capas débiles de facetas formadas la semana pasada. Ante una sobrecarga débil (paso de un esquiador) u ocasionalmente de manera natural podrán desencadenarse y provocar aludes de tamaño mediano o incluso grande (capaz de enterrar un coche), especialmente si se activan capas débiles persistentes más profundas, generalmente ubicadas en umbrías por encima de unos 2300 metros.

Predicción meteorológica para el martes, día 17

Poco nuboso o despejado. No se esperan precipitaciones. Temperaturas en ascenso, localmente notable. Heladas débiles en cotas altas. Viento inicialmente moderado de componente norte, tendiendo a flojo de dirección variable por la mañana.

Datos en la atmósfera libre:

Altitud de la isoterma de 0 ºC: 3300 m
Altitud de la isoterma de -10 ºC: 4700 m

Viento a 1500 m: VRB 5 km/h
Viento a 3000 m: N 20 km/h

Evolución para el miércoles día 18

Nivel de peligro estacionario.

(Información elaborada a partir de los datos recibidos de los refugios de Linza, Lizara, Panticosa, Bachimaña, Góriz, Pineta, Estós, Angel Orús, La Renclusa y Belagua, de las estaciones de esquí de Astún y Formigal y de Ordesa Pradera)

Escala europea de peligro de aludes

Débil | Limitado | Notable | Fuerte | Muy Fuerte

Problemas de aludes

Nieve reciente | Placas de viento | Capas débiles persistentes | Nieve húmeda | Deslizamientos basales | Sin problema evidente

Nota1: Se recuerda que, siempre que haya nieve, la ausencia total de peligro no existe. Hay que tener presente que en circunstancias desfavorables, con aludes de tamaño 1 (alud pequeño o colada) y tamaño 2 (alud mediano), se pueden sufrir severos daños personales.

Nota2: Los BPA se elaboran en base a información meteorológica así como al estado del manto nivoso a través de sondeos puntuales. Se advierte a los usuarios de la variabilidad de esta información al extrapolarla a zonas extensas de montaña. Por ello, AEMET no se hace responsable de su uso para la toma de decisiones que conciernen a la seguridad personal, ni de los riesgos físicos o materiales de ellas derivadas.

AEMET. Se autoriza la reproducción de su contenido citando la fuente.