ICGC Institut Cartogràfic i Geològic de Catalunya

Servei Meteorològic de Catalunya meteo.cat

Boletín de peligro de aludes para el Pirineo de Catalunya
Del 16/03/2026 al 17/03/2026

(Válido fuera pistas de esquí y zonas no controladas)

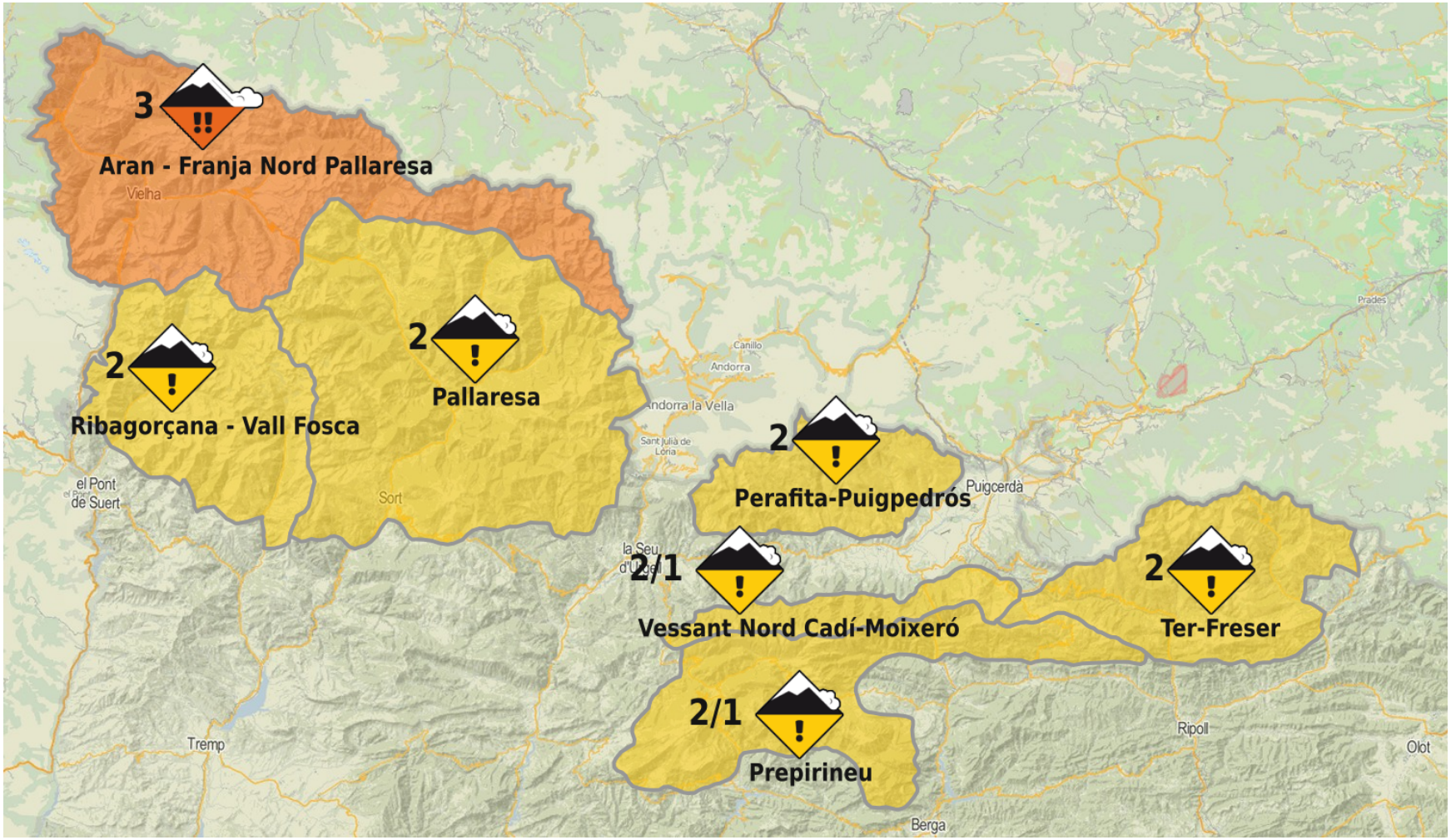

5 MUY FUERTE	4 FUERTE	3 NOTABLE	2 LIMITADO	1 DÉBIL

ICGC Institut Cartogràfic i Geològic de Catalunya

Servei Meteorològic de Catalunya

Boletín de peligro de aludes Aran - Franja Nord Pallaresa Del 16/03/2026 al 17/03/2026

(Válido fuera pistas de esquí y zonas no controladas)

Notable (3)

Situación primaria

Capas débiles persistentes

Distribución

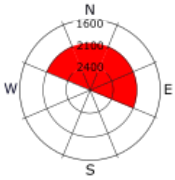

Tamaño

Origen

Tendencia

Situación secundaria

Nieve venteada

Distribución

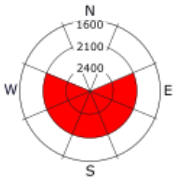

Tamaño

Origen

Tendencia

Estado del manto nivoso

El viento de los últimos días ha formado nuevas placas de viento. Con el enfriamiento nocturno también aumentan las capas débiles que dan propagaciones y también hay nieve granulada enterrada del fin de semana. Hay que prestar atención ya que podemos desencadenar fácilmente placas (nieve venteada y capas débiles) especialmente por encima de los 2100 m en cualquier orientación. Las placas de viento y los desencadenamientos por capas débiles persistentes pueden dar lugar a aludes de tamaño mediano, capacidad de enterrarnos, o incluso de tamaño suficiente para enterrar un grupo, sobre todo en las laderas umbrías protegidas del viento y bajo collados y crestas de las solanas. Con el aumento de la temperatura y la radiación solar, son probables aludes de nieve húmeda, incluso de tamaño mediano, sobre todo por debajo de los 2400-2500 m en las solanas pero también por debajo de los 2100 m en las umbrías.

Distribución del manto nivoso

Hay nieve por encima de unos 1.400-1-500 ma umbrías y 1.700 ma solanas. Los espesores a unos 2.200 m son superiores a los normales en la Franja Norte de la Pallaresa y en la mitad sur del Aran donde rondan los 180-220 cm. En la mitad norte de Arán hay unos 120-140 cm de grosor total.

Tendencia para las próximas 48-72h

El enfriamiento nocturno mantendrá activas las capas débiles. Evolución del peligro: ESTACIONARIO

El próximo boletín será emitido el día 2026-03-17

5 MUY FUERTE	4 FUERTE	3 NOTABLE	2 LIMITADO	1 DÉBIL

EAWS EUROPEAN AVALANCHE WARNING SERVICES

ICGC Institut Cartogràfic i Geològic de Catalunya

Servei Meteorològic de Catalunya

Boletín de peligro de aludes Ribagorçana - Vall Fosca Del 16/03/2026 al 17/03/2026

(Válido fuera pistas de esquí y zonas no controladas)

Limitado (2)

Situación primaria

Nieve húmeda

Distribución

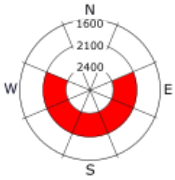

Tamaño

Origen

Tendencia

Situación secundaria

Nieve venteada

Distribución

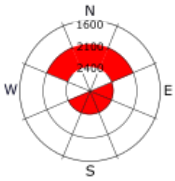

Tamaño

Origen

Tendencia

Estado del manto nivoso

El manto se erosionó por el viento, especialmente de cotas altas en umbrías donde aflora la costra marrón. El aumento térmico y la insolación de marzo transforman la nieve. Pueden caer aludes de fusión naturales por debajo de los 2500 m. No tendrán tamaño para enterrarnos, excepto en el extremo norte de la zona donde las nevadas dejaron mayor grosor. Cabe evitar terreno trampa y sobreacumulaciones en horas centrales del día y mientras no rehiele. Las orientaciones más proclives son las que van de E hacia W. El terreno proclive a aludes de fusión son las salidas de puntos oscuros (rocas y árboles). Durante la noche y madrugada la nieve rehelará donde se haya transformado durante el día. Se mantienen placas de viento que pueden caer a nuestro paso bajo collados y cordales por encima de 2500 m en orientaciones que van de E hacia S y en umbrías resguardadas N, NE y NW entre 2200-2400 m. Las placas tendrán capacidad de colgarnos, en el extremo norte del sector por las acumulaciones.

Distribución del manto nivoso

Hay nieve en el suelo a 1.600 m en terreno umbrío, y por encima de unos 1.800 m en laderas soleadas. El manto es esquiable por encima de unos 1.800-1.900 ma umbrías. Los grosores alcanzan los 105-135 cm a unos 2.200 m. Estos valores son superiores a los normales para la época.

Tendencia para las próximas 48-72h

Posible formación de capas débiles persistentes en umbrías donde se conserve nieve acumulada de la última nevada. Peligro: SIN CAMBIOS

El próximo boletín será emitido el día 2026-03-17

5 MUY FUERTE	4 FUERTE	3 NOTABLE	2 LIMITADO	1 DÉBIL

EAWS EUROPEAN AVALANCHE WARNING SERVICES

ICGC Institut Cartogràfic i Geològic de Catalunya

Servei Meteorològic de Catalunya

Boletín de peligro de aludes Pallaresa
Del 16/03/2026 al 17/03/2026

(Válido fuera pistas de esquí y zonas no controladas)

Limitado (2)

Situación primaria

Nieve húmeda

Distribución

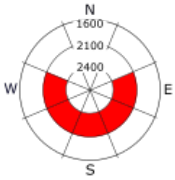

Tamaño

Origen

Tendencia

Situación secundaria

Nieve venteada

Distribución

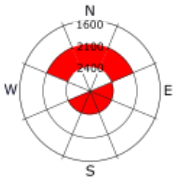

Tamaño

Origen

Tendencia

Estado del manto nivoso

El manto se erosionó por el viento, especialmente de cotas altas en umbrías donde aflora la costra marrón. El aumento térmico y la insolación de marzo transforman la nieve. Pueden caer aludes de fusión naturales por debajo de los 2500 m. No tendrán tamaño para enterrarnos, excepto en el extremo norte de la zona donde las nevadas dejaron mayor grosor. Cabe evitar terreno trampa y sobreacumulaciones en horas centrales del día y mientras no rehiele. Las orientaciones más proclives son las que van de E hacia W. El terreno proclive a aludes de fusión son las salidas de puntos oscuros (rocas y árboles). Durante la noche y madrugada la nieve rehelará donde se haya transformado durante el día. Se mantienen placas de viento que pueden caer a nuestro paso bajo collados y cordales por encima de 2500 m en orientaciones que van de E hacia S y en umbrías resguardadas N, NE y NW entre 2200-2400 m. Las placas tendrán capacidad de colgarnos, en el extremo norte del sector por las acumulaciones.

Distribución del manto nivoso

Hay nieve en el suelo a 1.600 m en N, ya 1.800-1.900 m en S. El manto es esquiable por encima de unos 1.800-1.900 m en umbrías. Los espesores alcanzan los 115-155 cm en cotas medias, variable según los efectos del viento.

Tendencia para las próximas 48-72h

Posible formación de capas débiles persistentes en umbrías donde se conserve nieve acumulada de la última nevada. Peligro: SIN CAMBIOS

El próximo boletín será emitido el día 2026-03-17

5 MUY FUERTE	4 FUERTE	3 NOTABLE	2 LIMITADO	1 DÉBIL

EAWS EUROPEAN AVALANCHE WARNING SERVICES

ICGC Institut Cartogràfic i Geològic de Catalunya

Servei Meteorològic de Catalunya

Boletín de peligro de aludes Perafita-Puigpedrós Del 16/03/2026 al 17/03/2026

(Válido fuera pistas de esquí y zonas no controladas)

Limitado (2)

Situación primaria

Nieve húmeda

Distribución

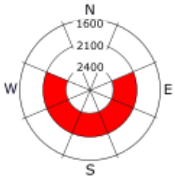

Tamaño

Origen

Tendencia

Situación secundaria

Nieve venteada

Distribución

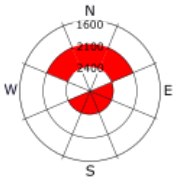

Tamaño

Origen

Tendencia

Estado del manto nivoso

El manto nivoso ha sido erosionado por el episodio de viento, especialmente de las cotas más altas de las umbrías donde aflora la costra marrón. El aumento térmico y la insolación propia de marzo transforman la nieve. Pueden caer aludes de fusión de forma natural por debajo de los 2500 m. No tendrán tamaño suficiente para enterrarnos, excepto en terreno trampa donde habrá que evitar pasar en las horas centrales del día y mientras la nieve no rehiele. Las orientaciones más proclives son las que van de E hacia W. El terreno más afectado por aludes de fusión son las zonas de salida de puntos oscuros (rocas y árboles). Durante la noche y madrugada la nieve rehelará allí donde se haya transformado durante el día. Aún se mantienen placas de viento que pueden caer a nuestro paso bajo collados y cordales por encima de 2500 en orientaciones que van de E hacia S y aisladamente en umbrías resguardadas como N, NE y NW entre 2200-2400 m. Las placas de viento tendrán capacidad de enterrarnos.

Distribución del manto nivoso

En umbrías hay nieve por encima de 1.400-1.500 m, y en las solanas está presente por encima de 1.700 m. Los espesores, aunque irregulares, rondan los 85-105 cm en cotas medias. Son grosores por encima de los habituales para la época.

Tendencia para las próximas 48-72h

Posible formación de capas débiles persistentes en umbrías donde se conserve nieve acumulada de la última nevada. Peligro: SIN CAMBIOS

El próximo boletín será emitido el día 2026-03-17

5 MUY FUERTE	4 FUERTE	3 NOTABLE	2 LIMITADO	1 DÉBIL

EAWS EUROPEAN AVALANCHE WARNING SERVICES

ICGC Institut Cartogràfic i Geològic de Catalunya

Servei Meteorològic de Catalunya

Boletín de peligro de aludes Vessant Nord Cadí-Moixeró Del 16/03/2026 al 17/03/2026

(Válido fuera pistas de esquí y zonas no controladas)

LIMITADO (2) por encima de 2200 m, DÉBIL (1) por debajo

Situación primaria

Nieve húmeda

Distribución

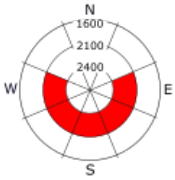

Tamaño

Origen

Tendencia

Situación secundaria

Nieve venteada

Distribución

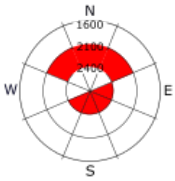

Tamaño

Origen

Tendencia

Estado del manto nivoso

El manto se erosionó por el episodio de viento, especialmente de las cotas más altas de umbrías donde aflora la costra marrón. El aumento térmico y la insolación de marzo transforman la nieve. Pueden caer aludes de fusión naturales por debajo de los 2500 m. No tendrán tamaño suficiente para enterrarnos, excepto en terreno trampa donde cabe evitar pasar a las horas centrales del día y mientras la nieve no rehiele. Las orientaciones más proclives son las que van de E hacia W. El terreno proclive a aludes de fusión son las zonas de salida de puntos oscuros (rocas y árboles). Durante la noche y madrugada la nieve rehelerá. Todavía se mantienen pequeñas placas de viento que pueden caer a nuestro paso en las umbrías y bajo collados y cordales por encima de 2500 m en orientaciones que van de E hacia S y aisladamente en N, NE y NW entre 2200-2400 m. Las placas de viento aunque no tendrán capacidad de enterrarnos pueden causarnos consecuencias en terreno trampa.

Distribución del manto nivoso

En umbrías hay nieve por encima de 1.400-1.500 m, y en las solanas está presente por encima de 1.500 m. El manto nivoso es esquiable por encima de unos 1.800 m. Los grosores están alrededor de 160-180 cm a 2.200 m. Estos valores son muy excedentarios para la época del año.

Tendencia para las próximas 48-72h

Posible formación de capas débiles persistentes en umbrías donde se conserve nieve acumulada de la última nevada. Peligro: SIN CAMBIOS

El próximo boletín será emitido el día 2026-03-17

5 MUY FUERTE	4 FUERTE	3 NOTABLE	2 LIMITADO	1 DÉBIL

EAWS EUROPEAN AVALANCHE WARNING SERVICES

ICGC Institut Cartogràfic i Geològic de Catalunya

Servei Meteorològic de Catalunya

Boletín de peligro de aludes Prepirineu
Del 16/03/2026 al 17/03/2026

(Válido fuera pistas de esquí y zonas no controladas)

LIMITADO (2) por encima de 2200 m, DÉBIL (1) por debajo

Situación primaria

Nieve húmeda

Distribución

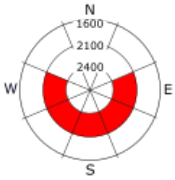

Tamaño

Origen

Tendencia

Situación secundaria

Nieve venteada

Distribución

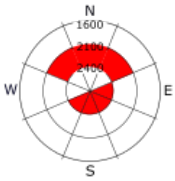

Tamaño

Origen

Tendencia

Estado del manto nivoso

El manto se erosionó por el episodio de viento, especialmente de las cotas más altas de umbrías donde aflora la costra marrón. El aumento térmico y la insolación de marzo transforman la nieve. Pueden caer aludes de fusión naturales por debajo de los 2500 m. No tendrán tamaño suficiente para enterrarnos, excepto en terreno trampa donde cabe evitar pasar a las horas centrales del día y mientras la nieve no rehiele. Las orientaciones más proclives son las que van de E hacia W. El terreno proclive a aludes de fusión son las zonas de salida de puntos oscuros (rocas y árboles). Durante la noche y madrugada la nieve rehelerá. Todavía se mantienen pequeñas placas de viento que pueden caer a nuestro paso en las umbrías y bajo collados y cordales por encima de 2500 m en orientaciones que van de E hacia S y aisladamente en N, NE y NW entre 2200-2400 m. Las placas de viento aunque no tendrán capacidad de enterrarnos pueden causarnos consecuencias en terreno trampa.

Distribución del manto nivoso

En umbrías hay nieve por encima de 1.600-1700 m. En solanas la nieve está presente por encima de 1.800-1.900 m. Los espesores, aunque irregulares, rondan los 65-85 cm en cotas medias.

Tendencia para las próximas 48-72h

Posible formación de capas débiles persistentes en umbrías donde se conserve nieve acumulada de la última nevada. Peligro: SIN CAMBIOS

El próximo boletín será emitido el día 2026-03-17

5 MUY FUERTE	4 FUERTE	3 NOTABLE	2 LIMITADO	1 DÉBIL

EAWS EUROPEAN AVALANCHE WARNING SERVICES

ICGC Institut Cartogràfic i Geològic de Catalunya

Servei Meteorològic de Catalunya

Boletín de peligro de aludes Ter-Freser Del 16/03/2026 al 17/03/2026

(Válido fuera pistas de esquí y zonas no controladas)

Limitado (2)

Situación primaria

Nieve húmeda

Distribución

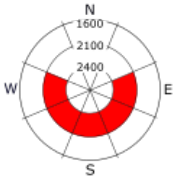

Tamaño

Origen

Tendencia

Situación secundaria

Nieve venteada

Distribución

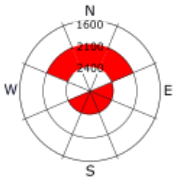

Tamaño

Origen

Tendencia

Estado del manto nivoso

El manto nivoso ha sido erosionado por el episodio de viento, especialmente de las cotas más altas de las umbrías donde aflora la costra marrón. El aumento térmico y la insolación propia de marzo transforman la nieve. Pueden caer aludes de fusión de forma natural por debajo de los 2500 m. No tendrán tamaño suficiente para enterrarnos, excepto en terreno trampa donde habrá que evitar pasar a las horas centrales del día y mientras la nieve no rehiele. Las orientaciones más proclives son las que van de E hacia W. El terreno más afectado por aludes de fusión son las zonas de salida de puntos oscuros como rocas y árboles. Durante la noche y madrugada la nieve rehelará allí donde se haya transformado durante el día. Aún se mantienen placas de viento que pueden caer a nuestro paso bajo collados y cordales por encima de 2500 m en orientaciones que van de E hacia S y aisladamente en umbrías resguardadas como N, NE y NW entre 2200-2400 m. Las placas de viento tendrán capacidad de enterrarnos.

Distribución del manto nivoso

Hay nieve en el suelo por encima de 1.600-1.700 m. Es esquiable a partir de unos 1700 m. El manto nivoso presenta grosores muy excedentarios para la época del año. En lugares no afectados por el viento los grosores oscilan entre 85-105 cm a unos 2.000 my más de 150 cm por encima de 2.400 m.

Tendencia para las próximas 48-72h

Posible formación de capas débiles persistentes en umbrías donde se conserve nieve acumulada de la última nevada. Peligro: SIN CAMBIOS

El próximo boletín será emitido el día 2026-03-17

5 MUY FUERTE	4 FUERTE	3 NOTABLE	2 LIMITADO	1 DÉBIL

EAWS EUROPEAN AVALANCHE WARNING SERVICES