BUTLLETÍ DEL PERILL D'ALLAUS DEL PRINCIPAT D'ANDORRA

Elaborado el 16/03/2026 16:00
Proxima actualización 17/03/2026 a las 16h

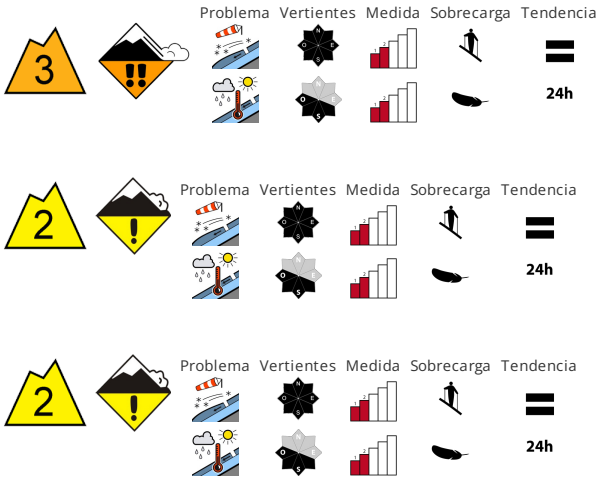

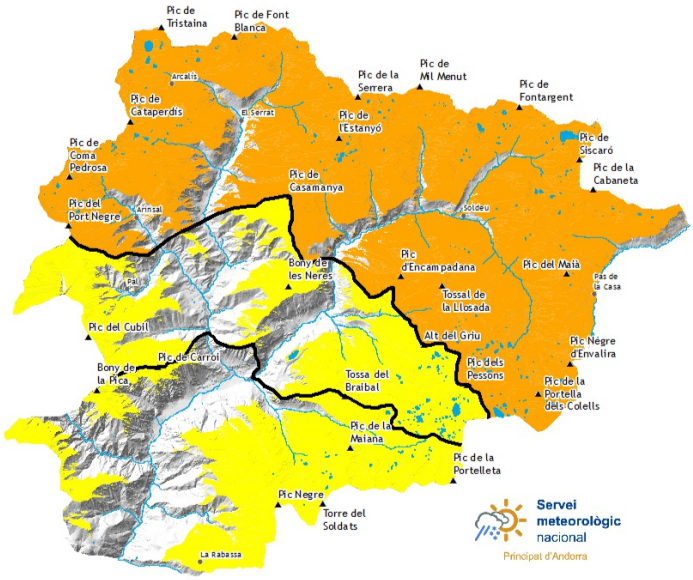

CALIDAD DE LA NIEVE

El viento con rachas muy fuertes ha transportado intensamente la nieve reciente y la nieve antigua. Las placas de viento representan la principal fuente de peligro. Sobre todo en las laderas orientadas a este, sur y oeste en la parte superior del manto de nieve hay capas débiles inestables. Las placas de viento pueden ser desencadenadas fácilmente y alcanzar un tamaño mediano. Los lugares peligrosos se encuentran en todas las orientaciones cerca del límite del bosque y en las transiciones de manto delgado a grueso. Con la subida de la temperatura diurna y la radiación solar, son posibles avalanchas de nieve húmeda de tamaño pequeño y mediano. Esto se da en las laderas solanas inclinadas , y en la base de las paredes rocosas.

ESTABILIDAD DEL MANTO NIVOSO

El domingo el viento ha soplado en muchos sectores muy fuerte. Las nuevas acumulaciones de nieve venteada se encuentran en todas las orientaciones. Cerca de los cordales los espesores de nieve varían mucho por la influencia del viento. Son engañosas las laderas con acumulaciones de nieve venteada. Se recomienda mantener la distancia de seguridad entre los miembros del grupo.

ESPESORES DEL MANTO NIVOSO FUERA DE PISTA

Zona norte		Espesor nieve		
Manto Nival		1500m	2000m	2500m
N	1600 m	0 cm	150 cm	200 cm
S	1900 m	0 cm	100 cm	150 cm

zona centro		Espesor nieve		
Manto Nival		1500m	2000m	2500m
N	1600 m	0 cm	150 cm	200 cm
S	1900 m	0 cm	100 cm	150 cm

Zona sur		Espesor nieve		
Manto Nival		1500m	2000m	2500m
N	1600 m	0 cm	120 cm	150 cm
S	1900 m	0 cm	60 cm	100 cm

Govern d'Andorra

EAWS EUROPEAN AVALANCHE WARNING SERVICES

Aquest butlletí ha estat elaborat seguint les normes i recomanacions de l'**European Avalanche Warning Services**, del qual el **Servei meteorològic Nacional** n'és membre

BUTLLETÍ DEL PERILL D'ALLAUS DEL PRINCIPAT D'ANDORRA

Servei meteorològic nacional
Principat d'Andorra

Información detallada por espacios naturales protegidos

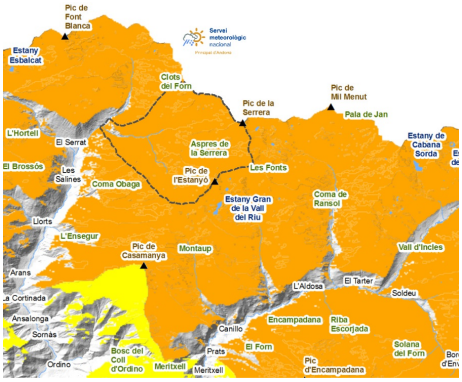

SORTENY

El ambiente invernal del fin de semana ha enterrado la nieve vieja, pero el viento le ha dejado al descubierto en cambios de rasante, crestas y vertientes orientadas a norte. A menudo, el viento se ha llevado la nieve nueva y también la vieja y ha dejado las trazas de relieve. El aumento de las temperaturas diurnas hace que la textura de la nieve sea muy diferente en pocos metros, puesto que la nieve nueva se humidifica más rápido y se desliza menos. Atención con las placas de viento de las vertientes este, sur y oeste, donde estos primeros días deberá circularse con más prudencia.

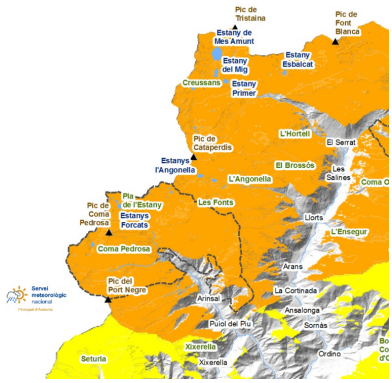

COMAPEDROSA

La nieve ha vuelto a llegar a todas las cotas del Parque, pero cerca del pueblo de Arinsal hay poco grosor que se está fundiendo rápidamente con el aumento de temperaturas diurno. En cotas altas, la nieve vieja está bien rehelada y se ha quedado al descubierto en los lugares vientos. La identificaremos por el cambio de color con la nieve nueva. Será más seguro y estable circular por la nieve vieja. La nieve nueva no ha sido suficiente para tapar las grietas de deslizamiento basal, que todavía representan un peligro de caída.

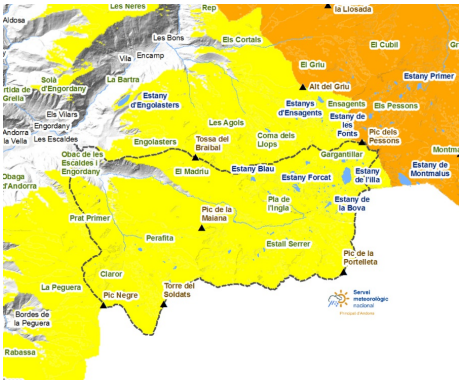

MADRIU-PERAFITA-CLAROR

Los accesos con esquís desde los Cortals d´Encamp, la Rabassa y Grau Roig siguen bien nevados, pero la nieve venteada en las vertientes este, sur y oeste nos debe hacer circular con precaución.

Govern d'Andorra

EAWS
EUROPEAN AVALANCHE WARNING SERVICES

Aquest butlletí ha estat elaborat seguint les normes i recomanacions de l'**European Avalanche Warning Services**, del qual el **Servei meteorològic Nacional** n'és membre

BUTLLETÍ DEL PERILL D'ALLAUS DEL PRINCIPAT D'ANDORRA

Servei meteorològic nacional
Principat d'Andorra

Espesores de nieve nueva de los últimos días (de las ultimas 24h mesurado a las 06:00h UTC)

	12/03/2026	13/03/2026	14/03/2026	15/03/2026
FEDA (Central)	0 cm	0 cm	0 cm	0 cm
Engolasters - FEDA	0 cm	0 cm	6 cm	0 cm
Bony de les Neres	0 cm	3 cm	14 cm	0 cm
Sorteny	0 cm	8 cm	25 cm	3 cm
Les Fonts d'Arinsal	0 cm	9 cm	26 cm	0 cm
Perafita	0 cm	0 cm	4 cm	34 cm
Tossa Espiolets	0 cm	5 cm	0 cm	0 cm
Grau Roig - FEDA	0 cm	4 cm	21 cm	0 cm
Fontverd	0 cm	0 cm	29 cm	0 cm
Ransol - FEDA	0 cm	0 cm	8 cm	0 cm
Caborreu	0 cm	5 cm	11 cm	0 cm
La Solana	0 cm	3 cm	29 cm	0 cm
Coll Pa	0 cm	4 cm	4 cm	0 cm
Envalira Antenes	0 cm	0 cm	37 cm	6 cm
Vall del Riu FEDA	0 cm	9 cm	14 cm	0 cm