BUTLLETÍ DEL PERILL D'ALLAUS DEL PRINCIPAT D'ANDORRA

Préparé le 16/03/2026 16:00
Prochaine mise à jour le 17/03/2026 à 16h

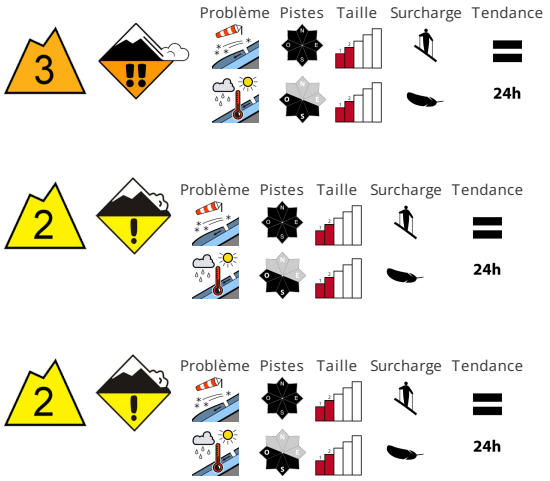

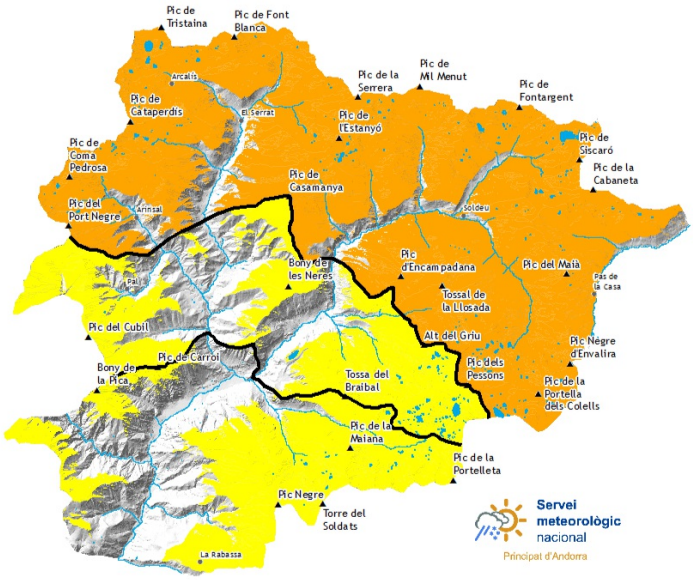

STABILITÉ DU MANTEAU NEIGEUX

Le vent parfois tempétueux a transporté intensivement la neige fraîche et la neige ancienne.. Les accumulations de neige soufflée constituent le danger principal. Dans la partie supérieure du manteau neigeux des couches fragiles susceptibles d'être déclenchées sont présentes ils se rencontrent , surtout sur les pentes exposées à l'est , au sud et à l'ouest. Les accumulations de neige soufflée peuvent peut être déchaîné facilement et atteindre une taille moyenne.. Les endroits dangereux se situent à toutes les expositions dans la zone de la limite de la forêt ainsi qu'aux transitions entre les endroits faiblement et fortement enneigés. Des avalanches petites et moyennes humides sont ils sont possibles avec le réchauffement diurne et le rayonnement solaire. Ceci sur les pentes raides ensoleillées comme au pied des parois rocheuses.

QUALITÈ DE LA NEIGE

Dimanche le vent à soufflé en général tempétueusement. Les accumulations récentes de neige soufflée se situent à toutes les expositions. À proximité des crêtes on trouve suivant l'influence du vent des hauteurs de neiges très différentes. Ce sont les pentes où la neige soufflée s'est accumulée qui sont traîtres. Des distances de délestage sont recommandées..

EPAISSEUR DE NEIGE HORS PISTE

Zone nord		Epaisseur de neige		
Nival manteau		1500m	2000m	2500m
N	1600 m	0 cm	150 cm	200 cm
S	1900 m	0 cm	100 cm	150 cm

Zone centre		Epaisseur de neige		
Nival manteau		1500m	2000m	2500m
N	1600 m	0 cm	150 cm	200 cm
S	1900 m	0 cm	100 cm	150 cm

Zone sud		Epaisseur de neige		
Nival manteau		1500m	2000m	2500m
N	1600 m	0 cm	120 cm	150 cm
S	1900 m	0 cm	60 cm	100 cm

Govern d'Andorra

EAWS EUROPEAN AVALANCHE WARNING SERVICES

Aquest butlletí ha estat elaborat seguint les normes i recomanacions de l'**European Avalanche Warning Services**, del qual el **Servei meteorològic Nacional** n'és membre

BUTLLETÍ DEL PERILL D'ALLAUS DEL PRINCIPAT D'ANDORRA

Servei meteorològic nacional
Principat d'Andorra

Des informations détaillées par espace naturel protégé

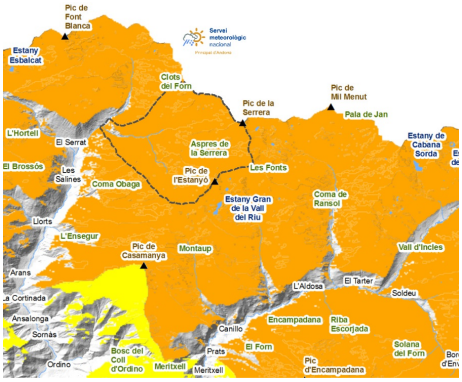

SORTENY

L'atmosphère hivernale du week-end a enfoui la vieille neige, mais le vent l'a laissée exposée dans les changements de pente, les crêtes et les pentes exposées au nord. Souvent, le vent a emporté la neige nouvelle comme l'ancienne et a laissé des traces en relief. L'augmentation des températures diurnes rend la texture de la neige très différente en quelques mètres seulement, car la nouvelle neige s'humidifie plus rapidement et glisse moins. Attention aux plaques de vent sur les versants est, sud et ouest, où ces premiers jours il faudra conduire plus prudemment. , , , , , , ,

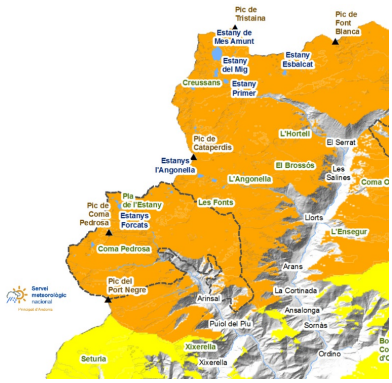

COMAPEDROSA

La neige est revenue à tous les niveaux du Parc, mais près de la ville d'Arinsal il y a une petite épaisseur qui fond rapidement avec l'augmentation des températures diurnes. À haute altitude, la vieille neige est bien gelée et a été exposée dans les zones venteuses. Nous l'identifierons par le changement de couleur avec la nouvelle neige. Il sera plus sûr et plus stable de rouler sur la vieille neige. La neige fraîche n'a pas suffi à couvrir les fissures de glissement basales, qui représentent toujours un risque de chute. , , , , , , , , ,

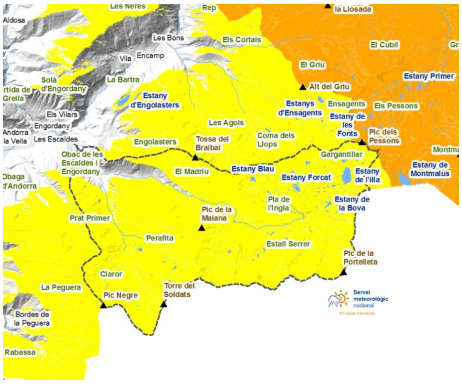

MADRIU-PERAFITA-CLAROR

Les accès à ski depuis les Cortals d´Encamp, la Rabassa et Grau Roig sont encore bien enneigés, mais la poudrerie sur les versants est, sud et ouest doit nous inciter à conduire avec prudence. ,

Govern d'Andorra

EAWS
EUROPEAN AVALANCHE WARNING SERVICES

Aquest butlletí ha estat elaborat seguint les normes i recomanacions de l'**European Avalanche Warning Services**, del qual el **Servei meteorològic Nacional** n'és membre

BUTLLETÍ DEL PERILL D'ALLAUS DEL PRINCIPAT D'ANDORRA

Servei meteorològic nacional
Principat d'Andorra

Couche de neige fraiche des derniers jours (De 24 h mesurée à 06:00 h UTC)

	12/03/2026	13/03/2026	14/03/2026	15/03/2026
FEDA (Central)	0 cm	0 cm	0 cm	0 cm
Engolasters - FEDA	0 cm	0 cm	6 cm	0 cm
Bony de les Neres	0 cm	3 cm	14 cm	0 cm
Sorteny	0 cm	8 cm	25 cm	3 cm
Les Fonts d'Arinsal	0 cm	9 cm	26 cm	0 cm
Perafita	0 cm	0 cm	4 cm	34 cm
Tossa Espiolets	0 cm	5 cm	0 cm	0 cm
Grau Roig - FEDA	0 cm	4 cm	21 cm	0 cm
Fontverd	0 cm	0 cm	29 cm	0 cm
Ransol - FEDA	0 cm	0 cm	8 cm	0 cm
Caborreu	0 cm	5 cm	11 cm	0 cm
La Solana	0 cm	3 cm	29 cm	0 cm
Coll Pa	0 cm	4 cm	4 cm	0 cm
Envalira Antenes	0 cm	0 cm	37 cm	6 cm
Vall del Riu FEDA	0 cm	9 cm	14 cm	0 cm