MINISTERO DELLA DIFESA

meteomont
Servizio Nazionale di previsione neve e valanghe

EAWS EUROPEAN AVALANCHE WARNING SERVICES

CARABINIERI

# MAJELLA

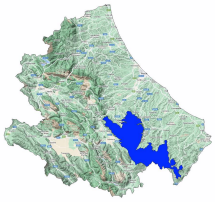

Bollettino Valanghe N. 363/2026 del 16/03/2026 ore 14.00
Validità 48 ore prossima emissione 17/03/2026

**A cura del Servizio METEOMONT dell'ARMA dei CARABINIERI**
**In collaborazione con Servizio Meteorologico dell'Aeronautica militare**

## SITUAZIONE alle 14:00 del 16/03/2026

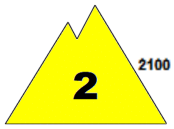


**SITUAZIONE TIPO: neve a debole coesione e vento.**

**SITUAZIONE TIPO: situazione primaverile.**

| Quota neve (mslm) | Nord | Sud |
|---|---|---|
| | 1600 | 1800 |

| Altezza Neve (cm) | Neve al suolo | Neve Fresca | Quota (mslm) |
|---|---|---|---|
| | 007 | 002 | 1650 |
| | 000 | 000 | 1270 |

**VALANGHE OSSERVATE: Nessuna valanga.**

## PREVISIONI 17/03/2026

## GRADO DI PERICOLO: MODERATO 2

## SITUAZIONE TIPO: neve a debole coesione e vento.

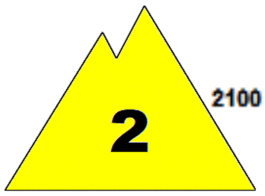


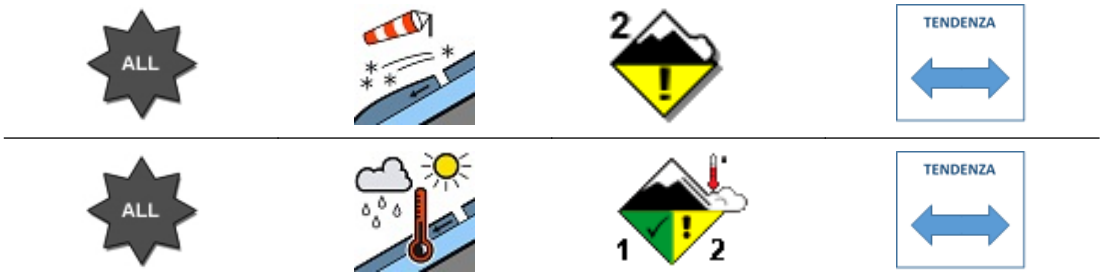


## SITUAZIONE TIPO: situazione primaverile.

**MANTO NEVOSO: La stabilità del manto nevoso è scarsa su alcuni punti (aree) per tutte le esposizioni al di sopra di 2100 mslm, possibili valanghe di dimensioni medie.**
**La stabilità del manto nevoso è scarsa su alcuni punti (aree) per tutte le esposizioni al di sotto di 2100 mslm, possibili valanghe di dimensioni medie.**

## AVVERTENZE

A seguito dell'attività eolica registrata sono da evitare le zone di accumulo, conche, canaloni, cambi di pendenza e pendii sotto vento in genere.

## SCALA EUROPEA DEL GRADO DI PERICOLO VALANGHE

## LEGENDA PROBLEMA

**Bollettino realizzato su scala sinottica-regionale (standard EAWS). La sua valutazione non può escludere in alcun modo la necessità di una seria e capace valutazione locale del pericolo (singolo pendio) che può essere anche sensibilmente diverso. Le previsioni meteorologiche sono relative all'orario UTC (per l'Italia +1 in inverno e +2 in estate).**

MINISTERO DELLA DIFESA

meteomont
Servizio Nazionale di previsione neve e valanghe

EAWS EUROPEAN AVALANCHE WARNING SERVICES

CARABINIERI

# MAJELLA

## PREVISIONE METEO

| Quota | | 17/03/2026 h6:00 | 17/03/2026 h12:00 | 17/03/2026 h18:00 |
|---|---|---|---|---|
| 1000 | Venti | 02 Nodi da Nord | 03 Nodi da Nord | 04 Nodi da Nord |
| | Temperature | +00 °C | +00 °C | -04 °C |
| | Temp.percepita | 0 °C | -2 °C | -7 °C |
| 2000 | Venti | 04 Nodi da Nord | 05 Nodi da Nord | 09 Nodi da Nord |
| | Temperature | -02 °C | -02 °C | -06 °C |
| | Temp.percepita | -5 °C | -5 °C | -12 °C |
| 3000 | Venti | 05 Nodi da N-Est | 07 nodi da N-Ovest | 11 Nodi da Nord |
| | Temperature | -08 °C | -09 °C | -13 °C |
| | Temp.percepita | -13 °C | -15 °C | -22 °C |
| Zero termico | | 1500-1700 m. | 1600-1800 m. | 1100-1300 m. |
| Fenomeno | | — | | — |
| Stato del cielo | | | | |

## LEGENDA FENOMENI

— Assenza Fenomeni · Nebbia · Foschia · Pioggia debole · Pioggia moderata · Pioggia forte · Temporali

Nevicata debole · Nevicata moderata · Nevicata forte

## STATO DEL CIELO

Sereno · Poco nuvoloso · Nuvoloso · Molto nuvoloso · Coperto

## Parametri meteonivometrici registrati presso i campi di rilevamento il 16/03/2026.

| Località | Comune | Quota (m.s.l.m.) | Altezza neve (cm) | Neve caduta nelle 24 ore (cm) | Temp. Min (°C) | Temp. Max (°C) | Condizioni del tempo |
|---|---|---|---|---|---|---|---|
| QUARTARANA | Campo di Giove (AQ) | 1200 | 0 | 0 | +1 | +7 | Pioggia forte |
| PASSOLANCIANO | Lettomanoppello (PE) | 1300 | 0 | 0 | +2 | +7 | Pioggia mista a neve |
| VALICO DELLA FORCHETTA | Palena (CH) | 1270 | 0 | 0 | +2 | +7 | Nebbia con cielo non visibile |
| VALLE DEL SOLE | Pizzoferrato (CH) | 1440 | 0 | 0 | N.P. | N.P. | Pioggia moderata |
| MAIELETTA MAMMA ROSA | Pretoro (CH) | 1650 | 7 | 2 | -1 | +4 | Pioggia mista a neve |
| PASSO SAN LEONARDO | Sant'Eufemia a Maiella (PE) | 1145 | 0 | 0 | +0 | +12 | Pioggia debole continua |

**(*) Rilievi fuori campo**

**L'INFORMAZIONE E' PREVENZIONE - LEGGI L'ATTUALE GRADO DI PERICOLO VALANGHE!**

**IL CAPO DEL CENTRO NAZIONALE METEOMONT**
**(Ten. Col. RFI Emanuela Gini)**
**FIRMA AUTOGRAFA OMESSA AI SENSI**
**DELL'ART.3 DEL D.LGS N.39/1993**

**Bollettino realizzato su scala sinottica-regionale (standard EAWS). La sua valutazione non può escludere in alcun modo la necessità di una seria e capace valutazione locale del pericolo (singolo pendio) che può essere anche sensibilmente diverso. Le previsioni meteorologiche sono relative all'orario UTC (per l'Italia +1 in inverno e +2 in estate).**